Bulletin d'estimation du risque d'avalanche
(valable en dehors des pistes balisées et ouvertes)

MASSIF : Aure Louron

Rédigé le dimanche 8 février 2026 à 17h

Estimation des risques pour le : LUNDI 09 FÉVRIER

NEIGE VENTÉE, RARES COUCHES FRAGILES PERSISTANTES ENFOUIES

2

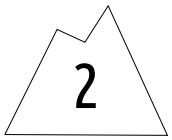

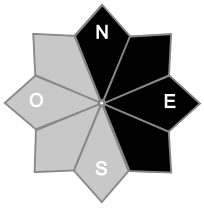

Encore des plaques

Indices de risque : 5 très fort - 4 fort - 3 marqué - 2 limité - 1 faible -- En noir : les pentes les plus dangereuses

Indice de risque limité.

Départs spontanés : Rares, petits départs ponctuels ou éventuellement linéaires

Déclenchements provoqués : Plaques au-dessus de 2000m en nord à est, couches fragilles enfouies en secteurs froids.

Stabilité du manteau neigeux

Situation avalancheuse typique : neige ventée couche fragile persistante

Déclenchements provoqués : Plaques en place parfois loin des crêtes, cols et sommets dans les secteurs déventés Nord à Est, formées par les épisodes successifs de vent de sud-ouest puis, devenant moins facilement déclenchables avec le tassement. Leur déclenchement reste un peu plus facile au-dessus de 2000m et surtout à proximité de la frontière, où les conditions sont restées hivernales ces derniers jours, limitant la stabilisation.
Les chutes de neige attendues lundi ne devraient pas créer de nouvelles plaques, faute de cumuls suffisants.
Dans les secteurs froids bien ombragés au-dessus de 2000m, des couches fragiles sont en place dans certains secteurs. Elles sont difficilement déclenchables car enfouies assez profondément, mais leur sollicitation, parfois possible là où l'épaisseur de neige est moins importante (abords des combes, ruptures de pente), peut engendrer des avalanches avec des cassures de plus de 50cm. Elles sont probablement plutôt présentes à l'avant de la chaîne où des épaisseurs moindres ont permis leur formation.

Départs spontanés :
Quelques départs spontanés en neige humide sont attendus en toutes expositions, sous l'effet des pluies avec la remontée de la limite pluie-neige atteignant 2000m l'après-midi. D'abord petites mobilisant la neige récente tombée ces derniers jours, elles peuvent atteindre une taille moyenne en mobilisant des couches plus anciennes. Elles atteignent rarement une grande taille avant lundi soir car le manteau a déjà été humidifié à ces altitudes et les cumuls de pluie restent limités. Le risque est en hausse la nuit suivante.

Autres :
Corniches souvent imposantes au-dessus des pentes est

Qualité de la neige

Enneigement : bon pour la saison, mais les crêtes, cols et sommets en expositions ouest sont souvent pelés par le vent dans les expositions ouest. Accumulations plus importantes en secteurs frontaliers.
Limites skiables : manteau neigeux skiable à partir de 1300-1400m en nord.
État de la neige : quelques centimètres de neige fraîche reposant sur un manteau bien regelé sous 2000m, sur de la neige sèche plus haut. En journée, le manteau s'humidifie nettement sous 2000m.

Aperçu météo pour le lundi 09 février

	nuit	matin	après-midi	soir
	Temps humide, remontée progressive de la limite pluie-neige, renforcement des pluies la nuit suivante			
Pluie-Neige		1 600 m	1 800 m	2 000 m
Iso 0 °C	1 500 m	1 900 m	2 100 m	2 400 m
Vent 1500 m	→ 15 km/h	↑ 15 km/h	↓ 15 km/h	↗ 20 km/h
Vent 3000 m	↘ 45 km/h	↘ 50 km/h	↘ 55 km/h	↘ 80 km/h

Épaisseur de neige hors-piste

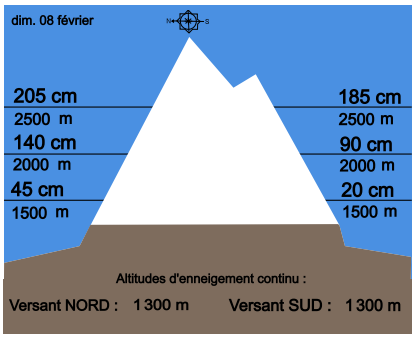

Précipitations à 1800 m

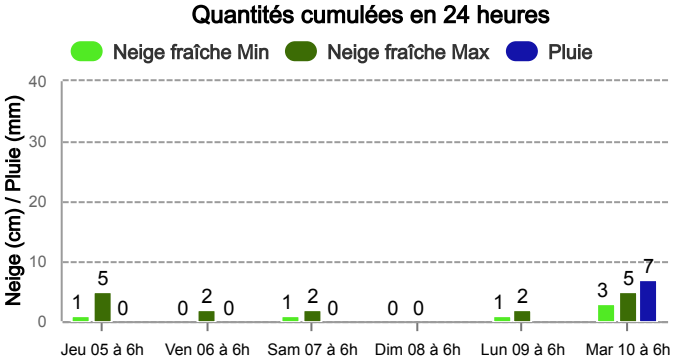

Tendance du mardi 10 février

3

Indice de risque marqué

Risque en hausse avec l'humidification d'un manteau hivernal.

Pour consulter la vigilance en cours, veuillez vous rendre sur le site https://vigilance.meteofrance.fr/fr

Météo-France - 73 avenue de Paris, 94165 Saint-Mandé cedex - Contact : contact@meteo.fr

Rédigé par Météo-France avec la contribution des observateurs du réseau nivo-météorologiques. Partenariat : ANMSM (Maires de Stations de Montagne), DSF (Domaines Skiables de France), ADSP (Directeurs de Pistes et de la Sécurité des Stations de Sports d'Hiver) et autres acteurs de la montagne.

Bulletin neige & avalanches par téléphone au
0 892 68 10 20 Service 0,35 € / min + prix appel

RÉPUBLIQUE FRANÇAISE
Liberté Égalité Fraternité

METEO FRANCE
À VOS CÔTÉS, DANS UN CLIMAT QUI CHANGE

Bulletin d'estimation du risque d'avalanche

(valable en dehors des pistes balisées et ouvertes)

MASSIF : Aure Louron

Rédigé le dimanche 8 février 2026 à 17h

Conditions nivo-météo des 7 derniers jours

	lun. 02/02				mar. 03/02				mer. 04/02				jeu. 05/02				ven. 06/02				sam. 07/02				dim. 08/02			
	03h	09h	15h	21h	03h	09h	15h	21h	03h	09h	15h	21h	03h	09h	15h	21h	03h	09h	15h	21h	03h	09h	15h	21h	03h	09h	15h	21h
Météo																												
Vent (km/h)	70	125	120	80	65	45	45	90	95	100	60	55	75	110	95	70	60	60	60	50	40	35	35	45	50	35	50	40
à 3000m																												
Vent (km/h)	50	85	85	45	25	30	30	50	60	40	30	30	45	70	65	40	30	35	25	25	20	10	15	25	30	10	20	15
à 1500m																												

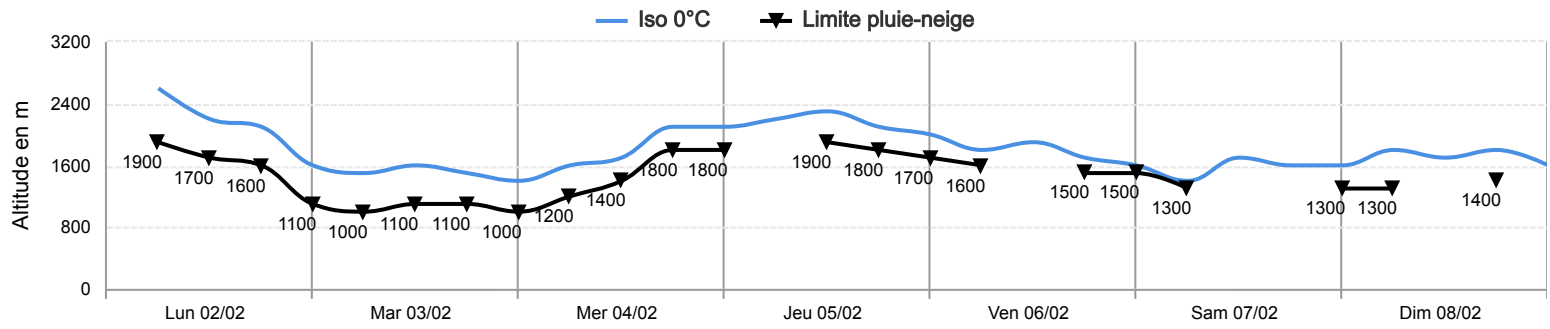

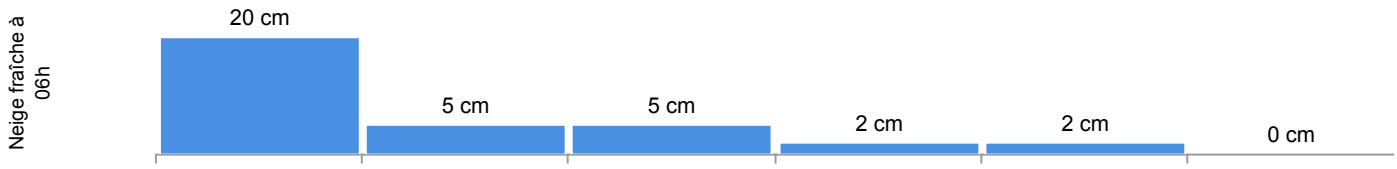

Risque d'avalanche	lun. 02/02	mar. 03/02	mer. 04/02	jeu. 05/02	ven. 06/02	sam. 07/02	dim. 08/02
	3	3	3	3	3	2	2

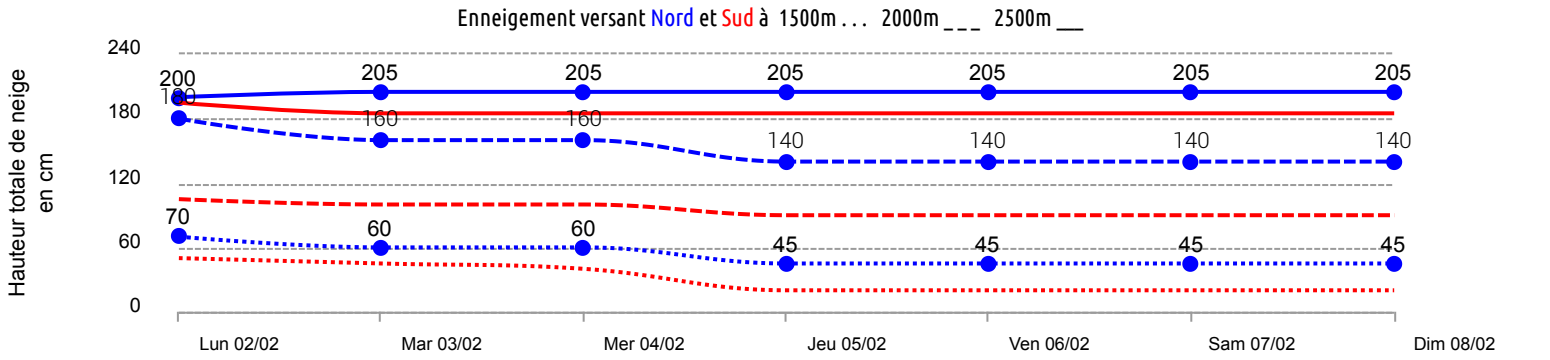

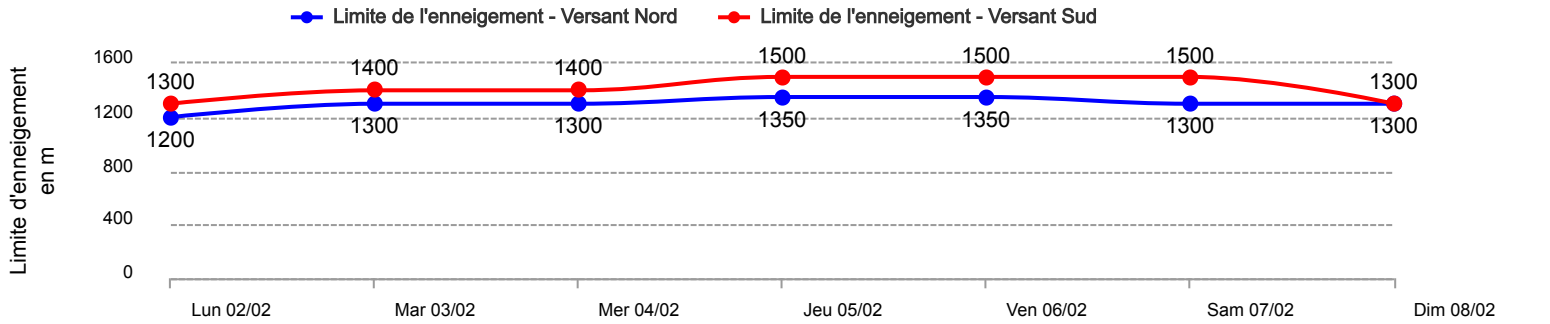

Pour consulter la vigilance en cours, veuillez vous rendre sur le site https://vigilance.meteofrance.fr/fr

Météo-France - 73 avenue de Paris, 94165 Saint-Mandé cedex - Contact : contact@meteo.fr

Bulletin neige & avalanches par téléphone au

0 892 68 10 20 Service 0,35 € / min + prix appel

Rédigé par Météo-France avec la contribution des observateurs du réseau nivo-météorologiques. Partenariat : ANMSM (Maires de Stations de Montagne), DSF (Domaines Skiables de France), ADSP (Directeurs de Pistes et de la Sécurité des Stations de Sports d'Hiver) et autres acteurs de la montagne.