# Bulletin d'estimation du risque d'avalanche

(valable en dehors des pistes balisées et ouvertes)

# MASSIF : Capcir Puymorens

Rédigé le dimanche 8 février 2026 à 17h

## Estimation des risques pour le : LUNDI 09 FÉVRIER

**PERSISTANCE DE QUELQUES INSTABILITÉS**

2

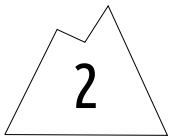


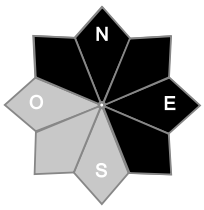


Indice de risque limité.

**Départs spontanés :** Avalanches en neige humide au soleil puis avec la pluie

**Déclenchements provoqués :** Vieilles plaques à vent juste sous les cols frontaliers mais aussi quelques plaques à vent en formation

Indices de risque : 5 très fort - 4 fort - 3 marqué - 2 limité - 1 faible -- En noir : les pentes les plus dangereuses

## Stabilité du manteau neigeux

**Situation avalancheuse typique :**

neige ventée

couche fragile persistante

**Déclenchements provoqués :**

* Au-dessus de 2000/2100 m, dans les orientations nord-ouest à est, déclenchements possibles au passage d'un randonneur d'avalanches de taille moyenne (T2), voire de grande taille (T3) dans les secteurs les plus défavorables de haute montagne côté Puymorens en particulier. En effet, des structures de plaques pas complètement stabilisées peuvent encore être présentes, principalement sous les crêtes et cols du fond de chaîne chargés par le vent de sud à sud-ouest.
* Au-dessus de 2200 m de nouvelles plaques se forment dans un secteur est à sud-est en raison du fort vent de nord-ouest, elles sont peu épaisses mais facilement déclenchables par un skieur.

**Départs spontanés :**

* Avalanches de glissement possibles en pentes très raides herbeuses ou sur des dalles rocheuses, surtout au soleil et en dessous de 2000 m (Taille 1 ou 2). (observables : présence de gueules de baleine, reptations, neige dense et très humide).
* Départs ponctuels en surface ( tailles 1 voire 2) en neige humide au soleil puis avec l'arrivée de la douceur et d'un peu de pluie l'après-midi : ces départs concernent alors toutes les expositions.

## Qualité de la neige

**Enneigement :**

L'enneigement est excellent et nettement excédentaire pour la saison. Skiabillité toujours présente dès les premiers plateaux.

**État de la neige :**

Au petit matin on trouvera un peu de neige fraîche qui s'humidifie en journée avec la remontée de l'isotherme 0 °C et les nuages puis les pluies associées.

## Aperçu météo pour le lundi 09 février

| | nuit | matin | après-midi | soir |
|---|---|---|---|---|
| | | | | |

Les nuages s'épaissent l'après-midi pour finir par donner un peu de pluie avec une limite pluie-neige en hausse progressive

| | | | | |
|---|---|---|---|---|
| **Pluie-Neige** | | | 1 800 m | 1 800 m |
| **Iso 0 °C** | 1 700 m | 1 900 m | 2 100 m | 2 200 m |
| **Vent 2000 m** | ↘ 35 km/h | ↗ 20 km/h | ↘ 30 km/h | ↗ 20 km/h |
| **Vent 3000 m** | ↘ 55 km/h | → 40 km/h | ↘ 60 km/h | → 40 km/h |

## Épaisseur de neige hors-piste

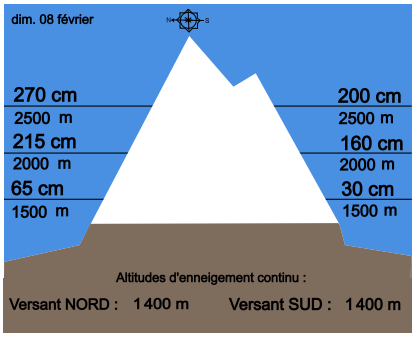


## Précipitations à 1800 m

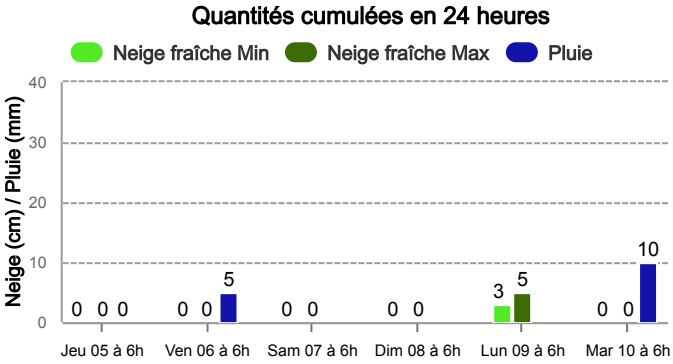


## Tendance du mardi 10 février

3

**Indice de risque marqué**

Risque de départ spontané en nette hausse du fait de l'arrivée de pluies significatives qui devraient faire réagir la neige récente mais aussi les couches fragiles plus anciennes enfouies dans le manteau neigeux.

Pour consulter la vigilance en cours, veuillez vous rendre sur le site https://vigilance.meteofrance.fr/fr

Météo-France - 73 avenue de Paris, 94165 Saint-Mandé cedex - Contact : contact@meteo.fr

Rédigé par Météo-France avec la contribution des observateurs du réseau nivo-météorologiques. Partenariat : ANMSM (Maires de Stations de Montagne), DSF (Domaines Skiables de France), ADSP (Directeurs de Pistes et de la Sécurité des Stations de Sports d'Hiver) et autres acteurs de la montagne.

Bulletin neige & avalanches par téléphone au

**0 892 68 10 20** Service 0,35 € / min + prix appel

RÉPUBLIQUE FRANÇAISE
*Liberté Égalité Fraternité*

METEO FRANCE
À VOS CÔTÉS, DANS UN CLIMAT QUI CHANGE

# Bulletin d'estimation du risque d'avalanche

(valable en dehors des pistes balisées et ouvertes)

# MASSIF : Capcir Puymorens

Rédigé le dimanche 8 février 2026 à 17h

## Conditions nivo-météo des 7 derniers jours

| | lun. 02/02 | | | | mar. 03/02 | | | | mer. 04/02 | | | | jeu. 05/02 | | | | ven. 06/02 | | | | sam. 07/02 | | | | dim. 08/02 | | | |
|---|---|---|---|---|---|---|---|---|---|---|---|---|---|---|---|---|---|---|---|---|---|---|---|---|---|---|---|---|
| | 03h | 09h | 15h | 21h | 03h | 09h | 15h | 21h | 03h | 09h | 15h | 21h | 03h | 09h | 15h | 21h | 03h | 09h | 15h | 21h | 03h | 09h | 15h | 21h | 03h | 09h | 15h | 21h |
| Météo | | | | | | | | | | | | | | | | | | | | | | | | | | | | |
| Vent (km/h) | 60 | 80 | 100 | 65 | 50 | 35 | 40 | 30 | 40 | 55 | 50 | 40 | 65 | 80 | 75 | 55 | 40 | 25 | 25 | 30 | 30 | 20 | 20 | 50 | 55 | 30 | 55 | 50 |
| à 3000m | | | | | | | | | | | | | | | | | | | | | | | | | | | | |
| Vent (km/h) | 20 | 50 | 75 | 45 | 35 | 25 | 30 | 25 | 30 | 45 | 35 | 30 | 45 | 60 | 55 | 40 | 25 | 15 | 15 | 20 | 20 | 15 | 15 | 40 | 45 | 20 | 35 | 35 |
| à 2000m | | | | | | | | | | | | | | | | | | | | | | | | | | | | |

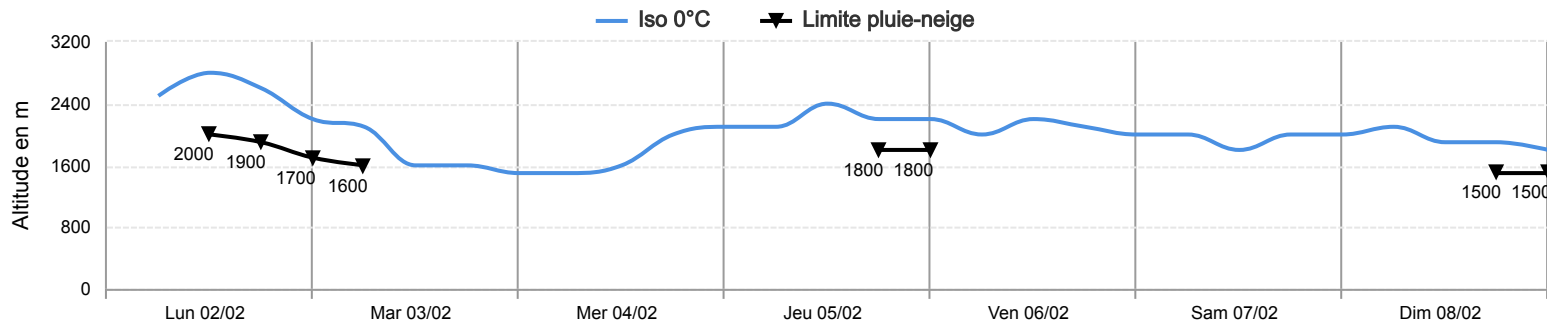


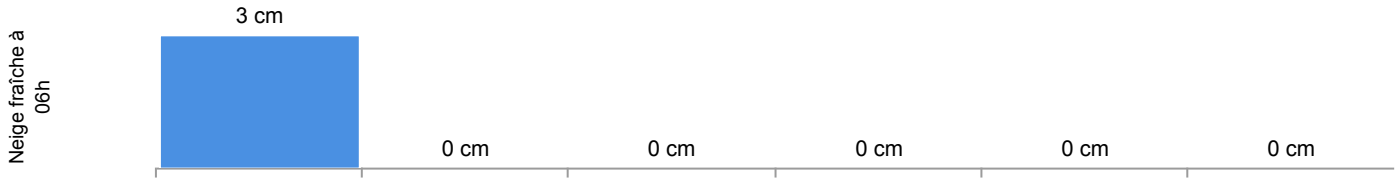


| Risque d'avalanche | lun. 02/02 | mar. 03/02 | mer. 04/02 | jeu. 05/02 | ven. 06/02 | sam. 07/02 | dim. 08/02 |
|---|---|---|---|---|---|---|---|
| | 3 | 3 | 3 | 3 | 2 | 2 | 2 |

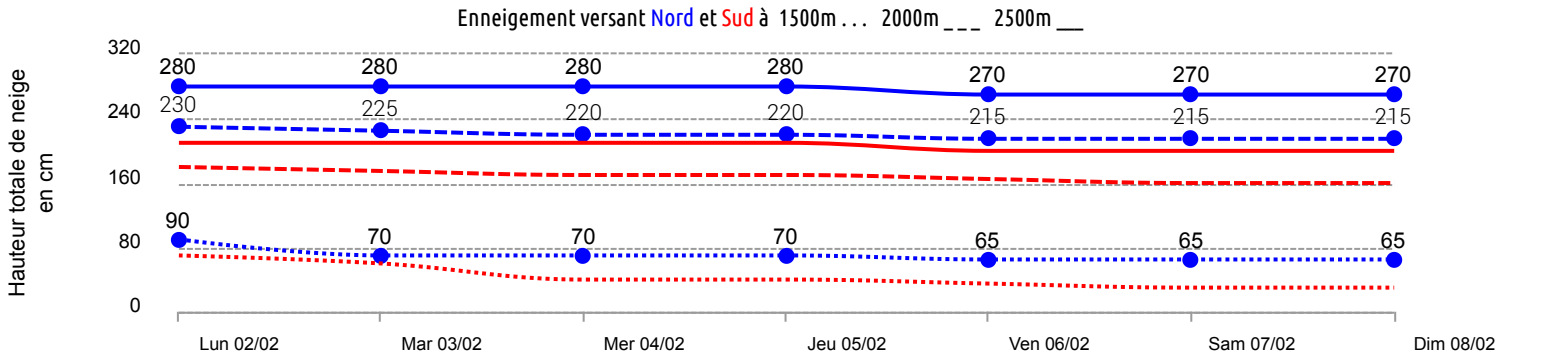


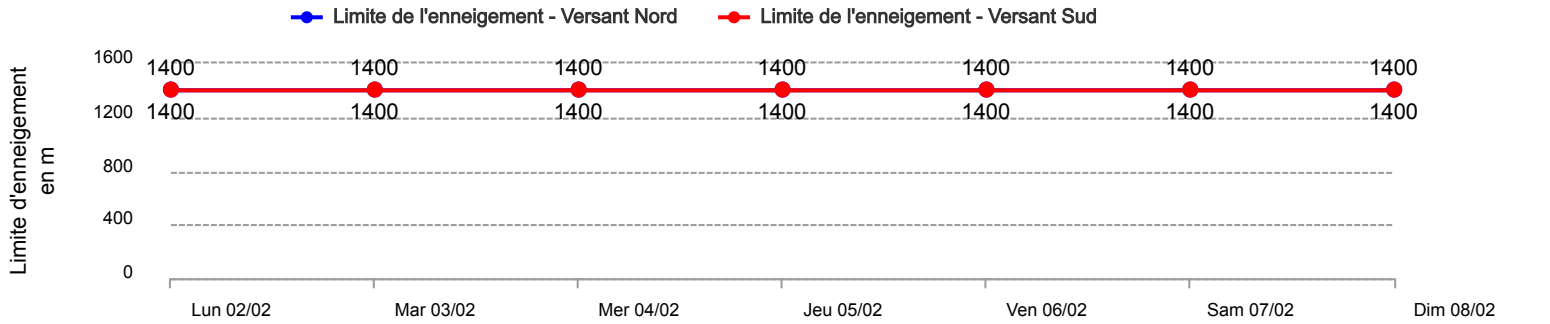


Pour consulter la vigilance en cours, veuillez vous rendre sur le site https://vigilance.meteofrance.fr/fr


Météo-France - 73 avenue de Paris, 94165 Saint-Mandé cedex - Contact : contact@meteo.fr


Bulletin neige & avalanches par téléphone au

0 892 68 10 20 Service 0,35 € / min + prix appel


Rédigé par Météo-France avec la contribution des observateurs du réseau nivo-météorologiques. Partenariat : ANMSM (Maires de Stations de Montagne), DSF (Domaines Skiables de France), ADSP (Directeurs de Pistes et de la Sécurité des Stations de Sports d'Hiver) et autres acteurs de la montagne.