Bulletin d'estimation du risque d'avalanche

(valable en dehors des pistes balisées et ouvertes)

MASSIF : Devoluy

Rédigé le dimanche 8 février 2026 à 17h

Estimation des risques pour le : LUNDI 09 FÉVRIER

QUELQUES INSTABILITÉS VOLUMINEUSES EN UBACS D'ALTITUDE, DIFFICILES À DÉCLENCHER

2

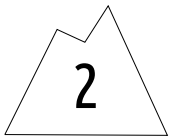

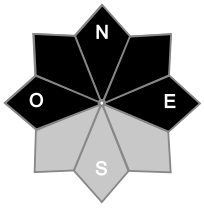

Indice de risque limité.

Départs spontanés : quelques départs superficiels en neige humide au soleil.

Déclenchements provoqués : Instabilités persistant en versants froids d'altitude, difficiles à déclencher

Indices de risque : 5 très fort - 4 fort - 3 marqué - 2 limité - 1 faible -- En noir : les pentes les plus dangereuses

Stabilité du manteau neigeux

Situation avalancheuse typique : couche fragile persistante — neige ventée

Déclenchements provoqués :

- quelques instabilités en place en versants est nord et ouest au-dessus de 1800/2000 m reposant sur des couches fragiles persistantes enfouies. Plaques généralement bien stabilisées et déclenchement difficile, mais encore possible localement sur les croupes et bords de couloirs où le manteau neigeux est moins épais. Elles engendrent des avalanches de taille moyennes à grande (taille 2 à 3), avec des cassures larges et épaisses.
- quelques plaques superficielles sont en places en toutes orientations dans la neige récente ventée, plutôt à proximité des crêtes. Elles génèrent des avalanches de petites taille en généralement, mais peuvent dans de rares cas déclencher en cascades les plaques plus volumineuses décrites précédemment.

Départs spontanés : quelques départs de neige récente humidifiée dans les pentes raides au soleil près des rochers. Départs ponctuels de taille petite à moyenne (taille 1 à 2).

Qualité de la neige

L'enneigement est excédentaire pour un début février.
Données observées : environ 100 cm vers 2000 m d'altitude.

Limite d'enneigement skiable : vers 1200/1300 m sur la plupart des itinéraires.

État de la neige de surface : 10/20 cm de neige récente en altitude,restée poudreuse et légère en versants froids au-dessus de 1700/1800 m, et parfois densifiée ou cartonnée par le vent près des crêtes. En versants ensoleillés, neige récente plus tassée et croutée sous 2400/2500 m.

Aperçu météo pour le lundi 09 février

Belles éclaircies le matin, passages nuageux l'après-midi, avec quelques flocons possibles en soirée.

	nuit	matin	après-midi	soir
Pluie-Neige				
Iso 0 °C	1 600 m	1 600 m	1 700 m	1 600 m
Vent 2000 m	5 km/h	15 km/h	15 km/h	15 km/h
Vent 3000 m	5 km/h	15 km/h	15 km/h	20 km/h

Épaisseur de neige hors-piste

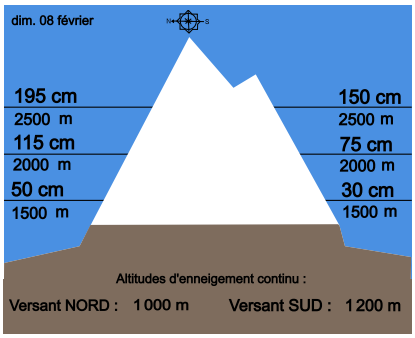

Précipitations à 1800 m

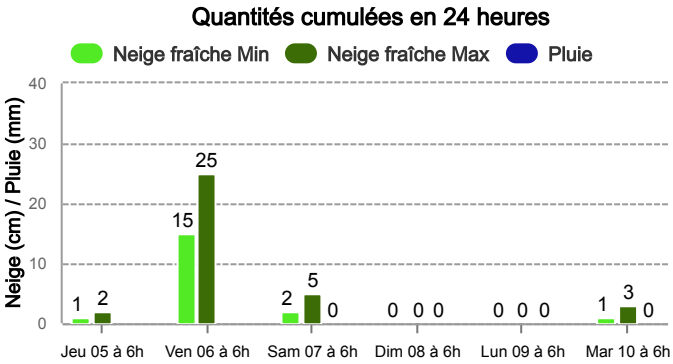

Tendance du mardi 10 février

3

Indice de risque marqué

Risque en hausse, devenant marqué avec les nouvelles chutes de neige.

Pour consulter la vigilance en cours, veuillez vous rendre sur le site https://vigilance.meteofrance.fr/fr

Météo-France - 73 avenue de Paris, 94165 Saint-Mandé cedex - Contact : contact@meteo.fr

Rédigé par Météo-France avec la contribution des observateurs du réseau nivo-météorologiques. Partenariat : ANMSM (Maires de Stations de Montagne), DSF (Domaines Skiables de France), ADSP (Directeurs de Pistes et de la Sécurité des Stations de Sports d'Hiver) et autres acteurs de la montagne.

Bulletin neige & avalanches par téléphone au 0 892 68 10 20 Service 0,35 € / min + prix appel

RÉPUBLIQUE FRANÇAISE
Liberté Égalité Fraternité

METEO FRANCE
À VOS CÔTÉS, DANS UN CLIMAT QUI CHANGE

Bulletin d'estimation du risque d'avalanche

(valable en dehors des pistes balisées et ouvertes)

MASSIF : Devoluy

Rédigé le dimanche 8 février 2026 à 17h

Conditions nivo-météo des 7 derniers jours

	lun. 02/02				mar. 03/02				mer. 04/02				jeu. 05/02				ven. 06/02				sam. 07/02				dim. 08/02			
	03h	09h	15h	21h	03h	09h	15h	21h	03h	09h	15h	21h	03h	09h	15h	21h	03h	09h	15h	21h	03h	09h	15h	21h	03h	09h	15h	21h
Météo																												
Vent (km/h)	35	50	70	100	120	60	50	40	40	40	30	15	30	15	60	40	40	45	35	20	15	10	10	5	10	25	25	10
à 3000m																												
Vent (km/h)	10	25	45	80	70	45	35	35	35	30	20	5	10	20	60	10	25	25	25	15	10	10	15	10	10	20	20	10
à 2000m																												

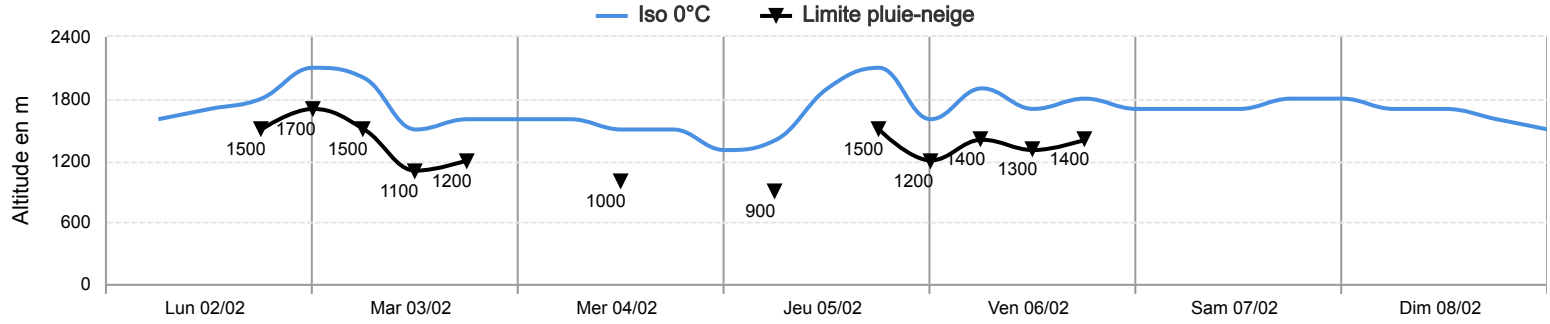

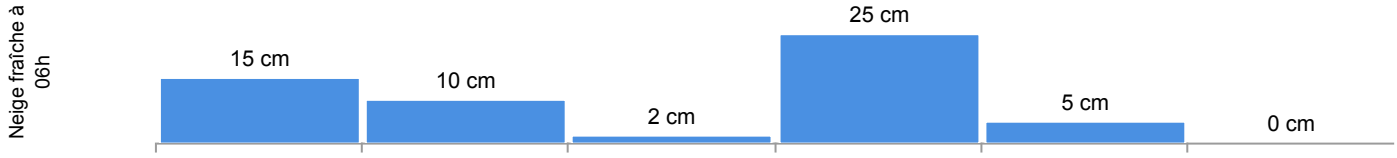

Risque d'avalanche	lun. 02/02	mar. 03/02	mer. 04/02	jeu. 05/02	ven. 06/02	sam. 07/02	dim. 08/02
	3	4	3	3	4	3	3

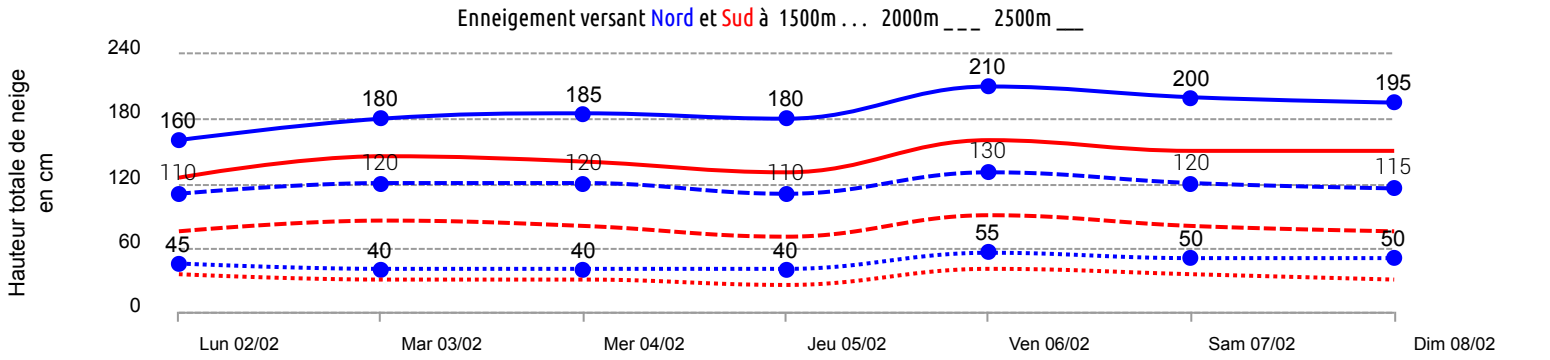

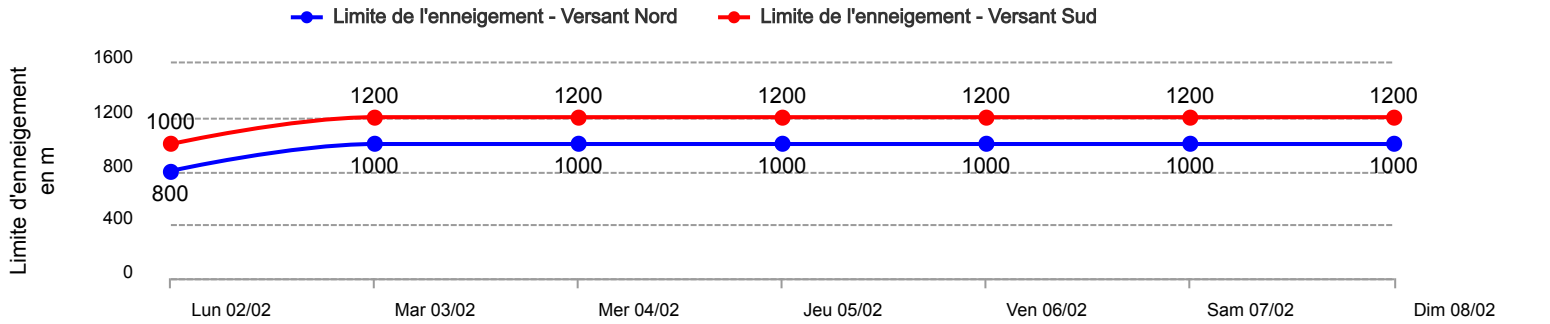

Pour consulter la vigilance en cours, veuillez vous rendre sur le site https://vigilance.meteofrance.fr/fr

Météo-France - 73 avenue de Paris, 94165 Saint-Mandé cedex - Contact : contact@meteo.fr

Bulletin neige & avalanches par téléphone au

0 892 68 10 20 Service 0,35 € / min + prix appel

Rédigé par Météo-France avec la contribution des observateurs du réseau nivo-météorologiques. Partenariat : ANMSM (Maires de Stations de Montagne), DSF (Domaines Skiables de France), ADSP (Directeurs de Pistes et de la Sécurité des Stations de Sports d'Hiver) et autres acteurs de la montagne.