RÉPUBLIQUE FRANÇAISE
*Liberté Égalité Fraternité*

METEO FRANCE
À VOS CÔTÉS, DANS UN CLIMAT QUI CHANGE

# Bulletin d'estimation du risque d'avalanche
## (valable en dehors des pistes balisées et ouvertes)
# MASSIF : Embrunais Parpaillon

Rédigé le dimanche 8 février 2026 à 17h

## Estimation des risques pour le : LUNDI 09 FÉVRIER

**INSTABILITÉS ENCORE FACILES À DÉCLENCHER EN UBACS D'ALTITUDE, SOUVENT VOLUMINEUSES**

3

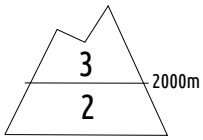


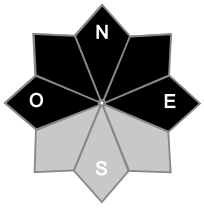


Au-dessus de 2000m indice de risque marqué, plus bas indice limité.

**Départs spontanés :** quelques départs superficiels en neige humide au soleil.

**Déclenchements provoqués :** Instabilités persistant en versants froids d'altitude, faciles à déclencher

Indices de risque : 5 très fort - 4 fort - 3 marqué - 2 limité - 1 faible -- En noir : les pentes les plus dangereuses

## Stabilité du manteau neigeux

**Situation avalancheuse typique :** couche fragile persistante neige ventée

**Déclenchements provoqués :**
- nombreuses instabilités en place en versants est nord et ouest au-dessus de 1800/2000 m reposant sur des couches fragiles persistantes enfouies. Plaques d'aspect poudreux, difficiles à identifier et déclenchables au passage d'un seul skieur, souvent à distance. Elles engendrent des avalanches de taille moyennes à grande (taille 2 à 3), avec des cassures larges et épaisses, notamment au-delà de 2300/2400 m.
- quelques plaques superficielles sont en places en toutes orientations dans la neige récente ventée, plutôt à proximité des crêtes. Elles génèrent des avalanches de petites taille en généralement, mais peuvent déclencher en cascades les plaques plus volumineuses décrites précédemment.

Sous 2000 m, ainsi qu'en adrets raides d'altitude, l'instabilité est plus limitée. La neige récente a pris une bonne cohésion, avec la récente humidification, et les couches fragiles persistantes sont moins généralisées.

**Départs spontanés :** quelques départs de neige récente humidifiée dans les pentes raides au soleil près des rochers. Départs ponctuels de taille petite à moyenne (taille 1 à 2).

## Qualité de la neige

**L'enneigement** est légèrement excédentaire pour un début février.
Données observées : 80 cm à la Nivôse du Parpaillon à 2550 m, secteur soufflé par le vent.

**Limite d'enneigement skiable** : dès 1200/1400 m sur la plupart des itinéraires, peu de sous-couche en adrets à cette altitude.

**État de la neige de surface** : 10/20 cm de neige récente, restée poudreuse et légère en versants froids au-dessus de 1700/1800 m, et parfois densifiée ou cartonnée par le vent près des crêtes. En versants ensoleillés, neige récente plus tassée et croutée sous 2400/2500 m.

## Aperçu météo pour le lundi 09 février

| nuit | matin | après-midi | soir |
|---|---|---|---|

Belles éclaircies le matin, passages nuageux l'après-midi, avec quelques flocons possibles en soirée.

| Pluie-Neige | | | | |
|---|---|---|---|---|
| Iso 0 °C | 1 600 m | 1 600 m | 1 800 m | 1 600 m |
| Vent 2000 m | ↙ 10 km/h | → 5 km/h | ↗ 15 km/h | ↑ 10 km/h |
| Vent 3000 m | ← 10 km/h | ↗ 15 km/h | ↗ 20 km/h | → 20 km/h |

## Épaisseur de neige hors-piste

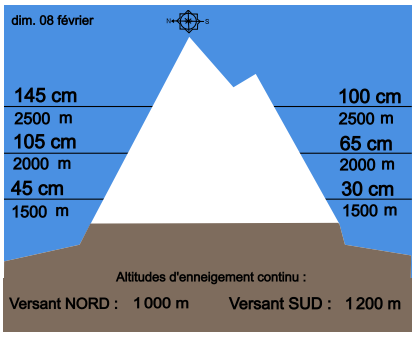


## Précipitations à 1800 m

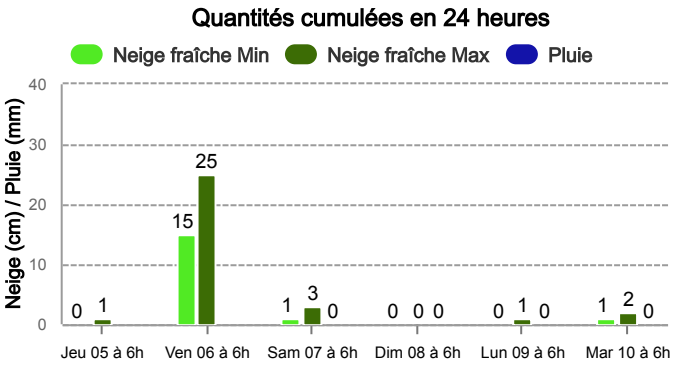


## Tendance du mardi 10 février

3 **Indice de risque marqué**

Risque en hausse mais restant marqué avec les nouvelles chutes de neige.

Pour consulter la vigilance en cours, veuillez vous rendre sur le site https://vigilance.meteofrance.fr/fr

Météo-France - 73 avenue de Paris, 94165 Saint-Mandé cedex - Contact : contact@meteo.fr

Rédigé par Météo-France avec la contribution des observateurs du réseau nivo-météorologiques. Partenariat : ANMSM (Maires de Stations de Montagne), DSF (Domaines Skiables de France), ADSP (Directeurs de Pistes et de la Sécurité des Stations de Sports d'Hiver) et autres acteurs de la montagne.

Bulletin neige & avalanches par téléphone au
**0 892 68 10 20** Service 0,35 € / min + prix appel

# Bulletin d'estimation du risque d'avalanche

(valable en dehors des pistes balisées et ouvertes)

# MASSIF : Embrunais Parpaillon

Rédigé le dimanche 8 février 2026 à 17h

## Conditions nivo-météo des 7 derniers jours

| | lun. 02/02 | | | | mar. 03/02 | | | | mer. 04/02 | | | | jeu. 05/02 | | | | ven. 06/02 | | | | sam. 07/02 | | | | dim. 08/02 | | | |
|---|---|---|---|---|---|---|---|---|---|---|---|---|---|---|---|---|---|---|---|---|---|---|---|---|---|---|---|---|
| | 03h | 09h | 15h | 21h | 03h | 09h | 15h | 21h | 03h | 09h | 15h | 21h | 03h | 09h | 15h | 21h | 03h | 09h | 15h | 21h | 03h | 09h | 15h | 21h | 03h | 09h | 15h | 21h |
| Météo | | | | | | | | | | | | | | | | | | | | | | | | | | | | |
| Vent (km/h) | 30 | 30 | 45 | 80 | 80 | 60 | 40 | 40 | 40 | 40 | 20 | 15 | 25 | 20 | 45 | 15 | 40 | 35 | 35 | 20 | 20 | 10 | 5 | 5 | 15 | 15 | 30 | 30 |
| à 3000m | | | | | | | | | | | | | | | | | | | | | | | | | | | | |
| Vent (km/h) | 10 | 10 | 15 | 40 | 40 | 30 | 20 | 15 | 15 | 20 | 15 | 10 | 10 | 10 | 20 | 15 | 15 | 15 | 20 | 10 | 10 | 5 | 10 | 10 | 10 | 10 | 20 | 20 |
| à 2000m | | | | | | | | | | | | | | | | | | | | | | | | | | | | |

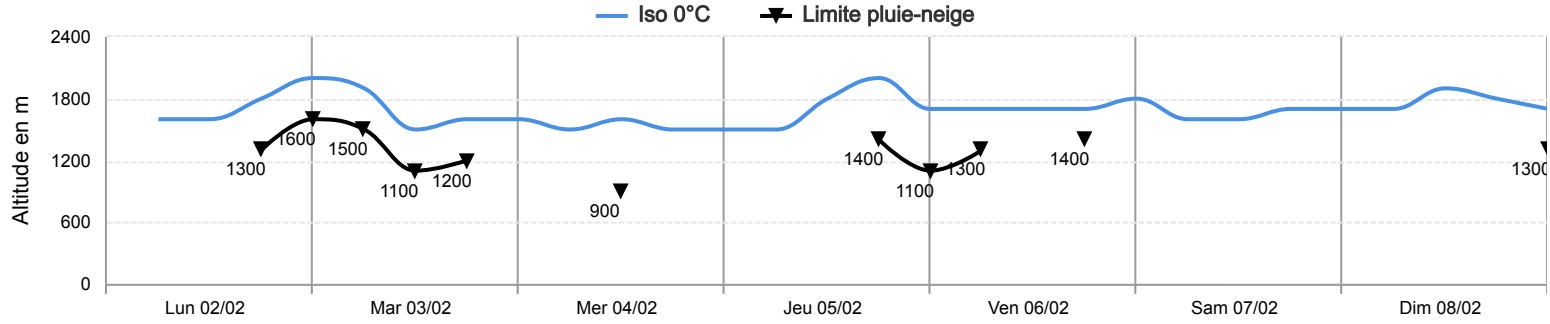


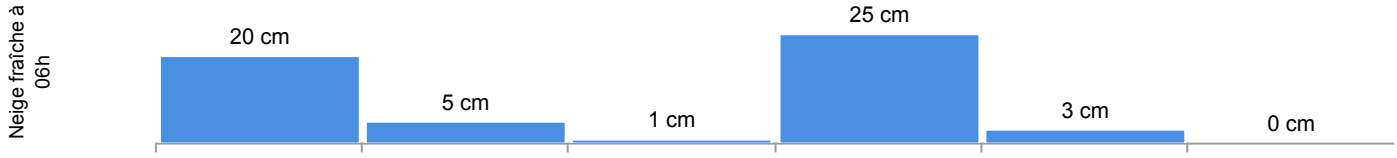


| Risque d'avalanche | lun. 02/02 | mar. 03/02 | mer. 04/02 | jeu. 05/02 | ven. 06/02 | sam. 07/02 | dim. 08/02 |
|---|---|---|---|---|---|---|---|
| | 3 | 4 | 4 | 3 | 4 | 4 | 3 |

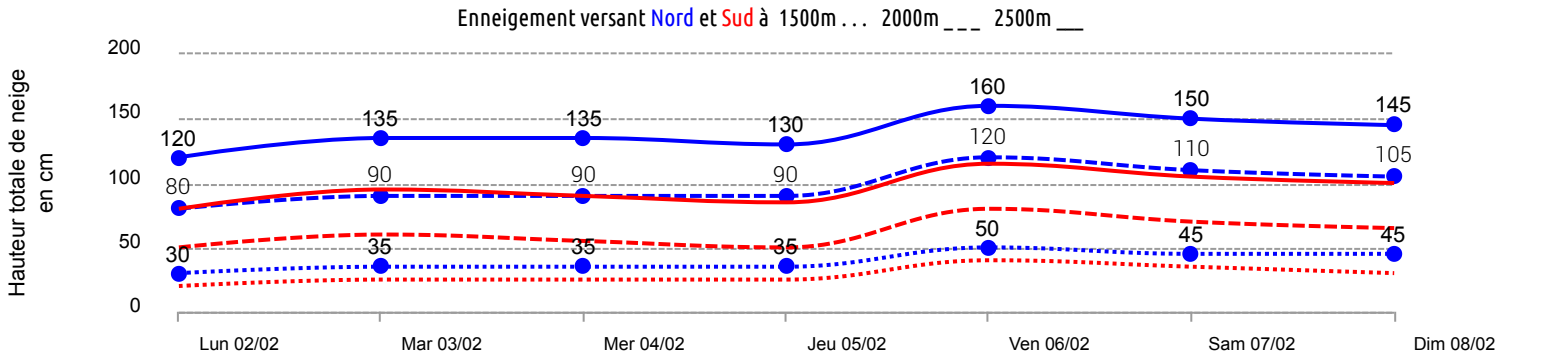


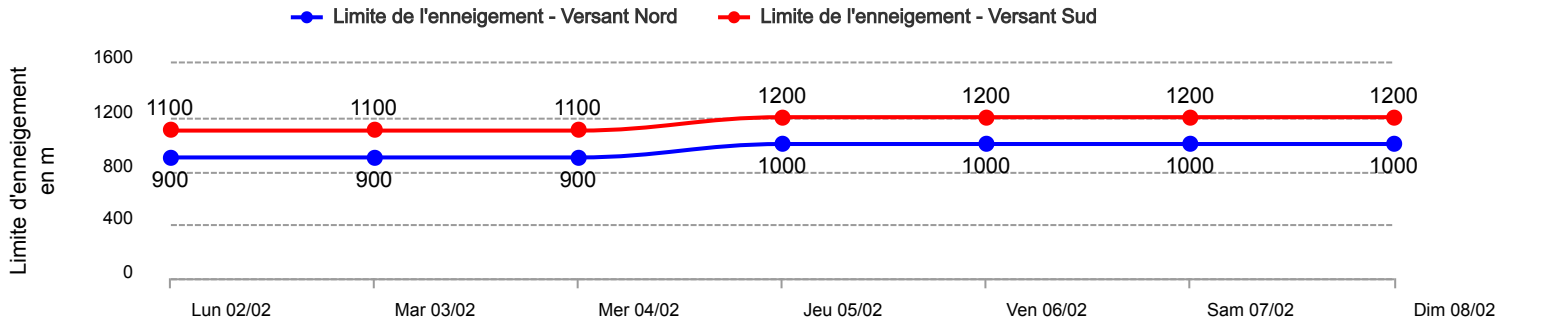


Pour consulter la vigilance en cours, veuillez vous rendre sur le site https://vigilance.meteofrance.fr/fr


Météo-France - 73 avenue de Paris, 94165 Saint-Mandé cedex - Contact : contact@meteo.fr



Rédigé par Météo-France avec la contribution des observateurs du réseau nivo-météorologiques. Partenariat : ANMSM (Maires de Stations de Montagne), DSF (Domaines Skiables de France), ADSP (Directeurs de Pistes et de la Sécurité des Stations de Sports d'Hiver) et autres acteurs de la montagne.


Bulletin neige & avalanches par téléphone au

0 892 68 10 20 Service 0,35 € / min + prix appel