Bulletin d'estimation du risque d'avalanche

(valable en dehors des pistes balisées et ouvertes)

MASSIF : Haute-Bigorre

Rédigé le dimanche 8 février 2026 à 17h

Estimation des risques pour le : LUNDI 09 FÉVRIER

NEIGE VENTÉE, RARES COUCHES FRAGILES PERSISTANTES ENFOUIES, DÉBUT D'HUMIDIFICATION

2

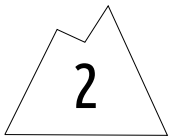

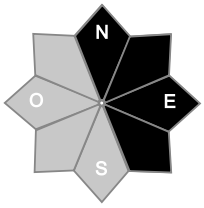

Encore des plaques

Indices de risque : 5 très fort - 4 fort - 3 marqué - 2 limité - 1 faible -- En noir : les pentes les plus dangereuses

Indice de risque limité.

Départs spontanés : En neige humide sous 2000m

Déclenchements provoqués : Plaques en nord à est, couches fragilles enfouies en secteurs froids.

Stabilité du manteau neigeux

Situation avalancheuse typique : neige ventée neige humide

Déclenchements provoqués : De nouvelles plaques se forment en journée de lundi avec les chutes de neige en expositions à l'abri du vent d'ouest. Elles peuvent être assez facilement déclenchables car reposant sur une couche de neige tendre tombée dimanche, mais restent le plus souvent de faible épaisseur et n'engendrent une avalanche de taille moyenne que dans des zones d'accumulation suffisante. Elles sont plutôt proches des crêtes, formées par un vent modéré.
La majorité des plaques plus anciennes, situées dans un large secteur nord à est, plus fréquentes en secteurs frontaliers, devient progressivement plus difficilement déclenchable par tassement.
Dans les secteurs froids bien ombragés au-dessus de 2000m, des couches fragiles sont en place dans certains secteurs. Elles sont difficilement déclenchables car enfouies assez profondément, mais leur sollicitation, parfois possible là où l'épaisseur de neige est moins importante (abords des combes, ruptures de pente), peut engendrer des avalanches avec des cassures de plus de 50cm.

Départs spontanés :
Des départs spontanés en neige humide sont attendus en toutes expositions, sous l'effet des pluies avec la remontée de la limite pluie-neige atteignant 2000m l'après-midi. D'abord petites mobilisant la neige récente tombée ces derniers jours, elles peuvent atteindre une taille moyenne en mobilisant des couches plus anciennes. Elles atteignent rarement une grande taille avant lundi soir car le manteau a déjà été humidifié à ces altitudes et les cumuls de pluie restent limités. Le risque est en hausse la nuit suivante.

Autres :
Corniches souvent imposantes au-dessus des pentes est

Qualité de la neige

Enneigement : bon pour la saison, mais les crêtes, cols et sommets en expositions ouest sont souvent pelés par le vent dans les expositions ouest. Accumulations plus importantes en secteurs frontaliers.
Limites skiables : manteau neigeux skiable à partir de 1300-1400m en nord.
État de la neige : Sous 1700m, la neige est déjà en cours d'humidification dès le petit matin. Plus haut, neige fraîche en surface, s'humidifiant sous 2000m en journée. Elle repose sur un manteau regelé sous 2000m, ou une neige sèche ancienne souvent tassée plus haut.

Aperçu météo pour le lundi 09 février

	nuit	matin	après-midi	soir

Temps humide, remontée progressive de la limite pluie-neige, renforcement des pluies la nuit suivante

	nuit	matin	après-midi	soir
Pluie-Neige		1 600 m	1 800 m	2 000 m
Iso 0 °C	1 500 m	1 900 m	2 100 m	2 400 m
Vent 2000 m	↗ 25 km/h	→ 25 km/h	→ 25 km/h	↗ 35 km/h
Vent 3000 m	→ 35 km/h	↘ 45 km/h	→ 55 km/h	→ 55 km/h

Épaisseur de neige hors-piste

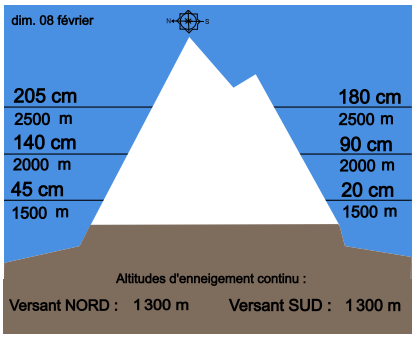

Précipitations à 1800 m

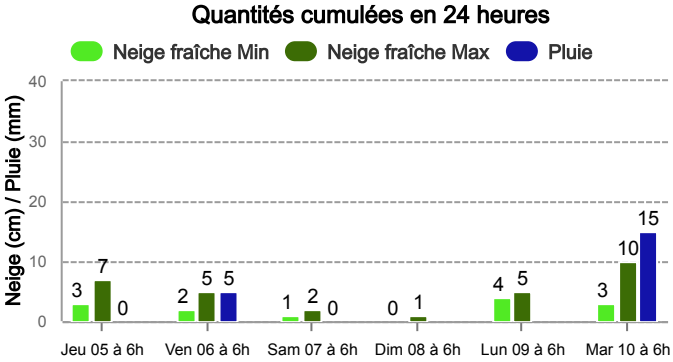

Tendance du mardi 10 février

4 **Indice de risque fort**

Risque en forte hausse avec des cumuls de pluie importants sur un manteau hivernal.

Pour consulter la vigilance en cours, veuillez vous rendre sur le site https://vigilance.meteofrance.fr/fr

Météo-France - 73 avenue de Paris, 94165 Saint-Mandé cedex - Contact : contact@meteo.fr

Bulletin neige & avalanches par téléphone au **0 892 68 10 20** Service 0,35 € / min + prix appel

Rédigé par Météo-France avec la contribution des observateurs du réseau nivo-météorologiques. Partenariat : ANMSM (Maires de Stations de Montagne), DSF (Domaines Skiables de France), ADSP (Directeurs de Pistes et de la Sécurité des Stations de Sports d'Hiver) et autres acteurs de la montagne.

Bulletin d'estimation du risque d'avalanche

(valable en dehors des pistes balisées et ouvertes)

MASSIF : Haute-Bigorre

Rédigé le dimanche 8 février 2026 à 17h

Conditions nivo-météo des 7 derniers jours

	lun. 02/02				mar. 03/02				mer. 04/02				jeu. 05/02				ven. 06/02				sam. 07/02				dim. 08/02			
	03h	09h	15h	21h	03h	09h	15h	21h	03h	09h	15h	21h	03h	09h	15h	21h	03h	09h	15h	21h	03h	09h	15h	21h	03h	09h	15h	21h
Météo																												
Vent (km/h)	70	125	120	80	50	45	55	90	95	100	60	55	75	130	95	70	70	70	60	50	45	35	40	55	55	20	45	35
à 3000m																												
Vent (km/h)	50	95	90	50	35	35	30	60	70	55	25	25	55	100	75	55	50	55	45	30	20	10	15	30	35	10	25	20
à 2000m																												

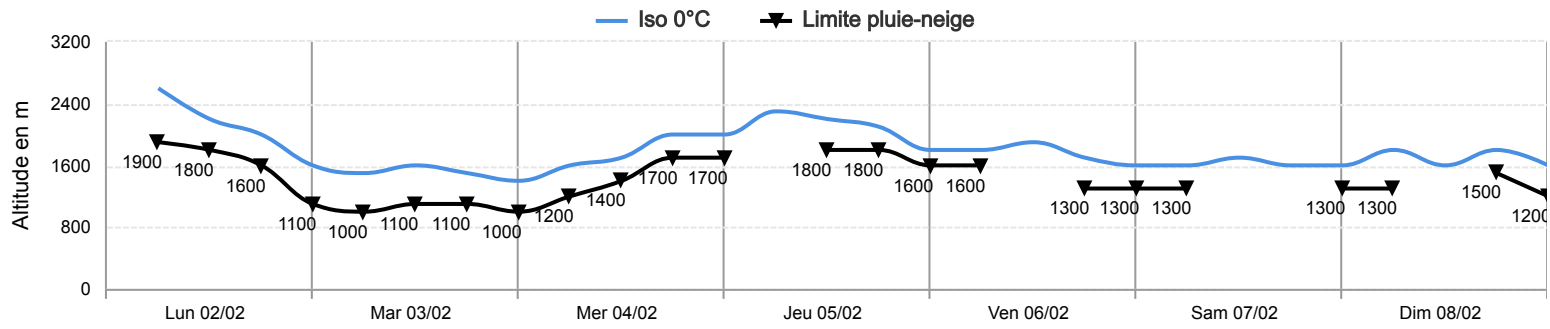

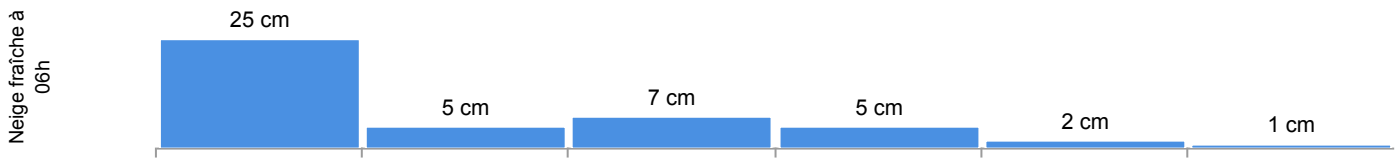

Risque d'avalanche	lun. 02/02	mar. 03/02	mer. 04/02	jeu. 05/02	ven. 06/02	sam. 07/02	dim. 08/02
	3	3	3	3	3	3	3

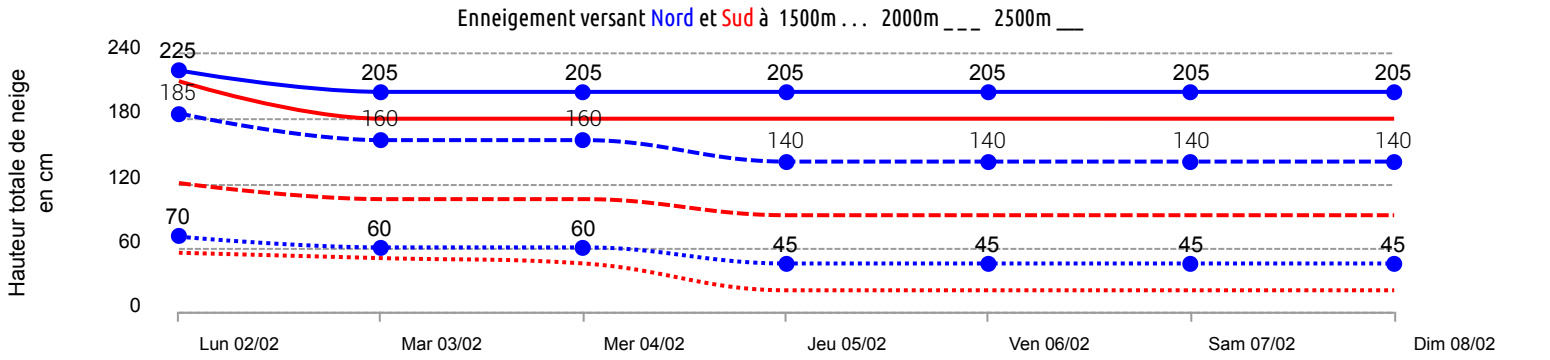

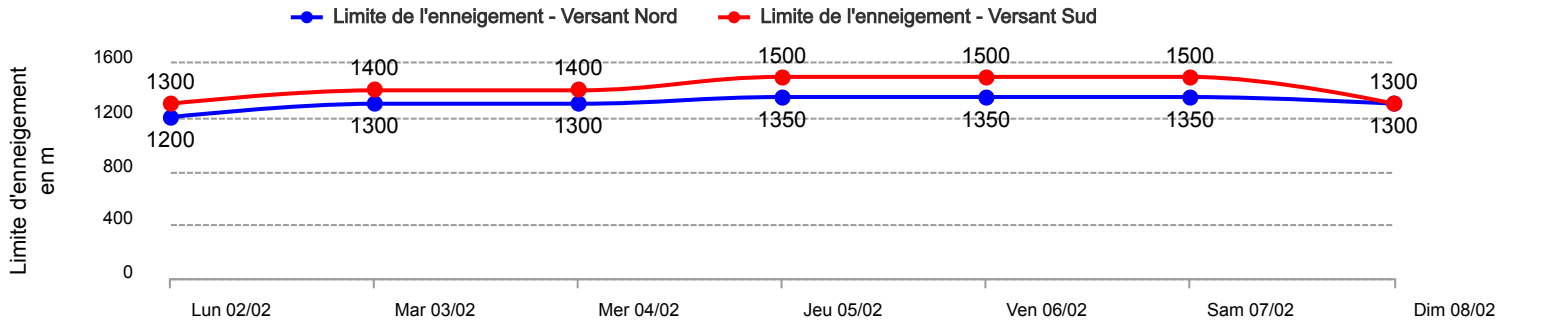

Pour consulter la vigilance en cours, veuillez vous rendre sur le site https://vigilance.meteofrance.fr/fr

Météo-France - 73 avenue de Paris, 94165 Saint-Mandé cedex - Contact : contact@meteo.fr

Bulletin neige & avalanches par téléphone au

0 892 68 10 20 Service 0,35 € / min + prix appel

Rédigé par Météo-France avec la contribution des observateurs du réseau nivo-météorologiques. Partenariat : ANMSM (Maires de Stations de Montagne), DSF (Domaines Skiables de France), ADSP (Directeurs de Pistes et de la Sécurité des Stations de Sports d'Hiver) et autres acteurs de la montagne.