Bulletin d'estimation du risque d'avalanche

(valable en dehors des pistes balisées et ouvertes)

MASSIF : Pays-Basque

Rédigé le dimanche 8 février 2026 à 17h

Estimation des risques pour le : LUNDI 09 FÉVRIER

QUELQUES PLAQUES AU PLUS HAUT DU MASSIF, HUMIDIFICATION AILLEURS

2

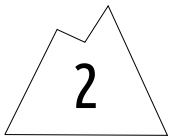

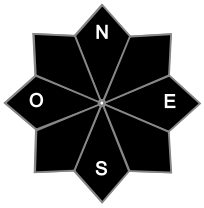

Humidification

Indices de risque : 5 très fort - 4 fort - 3 marqué - 2 limité - 1 faible -- En noir : les pentes les plus dangereuses

Indice de risque limité.

Départs spontanés : En neige humide

Déclenchements provoqués : Plaques peu épaisses en Est au-dessus de 1800 m.

Stabilité du manteau neigeux

Situation avalancheuse typique : neige humide neige ventée

Déclenchements provoqués : Au plus haut du massif, en général au-dessus de 1800m, des plaques se situent principalement dans un large secteur ouest. Elles sont assez facilement déclenchables car reposant une neige tendre tombée dimanche, mais n'atteignent une épaisseur suffisante pour engendrer une avalanche que dans certaines zones d'accumulation. Elles disparaissent rapidement l'après-midi avec le redoux

Départs spontanés : Des départs spontanés en neige humide sont attendus en toutes expositions, sous l'effet des pluies avec la remontée de la limite pluie-neige atteignant le haut du massif l'après-midi. D'abord petites mobilisant la neige récente tombée ces derniers jours, elles peuvent atteindre une taille moyenne, voire grande en fin de journée, dans de rares configurations (départ d'une zone d'accumulation en nord-est au plus haut du massif).

Qualité de la neige

Enneigement : bon pour la saison, mais les crêtes, cols et sommets sont souvent pelés par le vent dans les expositions ouest.
Limites skiables : manteau neigeux skiable à partir de 1400m en nord, 1500 en sud.
État de la neige : Lundi matin, un peu de neige fraîche en surface reposant en général sur un manteau neigeux dense et durci. L'humidification du manteau s'accélère en journée sous l'effet des pluies. La neige est rapidement gorgée d'eau à tous niveaux.

Aperçu météo pour le lundi 09 février

	nuit	matin	après-midi	soir
	Encore quelques flocons en matinée, remplacés par de la pluie, qui s'intensifie en soirée.			
Pluie-Neige		1 700 m	1 800 m	2 200 m
Iso 0 °C	1 500 m	2 000 m	2 100 m	2 400 m
Vent 1000 m	↑ 30 km/h	↑ 40 km/h	↑ 30 km/h	↑ 50 km/h
Vent 2000 m	↗ 60 km/h	↗ 50 km/h	↗ 50 km/h	↗ 60 km/h

Épaisseur de neige hors-piste

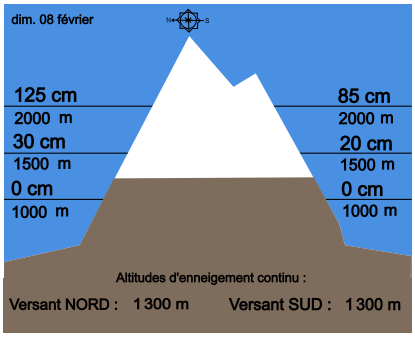

Précipitations à 1800 m

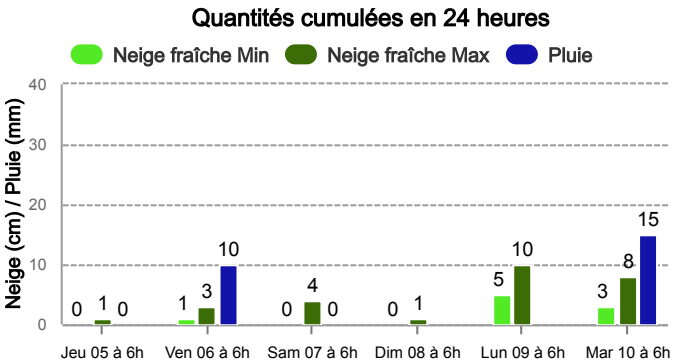

Tendance du mardi 10 février

3

Indice de risque marqué

Risque en hausse sous l'effet des importantes précipitations.

Pour consulter la vigilance en cours, veuillez vous rendre sur le site https://vigilance.meteofrance.fr/fr

Météo-France - 73 avenue de Paris, 94165 Saint-Mandé cedex - Contact : contact@meteo.fr

Rédigé par Météo-France avec la contribution des observateurs du réseau nivo-météorologiques. Partenariat : ANMSM (Maires de Stations de Montagne), DSF (Domaines Skiables de France), ADSP (Directeurs de Pistes et de la Sécurité des Stations de Sports d'Hiver) et autres acteurs de la montagne.

Bulletin neige & avalanches par téléphone au

0 892 68 10 20 Service 0,35 € / min + prix appel

RÉPUBLIQUE FRANÇAISE
Liberté Égalité Fraternité

METEO FRANCE
À VOS CÔTÉS, DANS UN CLIMAT QUI CHANGE

Bulletin d'estimation du risque d'avalanche

(valable en dehors des pistes balisées et ouvertes)

MASSIF : Pays-Basque

Rédigé le dimanche 8 février 2026 à 17h

Conditions nivo-météo des 7 derniers jours

	lun. 02/02				mar. 03/02				mer. 04/02				jeu. 05/02				ven. 06/02				sam. 07/02				dim. 08/02			
	03h	09h	15h	21h	03h	09h	15h	21h	03h	09h	15h	21h	03h	09h	15h	21h	03h	09h	15h	21h	03h	09h	15h	21h	03h	09h	15h	21h
Météo																												
Vent (km/h)	95	120	120	80	80	80	65	80	100	85	65	70	90	130	95	90	95	95	80	70	70	70	80	90	90	40	45	30
à 2000m	↑	↑	↑	↗	↗	↑	↑	↑	↑	↗	→	↗	↑	↑	↑	↗	↗	↗	↗	↗	↗	↗	↑	↑	↑	↘	↘	↑
Vent (km/h)	60	90	90	55	55	55	40	45	50	40	45	60	80	90	65	60	75	70	60	50	55	55	60	65	60	25	35	20
à 1000m	↑	↑	↑	↗	↑	↑	↑	↑	↑	↑	↑	↑	↑	↑	↗	↗	↗	↗	↑	↑	↗	↗	↑	↑	↑	↗	→	↑

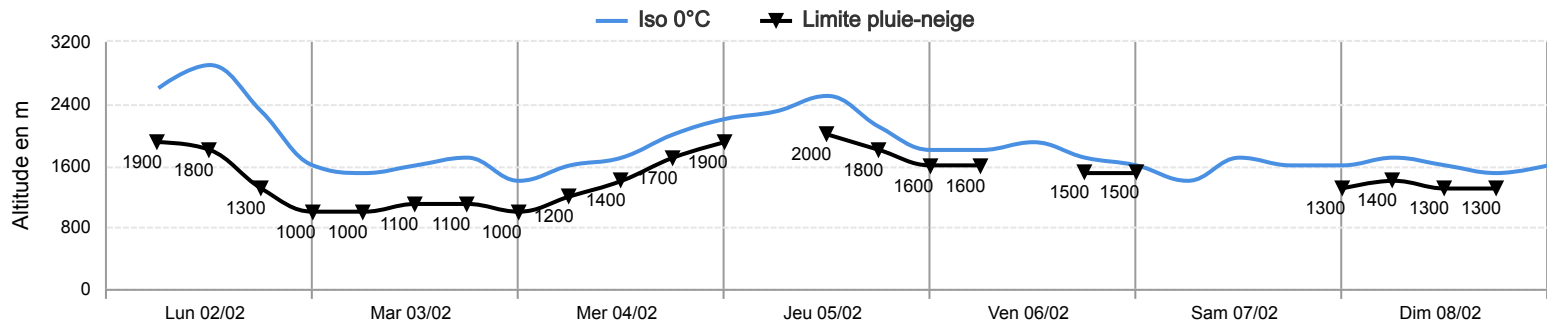

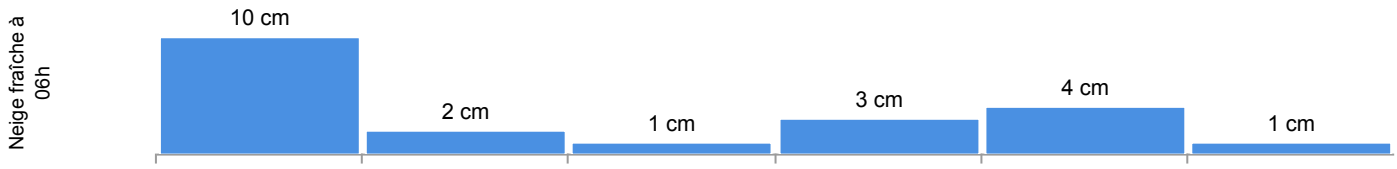

Risque d'avalanche	lun. 02/02	mar. 03/02	mer. 04/02	jeu. 05/02	ven. 06/02	sam. 07/02	dim. 08/02
	3	2	2	2	2	2	2

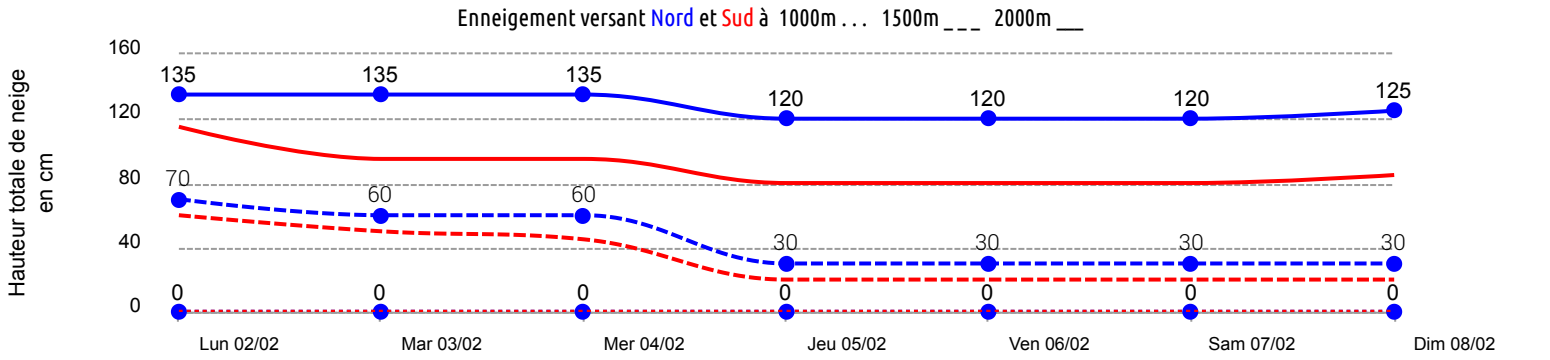

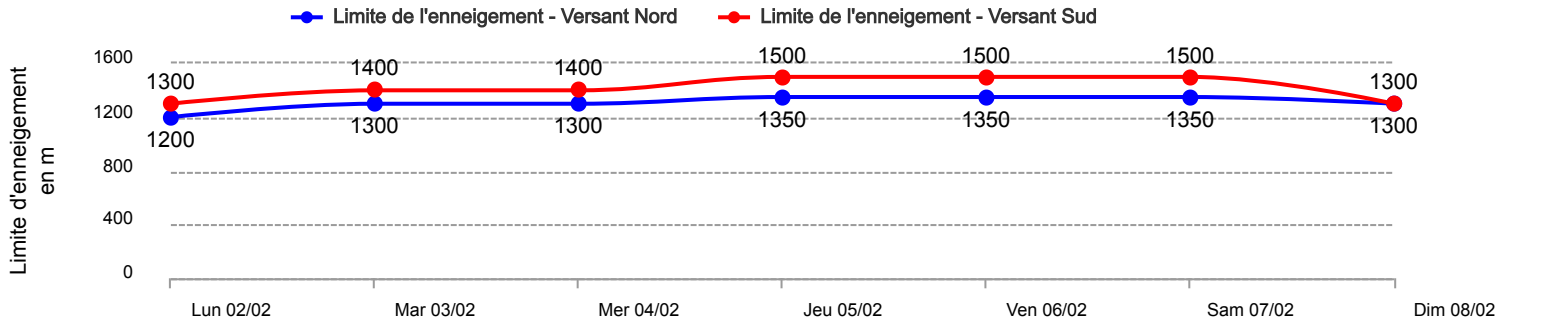

Pour consulter la vigilance en cours, veuillez vous rendre sur le site https://vigilance.meteofrance.fr/fr

Météo-France - 73 avenue de Paris, 94165 Saint-Mandé cedex - Contact : contact@meteo.fr

Rédigé par Météo-France avec la contribution des observateurs du réseau nivo-météorologiques. Partenariat : ANMSM (Maires de Stations de Montagne), DSF (Domaines Skiables de France), ADSP (Directeurs de Pistes et de la Sécurité des Stations de Sports d'Hiver) et autres acteurs de la montagne.

Bulletin neige & avalanches par téléphone au

0 892 68 10 20 Service 0,35 € / min + prix appel