Bulletin d'estimation du risque d'avalanche
(valable en dehors des pistes balisées et ouvertes)

MASSIF : Queyras

Rédigé le dimanche 8 février 2026 à 17h

Estimation des risques pour le : LUNDI 09 FÉVRIER

INSTABILITÉS ENCORE FACILES À DÉCLENCHER EN UBACS D'ALTITUDE, SOUVENT VOLUMINEUSES

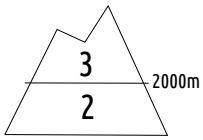

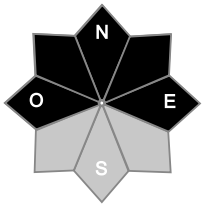

Au-dessus de 2000m indice de risque marqué, plus bas indice limité.

Départs spontanés : quelques départs superficiels en neige humide au soleil.

Déclenchements provoqués : Instabilités persistant en versants froids d'altitude, faciles à déclencher

Indices de risque : 5 très fort - 4 fort - 3 marqué - 2 limité - 1 faible -- En noir : les pentes les plus dangereuses

Stabilité du manteau neigeux

Situation avalancheuse typique : couche fragile persistante neige ventée

Déclenchements provoqués :
- nombreuses instabilités en place en versants est nord et ouest au-dessus de 1800/2000 m reposant sur des couches fragiles persistantes enfouies. Plaques d'aspect poudreux, difficiles à identifier et déclenchables au passage d'un seul skieur, souvent à distance. Elles engendrent des avalanches de taille moyennes à grande (taille 2 à 3), avec des cassures larges et épaisses, notamment au-delà de 2300/2400 m.
- quelques plaques superficielles sont en places en toutes orientations dans la neige récente ventée, plutôt à proximité des crêtes. Elles génèrent des avalanches de petites taille en généralement, mais peuvent déclencher en cascades les plaques plus volumineuses décrites précédemment.

Sous 2000 m, ainsi qu'en adrets raides d'altitude, l'instabilité est plus limitée. La neige récente a pris une bonne cohésion, avec la récente humidification, et les couches fragiles persistantes sont moins généralisées.

Départs spontanés : quelques départs de neige récente humidifiée dans les pentes raides au soleil près des rochers. Départs ponctuels de taille petite à moyenne (taille 1 à 2).

Qualité de la neige

L'enneigement est proche des normales dans les ubacs, voire excédentaire vers le Briançonnais, mais reste déficitaire dans les adrets d'altitude, notamment dans le Haut Guil.
Données observées : 136 cm en versant nord du col Izoard à 2300 m, 56 cm à la Nivôse du Col Agnel à 2630 m, 63 cm à Ristolas à 1670 m.

Limite d'enneigement skiable : dès 1000/1300 m en ubacs, plutôt 1500/1700 m en adrets avec peu de sous-couche jusqu'à haute altitude, notamment dans le Haut Guil.

État de la neige de surface : 10/20 cm de neige récente, restée poudreuse et légère en versants froids au-dessus de 1700/1800 m, et parfois densifiée ou cartonnée par le vent près des crêtes. En versants ensoleillés, neige récente plus tassée et croutée sous 2400/2500 m.

Aperçu météo pour le lundi 09 février

nuit	matin	après-midi	soir

Belles éclaircies le matin, passages nuageux l'après-midi, avec quelques flocons possibles en soirée.

Pluie-Neige				
Iso 0 °C	1 600 m	1 600 m	1 700 m	1 600 m
Vent 2000 m	↙ 10 km/h	↑ 10 km/h	↑ 15 km/h	↑ 10 km/h
Vent 3000 m	← 15 km/h	↖ 10 km/h	→ 15 km/h	↗ 15 km/h

Épaisseur de neige hors-piste

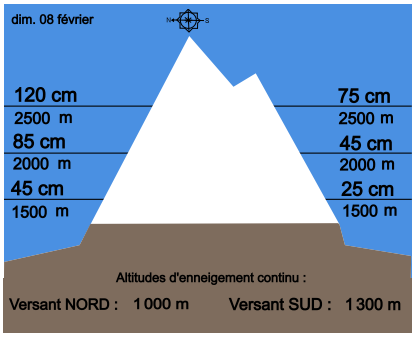

Précipitations à 1800 m

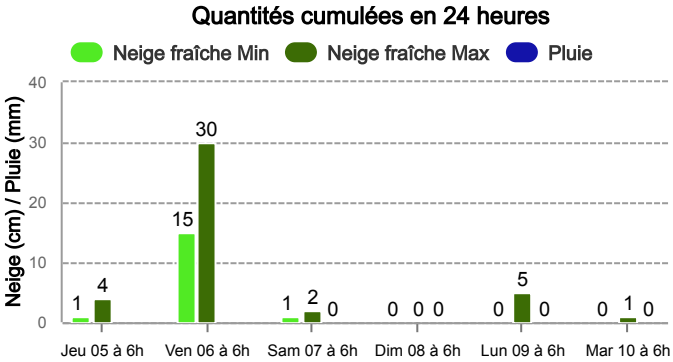

Tendance du mardi 10 février

Indice de risque marqué

Risque en hausse, mais restant marqué avec les nouvelles chutes de neige.

Pour consulter la vigilance en cours, veuillez vous rendre sur le site https://vigilance.meteofrance.fr/fr

Météo-France - 73 avenue de Paris, 94165 Saint-Mandé cedex - Contact : contact@meteo.fr

Rédigé par Météo-France avec la contribution des observateurs du réseau nivo-météorologiques. Partenariat : ANMSM (Maires de Stations de Montagne), DSF (Domaines Skiables de France), ADSP (Directeurs de Pistes et de la Sécurité des Stations de Sports d'Hiver) et autres acteurs de la montagne.

Bulletin neige & avalanches par téléphone au
0 892 68 10 20 Service 0,35 € / min + prix appel

RÉPUBLIQUE FRANÇAISE
Liberté Égalité Fraternité

METEO FRANCE
À VOS CÔTÉS, DANS UN CLIMAT QUI CHANGE

Bulletin d'estimation du risque d'avalanche

(valable en dehors des pistes balisées et ouvertes)

MASSIF : Queyras

Rédigé le dimanche 8 février 2026 à 17h

Conditions nivo-météo des 7 derniers jours

	lun. 02/02				mar. 03/02				mer. 04/02				jeu. 05/02				ven. 06/02				sam. 07/02				dim. 08/02			
	03h	09h	15h	21h	03h	09h	15h	21h	03h	09h	15h	21h	03h	09h	15h	21h	03h	09h	15h	21h	03h	09h	15h	21h	03h	09h	15h	21h
Météo																												
Vent (km/h)	20	30	40	60	80	60	40	40	30	30	25	30	20	25	40	25	35	35	40	25	25	15	15	10	10	20	35	35
à 3000m																												
Vent (km/h)	10	10	20	30	40	35	25	15	15	20	15	10	10	10	10	15	5	15	25	10	10	10	15	5	5	15	30	30
à 2000m																												

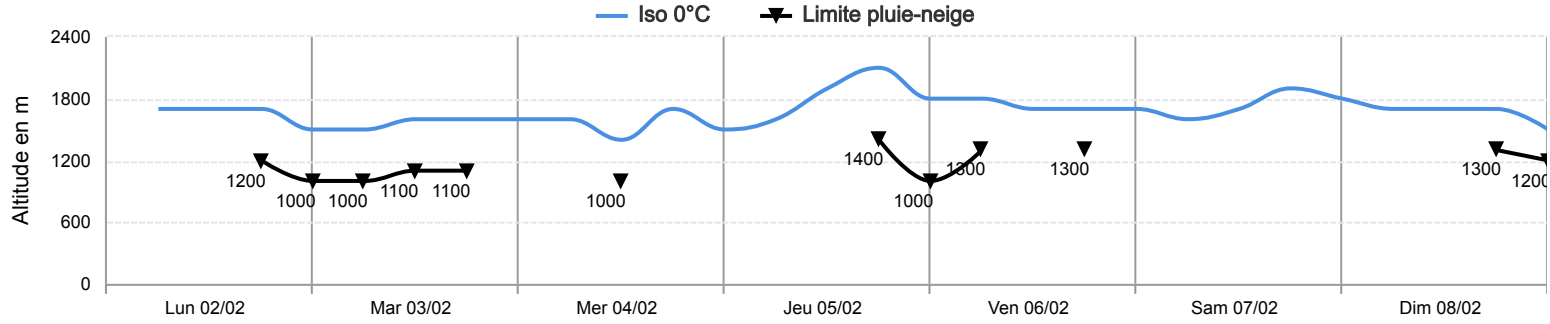

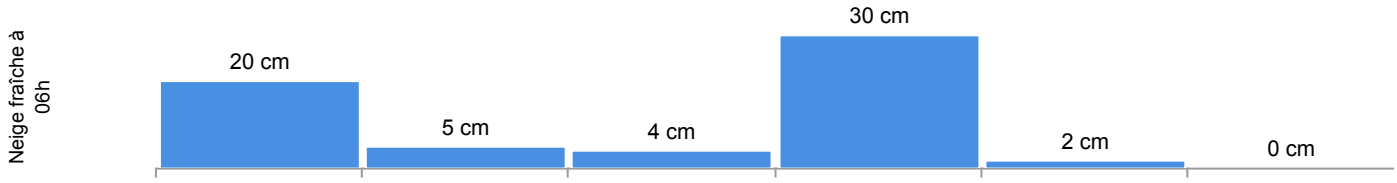

Risque d'avalanche	lun. 02/02	mar. 03/02	mer. 04/02	jeu. 05/02	ven. 06/02	sam. 07/02	dim. 08/02
	3	4	4	3	4	4	3

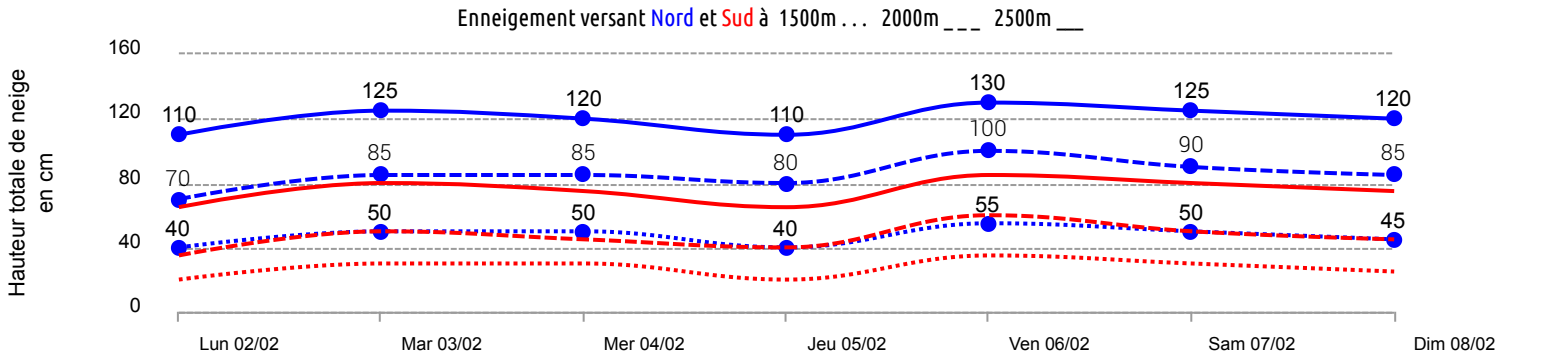

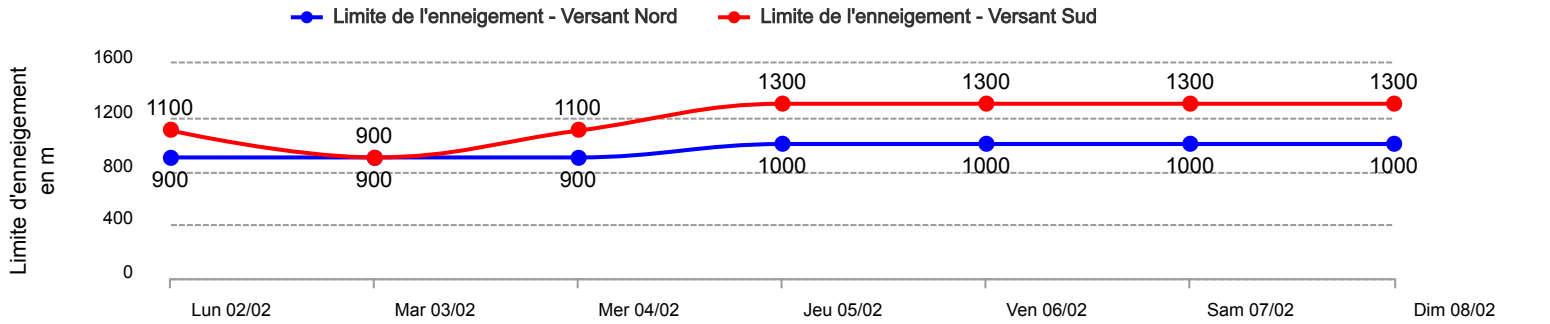

Pour consulter la vigilance en cours, veuillez vous rendre sur le site https://vigilance.meteofrance.fr/fr

Météo-France - 73 avenue de Paris, 94165 Saint-Mandé cedex - Contact : contact@meteo.fr

Rédigé par Météo-France avec la contribution des observateurs du réseau nivo-météorologiques. Partenariat : ANMSM (Maires de Stations de Montagne), DSF (Domaines Skiables de France), ADSP (Directeurs de Pistes et de la Sécurité des Stations de Sports d'Hiver) et autres acteurs de la montagne.

Bulletin neige & avalanches par téléphone au

0 892 68 10 20 Service 0,35 € / min + prix appel