GOBIERNO DE ESPAÑA
VICEPRESIDENCIA TERCERA DEL GOBIERNO
MINISTERIO PARA LA TRANSICIÓN ECOLÓGICA Y EL RETO DEMOGRÁFICO

Boletín de información nivológica y de peligro de aludes

Pirineo Catalán

aemet Agencia Estatal de Meteorología

lunes, 9 de febrero de 2026

Pronóstico hasta las 24 horas del martes, día 10 de febrero

(Válido fuera de pistas de esquí balizadas y abiertas)

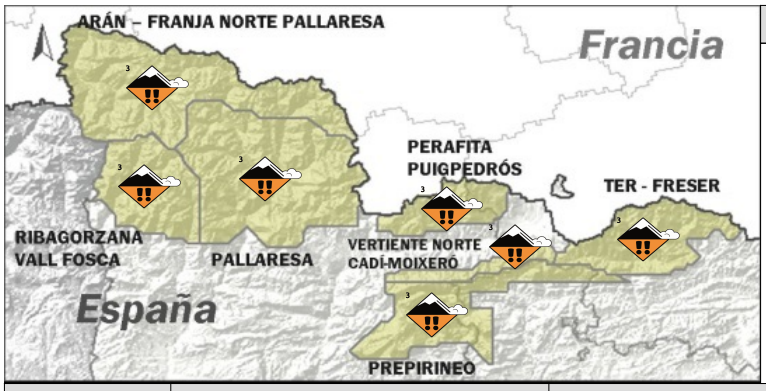

Problemas de aludes

Nieve húmeda

Placas de viento

Macizo	Peligro	Problemas de aludes, cota, orientación, tamaño	Innivación observada (m)
Arán - Franja norte Pallaresa	3 Notable	Nieve húmeda: 2400, N O E S, 3 Placas de viento: 2400, N O E S, 3	2026-02-09 N S Cotas bajas
Ribagorzana - Vall Fosca	3 Notable	Nieve húmeda: 2400, N O E S, 2 Placas de viento: 2400, N O E S, 2	2026-02-09 N S Cotas bajas
Pallaresa	3 Notable	Nieve húmeda: 2400, N O E S, 2 Placas de viento: 2400, N O E S, 2	2026-02-09 N S Cotas bajas

Por la mañana: 2 → 3

Boletín de información nivológica y de peligro de aludes

Pirineo Catalán

Perafita - Puigpedrós	3 Por la mañana **Notable**	**Nieve húmeda**  **Placas de viento** 	2026-02-09 Cotas bajas
Ter - Freser	3 Por la mañana **Notable**	**Nieve húmeda**  **Placas de viento** 	2026-02-09 Cotas bajas
Vertiente norte Cadí - Moixeró	3 Por la mañana **Notable**	**Nieve húmeda**  **Placas de viento** 	2026-02-09 Cotas bajas
Prepirineo	3 Por la mañana **Notable**	**Nieve húmeda**  **Placas de viento** 	2026-02-09 Cotas bajas

Estado del manto y observaciones recientes

Las últimas nevadas han dejado depósitos de varios cm, aunque han sido de escasa relevancia en general, incluso en algunos casos la acción del viento y la compactación de la nieve ha supuesto una ligera reducción de los grosores del manto, aunque sigue siendo abundante y continuo desde cotas bajas, con espesores que se van incrementando conforme ascendemos, de manera que en torno a 2.200 metros se alcanzan los 120 a 200 cm, aún más en ventisqueros, hoyas y otras zonas propensas a la acumulación.

AEMET. Se autoriza la reproducción de su contenido citando la fuente.

En cotas altas la nieve se mantiene seca y muy venteada, con numerosas placas en muchas orientaciones. Además, en zonas de umbría, todavía pueden persistir estratos débiles.

Evolución del manto y peligro de aludes para el martes, día 10

Situación de nieve húmeda, así como de placas de viento en la alta montaña.

Durante las próximas 24 horas se espera que las precipitaciones tiendan a generalizarse e intensificarse, con una cota de nieve en progresivo ascenso hasta situarse en altitudes considerables de cara a media mañana, por lo que la lluvia irá percolando, humedeciendo el manto e inestabilizándolo. En consecuencia serán frecuentes las purgas de nieve húmeda en laderas con suficiente inclinación y sin orientación preferente, que podrán ser de tamaño mediano o, en algún caso, grande, suficiente como para enterrar a un grupo de personas.

Por encima de unos 2.400 ó 2.500 metros las precipitaciones serán íntegramente en forma sólida y estarán acompañadas de fuertes vientos de componente oeste, volviendo a formase placas en diferentes áreas de la alta montaña, aunque con preferencia en vertientes este, que vendrán a sumarse a las ya existentes, en algunos casos difíciles de localizar. Todas estas estructuras permanecerán frágiles y podrán fracturarse ante una sobrecargas débiles, como es el paso de un esquiador, dando lugar a aludes de dimensión mediana o, localmente, alguno grande. Además, en las umbrías de la alta montaña pueden existir aún capas débiles en el interior del manto que en zonas de poco espesor podrían resultar problemáticas, por lo que se recomienda extremar las precauciones.

Predicción meteorológica para el martes, día 10

Muy nuboso o cubierto en los macizos occidentales y nuboso o muy nuboso en el resto. Se esperan precipitaciones débiles o moderadas, localmente persistentes en el valle de Arán y Franja Norte Pallaresa, que en ocasiones serán en forma de chubascos acompañados de alguna tormenta. Cota de nieve: subiendo a 2.400 ó 2.500 metros, pero con tendencia a descender a últimas horas a unos 2.000 ó 2.200. Temperaturas en ascenso, notable de las mínimas. Heladas débiles en la alta montaña, localmente moderadas. Soplarán vientos moderados o fuertes de componente oeste, con rachas muy fuertes en cotas altas y zonas expuestas.

Datos en la atmósfera libre:

Altitud de la isoterma de 0 ºC: 2.700 m
Altitud de la isoterma de -10 ºC: 4.400 m

Viento a 1500 m: W 50 km/h
Viento a 3000 m: NW 70 km/h

Evolución para el miércoles día 11

Sin cambios o en ligero ascenso.

AEMET. Se autoriza la reproducción de su contenido citando la fuente.

Boletín de información nivológica y de peligro de aludes

Pirineo Catalán

Escala europea de peligro de aludes

Débil | Limitado | Notable | Fuerte | Muy Fuerte

Problemas de aludes

Nieve reciente | Placas de viento | Capas débiles persistentes | Nieve húmeda | Deslizamientos basales | Sin problema evidente

Nota1: Se recuerda que, siempre que haya nieve, la ausencia total de peligro no existe. Hay que tener presente que en circunstancias desfavorables, con aludes de tamaño 1 (alud pequeño o colada) y tamaño 2 (alud mediano), se pueden sufrir severos daños personales.

Nota2: Los BPA se elaboran en base a información meteorológica así como al estado del manto nivoso a través de sondeos puntuales. Se advierte a los usuarios de la variabilidad de esta información al extrapolarla a zonas extensas de montaña. Por ello, AEMET no se hace responsable de su uso para la toma de decisiones que conciernen a la seguridad personal, ni de los riesgos físicos o materiales de ellas derivadas.

AEMET. Se autoriza la reproducción de su contenido citando la fuente.