aineva.it

Dienstag 10.02.2026

Aktualisiert am 09.02.2026 um 19:09

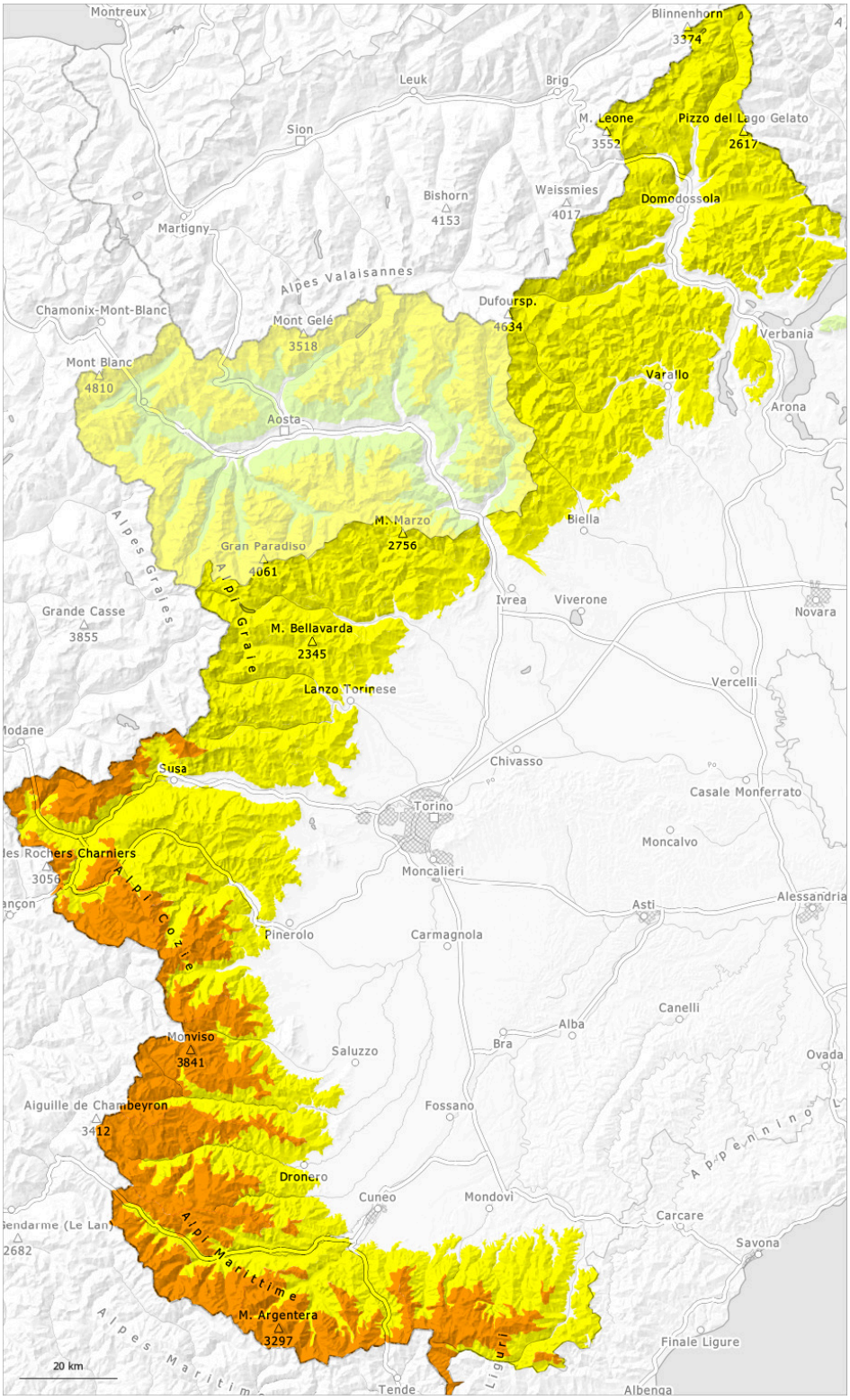

1	2	3	4	5
gering	mäßig	erheblich	groß	sehr groß

Gefahrenstufe 3 - Erheblich

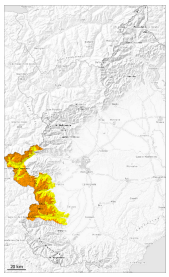

Waldgrenze

Tendenz: Lawinengefahr bleibt gleich
am Mittwoch, den 11.02.2026

Triebschnee

Waldgrenze

Triebschnee

Waldgrenze

In mittleren und hohen Lagen sind weiterhin trockene Schneebrettlawinen möglich. Die Lawinengefahr nimmt noch nicht ab.

Mit Neuschnee und mäßigem Wind entstanden meist dünne Triebschneeansammlungen.
Triebschneeansammlungen können schon von einzelnen Wintersportlern ausgelöst werden. Dies vor allem an steilen Hängen sowie in Rinnen, Mulden und hinter Geländekanten auch in mittleren Lagen.
Lawinen können v.a. an steilen Schattenhängen in tieferen Schichten ausgelöst werden.
Die Gefahrenstellen sind bei der schlechten Sicht kaum zu erkennen.

Eine überlegte Routenwahl ist nötig. Entlastungsabstände und Einzelabfahrten werden empfohlen.

Schneedecke

Gefahrenmuster gm.6: lockerer schnee und wind

Seit Sonntag fielen oberhalb von rund 1200 m 5 bis 10 cm Schnee. Mit Neuschnee und teils mäßigem Wind aus westlichen Richtungen entstanden vor allem oberhalb der Waldgrenze weitere Triebschneeansammlungen. Neu- und Triebschnee liegen an windgeschützten Schattenhängen auf weichen Schichten.
Der obere Teil der Schneedecke ist abbauend umgewandelt, mit einer nicht tragfähigen Schmelzharschkruste an der Oberfläche, vor allem an steilen Sonnenhängen.

Mittlere und hohe Lagen: Im unteren Teil der Schneedecke sind vor allem an sehr steilen Schattenhängen vereinzelt störanfällige Schwachschichten vorhanden.

Gefahrenstufe 3 - Erheblich

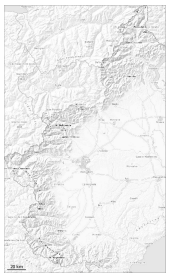

Waldgrenze

Tendenz: Lawinengefahr bleibt gleich
am Mittwoch, den 11.02.2026

Triebschnee

Waldgrenze

Neuschnee

Mit Neuschnee und Wind verbreitet erhebliche Gefahr von trockenen Lawinen. Dies v.a. oberhalb der Waldgrenze.

Mit Neuschnee und mäßigem Wind entstanden weitere Triebschneeansammlungen. Der Neuschnee und insbesondere die teils großen Triebschneeansammlungen können an allen Expositionen und allgemein oberhalb der Waldgrenze von einzelnen Wintersportlern ausgelöst werden. Dies vor allem an steilen Hängen und in Kammlagen, Rinnen und Mulden.
Die Lawinen können in den verschiedenen Neu- und Triebschneeschichten anreißen und groß werden. Die Gefahrenstellen sind bei der schlechten Sicht kaum zu erkennen.

Eine vorsichtige Routenwahl und Entlastungsabstände werden empfohlen. Touren erfordern große Vorsicht und Zurückhaltung.

Schneedecke

Gefahrenmuster gm.6: lockerer schnee und wind

In den letzten zwei Tagen fielen oberhalb von rund 1200 m 10 bis 15 cm Schnee, lokal auch mehr. Mit Schneefall und mäßigem Westwind entstanden frische Triebschneeansammlungen. Neu- und Triebschnee liegen verbreitet auf weichen Schichten.
Der obere Teil der Schneedecke ist abbauend umgewandelt, mit einer nicht tragfähigen Schmelzharschkruste an der Oberfläche, v.a. an Sonnenhängen.

Oberhalb von rund 1500 m liegt viel Schnee.

Gefahrenstufe 3 - Erheblich

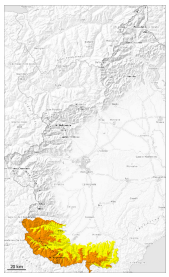

Waldgrenze

Tendenz: Lawinengefahr bleibt gleich
am Mittwoch, den 11.02.2026

Triebschnee

Waldgrenze

Nassschnee

1500m

Mit Neuschnee und Wind verbreitet erhebliche Gefahr von trockenen Lawinen. Dies v.a. oberhalb der Waldgrenze.

Mit Neuschnee und mäßigem Wind entstanden weitere Triebschneeansammlungen. Der Neuschnee und insbesondere die teils großen Triebschneeansammlungen können an allen Expositionen und allgemein oberhalb der Waldgrenze von einzelnen Wintersportlern ausgelöst werden. Dies vor allem an steilen Hängen und in Kammlagen, Rinnen und Mulden.
Die Lawinen können in den verschiedenen Neu- und Triebschneeschichten anreißen und groß werden.
Die Gefahrenstellen sind bei der schlechten Sicht kaum zu erkennen.
Unterhalb von rund 1500 m sind kleine und mittlere feuchte und nasse Lawinen möglich.

Eine vorsichtige Routenwahl und Entlastungsabstände werden empfohlen.

Schneedecke

Gefahrenmuster gm.6: lockerer schnee und wind

In den letzten zwei Tagen fielen oberhalb von rund 1200 m 10 bis 15 cm Schnee, lokal auch mehr. Mit Schneefall und mäßigem Westwind entstanden frische Triebschneeansammlungen. Neu- und Triebschnee liegen verbreitet auf weichen Schichten.
Der obere Teil der Schneedecke ist abbauend umgewandelt, mit einer nicht tragfähigen Schmelzharschkruste an der Oberfläche, v.a. an Sonnenhängen.
Die Schneedecke wird in tiefen Lagen feucht.

Oberhalb von rund 1500 m liegt viel Schnee.

Gefahrenstufe 2 - Mäßig

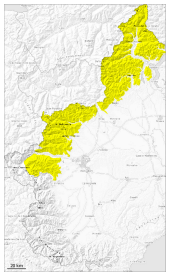

2

Tendenz: Lawinengefahr bleibt gleich
am Mittwoch, den 11.02.2026

Triebschnee

Einzelne Gefahrenstellen liegen vor allem im Steilgelände in mittleren und hohen Lagen.

Die frischen und schon etwas älteren Triebschneeansammlungen bilden die Hauptgefahr. Die Gefahrenstellen liegen vor allem in Kamm- und Passlagen sowie an steilen, wenig befahrenen Hängen. In der Höhe sind diese Gefahrenstellen häufiger und größer.
Die Lawinen sind mittelgroß und meist nur mit großer Belastung auslösbar.
Sehr vereinzelt können Lawinen auch im Altschnee anbrechen und groß werden.

Die Gefahrenstellen sind bei der schlechten Sicht kaum zu erkennen. Eine vorsichtige Routenwahl und Entlastungsabstände werden empfohlen.

Schneedecke

Gefahrenmuster gm.6: lockerer schnee und wind

Die Gefahrenstellen liegen besonders an Triebschneehängen. Die Triebschneeansammlungen liegen vor allem an Schattenhängen auf weichen Schichten.
Der obere Teil der Schneedecke ist abbauend umgewandelt, mit einer nicht tragfähigen Schmelzharschkruste an der Oberfläche, besonders an steilen Schattenhängen.
Im unteren Teil der Schneedecke sind an Schattenhängen kantig aufgebaute Schwachschichten vorhanden, besonders in mittleren und hohen Lagen.