aineva.it

Dienstag 10.02.2026

Aktualisiert am 09.02.2026 um 19:09

Vormittag

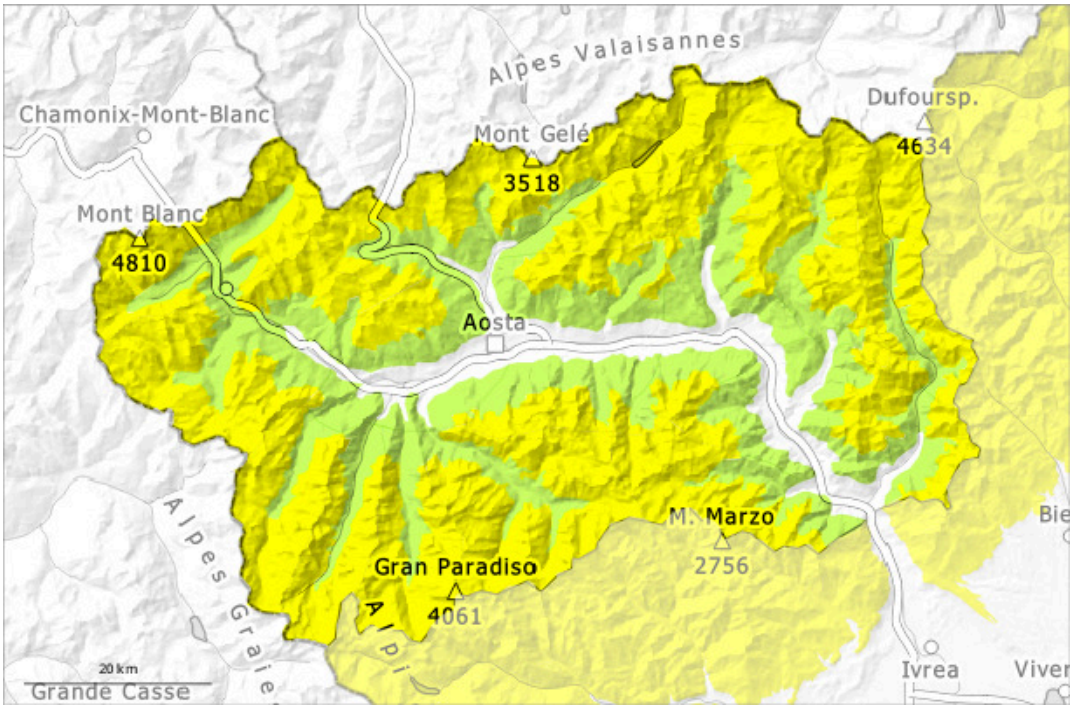

Nachmittag

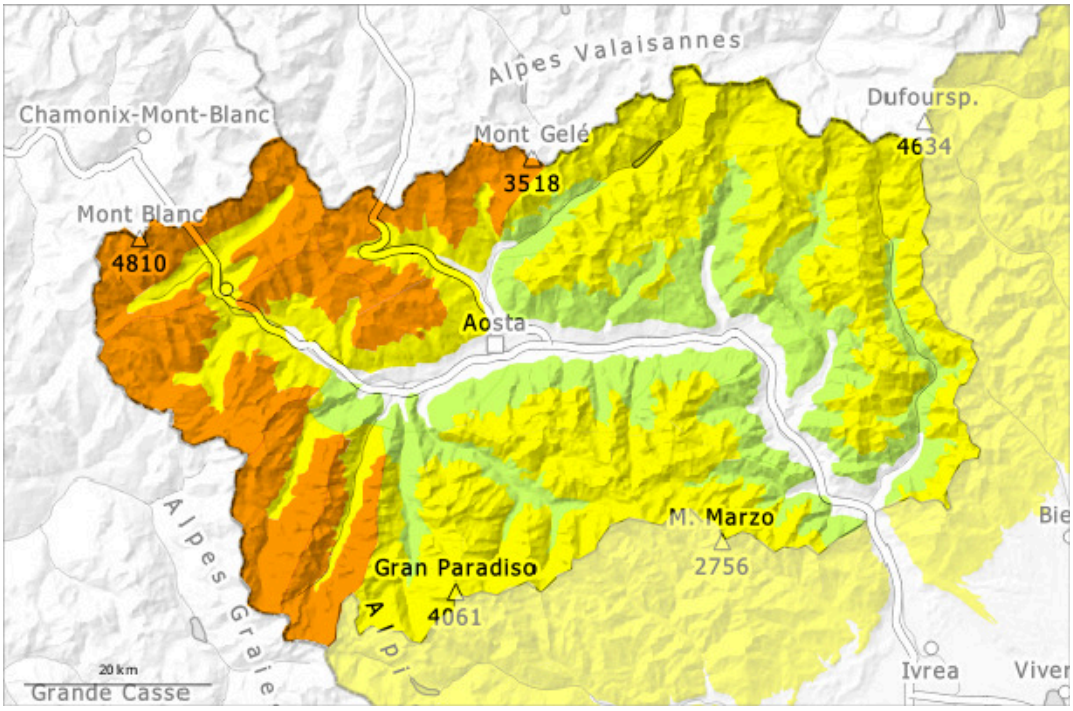

1	2	3	4	5
gering	mäßig	erheblich	groß	sehr groß

Gefahrenstufe 3 - Erheblich

AM:

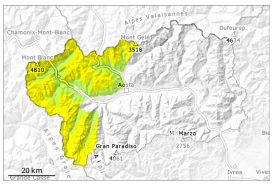

2000m

Tendenz: Lawinengefahr steigt
am Mittwoch, den 11.02.2026

Altschnee

2000m

PM:

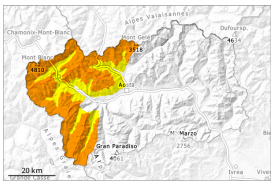

2200m

Tendenz: Lawinengefahr steigt
am Mittwoch, den 11.02.2026

Triebschnee

2200m

Altschnee

2000m

V.a. entlang der Grenze zu Frankreich und entlang der Grenze zur Schweiz sind die Gefahrenstellen weiter verbreitet und die Gefahr etwas höher.

Schwachschichten im Altschnee erfordern Vorsicht. Schon einzelne Wintersportler können Lawinen auslösen. Erklärung: "sie" darf nur für "die Lawinen" stehen können in tiefen Schichten ausgelöst werden und vereinzelt groß werden. Fernauslösungen sind möglich. Wummgeräusche und Risse beim Betreten der Schneedecke sind Alarmzeichen.
Mit Neuschnee und Wind nehmen die Gefahrenstellen am Nachmittag zu. Die weichen Triebschneeansammlungen werden vor allem an den Expositionen Nord über Ost bis Süd zunehmend störanfällig.
Mit der Intensivierung der Schneefälle sind im Tagesverlauf einzelne spontane Lawinen möglich, auch mittelgroße.

Schneedecke

Gefahrenmuster gm.6: lockerer schnee und wind

Dienstag: Es fallen oberhalb von rund 1600 m 20 bis 40 cm Schnee.
Der Neuschnee und insbesondere die weichen und harten Triebschneeansammlungen bedecken eine schwache alte Schneedecke und teilweise auch Oberflächenfrost. Die Triebschneeansammlungen sind teilweise schlecht mit dem Altschnee verbunden.
In der Altschneedecke sind v.a. an West-, Nord- und Osthängen kantig aufgebaute Schwachschichten vorhanden.
Seit Freitag gingen an sehr steilen Hängen mehrere mittlere und vereinzelt große Lawinen spontan ab. In

den letzten drei Tagen wurden einige kleine und mittlere Schneebrettlawinen von Personen ausgelöst.

Tendenz

Die Lawinengefahr steigt im Tagesverlauf rasch an. Der viele Neuschnee sowie die an allen Expositionen entstehenden Triebschneeansammlungen bilden die Hauptgefahr.

Gefahrenstufe 2 - Mäßig

AM:

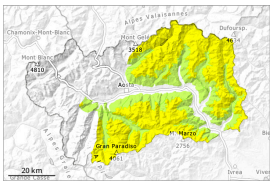

2000m

Tendenz: Lawinengefahr steigt
am Mittwoch, den 11.02.2026

Altschnee

2000m

PM:

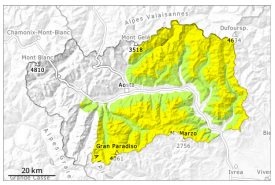

Waldgrenze

Tendenz: Lawinengefahr steigt
am Mittwoch, den 11.02.2026

Triebschnee

Waldgrenze

Altschnee

2000m

Und mit zunehmender Höhe werden die Gefahrenstellen immer häufiger.

Schwachschichten im Altschnee erfordern Vorsicht. Schon einzelne Wintersportler können Lawinen auslösen. Erklärung: "sie" darf nur für "die Lawinen" stehen können in tiefen Schichten ausgelöst werden und mittlere Größe erreichen. Fernauslösungen sind möglich. Wummgeräusche und Risse beim Betreten der Schneedecke sind Alarmzeichen.
Mit Neuschnee und Wind nehmen die Gefahrenstellen am Nachmittag zu. Die weichen Triebschneeansammlungen werden vor allem an den Expositionen Nord über Ost bis Süd zunehmend störanfällig.
Mit der Intensivierung der Schneefälle sind am Abend einzelne spontane Lawinen möglich, aber meist nur kleine.

Schneedecke

Gefahrenmuster gm.6: lockerer schnee und wind | gm.1: bodennahe schwachschicht

Dienstag: Bis am Abend fallen oberhalb von rund 1600 m 5 bis 10 cm Schnee, lokal auch mehr.
Der Neuschnee und insbesondere die weichen und harten Triebschneeansammlungen bedecken eine schwache alte Schneedecke und teilweise auch Oberflächenfrost.
In der Altschneedecke sind v.a. an West-, Nord- und Osthängen kantig aufgebaute Schwachschichten vorhanden.

Seit Freitag gingen an sehr steilen Hängen mehrere kleine bis mittlere Lawinen spontan ab. In den letzten drei Tagen wurden vereinzelt kleine bis mittlere Schneebrettlawinen von Personen ausgelöst.

Tendenz

Die Lawinengefahr steigt im Tagesverlauf rasch an.