ICGC Institut Cartogràfic i Geològic de Catalunya

Servei Meteorològic de Catalunya meteo.cat

Boletín de peligro de aludes para el Pirineo de Catalunya
Del 09/02/2026 al 10/02/2026

(Válido fuera pistas de esquí y zonas no controladas)

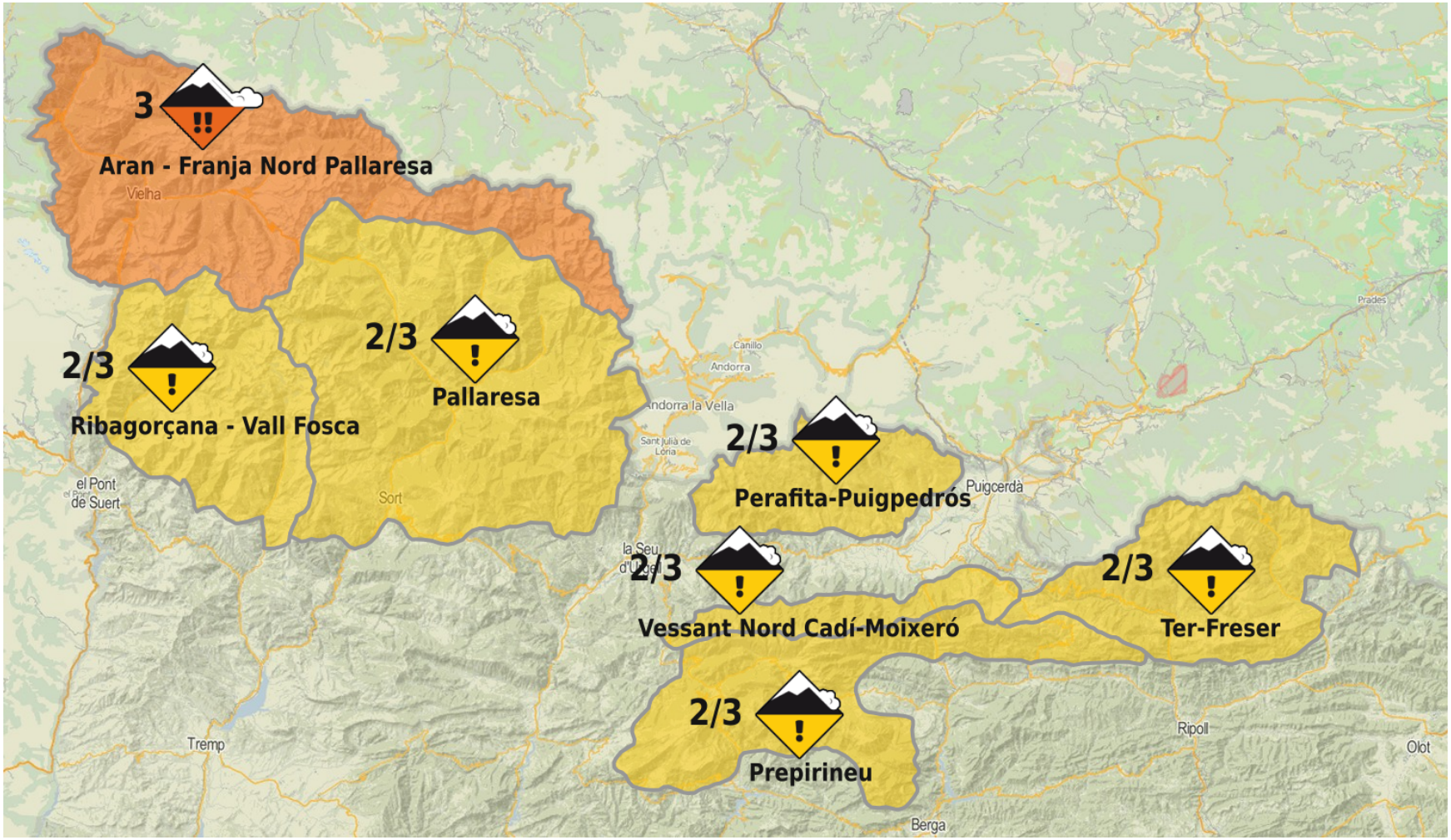

5 MUY FUERTE	4 FUERTE	3 NOTABLE	2 LIMITADO	1 DÉBIL

ICGC Institut Cartogràfic i Geològic de Catalunya

meteo.cat Servei Meteorològic de Catalunya

Boletín de peligro de aludes Aran - Franja Nord Pallaresa Del 09/02/2026 al 10/02/2026

(Válido fuera pistas de esquí y zonas no controladas)

NOTABLE (3).

Situación primaria

Nieve húmeda

Distribución

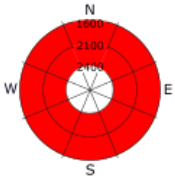

Tamaño

Origen

Tendencia

Situación secundaria

Nieve venteada

Distribución

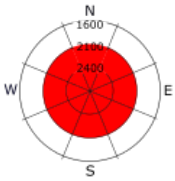

Tamaño

Origen

Tendencia

Estado del manto nivoso

El paulatino humedecimiento del manto con la llegada de un frente cálido generará problemas de nieve húmeda. Los aludes húmedos caerán de forma natural con la subida de la cota de nieve y en momentos en que precipite lluvia. Llegarán hasta tamaño medio (con capacidad de enterrar a una persona) y se darán, sobre todo, en pendientes fuertemente inclinadas. Caerán también deslizamientos basales, de hasta tamaño medio y, localmente, pueden llegar hasta tamaño grande (con capacidad de enterrar a un grupo de montañeros). En la superficie del manto, actualmente, se ha formado escarcha y en su encima se pueden formar nuevas placas, con el viento fuerte del Oeste. También hay alguna capa débil enterrada que puede llegar a colapsar. Estas placas las encontraremos sobre todo por encima del límite del bosque y en cualquier orientación, preferentemente, en Norte y Este. Pueden ser de tamaño medio, capacidad de enterrar a una persona, o incluso a un grupo de personas en caso de capas débiles.

Distribución del manto nivoso

Hay nieve en el suelo a 1.000 m. El manto es esquiable por encima de unos 1.500 m. Los espesores a unos 2.200 m rondan los 100-135 cm en el norte de Arán y 140-190 cm en la Franja Norte Pallaresa y en el sur de Aran, y son superiores a los normales por estas fechas.

Tendencia para las próximas 48-72h

Seguirán los aludes de nieve húmeda, sobre todo en laderas con fuerte inclinación y en solanas. Peligro ESTACIONARIO.

El próximo boletín será emitido el día 2026-02-10

5 MUY FUERTE	4 FUERTE	3 NOTABLE	2 LIMITADO	1 DÉBIL

EAWS EUROPEAN AVALANCHE WARNING SERVICES

ICGC Institut Cartogràfic i Geològic de Catalunya

meteo.cat Servei Meteorològic de Catalunya

Boletín de peligro de aludes Ribagorçana - Vall Fosca Del 09/02/2026 al 10/02/2026

(Válido fuera pistas de esquí y zonas no controladas)

LIMITADO (2) por la mañana. NOTABLE (3), a partir de mediodía.

Situación primaria

Nieve venteada

Distribución

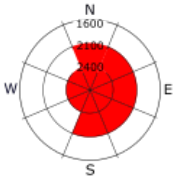

Tamaño

Origen

Tendencia

Situación secundaria

Nieve húmeda

Distribución

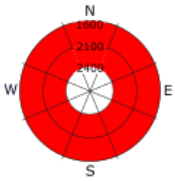

Tamaño

Origen

Tendencia

Estado del manto nivoso

Encontramos nieve venteada, con escarcha de superficie, que se alterna con grano fino, formas mixtas y costras. En todo el sector hay placas de viento por encima de los 2.300-2.400 m, en todas orientaciones, pero en especial en vertiente E y SE. A estas placas deberemos sumarle las nuevas que se formarán con el viento previsto del Oeste y del Noroeste, que con las nevadas previstas, pueden quedar tapadas y ser difíciles de detectar. Las más sensibles y frágiles estarán por encima de los 2.500 my podrán caer fácilmente al paso de un montañero y alcanzar tamaño suficiente para enterrar a una persona. Durante la tarde el problema predominante será el de la nieve húmeda. Los aludes serán más probables durante la tarde del martes, y caerán de forma natural con el humedecimiento previsto y en momentos en que precipite lluvia. Llegarán hasta tamaño medio (con capacidad de enterrar a una persona) y se darán, sobre todo, en pendientes fuertemente inclinadas.

Distribución del manto nivoso

Hay nieve en el suelo a 1.500 m. El manto es esquiable por encima de unos 1500-1600 m. Los grosores alcanzan los 130-160 cm. Estos valores son muy superiores a los normales en la época.

Tendencia para las próximas 48-72h

Seguirán las purgas de nieve húmeda, sobre todo en laderas con fuerte inclinación. Peligro ESTACIONARIO.

El próximo boletín será emitido el día 2026-02-10

5 MUY FUERTE	4 FUERTE	3 NOTABLE	2 LIMITADO	1 DÉBIL

EAWS EUROPEAN AVALANCHE WARNING SERVICES

ICGC Institut Cartogràfic i Geològic de Catalunya

meteo.cat Servei Meteorològic de Catalunya

Boletín de peligro de aludes Pallaresa
Del 09/02/2026 al 10/02/2026

(Válido fuera pistas de esquí y zonas no controladas)

LIMITADO (2) por la mañana. NOTABLE (3), a partir de mediodía.

Situación primaria

Nieve venteada

Distribución

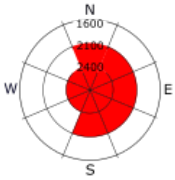

Tamaño

Origen

Tendencia

Situación secundaria

Nieve húmeda

Distribución

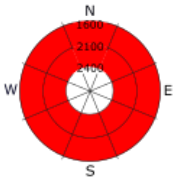

Tamaño

Origen

Tendencia

Estado del manto nivoso

Encontramos nieve venteada, con escarcha de superficie, que se alterna con grano fino, formas mixtas y costras. En todo el sector hay placas de viento por encima de los 2.300-2.400 m, en todas orientaciones, pero en especial en vertiente E y SE. A estas placas deberemos sumarle las nuevas que se formarán con el viento previsto del Oeste y del Noroeste, que con las nevadas previstas, pueden quedar tapadas y ser difíciles de detectar. Las más sensibles y frágiles estarán por encima de los 2.500 my podrán caer fácilmente al paso de un montañero y alcanzar tamaño suficiente para enterrar a una persona. Durante la tarde el problema predominante será el de la nieve húmeda. Los aludes serán más probables durante la tarde del martes, y caerán de forma natural con el humedecimiento previsto y en momentos en que precipite lluvia. Llegarán hasta tamaño medio (con capacidad de enterrar a una persona) y se darán, sobre todo, en pendientes fuertemente inclinadas.

Distribución del manto nivoso

Hay nieve desde los 1600 m. Los espesores en cotas altas y medias superan los 140-150 cm. Estos valores son superiores a los normales para la época.

Tendencia para las próximas 48-72h

Seguirán las purgas de nieve húmeda, sobre todo en laderas con fuerte inclinación. Peligro ESTACIONARIO.

El próximo boletín será emitido el día 2026-02-10

5 MUY FUERTE	4 FUERTE	3 NOTABLE	2 LIMITADO	1 DÉBIL

EAWS EUROPEAN AVALANCHE WARNING SERVICES

ICGC Institut Cartogràfic i Geològic de Catalunya

Servei Meteorològic de Catalunya

Boletín de peligro de aludes Perafita-Puigpedrós Del 09/02/2026 al 10/02/2026

(Válido fuera pistas de esquí y zonas no controladas)

LIMITADO (2) por la mañana. NOTABLE (3), a partir de mediodía.

Situación primaria

Nieve venteada

Distribución

Tamaño

Origen

Tendencia

Situación secundaria

Nieve húmeda

Distribución

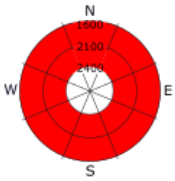

Tamaño

Origen

Tendencia

Estado del manto nivoso

En la superficie del manto observamos escarcha y por debajo nieve venteada que se alterna con grano fino, formas mixtas y costras. Encontramos algún cristal facetado, justo donde el manto se ha enfriado más. El principal problema para el martes por la mañana serán las placas de viento. A las ya existentes deberemos sumarle las nuevas que se formarán con los nuevos chubascos y el viento previsto del Oeste y del Noroeste. Las más sensibles y frágiles estarán por encima de los 2.400 my podrán caer fácilmente al paso de un montañero y alcanzar tamaño suficiente para enterrar a una persona. Durante la tarde del martes el problema predominante pasará a ser de nieve húmeda. Los aludes caerán de forma natural con el humedecimiento previsto y en momentos en que precipite lluvia. Llegarán hasta tamaño medio (con capacidad de enterrar a una persona) y se darán, sobre todo, en pendientes fuertemente inclinadas.

Distribución del manto nivoso

Hay nieve en el suelo por encima de 1.400-1500 m. Sin embargo, el manto es esquiable por encima de 1.500-1.600 m. Los grosores alcanzan los 130-150 cm a 2.200 m. Son grosores muy por encima de los habituales por la época.

Tendencia para las próximas 48-72h

Seguirán las purgas de nieve húmeda, sobre todo en laderas con fuerte inclinación. Peligro ESTACIONARIO.

El próximo boletín será emitido el día 2026-02-10

5 MUY FUERTE	4 FUERTE	3 NOTABLE	2 LIMITADO	1 DÉBIL

EAWS EUROPEAN AVALANCHE WARNING SERVICES

ICGC Institut Cartogràfic i Geològic de Catalunya

meteo.cat Servei Meteorològic de Catalunya

Boletín de peligro de aludes
Vessant Nord Cadí-Moixeró
Del 09/02/2026 al 10/02/2026

(Válido fuera pistas de esquí y zonas no controladas)

LIMITADO (2), por la mañana.
NOTABLE (3), por la tarde.

Situación primaria

Nieve venteada

Distribución

Tamaño

Origen

Tendencia

Situación secundaria

Nieve húmeda

Distribución

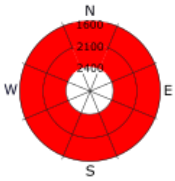

Tamaño

Origen

Tendencia

Estado del manto nivoso

Las nevadas con viento han formado placas de viento al abrigo del viento de componente W. Por encima de los 2300-2400 m, el manto nivoso está constituido por placas que pueden caer al paso de un montañero y alcanzar tamaño suficiente para enterrar a una persona. Por lo general, se encuentran en laderas E, N y en zonas resguardadas del viento de W. Las nuevas que se puedan formar pueden hacerlo sobre escarcha. Durante la tarde del martes el problema predominante pasará a ser de nieve húmeda. Los aludes caerán de forma natural con el humedecimiento previsto y en momentos en que precipite lluvia. Llegarán hasta tamaño medio (con capacidad de enterrar a una persona) y se darán, sobre todo, en pendientes fuertemente inclinadas.

Distribución del manto nivoso

Hay nieve desde 1.200-1300 m en norte y desde 1.400-1500 m en sur, esquiable por encima de unos 1.600 m. Los grosores están alrededor de 155-165 cm a 2.200 m. Estos valores son muy excedentarios para la época del año.

Tendencia para las próximas 48-72h

Seguirán las purgas de nieve húmeda, sobre todo en laderas con fuerte inclinación. Peligro ESTACIONARIO.

El próximo boletín será emitido el día 2026-02-10

5 MUY FUERTE	4 FUERTE	3 NOTABLE	2 LIMITADO	1 DÉBIL

EAWS EUROPEAN AVALANCHE WARNING SERVICES

ICGC Institut Cartogràfic i Geològic de Catalunya

Servei Meteorològic de Catalunya meteo.cat

Boletín de peligro de aludes Prepirineu
Del 09/02/2026 al 10/02/2026

(Válido fuera pistas de esquí y zonas no controladas)

LIMITADO (2), por la mañana. NOTABLE (3), a partir de mediodía.

Situación primaria

Nieve venteada

Distribución

Tamaño

Origen

Tendencia

Situación secundaria

Nieve húmeda

Distribución

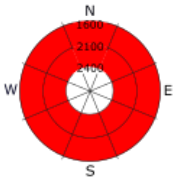

Tamaño

Origen

Tendencia

Estado del manto nivoso

Las nevadas con viento de los últimos días han formado placas de viento al abrigo del viento de componente W. Por encima de los 2300-2400 m, el manto nivoso está constituido por placas que pueden caer al paso de un montañero y alcanzar tamaño suficiente para enterrar a una persona. Por lo general, se encuentran en laderas E, N y en zonas resguardadas del viento de W. Las nuevas que se puedan formar pueden hacerlo sobre escarcha. Durante la tarde del martes el problema predominante pasará a ser de nieve húmeda. Los aludes caerán de forma natural con el humedecimiento previsto y en momentos en que precipite lluvia. Llegarán hasta tamaño medio (con capacidad de enterrar a una persona) y se darán, sobre todo, en pendientes fuertemente inclinadas.

Distribución del manto nivoso

Hay nieve desde 1400-1500 m. El manto es esquiable a partir de 1600 m. Los grosores están alrededor de 110-130 cm a unos 2.200 m y son superiores a los habituales.

Tendencia para las próximas 48-72h

Seguirán las purgas de nieve húmeda, sobre todo en laderas con fuerte inclinación. Peligro ESTACIONARIO.

El próximo boletín será emitido el día 2026-02-10

5 MUY FUERTE	4 FUERTE	3 NOTABLE	2 LIMITADO	1 DÉBIL

EAWS EUROPEAN AVALANCHE WARNING SERVICES

ICGC Institut Cartogràfic i Geològic de Catalunya

Servei Meteorològic de Catalunya meteo.cat

Boletín de peligro de aludes Ter-Freser
Del 09/02/2026 al 10/02/2026

(Válido fuera pistas de esquí y zonas no controladas)

LIMITADO (2), por la mañana.
NOTABLE (3), por la tarde

Situación primaria

Nieve venteada

Distribución

Tamaño

Origen

Tendencia

Situación secundaria

Nieve húmeda

Distribución

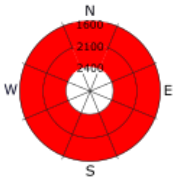

Tamaño

Origen

Tendencia

Estado del manto nivoso

El problema predominante es de las placas de viento. En todo el sector hay placas por encima de los 2.300-2.400 m, en todas orientaciones, pero en especial en vertiente E y SE. A estas placas formadas días atrás deberemos sumar las nuevas que se formarán con los nuevos chubascos previstos y el viento previsto del Oeste y del Noroeste. Estas placas pueden caer a nuestro paso y alcanzar tamaño suficiente para enterrar a una persona. Se encuentran especialmente en ladera E, N y en algunas zonas S resguardadas del viento de W. Por debajo de los 2300 m el manto nivoso se ha ido endureciendo. Durante la tarde el problema predominante será el de la nieve húmeda. Los aludes serán más probables durante la tarde del martes, y caerán de forma natural con el humedecimiento previsto y en momentos de lloviznas. en caso de que se desencadenen, llegarán hasta tamaño medio (con capacidad de enterrar a una persona) y se darán, sobre todo, en pendientes fuertemente inclinadas. Localmente,

Distribución del manto nivoso

El manto nivoso presenta grosores muy excedentarios para la época del año. En lugares no afectados por el viento, los espesores oscilan entre 100-140 cm a unos 2.000 m, siendo esquiable a partir de unos 1.500 m.

Tendencia para las próximas 48-72h

Seguirán las purgas de nieve húmeda, sobre todo en laderas con fuerte inclinación. Peligro ESTACIONARIO.

El próximo boletín será emitido el día 2026-02-10

5 MUY FUERTE	4 FUERTE	3 NOTABLE	2 LIMITADO	1 DÉBIL

EAWS EUROPEAN AVALANCHE WARNING SERVICES