MINISTERO DELLA DIFESA

meteomont Servizio Nazionale di previsione neve e valanghe

EAWS EUROPEAN AVALANCHE WARNING SERVICES

CARABINIERI

PREALPI LOMBARDE

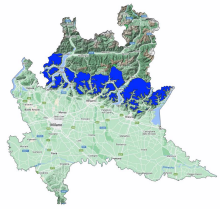

Bollettino Valanghe N. 339/2026 del 09/02/2026 ore 14.00
Validità 48 ore prossima emissione 10/02/2026

A cura del Servizio METEOMONT dell'ARMA dei CARABINIERI
In collaborazione con Servizio Meteorologico dell'Aeronautica militare

SITUAZIONE alle 14:00 del 09/02/2026

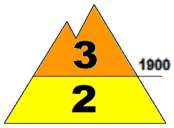

SITUAZIONE TIPO: strato debole persistente basale.

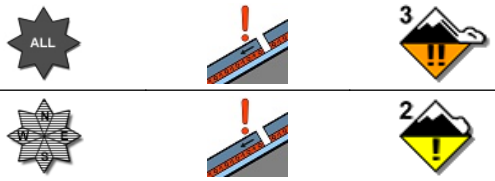

SITUAZIONE TIPO: strato debole persistente basale.

Quota neve (mslm)	Nord	Sud
	1200 - 1400	1000 - 1200

Altezza Neve (cm)	Neve al suolo	Neve Fresca	Quota (mslm)
	67	2	1724
	33	0	1445

VALANGHE OSSERVATE: -.

PREVISIONI 10/02/2026

GRADO DI PERICOLO: MARCATO 3

SITUAZIONE TIPO: strato debole persistente basale.

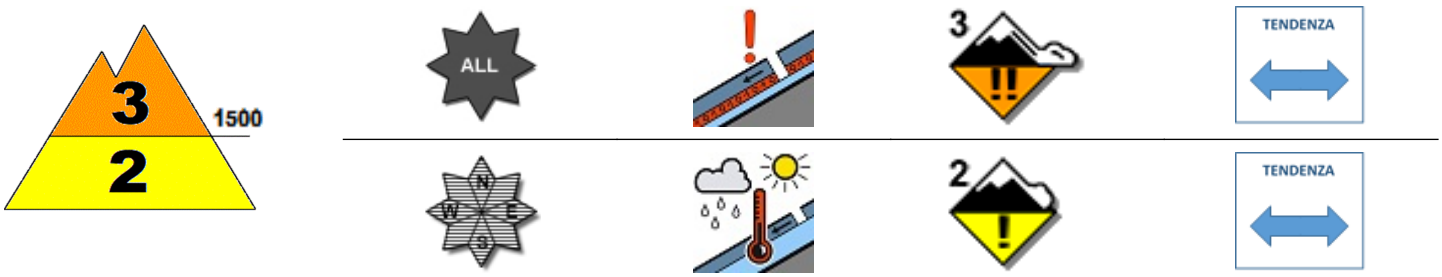

SITUAZIONE TIPO: pioggia su neve.

MANTO NEVOSO: La stabilità del manto nevoso è molto scarsa su molti punti (aree) per tutte le esposizioni al di sopra di 1500 mslm, possibili valanghe di dimensioni medie.
La stabilità del manto nevoso è scarsa su alcuni punti (aree) per isolati pendii al di sotto di 1500 mslm, possibili valanghe di dimensioni medie.

AVVERTENZE

In considerazione delle avverse condizioni meteorologiche previste, e della scarsa visibilità, risulterà difficoltosa l'individuazione dell'itinerario e della valutazione del singolo pendio.

SCALA EUROPEA DEL GRADO DI PERICOLO VALANGHE

5 - MOLTO FORTE | 4 - FORTE | 3 - MARCATO | 2 - MODERATO | 1 - DEBOLE | NO NEVE | NO INFO

LEGENDA PROBLEMA

NEVE FRESCA | LASTRONI DA VENTO | STRATI DEBOLI PERSISTENTI | NEVE BAGNATA | SLITTAMENTO | CORNICI | NESSUN PROBLEMA VALANGHIVO EVIDENTE | NO_INFO

Bollettino realizzato su scala sinottica-regionale (standard EAWS). La sua valutazione non può escludere in alcun modo la necessità di una seria e capace valutazione locale del pericolo (singolo pendio) che può essere anche sensibilmente diverso. Le previsioni meteorologiche sono relative all'orario UTC (per l'Italia +1 in inverno e +2 in estate).

MINISTERO DELLA DIFESA

meteomont
Servizio Nazionale di previsione neve e valanghe

EAWS EUROPEAN AVALANCHE WARNING SERVICES

CARABINIERI

PREALPI LOMBARDE

PREVISIONE METEO

Quota		10/02/2026 h6:00	10/02/2026 h12:00	10/02/2026 h18:00
1000	Venti	02 Nodi da S-Est	01 Nodi da Sud	01 Nodi da S-Est
	Temperature	-04 °C	-02 °C	-02 °C
	Temp.percepita	-4 °C	-2 °C	-2 °C
2000	Venti	03 Nodi da Sud	02 Nodi da Sud	02 Nodi da Sud
	Temperature	-05 °C	-04 °C	-04 °C
	Temp.percepita	-8 °C	-4 °C	-4 °C
3000	Venti	06 Nodi da Ovest	06 Nodi da S-Ovest	05 Nodi da Ovest
	Temperature	-11 °C	-10 °C	-08 °C
	Temp.percepita	-17 °C	-16 °C	-13 °C
Zero termico		1000-1200 m.	1300-1500 m.	1100-1300 m.
Fenomeno		—		—
Stato del cielo				

LEGENDA FENOMENI

— Assenza Fenomeni · Nebbia · Foschia · Pioggia debole · Pioggia moderata · Pioggia forte · Temporali

Nevicata debole · Nevicata moderata · Nevicata forte

STATO DEL CIELO

Sereno · Poco nuvoloso · Nuvoloso · Molto nuvoloso · Coperto

Parametri meteonivometrici registrati presso i campi di rilevamento il 09/02/2026.

Località	Comune	Quota (m.s.l.m.)	Altezza neve (cm)	Neve caduta nelle 24 ore (cm)	Temp. Min (°C)	Temp. Max (°C)	Condizioni del tempo
PIANI DI BOBBIO	Barzio (LC)	1724	67	2	N.P.	N.P.	Assenza di precipitazioni
PIAN DELLE BETULLE	Margno (LC)	1445	33	0	-3	+6	Precipitazioni all'orizzonte (pioggia, neve, grandine, temporali) ma non sulla stazione

(*) Rilievi fuori campo

L'INFORMAZIONE E' PREVENZIONE - LEGGI L'ATTUALE GRADO DI PERICOLO VALANGHE!

IL CAPO DEL CENTRO NAZIONALE METEOMONT
(Ten. Col. RFI Emanuela Gini)
FIRMA AUTOGRAFA OMESSA AI SENSI
DELL'ART.3 DEL D.LGS N.39/1993