TERMINILLO MONTI REATINI E LAGA OVEST

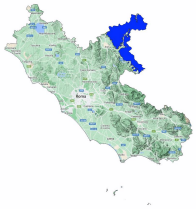

Bollettino Valanghe N. 282/2026 del 09/02/2026 ore 14.00
Validità 48 ore prossima emissione 10/02/2026

A cura del Servizio METEOMONT dell'ARMA dei CARABINIERI
In collaborazione con Servizio Meteorologico dell'Aeronautica militare

SITUAZIONE alle 14:00 del 09/02/2026

SITUAZIONE TIPO: neve pallottolare sepolta.

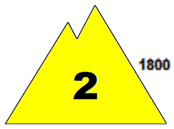



SITUAZIONE TIPO: pioggia su neve.

Quota neve (mslm)	Nord	Sud
	1400 - 1600	1600

Altezza Neve (cm)	Neve al suolo	Neve Fresca	Quota (mslm)
	059	003	1700
	015	000	1350

VALANGHE OSSERVATE: Alcune valanghe di medie dimensioni, Valanghe a lastroni di fondo.

PREVISIONI 10/02/2026

GRADO DI PERICOLO: MODERATO 2

SITUAZIONE TIPO: neve pallottolare sepolta.

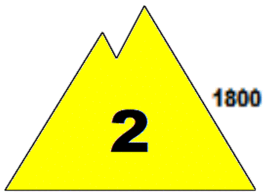



SITUAZIONE TIPO: pioggia su neve.

MANTO NEVOSO: La stabilità del manto nevoso è scarsa su molti punti (aree) per versanti da nord ovest a sud est compresi al di sopra di 1800 mslm, possibili valanghe di dimensioni medie.
La stabilità del manto nevoso è scarsa su alcuni punti (aree) per isolati pendii al di sotto di 1800 mslm, possibili valanghe di dimensioni medie.

AVVERTENZE

In considerazione dei recenti apporti di neve fresca, è richiesta un'ottima valutazione locale della stabilità ed individuazione dell'itinerario.

SCALA EUROPEA DEL GRADO DI PERICOLO VALANGHE

5 - MOLTO FORTE | 4 - FORTE | 3 - MARCATO | 2 - MODERATO | 1 - DEBOLE | NO NEVE | NO INFO

LEGENDA PROBLEMA

NEVE FRESCA | LASTRONI DA VENTO | STRATI DEBOLI PERSISTENTI | NEVE BAGNATA | SLITTAMENTO | CORNICI | NESSUN PROBLEMA VALANGHIVO EVIDENTE | NO_INFO

Bollettino realizzato su scala sinottica-regionale (standard EAWS). La sua valutazione non può escludere in alcun modo la necessità di una seria e capace valutazione locale del pericolo (singolo pendio) che può essere anche sensibilmente diverso. Le previsioni meteorologiche sono relative all'orario UTC (per l'Italia +1 in inverno e +2 in estate).

TERMINILLO MONTI REATINI E LAGA OVEST

PREVISIONE METEO

Quota		10/02/2026 h6:00	10/02/2026 h12:00	10/02/2026 h18:00
1000	Venti	01 Nodi da S-Ovest	03 Nodi da S-Ovest	02 Nodi da S-Ovest
	Temperature	+02 °C	+03 °C	+02 °C
	Temp.percepita	2 °C	2 °C	2 °C
2000	Venti	03 Nodi da Ovest	06 Nodi da S-Ovest	06 Nodi da S-Ovest
	Temperature	-02 °C	-02 °C	-02 °C
	Temp.percepita	-4 °C	-6 °C	-6 °C
3000	Venti	07 Nodi da Ovest	07 Nodi da Ovest	10 Nodi da Ovest
	Temperature	-08 °C	-08 °C	-07 °C
	Temp.percepita	-14 °C	-14 °C	-14 °C
Zero termico		1700-1900 m.	1600-1800 m.	1600-1800 m.
Fenomeno		—	—	
Stato del cielo				

LEGENDA FENOMENI

— Assenza Fenomeni · Nebbia · Foschia · Pioggia debole · Pioggia moderata · Pioggia forte · Temporali

Nevicata debole · Nevicata moderata · Nevicata forte

STATO DEL CIELO

Sereno · Poco nuvoloso · Nuvoloso · Molto nuvoloso · Coperto

Parametri meteonivometrici registrati presso i campi di rilevamento il 09/02/2026.

Località	Comune	Quota (m.s.l.m.)	Altezza neve (cm)	Neve caduta nelle 24 ore (cm)	Temp. Min (°C)	Temp. Max (°C)	Condizioni del tempo
PESCHIERE	Amatrice (RI)	1270	0	0	-1	+8	Assenza di precipitazioni
M. CAIDURO	Cittareale (RI)	1300	9	2	0	+7	Assenza di precipitazioni
VALLONINA	Leonessa (RI)	1350	15	0	-1	+8	Assenza di precipitazioni
GIRO DELL'ANELLO - VILLA CHIGI *	Rieti (RI)	1771	59	3	-2	+4	Assenza di precipitazioni

(*) Rilievi fuori campo

L'INFORMAZIONE E' PREVENZIONE - LEGGI L'ATTUALE GRADO DI PERICOLO VALANGHE!

IL CAPO DEL CENTRO NAZIONALE METEOMONT
(Ten. Col. RFI Emanuela Gini)
FIRMA AUTOGRAFA OMESSA AI SENSI
DELL'ART.3 DEL D.LGS N.39/1993

Bollettino realizzato su scala sinottica-regionale (standard EAWS). La sua valutazione non può escludere in alcun modo la necessità di una seria e capace valutazione locale del pericolo (singolo pendio) che può essere anche sensibilmente diverso. Le previsioni meteorologiche sono relative all'orario UTC (per l'Italia +1 in inverno e +2 in estate).