Bulletin d'estimation du risque d'avalanche

(valable en dehors des pistes balisées et ouvertes)

MASSIF : Renoso Incudine

Rédigé le lundi 9 février 2026 à 15h

Estimation des risques pour le : MARDI 10 FÉVRIER

COUCHES FRAGILES PERSISTANTES ENFOUIES.

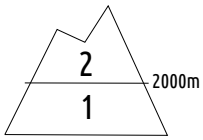

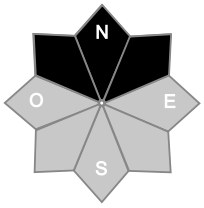

Au-dessus de 2000m indice de risque limité, plus bas indice faible.

Départs spontanés : peu probables ou superficiel en neige récente.

Déclenchements provoqués : Plaques en altitude

Indices de risque : 5 très fort - 4 fort - 3 marqué - 2 limité - 1 faible -- En noir : les pentes les plus dangereuses

Stabilité du manteau neigeux

Situation avalancheuse typique : couche fragile persistante neige ventée

Déclenchements provoqués : Plaques en place parfois loin des crêtes formées par les épisodes successifs de vent fort d'ouest à sud-ouest. Plaques dures juste sous les crêtes balayées par le vent, friables en altitude dans les zones de redépose un peu plus abrités. Elles se stabilisent peu à peu par tassement et deviennent plus difficilement déclenchables générant des avalanches de taille moyenne (taille 2). Dans les secteurs froids bien ombragés au-dessus de 2000m, une avalanche de grande taille (taille 3) reste non exclue, par sollicitation de couches fragiles persistantes dans le manteau neigeux. Elles sont difficilement déclenchables, car maintenant enfouies assez profondément. Leur sollicitation est parfois possible là où l'épaisseur de neige est moins importante (abords des combes, ruptures de pente....).
En dessous de 2000 m, les pluies des jours précédents et le tassement ont contribué à stabiliser le manteau. Les plaques formées par la suite sont généralement peu épaisses.
Départs spontanés : Quelques coulées voire avalanches de neige récente de taille petites à moyenne sont attendues à la faveur des éclaircies.

Qualité de la neige

Qualification de l'enneigement : l'enneigement est excellent pour la saison à toutes altitudes. On relève plus de 2 mètres dans les combes abritées.
Limite d'enneigement skiable : 1400 à 1500 m.
État de la neige : Le manteau neigeux a connu un cycle dégel/regel sous 1800m voire plus haut en versants sud. La neige est souvent dure et portante en dessous de 2000 m environ. Au-dessus de 2000m en secteurs ombragés ou à soleil plus rasant, La neige reste sèche, légère et profonde à l'abri du vent d'ouest et de la neige très changeante (dure, carton, regelée) dans les secteurs ventés. Au-dessus de 1600m on peut trouver une dizaine de cm de neige fraîche. Corniches et accumulations parfois volumineuses en place. Par endroits on peut même apercevoir l'effet du Sirocco de la semaine dernière avec de la neige colorée.

Aperçu météo pour le mardi 10 février

	nuit	matin	après-midi	soir
Pluie-Neige			1 800 m	2 100 m
Iso 0 °C	1 800 m	1 900 m	2 100 m	2 400 m
Vent 1500 m	→ 30 km/h	↗ 30 km/h	→ 40 km/h	↗ 50 km/h
Vent 2000 m	→ 30 km/h	→ 30 km/h	→ 50 km/h	→ 60 km/h

Épaisseur de neige hors-piste

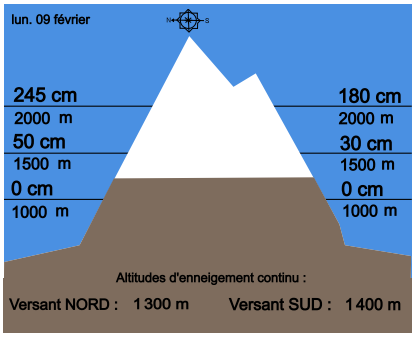

Précipitations à 1800 m

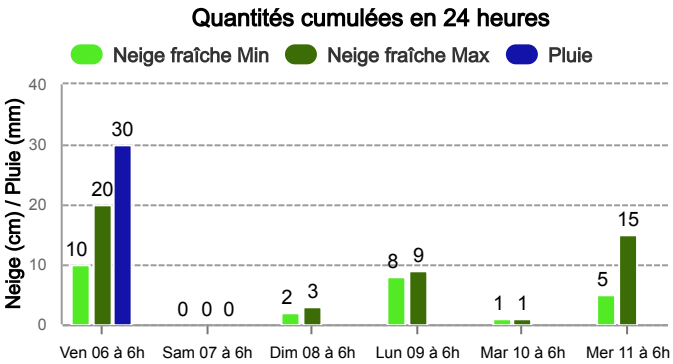

Tendance du mercredi 11 février

Indice de risque marqué

Risque en hausse avec les pluies attendues sous 2000/2200m et la neige ventée au-dessus.

Pour consulter la vigilance en cours, veuillez vous rendre sur le site https://vigilance.meteofrance.fr/fr

Météo-France - 73 avenue de Paris, 94165 Saint-Mandé cedex - Contact : contact@meteo.fr

Rédigé par Météo-France avec la contribution des observateurs du réseau nivo-météorologiques. Partenariat : ANMSM (Maires de Stations de Montagne), DSF (Domaines Skiables de France), ADSP (Directeurs de Pistes et de la Sécurité des Stations de Sports d'Hiver) et autres acteurs de la montagne.

Bulletin neige & avalanches par téléphone au 0 892 68 10 20 Service 0,35 € / min + prix appel

RÉPUBLIQUE FRANÇAISE
Liberté Égalité Fraternité

METEO FRANCE
À VOS CÔTÉS, DANS UN CLIMAT QUI CHANGE

Bulletin d'estimation du risque d'avalanche

(valable en dehors des pistes balisées et ouvertes)

MASSIF : Renoso Incudine

Rédigé le lundi 9 février 2026 à 15h

Conditions nivo-météo des 7 derniers jours

	mar. 03/02				mer. 04/02				jeu. 05/02				ven. 06/02				sam. 07/02				dim. 08/02				lun. 09/02			
	03h	09h	15h	21h	03h	09h	15h	21h	03h	09h	15h	21h	03h	09h	15h	21h	03h	09h	15h	21h	03h	09h	15h	21h	03h	09h	15h	21h
Météo																												
Vent (km/h)	55	45	10	20	15	60	40	20	30	60	45	70	85	70	60	45	55	55	45	50	50	15	30	15	10	10	20	20
à 2000m	↗	→	↑	←	↗	↘	→	↑	→	→	→	→	→	→	→	→	→	↗	→	→	→	↖	↑	↗	↑	→	→	↘
Vent (km/h)	35	35	10	15	20	50	30	10	25	40	35	55	95	80	75	60	60	45	65	50	60	15	25	15	15	15	15	10
à 1500m	↑	→	↑	↓	↗	→	→	↗	→	→	↗	↗	→	→	→	→	→	→	→	→	→	↖	←	←	↗	↘	→	→

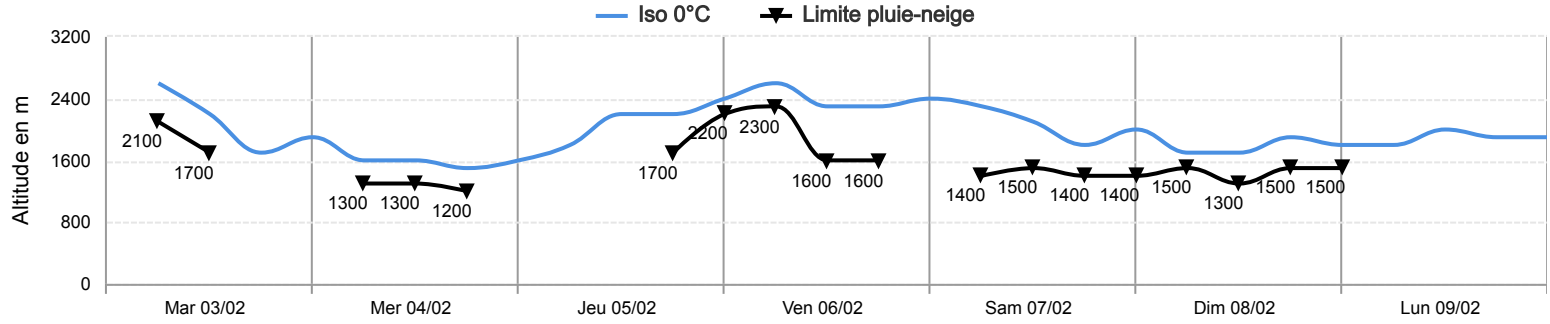

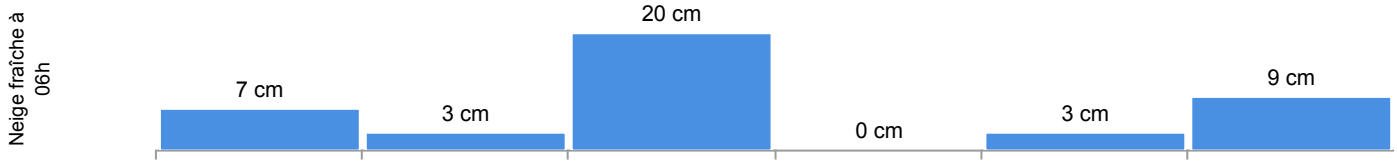

Risque d'avalanche							
	mar. 03/02	mer. 04/02	jeu. 05/02	ven. 06/02	sam. 07/02	dim. 08/02	lun. 09/02

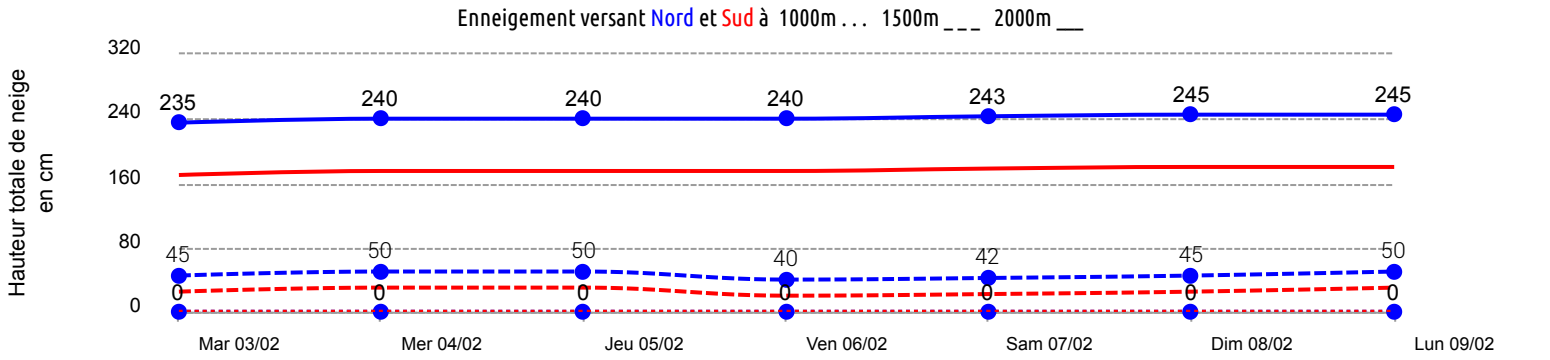

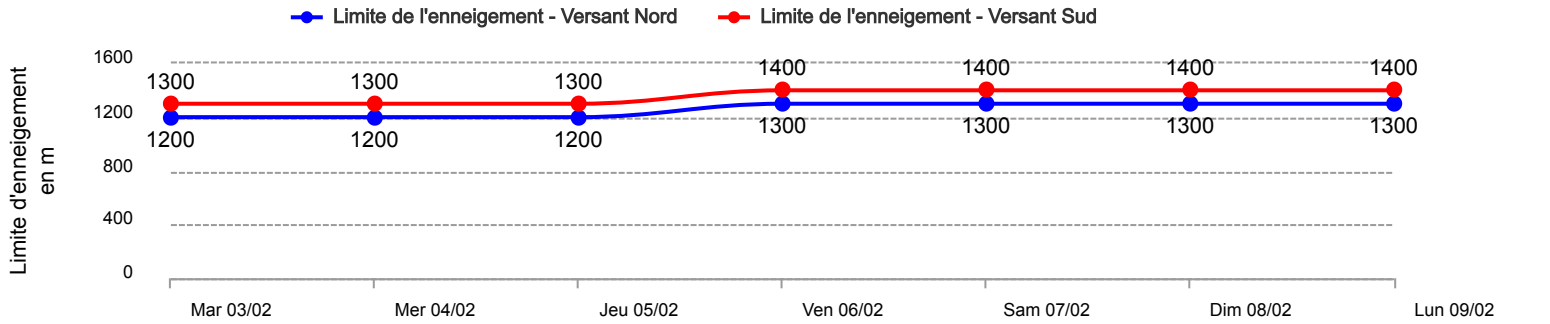

Pour consulter la vigilance en cours, veuillez vous rendre sur le site https://vigilance.meteofrance.fr/fr

Météo-France - 73 avenue de Paris, 94165 Saint-Mandé cedex - Contact : contact@meteo.fr

Rédigé par Météo-France avec la contribution des observateurs du réseau nivo-météorologiques. Partenariat : ANMSM (Maires de Stations de Montagne), DSF (Domaines Skiables de France), ADSP (Directeurs de Pistes et de la Sécurité des Stations de Sports d'Hiver) et autres acteurs de la montagne.

Bulletin neige & avalanches par téléphone au
0 892 68 10 20 Service 0,35 € / min + prix appel