Bulletin d'estimation du risque d'avalanche

(valable en dehors des pistes balisées et ouvertes)

MASSIF : Belledonne

Rédigé le lundi 9 février 2026 à 16h

Estimation des risques pour le : MARDI 10 FÉVRIER

QUELQUES INSTABILITES EN JOURNEE DANS LA NEIGE FRAICHE / VENTEE. NOMBREUSES NOUVELLES PLAQUES EN SOIREE

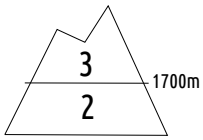

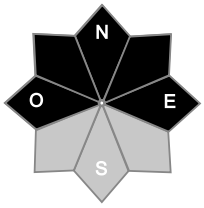

Au-dessus de 1700m indice de risque marqué, plus bas indice limité.

Départs spontanés : Rares en journée, nombreuses en soirée sous les chutes de neige et sous la pluie à plus basse altitude.

Déclenchements provoqués : Instabilités en large Nord dans la neige fraîche / ventée en journée. Plaques plus nombreuses et en tout versants sous les chutes de neige en soirée.

Indices de risque : 5 très fort - 4 fort - 3 marqué - 2 limité - 1 faible -- En noir : les pentes les plus dangereuses

Stabilité du manteau neigeux

Situation avalancheuse typique : neige ventée neige humide

En journée : Faible passage perturbé dans la nuit et en matinée de mardi, avec 5 à 10cm dés 1500m. Formation de quelques plaques sous le vent d'Ouest / Sud-Ouest.
Déclenchements provoqués : Au-desus de 1500m et surtout en large Nord, des instabilités sont présentes dans les 5 à 10cm de neige fraîche qui tombent en fin de nuit / matinée de mardi. Cette neige fraîche se dépose parfois sur de la neige encore légère en versants Nord, rendant les plaques localement très réactives. Elles restent toutefois peu épaisses (10 à 20cm dans les accumulations) et relativement peu larges.
En large Nord et dés 2000m environ, des grains anguleux sont enfouis dans le manteau. Ces couches fragiles sont difficiles à solliciter par un skieur, mais le départ d'une plaque de surface pourrait par cascade déclencher une plaque de plus grande ampleur, avec une cassure large et épaisse.
Départs spontanés : Des boulettes ou de petites coulées possibles en journée, dans la neige récente qui s'humidifie sous 1800/2000m. Au-dessus, peu probable, ou une petite coulée en neige fraîche, surtout sous le vent de Sud-Ouest.

En soirée : Perturbation active, avec 20 à 30cm en quelques heures au-dessus de 2000m, accompagnées d'un vent fort d'Ouest / Nord-Ouest. Pluies soutenues à plus basses altitude.
Départs spontanés : Au-dessus de 2000m, des **avalanches naturelles de plus en plus nombreuses au fil des chutes de neige sont attendues, souvent de tailles moyennes, parfois de grandes tailles en fin de soirée**. Elles sont plus nombreuses en large secteur Est. Sous 2000m, la pluie alourdit le manteau neigeux et provoque de nombreux départs spontanés, souvent de tailles moyennes (surtout en versants Nord où la neige est restée froide).
Déclenchements provoqués : De nouvelles plaques se forment en soirée en tout versants. Plaques dures vers les crêtes, plus poudreuses en bas de pente où le vent est plus faible. Cassures pouvant être larges et de plus en plus épaisses au fil des heures. Surtout en Est où les accumulations seront plus importantes sous le vent.

Qualité de la neige

Qualification de l'enneigement : L'enneigement est bon pour la saison en altitude, dans les combes et médiocre sous les sapins et en dessous de la moyenne montagne...

Limites skiables : vers 1100/1500 m.

Qualité de la neige mardi : Au-dessus de 1800m, 5 à 10cm de neige fraîche, parfois densifiée par le vent, notamment à l'abord des crêtes. Entre 1300 et 1800m, petite couche de neige récente humide, collant parfois aux skis. Sous-couche en poudreuse dense en versants froids, croûtée en Sud.

Aperçu météo pour le mardi 10 février

	nuit	matin	après-midi	soir

Petites chutes de neige en fin de nuit / matinée. Petites averses en journée sous un ciel couvert. Perturbation active en soirée / nuit suivante.

Pluie-Neige	1 200 m	1 400 m	1 700 m	1 900 m
Iso 0 °C	1 800 m	1 800 m	2 100 m	2 200 m
Vent 2000 m	↗ 35 km/h	↗ 25 km/h	↗ 40 km/h	↗ 50 km/h
Vent 3000 m	↗ 50 km/h	→ 40 km/h	↗ 50 km/h	→ 70 km/h

Épaisseur de neige hors-piste

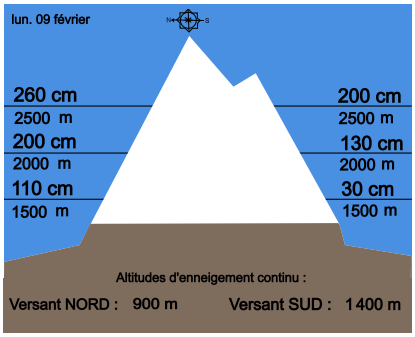

Précipitations à 1800 m

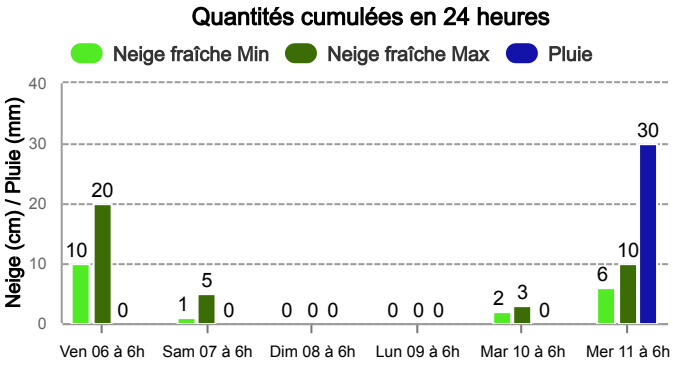

Tendance du mercredi 11 février

Indice de risque fort

Risque devenant fort dés la nuit de mardi à mercredi. Les chutes de neige se poursuivent en journée, avec une limite pluie-neige s'abaissant vers 1500m. Instabilités généralisées dans l'importante couche de neige récente. Grandes avalanches possibles.

Pour consulter la vigilance en cours, veuillez vous rendre sur le site https://vigilance.meteofrance.fr/fr

Météo-France - 73 avenue de Paris, 94165 Saint-Mandé cedex - Contact : contact@meteo.fr

Rédigé par Météo-France avec la contribution des observateurs du réseau nivo-météorologiques. Partenariat : ANMSM (Maires de Stations de Montagne), DSF (Domaines Skiables de France), ADSP (Directeurs de Pistes et de la Sécurité des Stations de Sports d'Hiver) et autres acteurs de la montagne.

Bulletin neige & avalanches par téléphone au **0 892 68 10 20** Service 0,35 € / min + prix appel

Bulletin d'estimation du risque d'avalanche

(valable en dehors des pistes balisées et ouvertes)

MASSIF : Belledonne

Rédigé le lundi 9 février 2026 à 16h

Conditions nivo-météo des 7 derniers jours

	mar. 03/02				mer. 04/02				jeu. 05/02				ven. 06/02				sam. 07/02				dim. 08/02				lun. 09/02			
	03h	09h	15h	21h	03h	09h	15h	21h	03h	09h	15h	21h	03h	09h	15h	21h	03h	09h	15h	21h	03h	09h	15h	21h	03h	09h	15h	21h
Météo																												
Vent (km/h)	100	85	75	65	50	45	20	35	35	30	45	40	40	30	25	20	15	10	5	5	15	25	20	25	30	30	35	40
à 3000m																												
Vent (km/h)	85	65	55	40	35	30	20	15	15	15	30	20	25	25	20	10	10	5	10	10	10	10	10	15	20	10	15	20
à 2000m																												

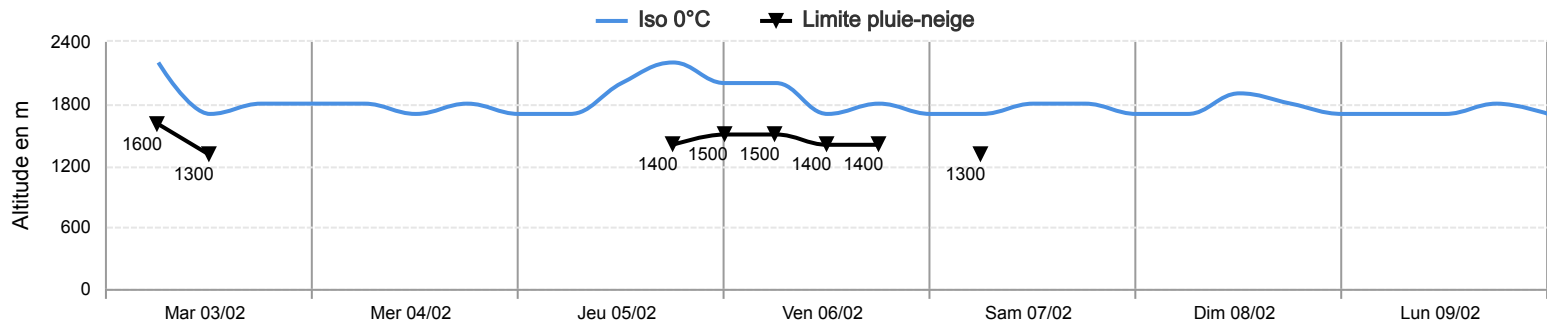

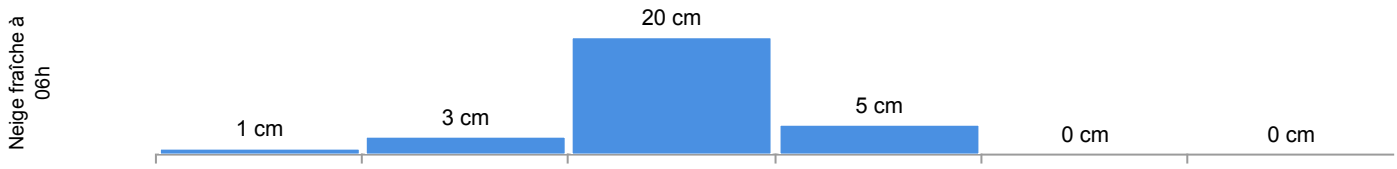

Risque d'avalanche	mar. 03/02	mer. 04/02	jeu. 05/02	ven. 06/02	sam. 07/02	dim. 08/02	lun. 09/02
	3	3	3	3	3	3	2

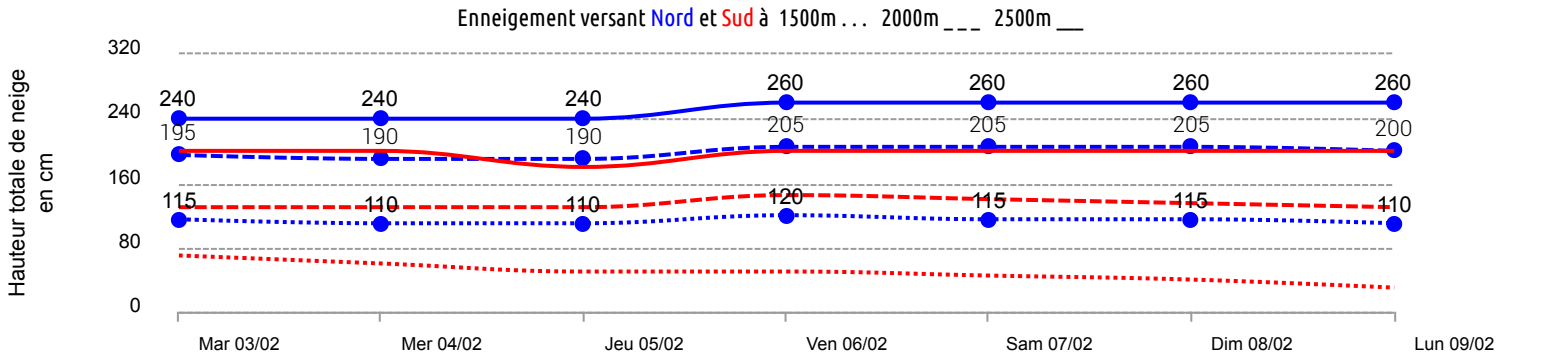

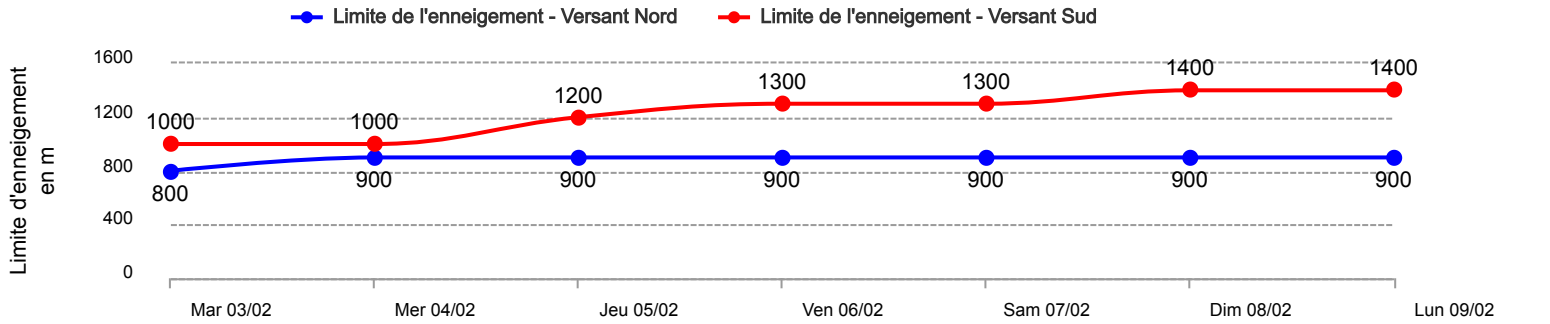

Pour consulter la vigilance en cours, veuillez vous rendre sur le site https://vigilance.meteofrance.fr/fr

Météo-France - 73 avenue de Paris, 94165 Saint-Mandé cedex - Contact : contact@meteo.fr

Bulletin neige & avalanches par téléphone au

0 892 68 10 20 Service 0,35 € / min + prix appel

Rédigé par Météo-France avec la contribution des observateurs du réseau nivo-météorologiques. Partenariat : ANMSM (Maires de Stations de Montagne), DSF (Domaines Skiables de France), ADSP (Directeurs de Pistes et de la Sécurité des Stations de Sports d'Hiver) et autres acteurs de la montagne.