RÉPUBLIQUE FRANÇAISE
*Liberté Égalité Fraternité*

METEO FRANCE
À VOS CÔTÉS, DANS UN CLIMAT QUI CHANGE

# Bulletin d'estimation du risque d'avalanche
(valable en dehors des pistes balisées et ouvertes)

# MASSIF : Cerdagne Canigou

Rédigé le lundi 9 février 2026 à 16h

## Estimation des risques pour le : MARDI 10 FÉVRIER

**PERSISTANCE DE QUELQUES INSTABILITÉS RÉSIDUELLES**

2

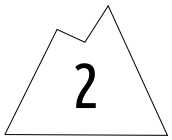


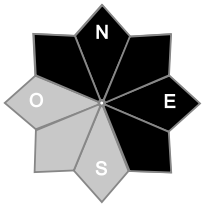


Indice de risque limité.

**Départs spontanés :** Avalanches en neige humide

**Déclenchements provoqués :** Vieilles plaques à vent juste sous les cols frontaliers mais aussi quelques plaques à vent en formation en altitude

Indices de risque : 5 très fort - 4 fort - 3 marqué - 2 limité - 1 faible -- En noir : les pentes les plus dangereuses

## Stabilité du manteau neigeux

**Situation avalancheuse typique :** neige ventée neige humide

**Déclenchements provoqués :**
* Au-dessus de 2200 m, dans les orientations nord-ouest à est, déclenchements possibles au passage d'un randonneur d'avalanches de taille moyenne (T2), voire de grande taille (T3) dans les secteurs les plus défavorables de haute montagne. En effet, des structures de plaques pas complètement stabilisées peuvent encore être présentes. D'autres, moins épaisses, mais facilement déclenchables sont en formation principalement sous les crêtes d'un large secteur Est.

**Départs spontanés :**
* Avalanches de glissement possibles en pentes très raides herbeuses ou sur des dalles rocheuses en toutes orientations en dessous de 2200 m principalemenr (Taille 1 ou 2). (observables : présence de gueules de baleine, reptations, neige dense et très humide).
* Départs ponctuels en surface (tailles1 voire 2) en neige humide avec les précipitations et les nuages.

## Qualité de la neige

**Enneigement :**
Malgré un début de fonte à basse altitude, l'enneigement est excellent et très largement excédentaire pour la saison sur le massif. La limite de skiabilité se situe vers 1300/1400 m dans les meilleures configurations.

**État de la neige :**
Au petit matin, neige déjà humide et peu portante à cause d'un mauvais regel nocturne. Poursuite de l'humidification ensuite au fil des pluies et des nuages associés.

## Aperçu météo pour le mardi 10 février

| | nuit | matin | après-midi | soir |
|---|---|---|---|---|
| Doux et humide | | | | |
| **Pluie-Neige** | 2 000 m | 2 300 m | | 2 400 m |
| **Iso 0 °C** | 2 300 m | 2 600 m | 2 900 m | 2 800 m |
| **Vent 2000 m** | 30 km/h | 30 km/h | 30 km/h | 40 km/h |
| **Vent 3000 m** | 50 km/h | 50 km/h | 55 km/h | 60 km/h |

## Épaisseur de neige hors-piste

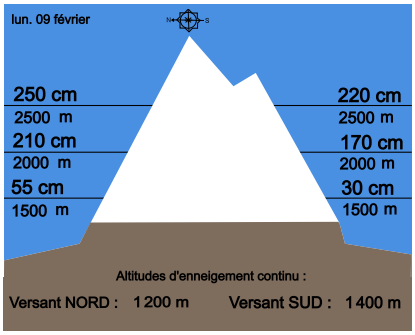


## Précipitations à 1800 m

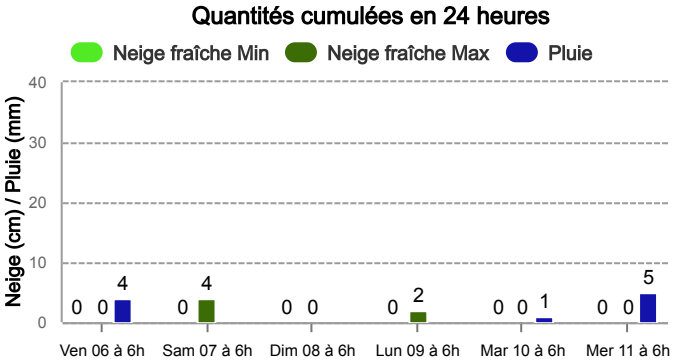


## Tendance du mercredi 11 février

2

**Indice de risque limité**

Maintien du risque limité, ou augmentation en risque modéré en foction des précipitations attendues mercredi.

Pour consulter la vigilance en cours, veuillez vous rendre sur le site https://vigilance.meteofrance.fr/fr

Météo-France - 73 avenue de Paris, 94165 Saint-Mandé cedex - Contact : contact@meteo.fr

Rédigé par Météo-France avec la contribution des observateurs du réseau nivo-météorologiques. Partenariat : ANMSM (Maires de Stations de Montagne), DSF (Domaines Skiables de France), ADSP (Directeurs de Pistes et de la Sécurité des Stations de Sports d'Hiver) et autres acteurs de la montagne.

Bulletin neige & avalanches par téléphone au
**0 892 68 10 20** Service 0,35 € / min + prix appel

RÉPUBLIQUE FRANÇAISE
*Liberté Égalité Fraternité*

METEO FRANCE
À VOS CÔTÉS, DANS UN CLIMAT QUI CHANGE

# Bulletin d'estimation du risque d'avalanche

(valable en dehors des pistes balisées et ouvertes)

# MASSIF : Cerdagne Canigou

Rédigé le lundi 9 février 2026 à 16h

## Conditions nivo-météo des 7 derniers jours

| | mar. 03/02 | | | | mer. 04/02 | | | | jeu. 05/02 | | | | ven. 06/02 | | | | sam. 07/02 | | | | dim. 08/02 | | | | lun. 09/02 | | | |
|---|---|---|---|---|---|---|---|---|---|---|---|---|---|---|---|---|---|---|---|---|---|---|---|---|---|---|---|---|
| | 03h | 09h | 15h | 21h | 03h | 09h | 15h | 21h | 03h | 09h | 15h | 21h | 03h | 09h | 15h | 21h | 03h | 09h | 15h | 21h | 03h | 09h | 15h | 21h | 03h | 09h | 15h | 21h |
| Météo | | | | | | | | | | | | | | | | | | | | | | | | | | | | |
| Vent (km/h) | 70 | 50 | 40 | 40 | 50 | 75 | 40 | 35 | 65 | 80 | 75 | 55 | 40 | 25 | 25 | 30 | 30 | 20 | 25 | 50 | 55 | 50 | 50 | 40 | 50 | 35 | 55 | 45 |
| à 3000m | | | | | | | | | | | | | | | | | | | | | | | | | | | | |
| Vent (km/h) | 45 | 25 | 25 | 20 | 25 | 45 | 25 | 25 | 45 | 60 | 55 | 40 | 25 | 15 | 15 | 20 | 20 | 15 | 15 | 40 | 45 | 40 | 35 | 25 | 30 | 20 | 25 | 20 |
| à 2000m | | | | | | | | | | | | | | | | | | | | | | | | | | | | |

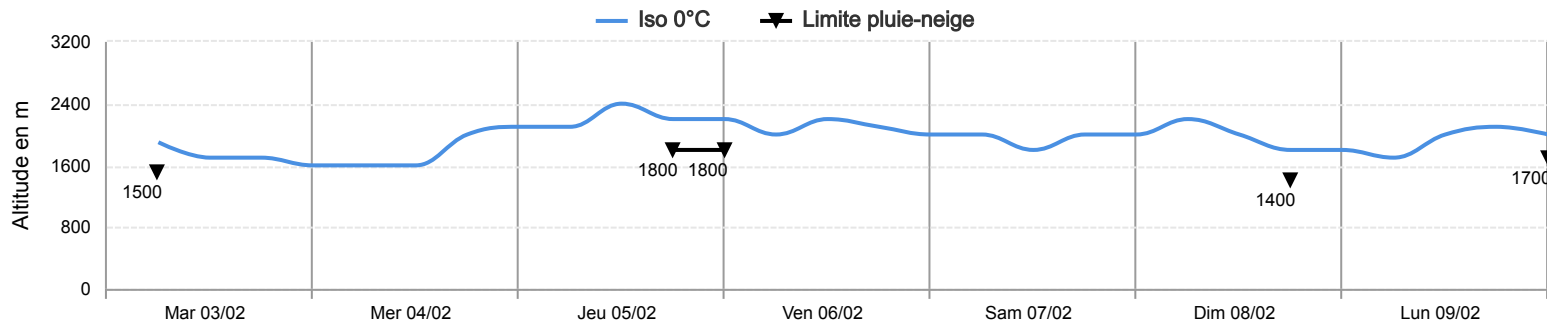


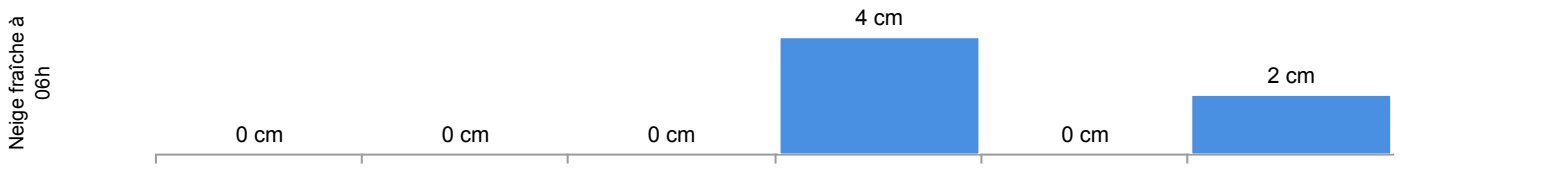


| Risque d'avalanche | mar. 03/02 | mer. 04/02 | jeu. 05/02 | ven. 06/02 | sam. 07/02 | dim. 08/02 | lun. 09/02 |
|---|---|---|---|---|---|---|---|
| | 3 | 3 | 2 | 2 | 2 | 2 | 2 |

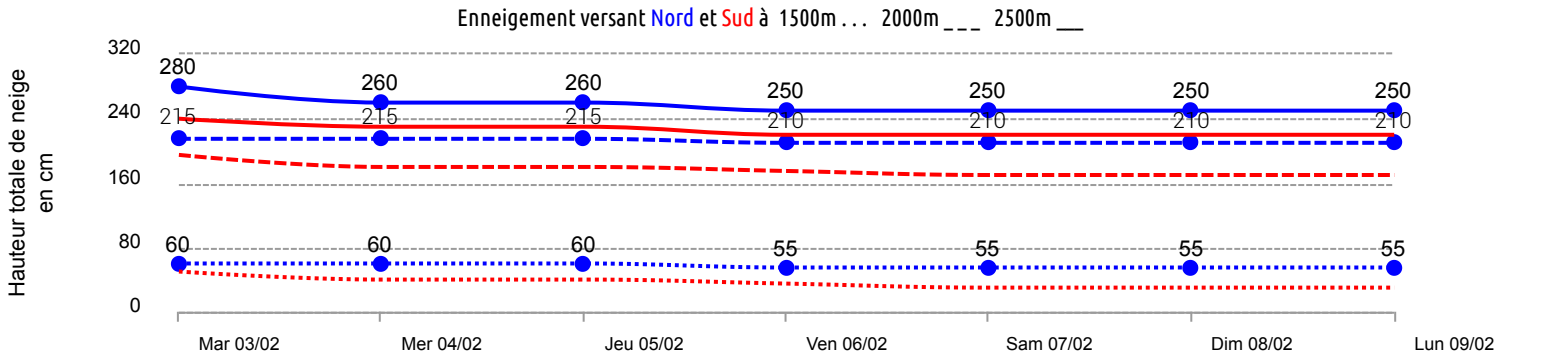


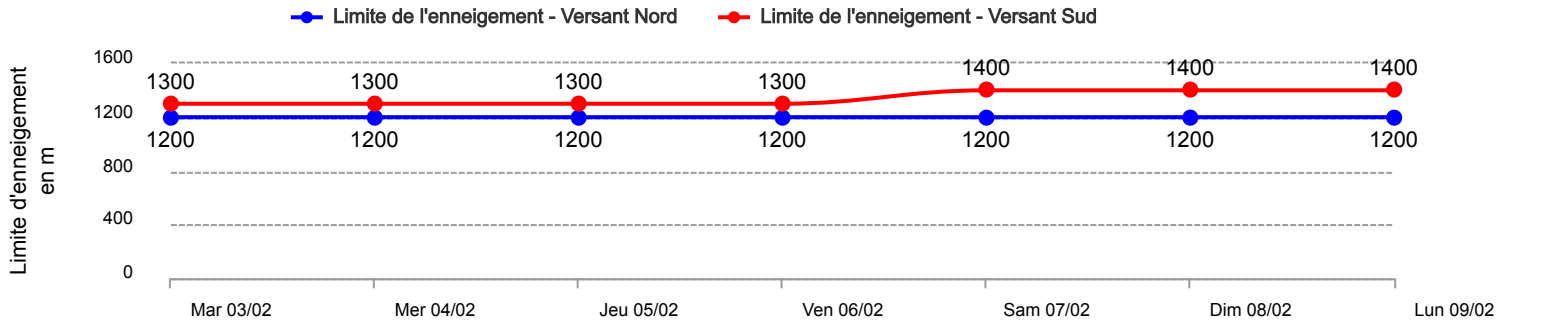


Pour consulter la vigilance en cours, veuillez vous rendre sur le site https://vigilance.meteofrance.fr/fr


Météo-France - 73 avenue de Paris, 94165 Saint-Mandé cedex - Contact : contact@meteo.fr



Rédigé par Météo-France avec la contribution des observateurs du réseau nivo-météorologiques. Partenariat : ANMSM (Maires de Stations de Montagne), DSF (Domaines Skiables de France), ADSP (Directeurs de Pistes et de la Sécurité des Stations de Sports d'Hiver) et autres acteurs de la montagne.



Bulletin neige & avalanches par téléphone au
0 892 68 10 20 Service 0,35 € / min + prix appel