Bulletin d'estimation du risque d'avalanche

(valable en dehors des pistes balisées et ouvertes)

MASSIF : Couserans

Rédigé le lundi 9 février 2026 à 16h

Estimation des risques pour le : MARDI 10 FÉVRIER

INSTABILITÉ GÉNÉRALISÉE EN NEIGE HUMIDE

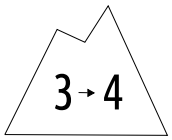

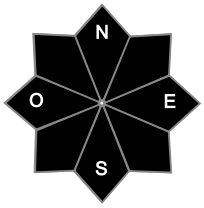

Indice de risque marqué évoluant en fort.

Départs spontanés : De plus en plus nombreux et volumineux au fil des heures

Déclenchements provoqués : Structures de plaques en altitude

Indices de risque : 5 très fort - 4 fort - 3 marqué - 2 limité - 1 faible -- En noir : les pentes les plus dangereuses

Stabilité du manteau neigeux

Situation avalancheuse typique : neige humide neige ventée

Départs spontanés :

Avec le redoux et la pluie prévue, de nombreux départs spontanés se produiront en toutes orientations en-dessous de la limite pluie/neige. Ils mobiliseront des volumes de neige de plus en plus importants au fur et à mesure de l'humidification en profondeur du manteau neigeux, notamment dans les pentes pas ou peu humidifiées jusqu'alors (au dessus de 2000m d'altitude, ainsi que dans un large secteur nord)
(observables : neige meuble, "escargots").

Des avalanches de glissement sur des pentes herbeuses/roches lisses pas encore humidifiées jusqu'au sol sont aussi à attendre dans de nouveaux secteurs (observables : large fissures, reptations).

Dans les deux cas, on observera des avalanches de taille petite à moyenne (taille 2 à 3) de plus en plus nombreuses au fil des heures du jour et de la nuit suivante. Quelques avalanches de grande taille (taille 4) sont possibles dans les configurations les moins favorables avec un départ en altitude.

Déclenchements provoqués :

Plaques à vent facilement déclenchables présentes ou en formation en altitude, généralement de faible épaisseur. Risque limité à un large secteur Est au-dessus de la limite pluie/neige, proche des plus hauts sommets. Avalanches de taille 1 à 2, rarement 3. (observables : affaissement soudain du manteau neigeux, fissures sous les skis, traces de transport de neige par le vent).

Qualité de la neige

Enneigement :

Après plusieurs années déficitaires, l'enneigement sur le massif est légèrement au-dessus des normales. La limite de skiabilité se situe au plus bas vers 1200/1300 m dans les meilleures configurations et on peut skier confortablement dès 1500m

État de la neige :

La neige est déjà bien humide voir 'pourrie' dès le matin en-dessous de 2000m. Quelques cm de neige fraiche persisteront encore au-dessus de 2300/2400m. En journée, avec les précipitations attendues et la remontée de la limite pluie/neige, la neige s'humidifiera quasiment partout, et sur une profondeur de plus en plus importante.

Aperçu météo pour le mardi 10 février

	nuit	matin	après-midi	soir
Doux et pluvieux				
Pluie-Neige	2 100 m	2 200 m	2 600 m	2 300 m
Iso 0 °C	2 300 m	2 500 m	2 900 m	2 600 m
Vent 2000 m	↗ 30 km/h	→ 30 km/h	→ 40 km/h	→ 45 km/h
Vent 3000 m	↘ 40 km/h	→ 45 km/h	↗ 45 km/h	↓ 50 km/h

Épaisseur de neige hors-piste

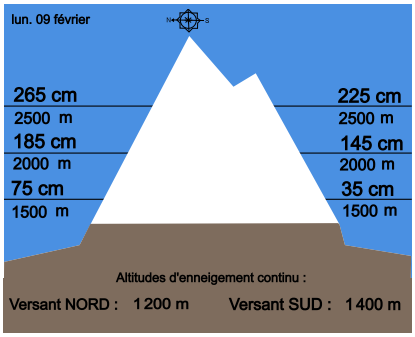

Précipitations à 1800 m

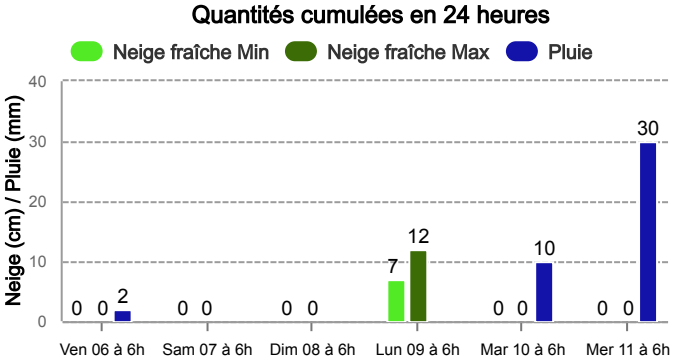

Tendance du mercredi 11 février

Indice de risque fort

Maintien d'un risque fort avec le poursuite de l'humidification en profondeur du manteau.

Pour consulter la vigilance en cours, veuillez vous rendre sur le site https://vigilance.meteofrance.fr/fr

Météo-France - 73 avenue de Paris, 94165 Saint-Mandé cedex - Contact : contact@meteo.fr

Rédigé par Météo-France avec la contribution des observateurs du réseau nivo-météorologiques. Partenariat : ANMSM (Maires de Stations de Montagne), DSF (Domaines Skiables de France), ADSP (Directeurs de Pistes et de la Sécurité des Stations de Sports d'Hiver) et autres acteurs de la montagne.

Bulletin neige & avalanches par téléphone au
0 892 68 10 20 Service 0,35 € / min + prix appel

RÉPUBLIQUE FRANÇAISE
Liberté Égalité Fraternité

METEO FRANCE
À VOS CÔTÉS, DANS UN CLIMAT QUI CHANGE

Bulletin d'estimation du risque d'avalanche

(valable en dehors des pistes balisées et ouvertes)

MASSIF : Couserans

Rédigé le lundi 9 février 2026 à 16h

Conditions nivo-météo des 7 derniers jours

	mar. 03/02				mer. 04/02				jeu. 05/02				ven. 06/02				sam. 07/02				dim. 08/02				lun. 09/02			
	03h	09h	15h	21h	03h	09h	15h	21h	03h	09h	15h	21h	03h	09h	15h	21h	03h	09h	15h	21h	03h	09h	15h	21h	03h	09h	15h	21h
Météo																												
Vent (km/h)	85	55	55	60	75	75	45	40	65	80	75	55	40	25	25	30	30	20	20	55	55	25	50	45	40	40	60	50
à 3000m	↑	↑	↑	↑	↑	↑	↘	→	↑	↑	↑	↗	→	→	→	↘	↘	↘	↘	→	↑	↘	↘	→	→	→	→	→
Vent (km/h)	35	35	35	45	50	55	25	25	45	60	55	40	25	15	15	20	20	15	15	40	45	10	45	40	35	25	50	30
à 2000m	↗	↑	↗	↑	↑	↑	→	↗	→	↑	↑	↗	→	→	→	↘	↑	↘	↘	→	↑	↘	→	→	→	→	→	→

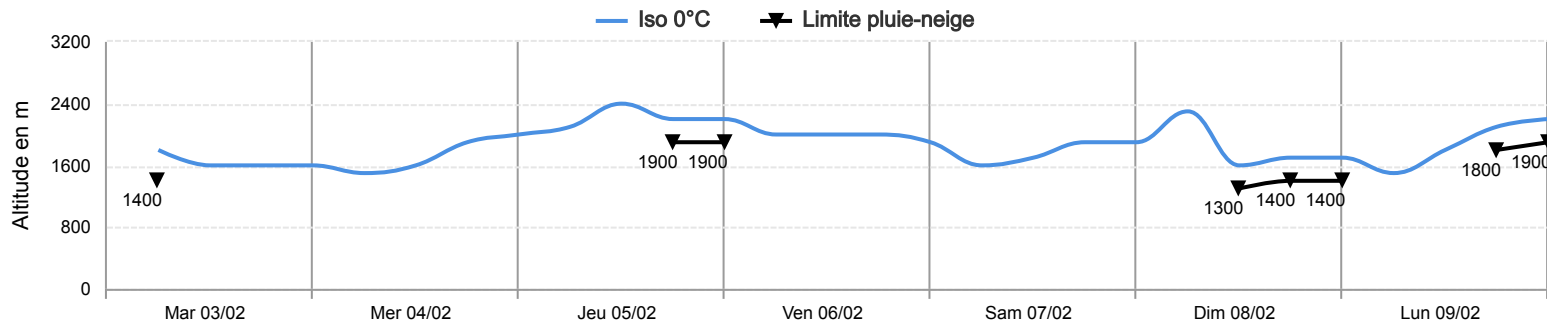

Risque d'avalanche	mar. 03/02	mer. 04/02	jeu. 05/02	ven. 06/02	sam. 07/02	dim. 08/02	lun. 09/02
	3	3	2	2	2	2	2

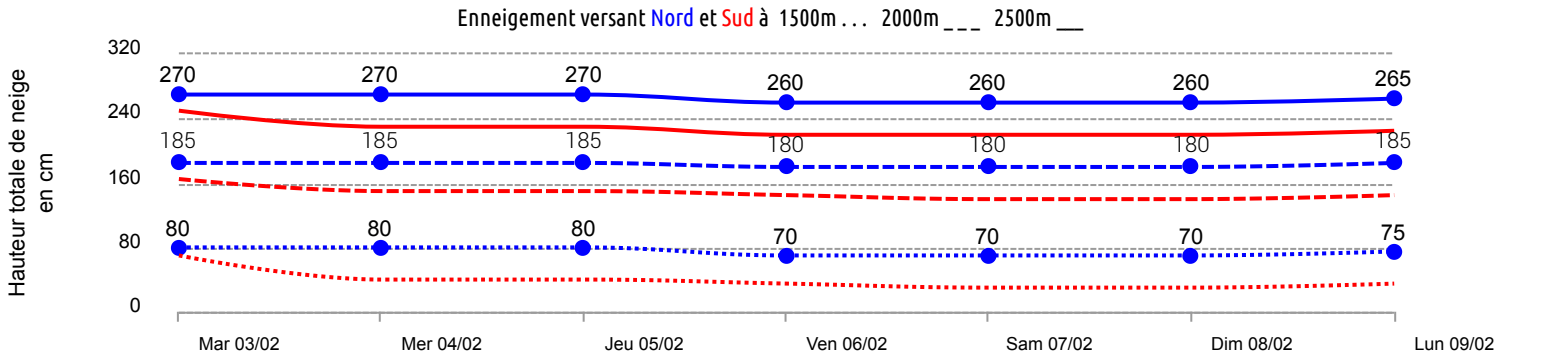

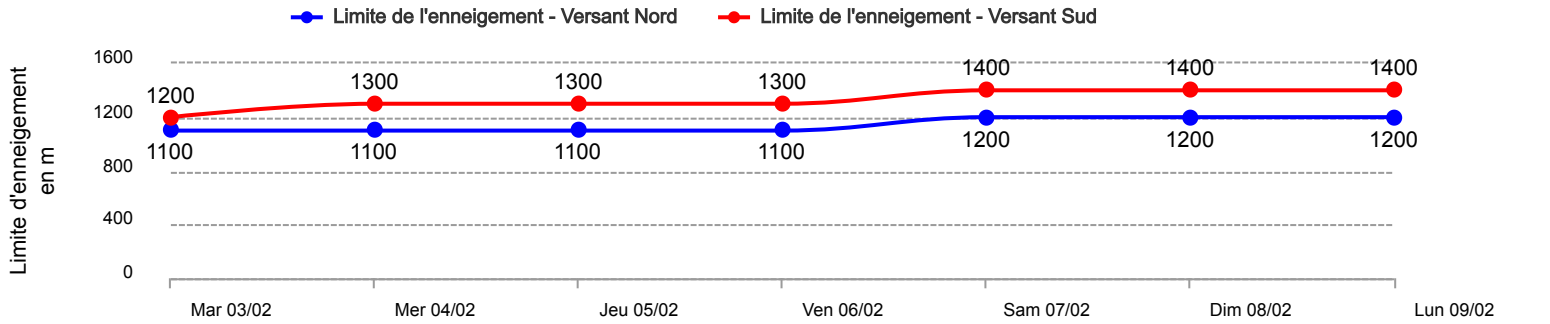

Pour consulter la vigilance en cours, veuillez vous rendre sur le site https://vigilance.meteofrance.fr/fr

Météo-France - 73 avenue de Paris, 94165 Saint-Mandé cedex - Contact : contact@meteo.fr

Rédigé par Météo-France avec la contribution des observateurs du réseau nivo-météorologiques. Partenariat : ANMSM (Maires de Stations de Montagne), DSF (Domaines Skiables de France), ADSP (Directeurs de Pistes et de la Sécurité des Stations de Sports d'Hiver) et autres acteurs de la montagne.

Bulletin neige & avalanches par téléphone au
0 892 68 10 20 Service 0,35 € / min + prix appel