Bulletin d'estimation du risque d'avalanche

(valable en dehors des pistes balisées et ouvertes)

MASSIF : Devoluy

Rédigé le lundi 9 février 2026 à 16h

Estimation des risques pour le : MARDI 10 FÉVRIER

QUELQUES INSTABILITÉS VOLUMINEUSES EN UBACS D'ALTITUDE, DIFFICILES À DÉCLENCHER

2

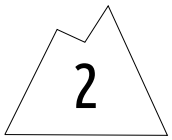

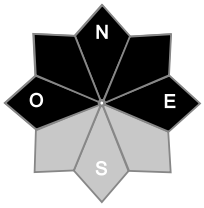

Indice de risque limité.

Départs spontanés : départs superficiels en neige humide

Déclenchements provoqués : quelques instabilités, parfois faciles à déclencher. En versants froids d'altitude, avalanches de plaque parfois grandes, mais difficiles à déclencher

Indices de risque : 5 très fort - 4 fort - 3 marqué - 2 limité - 1 faible -- En noir : les pentes les plus dangereuses

Stabilité du manteau neigeux

Situation avalancheuse typique : couche fragile persistante neige ventée

Déclenchements provoqués : quelques instabilités en place en versants est / nord / ouest au-dessus de 2000 m environ. Plaques généralement bien stabilisées, déclenchement difficile, mais encore possible localement sur les croupes et bords de couloirs où le manteau neigeux est moins épais. Elles engendrent des avalanches de taille moyenne à grande (taille 2 à 3), avec des cassures larges et épaisses. En effet, présence d'une importante couche fragile enfouie à la base du manteau neigeux.
Par ailleurs en altitude, quelques plaques plus superficielles en place en toute orientation dans la neige récente ventée, plutôt à proximité des crêtes. D'autres en formation avec les faibles chutes de neige plus ou moins ventée. Faciles à déclencher, générant des avalanches de petite taille, voire moyenne, mais peuvent déclencher en cascade les plaques plus volumineuses décrites précédemment.
En fin de journée de mardi, avec les nouvelles chutes de neige attendues en altitude et le vent, nouvelles plaques en formation.

Départs spontanés : départs ponctuels de neige humidifiée avec le redoux temporaire en journée. Taille petite, rarement moyenne.
En fin de journée, avec le renforcement des précipitations, l'activité naturelle est en nette augmentation. En neige humide jusqu'à 1800/2000 m, en neige sèche au-dessus.

Qualité de la neige

L'enneigement est excédentaire pour un début février.
Données observées : environ 100 cm vers 2000 m d'altitude.

Limite d'enneigement skiable : vers 1200/1300 m sur la plupart des itinéraires.

État de la neige de surface : un peu de neige fraiche sur de la neige récente en altitude, restée poudreuse et légère en versants froids au-dessus de 1700/1800 m, et parfois densifiée ou cartonnée par le vent près des crêtes. En versants ensoleillés, sur de la neige récente plus tassée et croutée sous 2400/2500 m.

Aperçu météo pour le mardi 10 février

	nuit	matin	après-midi	soir

5/10 cm de neige entre la fin de nuit/matinée. Dégradation plus franche en soirée/première partie de nuit de mardi.

	nuit	matin	après-midi	soir
Pluie-Neige	1 100 m	1 100 m	1 700 m	1 400 m
Iso 0 °C	1 500 m	1 600 m	2 000 m	1 900 m
Vent 2000 m	↑ 20 km/h	↑ 15 km/h	↑ 20 km/h	↑ 25 km/h
Vent 3000 m	→ 30 km/h	→ 40 km/h	→ 40 km/h	→ 55 km/h

Épaisseur de neige hors-piste

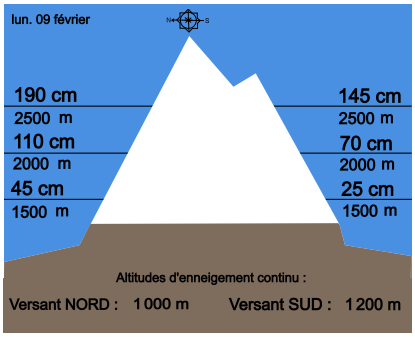

Précipitations à 1800 m

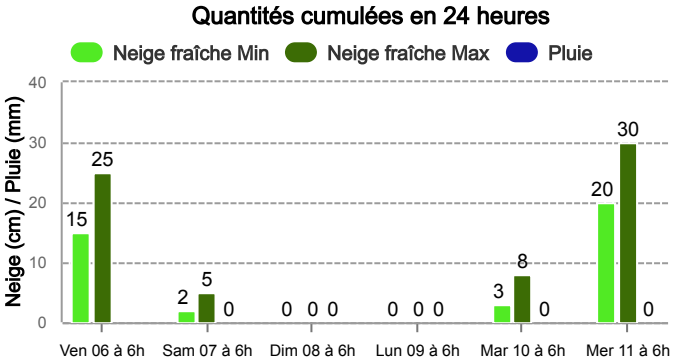

Tendance du mercredi 11 février

3

Indice de risque marqué

Risque en hausse. Formation de nouvelles instabilités.

Pour consulter la vigilance en cours, veuillez vous rendre sur le site https://vigilance.meteofrance.fr/fr

Météo-France - 73 avenue de Paris, 94165 Saint-Mandé cedex - Contact : contact@meteo.fr

Rédigé par Météo-France avec la contribution des observateurs du réseau nivo-météorologiques. Partenariat : ANMSM (Maires de Stations de Montagne), DSF (Domaines Skiables de France), ADSP (Directeurs de Pistes et de la Sécurité des Stations de Sports d'Hiver) et autres acteurs de la montagne.

Bulletin neige & avalanches par téléphone au 0 892 68 10 20 Service 0,35 € / min + prix appel

RÉPUBLIQUE FRANÇAISE
Liberté Égalité Fraternité

METEO FRANCE
À VOS CÔTÉS, DANS UN CLIMAT QUI CHANGE

Bulletin d'estimation du risque d'avalanche

(valable en dehors des pistes balisées et ouvertes)

MASSIF : Devoluy

Rédigé le lundi 9 février 2026 à 16h

Conditions nivo-météo des 7 derniers jours

	mar. 03/02				mer. 04/02				jeu. 05/02				ven. 06/02				sam. 07/02				dim. 08/02				lun. 09/02			
	03h	09h	15h	21h	03h	09h	15h	21h	03h	09h	15h	21h	03h	09h	15h	21h	03h	09h	15h	21h	03h	09h	15h	21h	03h	09h	15h	21h
Météo																												
Vent (km/h)	120	60	50	40	40	40	30	15	30	15	60	40	40	45	35	20	15	10	10	5	10	25	25	10	5	15	15	20
à 3000m																												
Vent (km/h)	70	45	35	35	35	30	20	5	10	20	60	10	25	25	25	15	10	10	15	10	10	20	20	10	5	15	15	15
à 2000m																												

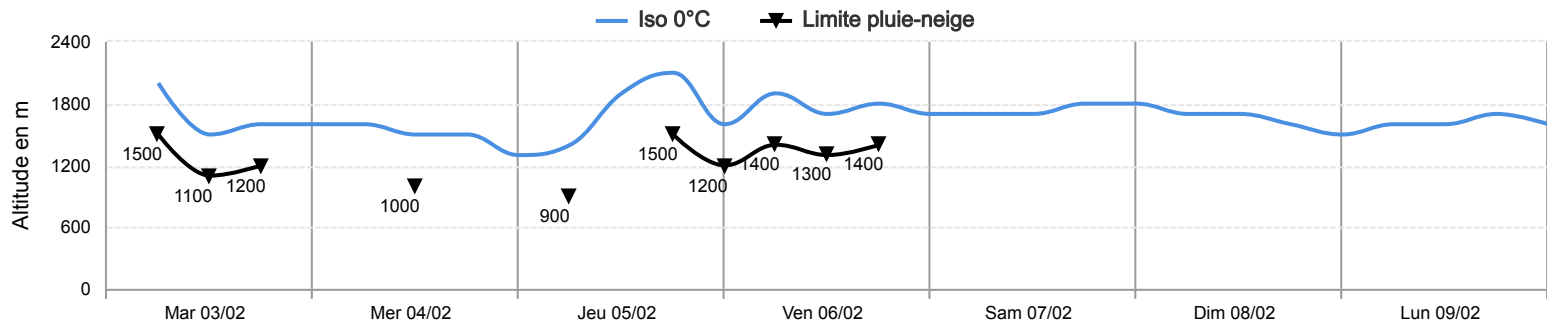

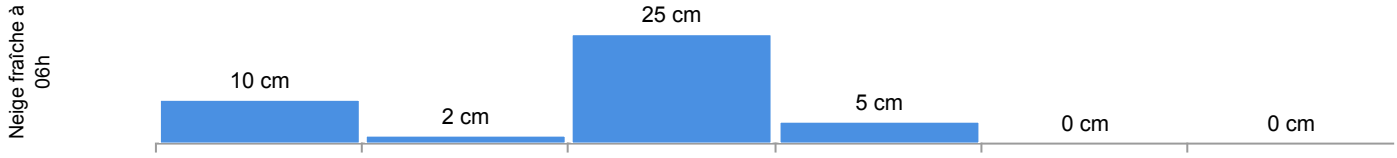

Risque d'avalanche	mar. 03/02	mer. 04/02	jeu. 05/02	ven. 06/02	sam. 07/02	dim. 08/02	lun. 09/02
	4	3	3	4	3	3	2

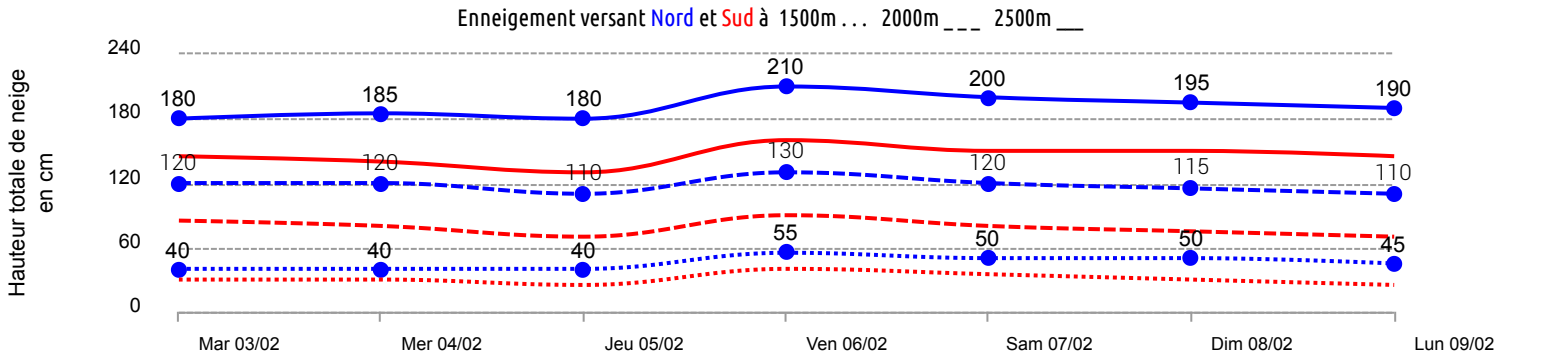

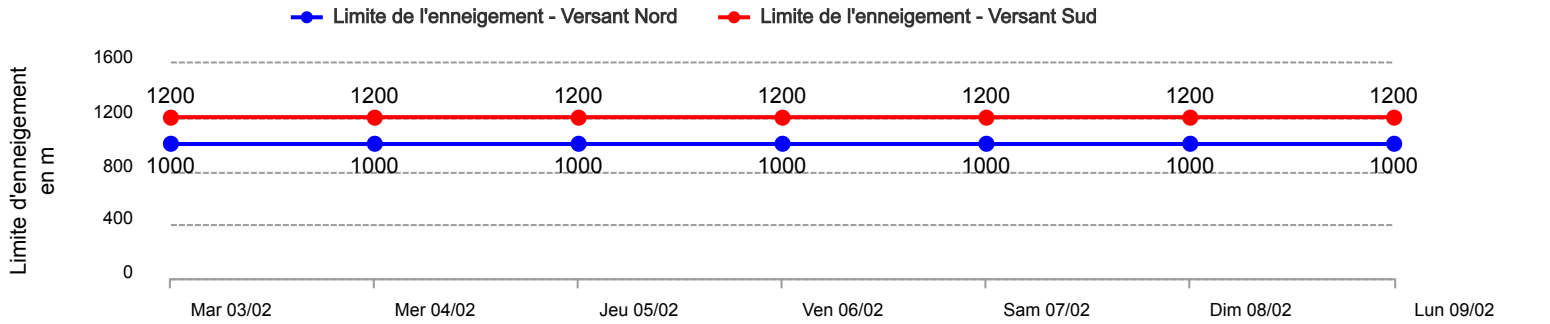

Pour consulter la vigilance en cours, veuillez vous rendre sur le site https://vigilance.meteofrance.fr/fr

Météo-France - 73 avenue de Paris, 94165 Saint-Mandé cedex - Contact : contact@meteo.fr

Rédigé par Météo-France avec la contribution des observateurs du réseau nivo-météorologiques. Partenariat : ANMSM (Maires de Stations de Montagne), DSF (Domaines Skiables de France), ADSP (Directeurs de Pistes et de la Sécurité des Stations de Sports d'Hiver) et autres acteurs de la montagne.

Bulletin neige & avalanches par téléphone au
0 892 68 10 20 Service 0,35 € / min + prix appel