Bulletin d'estimation du risque d'avalanche

(valable en dehors des pistes balisées et ouvertes)

MASSIF : Haute-Tarentaise

Rédigé le lundi 9 février 2026 à 16h

Estimation des risques pour le : MARDI 10 FÉVRIER

LES PRÉCIPITATIONS FAIBLES ET NEIGEUSES LE MATIN ET SURTOUT CELLES FORTES ET PLUVIEUSES ASSEZ HAUT LE SOIR VONT RADICALEMENT CHANGER ET AGGRAVER LA SITUATION NIVOLOGIQUE

3

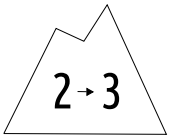

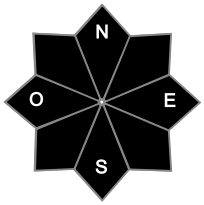

Indice de risque limité évoluant en marqué.

Départs spontanés : En soirée: sous 1900m en neige humide à cause de la pluie , au dessus de 1900m en avalanche de poudre

Déclenchements provoqués : Plaques piégeuses car d'aspect poudreux encore faciles à déclencher dans la neige fraiche, plus fréquentes en large Nord et au dessus de 1800m.

Indices de risque : 5 très fort - 4 fort - 3 marqué - 2 limité - 1 faible -- En noir : les pentes les plus dangereuses

Stabilité du manteau neigeux

Situation avalancheuse typique : couche fragile persistante neige humide

En journée de mardi: le risque principal reste le déclenchement provoqué de **plaques d'aspect poudreux reposant sur des couches fragiles,** enfouies plus ou moins profondément. De nouvelles petites plaques vont se former en journée lors des chutes de neige accompagnées de vent d'ouest, elles vont se rajouter à celles plus épaisse encore en place. Déclenchement **possibles au passage d'un seul skieur,** cassure 20/30 cm pour les plaques récentes pouvant dépasser les 60/80 cm pour les plus anciennes. **Taille 2 voir 3 si départ en cascade**. On les trouvera surtout **au dessus de 1800m et plutôt en large secteur Nord (pour la présence de couche fragile persistante)**. En journée le cumul de précipitations semble encore trop faible pour générer des départs spontanés

En fin de journée et surtout soirée de mardi : **Nombreuses avalanches de neige humide sous 1800m** engendrées par les **fortes pluies** (15/20mm attendues en 4h) qui vont remonter progressivement jusque vers 1800/2000m en milieu de nuit . Départs possible en **toutes orientations** mais c'est en Nord là où la neige était encore poudreuse et mobilisable que ces avalanches pourront atteindre les plus gros volumes T2 rare T3 (cassure 30/40 cm). **Des avalanches de talus pourraient ainsi toucher dans la nuit quelques routes d'altitude et plus surement des chemins forestiers et pistes de skis.**
Au dessus de 2000m les cumuls de neige deviennent suffisant en fin de soirée pour occasionner les **premières avalanches naturelles en poudreuse** dans les pentes les plus raides (départs ponctuel ou en plaque) Taille 2 à taille 3 là où ces avalanches vont partir en activant les sous couches fragiles persistantes enfouies.

Qualité de la neige

Enneigement : Un peu en dessous des normales de saison mais les chutes qui débutent ce mardi vont améliorer nettement l'enneigement au dessus de 1500m, en dessous la pluie attendue va bien dégrader le manteau.

Limite skiable : Les versants froids voyant pas ou peu le soleil ont gardé de la neige à basse altitude, skiable sur l'herbe ou sur pistes forestières dès 1000m. Sous bois skiables dès 1200m. En versant sud skiable dès 1300/1400m en prairies pas trop raides, 1800m en Sud raide.

Qualité de la neige : En Sud sous 2300m, en Est, Nord et Ouest, sous 1700 m neige croutée au lever du jour et peu à peu recouverte de fraiche pour atteindre 7/10cm de fraiche à la mi-journée. Plus haut, elle reste poudreuse (~20 puis 30 cm), bonne à skier, jusqu'à l'approche des crêtes où elle peut être cartonnée par le vent.
A l'arrivée de la pluie cette belle neige poudreuse devient toute de suite collante, voir pourrie une fois qu'elle est bien arrosée.

Aperçu météo pour le mardi 10 février

	nuit	matin	après-midi	soir

Neige faible le matin dès la basse altitude, rares averses l'après midi de neige vers 1600m, fortes pluies le soir temporairement jusqu'à 1800/2000m

Pluie-Neige	800 m	900 m	1700 m	1900 m
Iso 0 °C	1800 m	1700 m	2100 m	2300 m
Vent 2500 m	↖ 10 km/h	↗ 15 km/h	→ 20 km/h	↑ 20 km/h
Vent 3500 m	→ 35 km/h	→ 50 km/h	↗ 55 km/h	→ 55 km/h

Épaisseur de neige hors-piste

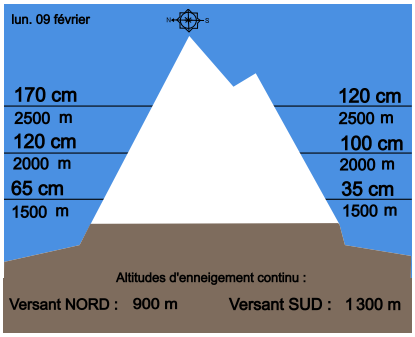

Précipitations à 1800 m

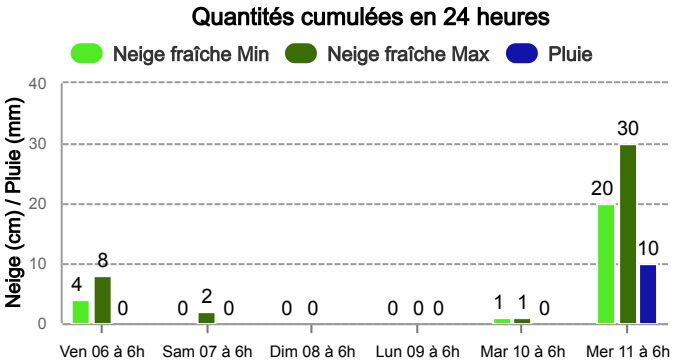

Tendance du mercredi 11 février

Indice de risque fort

Les fortes chutes de neige se poursuivent au dessus de 1500/1600m (temporairement 1900m) les cumuls de fraiche deviennent déjà critiques en fin de journée occasionnant un fort risque d' avalanches naturelles.

Pour consulter la vigilance en cours, veuillez vous rendre sur le site https://vigilance.meteofrance.fr/fr

Météo-France - 73 avenue de Paris, 94165 Saint-Mandé cedex - Contact : contact@meteo.fr

Rédigé par Météo-France avec la contribution des observateurs du réseau nivo-météorologiques. Partenariat : ANMSM (Maires de Stations de Montagne), DSF (Domaines Skiables de France), ADSP (Directeurs de Pistes et de la Sécurité des Stations de Sports d'Hiver) et autres acteurs de la montagne.

Bulletin neige & avalanches par téléphone au

0 892 68 10 20 Service 0,35 € / min + prix appel

RÉPUBLIQUE FRANÇAISE
Liberté Égalité Fraternité

METEO FRANCE
À VOS CÔTÉS, DANS UN CLIMAT QUI CHANGE

Bulletin d'estimation du risque d'avalanche

(valable en dehors des pistes balisées et ouvertes)

MASSIF : Haute-Tarentaise

Rédigé le lundi 9 février 2026 à 16h

Conditions nivo-météo des 7 derniers jours

	mar. 03/02				mer. 04/02				jeu. 05/02				ven. 06/02				sam. 07/02				dim. 08/02				lun. 09/02			
	03h	09h	15h	21h	03h	09h	15h	21h	03h	09h	15h	21h	03h	09h	15h	21h	03h	09h	15h	21h	03h	09h	15h	21h	03h	09h	15h	21h
Météo																												
Vent (km/h)	90	75	50	50	55	30	30	35	35	35	40	40	40	45	45	20	15	15	15	15	20	30	30	25	20	15	20	25
à 3500m																												
Vent (km/h)	75	55	35	25	35	30	20	10	15	20	25	30	30	35	35	15	5	5	5	5	10	25	25	20	10	10	10	10
à 2500m																												

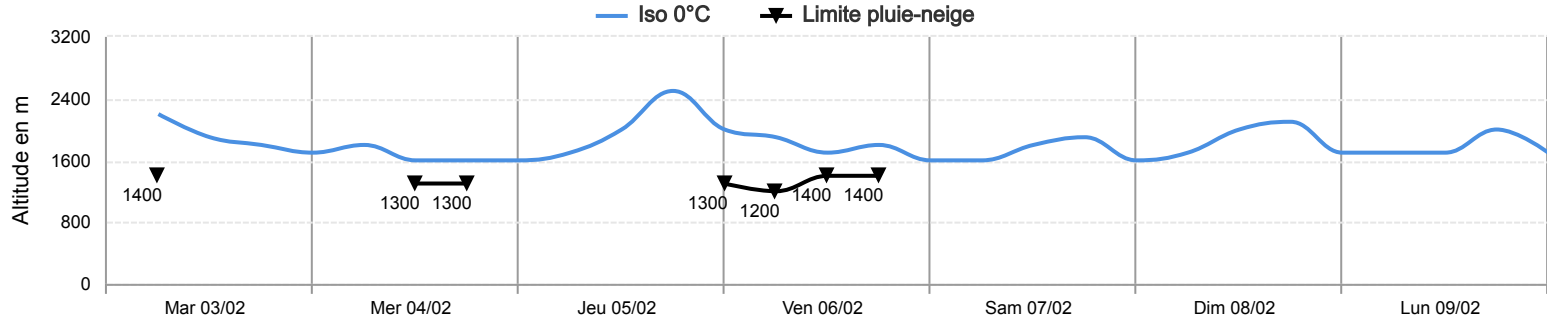

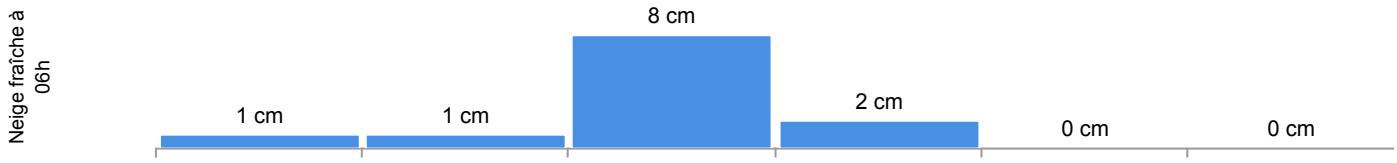

Risque d'avalanche	mar. 03/02	mer. 04/02	jeu. 05/02	ven. 06/02	sam. 07/02	dim. 08/02	lun. 09/02
	3	3	3	3	3	3	3

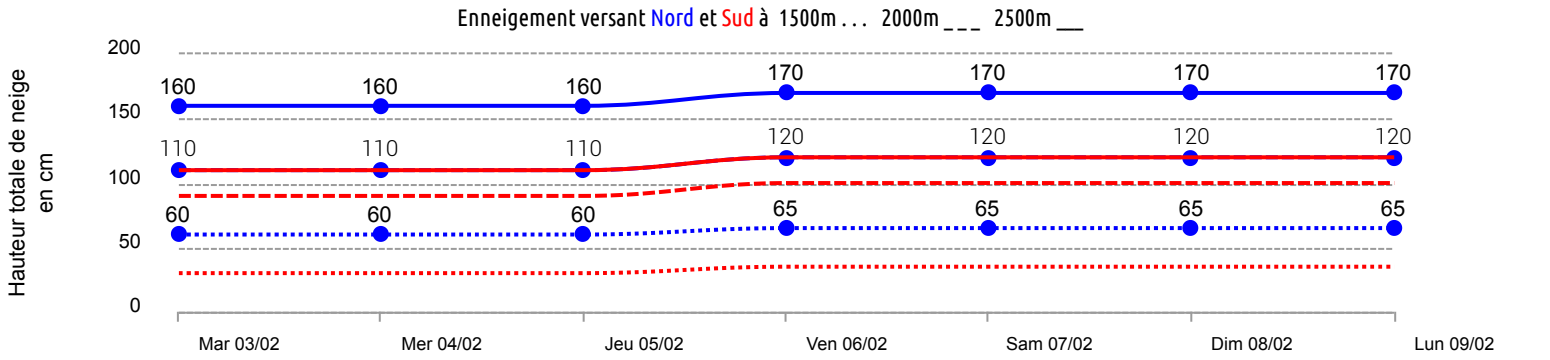

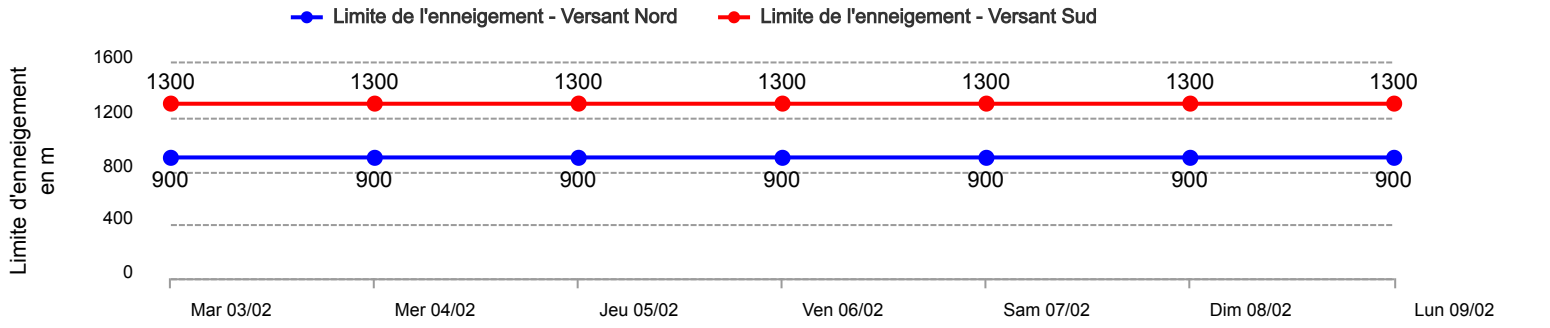

Pour consulter la vigilance en cours, veuillez vous rendre sur le site https://vigilance.meteofrance.fr/fr

Météo-France - 73 avenue de Paris, 94165 Saint-Mandé cedex - Contact : contact@meteo.fr

Rédigé par Météo-France avec la contribution des observateurs du réseau nivo-météorologiques. Partenariat : ANMSM (Maires de Stations de Montagne), DSF (Domaines Skiables de France), ADSP (Directeurs de Pistes et de la Sécurité des Stations de Sports d'Hiver) et autres acteurs de la montagne.

Bulletin neige & avalanches par téléphone au
0 892 68 10 20 Service 0,35 € / min + prix appel