Bulletin d'estimation du risque d'avalanche
(valable en dehors des pistes balisées et ouvertes)

MASSIF : Luchonnais

Rédigé le lundi 9 février 2026 à 16h

Estimation des risques pour le : MARDI 10 FÉVRIER

NEIGE VENTÉE EN ALTITUDE, HUMIDIFICATION MARQUÉE AILLEURS AU FIL DE LA JOURNÉE.

3

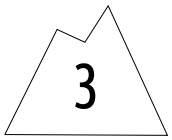

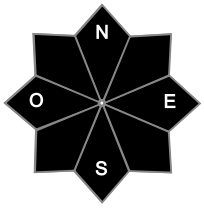

Indice de risque marqué.

Départs spontanés : Par surcharge par le vent en altitude, humidification importante plus bas.

Déclenchements provoqués : Plaques s'épaississant en altitude, couches fragiles enfouies en secteurs froids.

Indices de risque : 5 très fort - 4 fort - 3 marqué - 2 limité - 1 faible -- En noir : les pentes les plus dangereuses

Stabilité du manteau neigeux

Situation avalancheuse typique : neige ventée neige humide

Déclenchements provoqués :
Au-dessus de 2300m, de nouvelles plaques se forment en journée ce mardi dans les versants allant majoritairement du Nord vers le Sud-Est. Elles sont déjà plus ou moins épaisses à la mi-journée avec les chutes de neige de la nuit précédente et celles se poursuivant ce mardi sous l'effet du vent soutenu d'Ouest à Nord-Ouest. Elles continuent à s'épaissir au fil de la journée. Elles reposent généralement sur des plaques moins épaisses datant des chutes de neige précédentes. Elles restent facilement déclenchables et leur rupture par un simple skieur peut engendrer des cassures linéaires moyennes à grandes (tailles 2 à 3). Il n'est pas exclu de trouver des plaques épaisses dans un large secteur Ouest, leur sollicitation engendrant des avalanches moyennes à parfois grandes (taille 2 à 3).
Dans les secteurs froids bien ombragés au-dessus de 2300m, des couches fragiles sont encore en place, bien enfouies donc difficilement déclenchables. Cependant, leur sollicitation reste possible et peut engendrer de grandes cassures (taille 3).

Départs spontanés :
Au-dessus de 2300m, des départs spontanés des plaques décrites ci-dessus restent possibles, par surcharge par le vent, engendrant principalement des avalanches moyennes à grandes (taille 2 à 3). Dans les secteurs froids ombragés, les couches fragiles persistantes restent sollicitables, même si elles sont bien enfouies, par surcharge par le vent, ce qui peut engendrer de grandes avalanches (taille 3).
Avec les averses de pluie marquées ce mardi, poursuivant celles déjà entamées dans la nuit de lundi à mardi, des départs spontanés dans la neige humide sont attendus sous 2300/2400m en toutes expositions avec la limite pluie-neige remontant jusqu'à 2300/2400m. En mobilisant des couches de neige anciennes et en humidifiant le manteau neigeux en profondeur, les avalanches peuvent être de tailles moyennes à grandes dès la matinée. Plus rarement, de très grandes avalanches (taille 4) sont possibles avec les cumuls de pluie importants sur la journée et se poursuivant en soirée et nuit suivante (de mardi à mercredi). Cela peut se produire lorsque le manteau est humidifié bien en profondeur notamment au fur et à mesure de la journée et notamment dans les zones d'accumulation les plus importantes.

Autres :
Corniches souvent imposantes au-dessus des pentes est

Qualité de la neige

Enneigement : Bon pour la saison, mais les crêtes, cols et sommets en expositions ouest sont souvent pelés par le vent dans les expositions ouest. Accumulations plus importantes en secteurs frontaliers. Fonte de la neige attendue ce mardi sous 2300m.
Limites skiables : Manteau neigeux skiable à partir de 1300-1400m en Nord.
État de la neige : Sous 2300/2400m, la neige est déjà bien humidifiée et lourde dès la matinée et elle continue à se gorger d'eau au fil de la journée et des averses de pluie. Au-dessus, le neige reste sèche, souvent bien travaillée par le vent dans les secteur Nord à Sud-Est, parfois même dans un large secteur Ouest.

Aperçu météo pour le mardi 10 février

	nuit	matin	après-midi	soir

Des averses de pluie marquées sur la journée jusqu'à 2400/2500m, parfois orageuses en fin d'échéance. Vent d'Ouest à Nord-Ouest assez fort.

Pluie-Neige	1 900 m	2 300 m	2 600 m	2 300 m
Iso 0 °C	2 300 m	2 700 m	2 900 m	2 700 m
Vent 2000 m	↗ 30 km/h	↘ 40 km/h	↗ 40 km/h	↓ 55 km/h
Vent 3000 m	↘ 90 km/h	↘ 85 km/h	→ 95 km/h	→ 90 km/h

Pour consulter la vigilance en cours, veuillez vous rendre sur le site https://vigilance.meteofrance.fr/fr

Météo-France - 73 avenue de Paris, 94165 Saint-Mandé cedex - Contact : contact@meteo.fr

Rédigé par Météo-France avec la contribution des observateurs du réseau nivo-météorologiques. Partenariat : ANMSM (Maires de Stations de Montagne), DSF (Domaines Skiables de France), ADSP (Directeurs de Pistes et de la Sécurité des Stations de Sports d'Hiver) et autres acteurs de la montagne.

Bulletin neige & avalanches par téléphone au 0 892 68 10 20 Service 0,35 € / min + prix appel

Bulletin d'estimation du risque d'avalanche

(valable en dehors des pistes balisées et ouvertes)

MASSIF : Luchonnais

Rédigé le lundi 9 février 2026 à 16h

Épaisseur de neige hors-piste

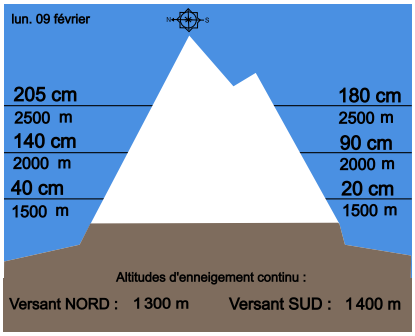

Précipitations à 1800 m

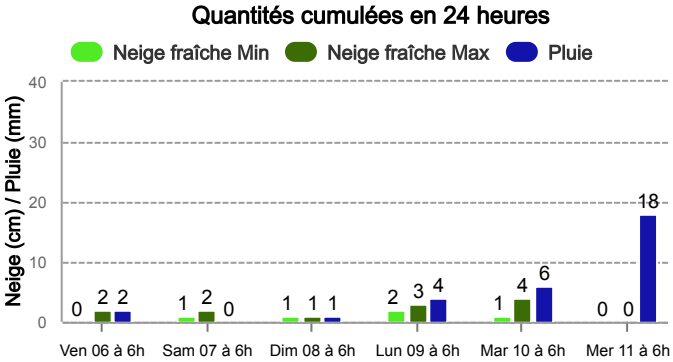

Tendance du mercredi 11 février

Indice de risque fort

Risque fort potentiel, le manteau neigeux poursuit son humidification ce mercredi avec des averses de pluie jusqu'à 2300/2400m en journée. Vent restant assez fort à fort d'Ouest à Nord-Ouest.

Pour consulter la vigilance en cours, veuillez vous rendre sur le site https://vigilance.meteofrance.fr/fr

Météo-France - 73 avenue de Paris, 94165 Saint-Mandé cedex - Contact : contact@meteo.fr

Rédigé par Météo-France avec la contribution des observateurs du réseau nivo-météorologiques. Partenariat : ANMSM (Maires de Stations de Montagne), DSF (Domaines Skiables de France), ADSP (Directeurs de Pistes et de la Sécurité des Stations de Sports d'Hiver) et autres acteurs de la montagne.

Bulletin neige & avalanches par téléphone au

0 892 68 10 20 Service 0,35 € / min + prix appel

RÉPUBLIQUE FRANÇAISE
Liberté Égalité Fraternité

METEO FRANCE
À VOS CÔTÉS, DANS UN CLIMAT QUI CHANGE

Bulletin d'estimation du risque d'avalanche

(valable en dehors des pistes balisées et ouvertes)

MASSIF : Luchonnais

Rédigé le lundi 9 février 2026 à 16h

Conditions nivo-météo des 7 derniers jours

	mar. 03/02				mer. 04/02				jeu. 05/02				ven. 06/02				sam. 07/02				dim. 08/02				lun. 09/02			
	03h	09h	15h	21h	03h	09h	15h	21h	03h	09h	15h	21h	03h	09h	15h	21h	03h	09h	15h	21h	03h	09h	15h	21h	03h	09h	15h	21h
Météo																												
Vent (km/h)	55	45	40	90	95	100	60	55	75	130	95	70	70	70	60	50	40	40	40	50	40	35	50	40	50	50	55	65
à 3000m	→	→	↗	↗	↗	→	→	→	↗	↗	→	→	↗	↗	↗	↑	→	↘	↘	↑	↗	↘	↘	↘	↘	→	↘	→
Vent (km/h)	35	40	30	60	70	55	25	25	55	100	75	55	50	55	45	30	30	10	20	35	30	10	20	15	20	20	20	25
à 2000m	↑	↑	↖	→	↑	↑	↗	↗	↑	↑	↑	↗	↗	↗	↗	↗	↗	↗	↑	↑	↑	↘	↘	↗	↗	↗	↘	↗

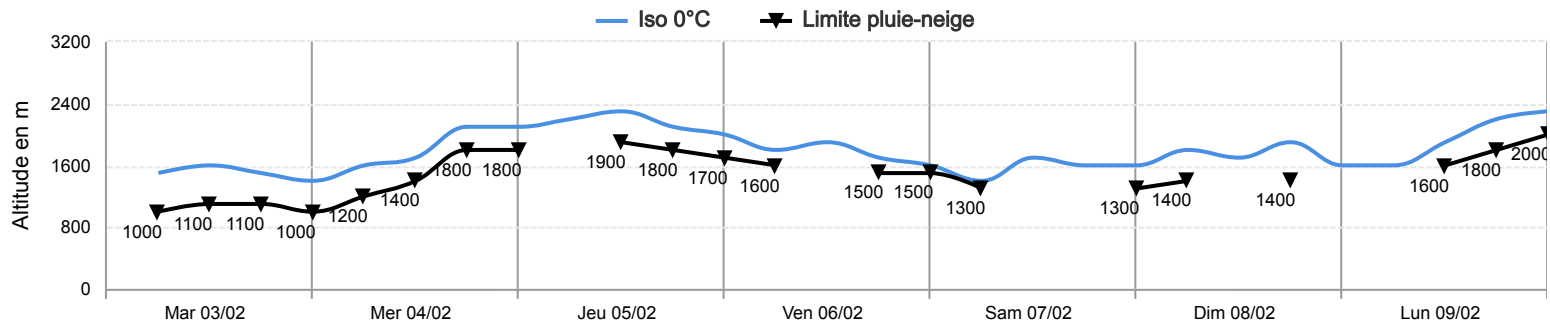

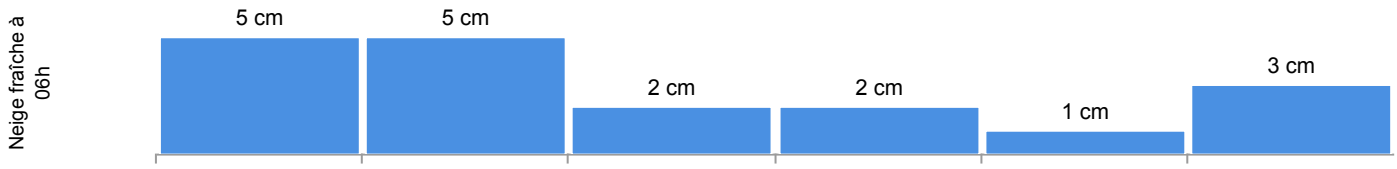

Risque d'avalanche							
	3	3	3	3	2	2	2
	mar. 03/02	mer. 04/02	jeu. 05/02	ven. 06/02	sam. 07/02	dim. 08/02	lun. 09/02

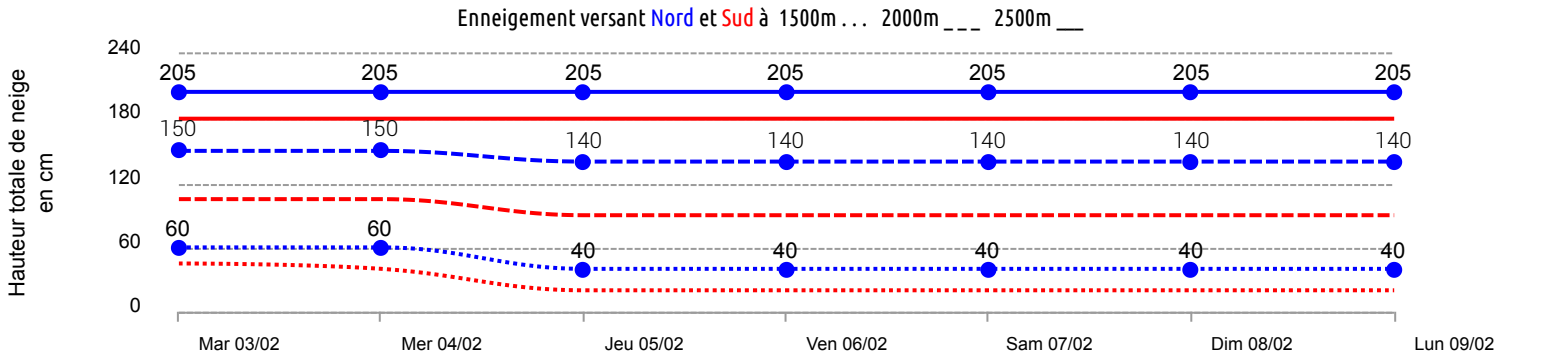

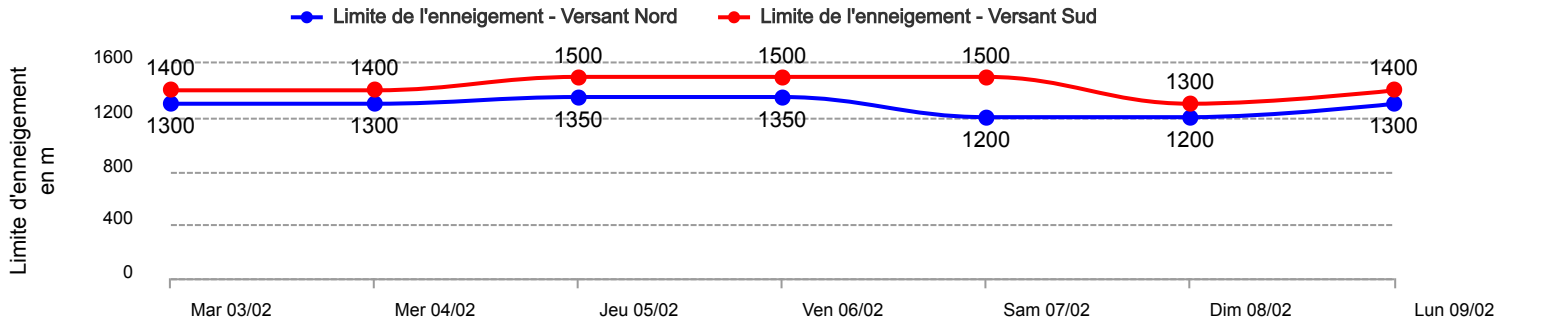

Pour consulter la vigilance en cours, veuillez vous rendre sur le site https://vigilance.meteofrance.fr/fr

Météo-France - 73 avenue de Paris, 94165 Saint-Mandé cedex - Contact : contact@meteo.fr

Rédigé par Météo-France avec la contribution des observateurs du réseau nivo-météorologiques. Partenariat : ANMSM (Maires de Stations de Montagne), DSF (Domaines Skiables de France), ADSP (Directeurs de Pistes et de la Sécurité des Stations de Sports d'Hiver) et autres acteurs de la montagne.

Bulletin neige & avalanches par téléphone au
0 892 68 10 20 Service 0,35 € / min + prix appel