Bulletin d'estimation du risque d'avalanche

(valable en dehors des pistes balisées et ouvertes)

MASSIF : Oisans

Rédigé le lundi 9 février 2026 à 16h

Estimation des risques pour le : MARDI 10 FÉVRIER

INSTABILITES EN NEIGE FRAICHE / VENTEE EN LARGE NORD D'ALTITUTDE. POSSIBILITE DE GRANDE CASSURE. RISQUE EN HAUSSE EN SOIREE

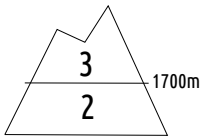

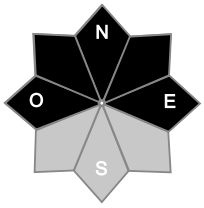

Au-dessus de 1700m indice de risque marqué, plus bas indice limité.

Départs spontanés : Rares en journée, nombreuses en soirée sous les chutes de neige et sous la pluie à plus basse altitude.

Déclenchements provoqués : Instabilités en large Nord dans la neige fraîche / ventée en journée. Possibilité de déclenchement à distance / grande cassure. Plaques plus nombreuses et en tout versants sous les chutes de neige en soirée.

Indices de risque : 5 très fort - 4 fort - 3 marqué - 2 limité - 1 faible -- En noir : les pentes les plus dangereuses

Stabilité du manteau neigeux

Situation avalancheuse typique : couche fragile persistante neige ventée

En journée : Faible passage perturbé dans la nuit et en matinée de mardi, avec 5 à 10cm dés 1500m. Formation de quelques plaques sous le vent d'Ouest / Sud-Ouest.
Déclenchements provoqués : Au-desus de 1700m et surtout en large Nord, des instabilités de surface sont présentes dans les 5 à 10cm de neige fraîche qui tombent en fin de nuit / matinée de mardi. Cette neige fraîche se dépose parfois sur de la neige encore légère en versants Nord, rendant les plaques localement très réactives. Dans les mêmes versants au-dessus de 2100/2300m des plaques plus anciennes restent présentes. Plus dures à solliciter, elles peuvent également être plus épaisses.
En large Nord et dés 2000m environ, des **grains anguleux sont souvent enfouis dans le manteau, rendant possible le déclenchement à distance, et le départ de grandes avalanches**. Le risque de solliciter une de ces couches fragiles à ski diminue mais reste bien présent. Par ailleurs le départ d'une avalanche de surface (même modeste) peut être suffisant pour déclencher en cascade une avalanche de grande taille. Une pente skiée n'est pas un indice de stabilité.
Départs spontanés : Des boulettes ou de petites coulées possibles en journée, dans la neige récente qui s'humidifie sous 1800/2000m. Au-dessus, peu probable, ou une petite coulée en neige fraîche, surtout sous le vent de Sud-Ouest.

En soirée : Perturbation active, avec 20 à 30cm en quelques heures au-dessus de 2000m, accompagnées d'un vent fort d'Ouest / Nord-Ouest. Pluies soutenues plus bas.
Départs spontanés : Au-dessus de 2000m, des **avalanches naturelles de plus en plus nombreuses au fil des chutes de neige sont attendues,** souvent de tailles moyennes, parfois de grandes tailles en fin de soirée, voire de très grande taille si les couches fragiles persistantes sont sollicitées. Elles sont plus nombreuses en large secteur Est. Sous 2000m, la pluie alourdit le manteau neigeux et provoque de nombreux départs spontanés, souvent de tailles moyennes (surtout en versants Nord où la neige est restée froide).
Déclenchements provoqués : De nouvelles plaques se forment en soirée en tout versants. Plaques dures vers les crêtes, plus poudreuses en bas de pente où le vent est plus faible. Cassures pouvant être larges et de plus en plus épaisses au fil des heures. Surtout en Est où les accumulations seront plus importantes sous le vent.

Qualité de la neige

Qualification de l'enneigement : L'enneigement est correct à très bon pour la saison en altitude, notamment dans les combes et médiocre sous la moyenne montagne, en vallées...

Limites skiables : vers 1100/1500 m.

Qualité de la neige mardi : Au-dessus de 1800m, 5 à 10cm de neige fraîche, parfois densifiée par le vent, notamment à l'abord des crêtes. Entre 1300 et 1800m, petite couche de neige récente humide, collant parfois aux skis. Sous-couche en poudreuse dense en versants froids, croûtée en Sud.

Aperçu météo pour le mardi 10 février

	nuit	matin	après-midi	soir

Petites chutes de neige en fin de nuit / matinée. Petites averses en journée sous un ciel couvert. Perturbation active en soirée / nuit suivante.

Pluie-Neige	1 200 m	1 300 m	1 800 m	1 900 m
Iso 0 °C	1 800 m	1 700 m	2 100 m	2 200 m
Vent 2500 m	↑ 15 km/h	↑ 15 km/h	↗ 30 km/h	↑ 45 km/h
Vent 3500 m	↗ 25 km/h	↗ 30 km/h	↗ 45 km/h	↗ 70 km/h

Épaisseur de neige hors-piste

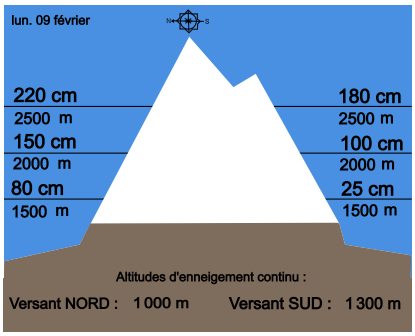

Précipitations à 1800 m

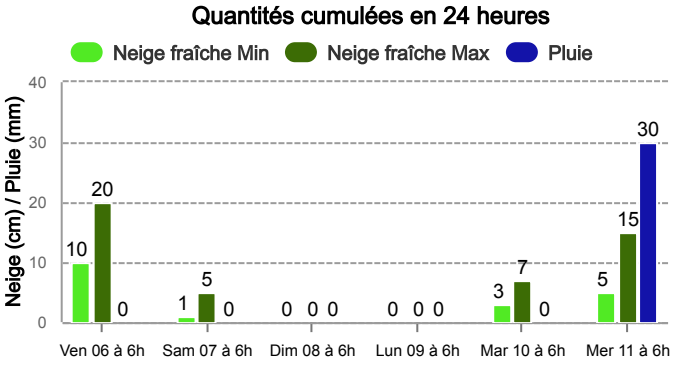

Tendance du mercredi 11 février

Indice de risque fort

Risque devenant fort dés la nuit de mardi à mercredi. Les chutes de neige se poursuivent en journée, avec une limite pluie-neige s'abaissant vers 1500m. Instabilités généralisées dans l'importante couche de neige récente. Grandes avalanches possibles.

Pour consulter la vigilance en cours, veuillez vous rendre sur le site https://vigilance.meteofrance.fr/fr

Météo-France - 73 avenue de Paris, 94165 Saint-Mandé cedex - Contact : contact@meteo.fr

Rédigé par Météo-France avec la contribution des observateurs du réseau nivo-météorologiques. Partenariat : ANMSM (Maires de Stations de Montagne), DSF (Domaines Skiables de France), ADSP (Directeurs de Pistes et de la Sécurité des Stations de Sports d'Hiver) et autres acteurs de la montagne.

Bulletin neige & avalanches par téléphone au **0 892 68 10 20** Service 0,35 € / min + prix appel

RÉPUBLIQUE FRANÇAISE
Liberté Égalité Fraternité

METEO FRANCE
À VOS CÔTÉS, DANS UN CLIMAT QUI CHANGE

Bulletin d'estimation du risque d'avalanche
(valable en dehors des pistes balisées et ouvertes)

MASSIF : Oisans

Rédigé le lundi 9 février 2026 à 16h

Conditions nivo-météo des 7 derniers jours

	mar. 03/02				mer. 04/02				jeu. 05/02				ven. 06/02				sam. 07/02				dim. 08/02				lun. 09/02			
	03h	09h	15h	21h	03h	09h	15h	21h	03h	09h	15h	21h	03h	09h	15h	21h	03h	09h	15h	21h	03h	09h	15h	21h	03h	09h	15h	21h
Météo																												
Vent (km/h)	110	90	75	70	35	40	35	20	25	40	60	60	35	35	30	15	15	10	10	10	15	25	20	15	15	25	15	20
à 3500m																												
Vent (km/h)	95	75	55	55	30	30	25	15	10	25	40	45	20	20	20	10	10	5	10	10	10	25	10	10	5	20	15	15
à 2500m																												

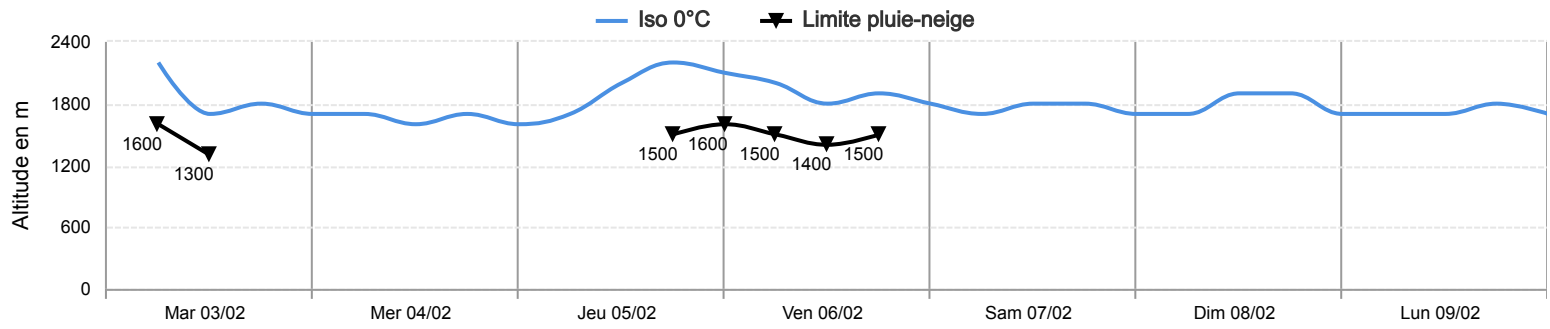

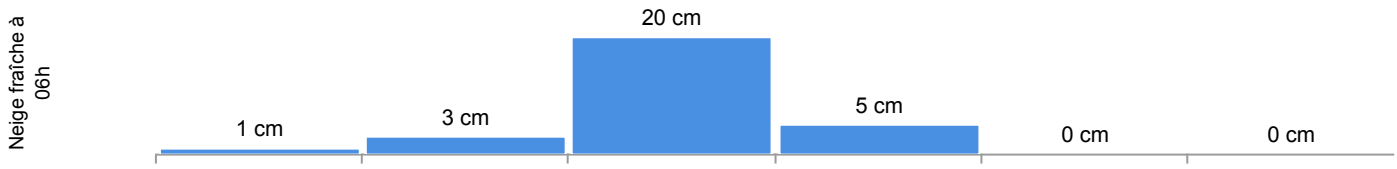

Risque d'avalanche	mar. 03/02	mer. 04/02	jeu. 05/02	ven. 06/02	sam. 07/02	dim. 08/02	lun. 09/02
	4	4	3	3	3	3	3

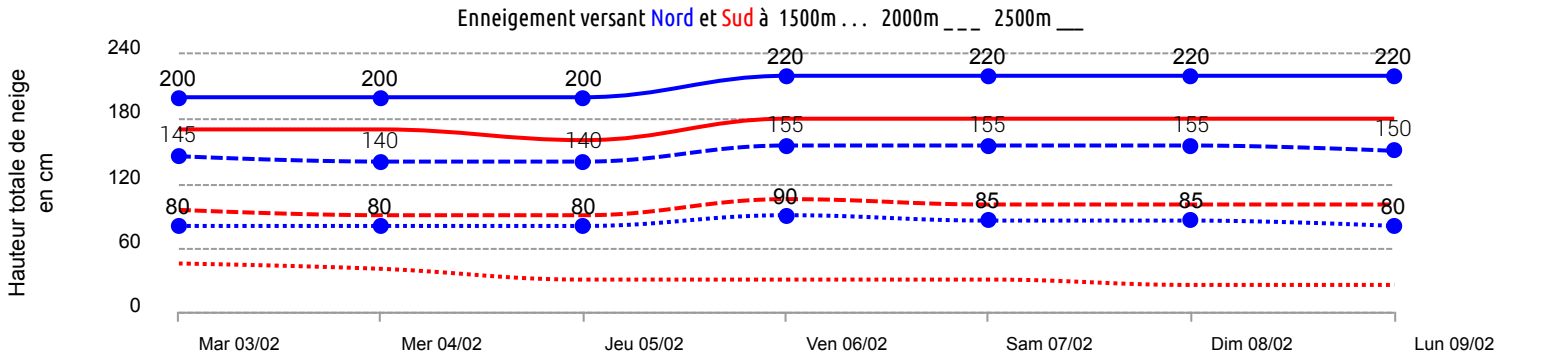

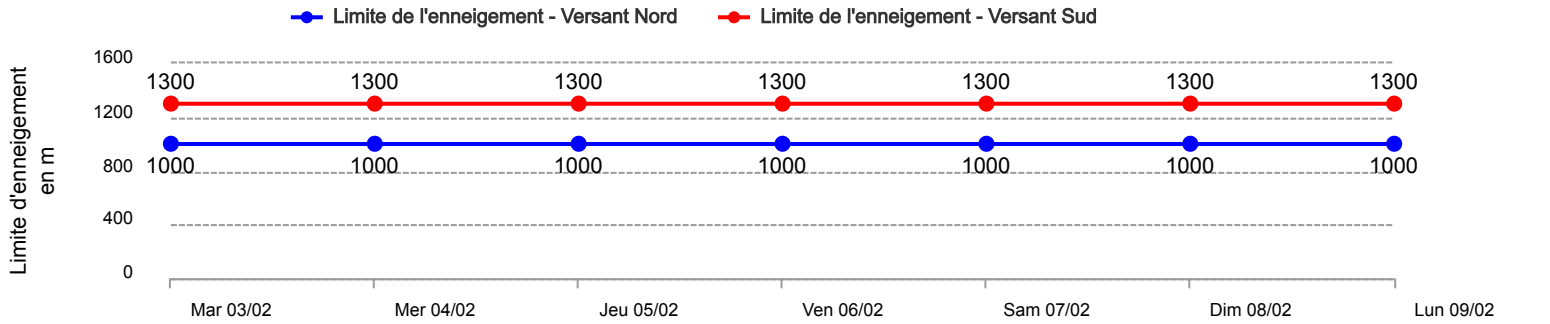

Pour consulter la vigilance en cours, veuillez vous rendre sur le site https://vigilance.meteofrance.fr/fr

Météo-France - 73 avenue de Paris, 94165 Saint-Mandé cedex - Contact : contact@meteo.fr

Rédigé par Météo-France avec la contribution des observateurs du réseau nivo-météorologiques. Partenariat : ANMSM (Maires de Stations de Montagne), DSF (Domaines Skiables de France), ADSP (Directeurs de Pistes et de la Sécurité des Stations de Sports d'Hiver) et autres acteurs de la montagne.

Bulletin neige & avalanches par téléphone au
0 892 68 10 20 Service 0,35 € / min + prix appel