Bulletin d'estimation du risque d'avalanche

(valable en dehors des pistes balisées et ouvertes)

MASSIF : Pays-Basque

Rédigé le lundi 9 février 2026 à 16h

Estimation des risques pour le : MARDI 10 FÉVRIER

HUMIDIFICATION MARQUÉE ET PROGRESSIVE AU FIL DE LA JOURNÉE.

3

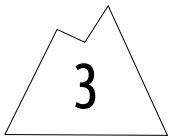

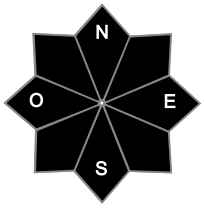

Indice de risque marqué.

Départs spontanés : Humidification importante, progressive et en profondeur à tous niveaux.

Déclenchements provoqués : Difficiles, dans la neige bien humidifiée.

Indices de risque : 5 très fort - 4 fort - 3 marqué - 2 limité - 1 faible -- En noir : les pentes les plus dangereuses

Stabilité du manteau neigeux

Situation avalancheuse typique : neige humide

Déclenchements provoqués :
Les déclenchements restent peu probables et difficiles, le manteau neigeux étant bien humidifié et les plaques formées la veille ont disparu assez rapidement avec le redoux. Cependant, un simple skieur peut déclencher difficilement des avalanches dans la neige bien humidifiée par les averses de pluie de la nuit précédente et celles en cours, engendrant des avalanches moyennes (taille 2) à parfois grandes (taille 3) notamment où les épaisseurs de neige sont les plus importantes.

Départs spontanés :
Avec les averses de pluie marquées ce mardi, poursuivant celles déjà entamées dans la nuit de lundi à mardi, des départs spontanés dans la neige humide sont attendus en toutes expositions avec la limite pluie-neige remontant jusqu'à 2300/2400m. En mobilisant des couches de neige anciennes et en humidifiant le manteau neigeux en profondeur, les avalanches peuvent être de tailles moyennes à grandes dès la matinée. Plus rarement, de très grandes avalanches (taille 4) sont possibles avec les cumuls de pluie importants sur la journée et se poursuivant en soirée et nuit suivante (de mardi à mercredi). Cela peut se produire lorsque le manteau est humidifié bien en profondeur notamment au fur et à mesure de la journée et notamment sur les zones d'accumulation les plus importantes.

Qualité de la neige

Enneigement : Bon pour la saison, mais les crêtes, cols et sommets en expositions ouest sont souvent pelés par le vent dans les expositions ouest. Fonte de la neige attendue ce mardi à tous niveaux.
Limites skiables : Manteau neigeux skiable à partir de 1300/1400m en Nord.
État de la neige : La neige est déjà bien humidifiée et lourde dès la matinée et elle continue à se gorger d'eau au fil de la journée et des averses de pluie. L'humidification du manteau neigeux s'accélère bien au fil de la journée avec des cumuls de pluie marqués ce mardi et à tous niveaux.

Aperçu météo pour le mardi 10 février

	nuit	matin	après-midi	soir

Des averses de pluie marquées sur la journée jusqu'à 2400/2500m, parfois orageuses en fin d'échéance. Vent d'Ouest à Nord-Ouest assez fort.

Pluie-Neige	2 200 m	2 500 m	2 600 m	2 300 m
Iso 0 °C	2 400 m	2 800 m	2 900 m	2 600 m
Vent 1000 m	↗ 45 km/h	↗ 45 km/h	↗ 60 km/h	→ 60 km/h
Vent 2000 m	↗ 60 km/h	↗ 65 km/h	↗ 85 km/h	↗ 90 km/h

Épaisseur de neige hors-piste

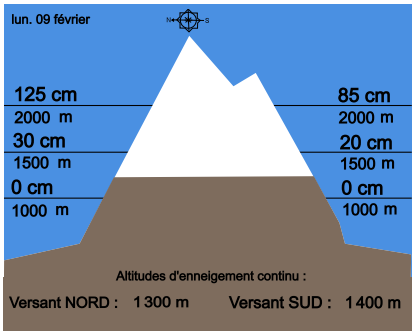

Précipitations à 1800 m

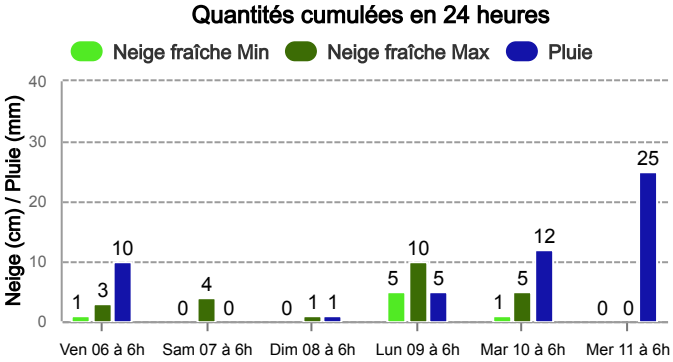

Tendance du mercredi 11 février

3 **Indice de risque marqué**

Maintien d'un risque marqué, le manteau neigeux poursuit son humidification ce mercredi avec des averses de pluie jusqu'à 2300/2400m en journée. Vent restant assez fort à fort d'Ouest à Nord-Ouest.

Pour consulter la vigilance en cours, veuillez vous rendre sur le site https://vigilance.meteofrance.fr/fr

Météo-France - 73 avenue de Paris, 94165 Saint-Mandé cedex - Contact : contact@meteo.fr

Rédigé par Météo-France avec la contribution des observateurs du réseau nivo-météorologiques. Partenariat : ANMSM (Maires de Stations de Montagne), DSF (Domaines Skiables de France), ADSP (Directeurs de Pistes et de la Sécurité des Stations de Sports d'Hiver) et autres acteurs de la montagne.

Bulletin neige & avalanches par téléphone au **0 892 68 10 20** Service 0,35 € / min + prix appel

RÉPUBLIQUE FRANÇAISE
Liberté Égalité Fraternité

METEO FRANCE
À VOS CÔTÉS, DANS UN CLIMAT QUI CHANGE

Bulletin d'estimation du risque d'avalanche
(valable en dehors des pistes balisées et ouvertes)
MASSIF : Pays-Basque

Rédigé le lundi 9 février 2026 à 16h

Conditions nivo-météo des 7 derniers jours

	mar. 03/02				mer. 04/02				jeu. 05/02				ven. 06/02				sam. 07/02				dim. 08/02				lun. 09/02			
	03h	09h	15h	21h	03h	09h	15h	21h	03h	09h	15h	21h	03h	09h	15h	21h	03h	09h	15h	21h	03h	09h	15h	21h	03h	09h	15h	21h
Météo																												
Vent (km/h)	80	80	65	80	100	85	65	70	90	130	95	90	95	95	80	70	70	70	80	90	90	40	45	30	60	50	50	60
à 2000m	↗	↑	↑	↑	↑	↗	→	↗	↑	↑	↑	↗	↗	↗	↗	↗	↗	↗	↑	↑	↑	↘	↘	↑	↗	↗	↗	↗
Vent (km/h)	55	55	40	45	50	40	45	60	80	90	65	60	75	70	60	50	55	55	60	65	60	25	35	20	30	40	30	50
à 1000m	↑	↑	↑	↑	↑	↑	↑	↑	↑	↑	↗	↗	↗	↗	↑	↑	↗	↗	↑	↑	↑	↗	→	↑	↑	↑	↑	↑

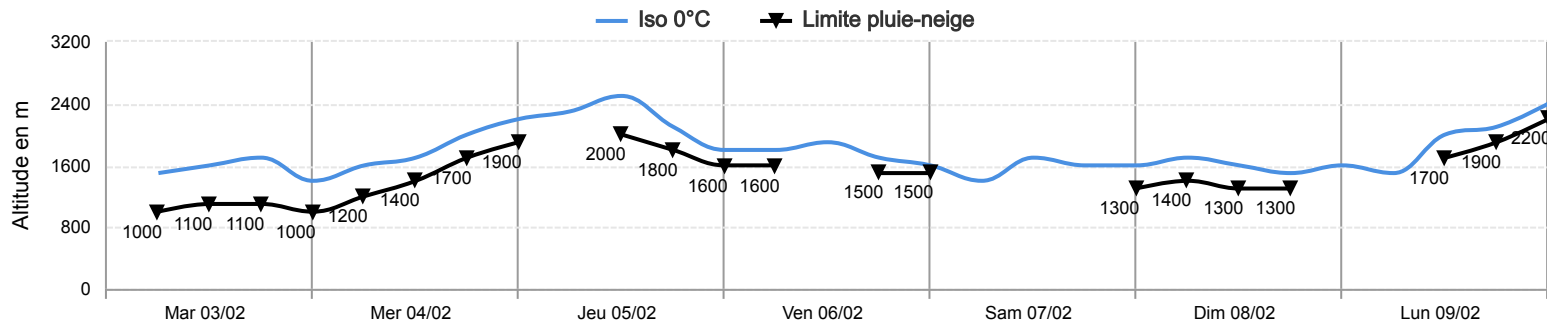

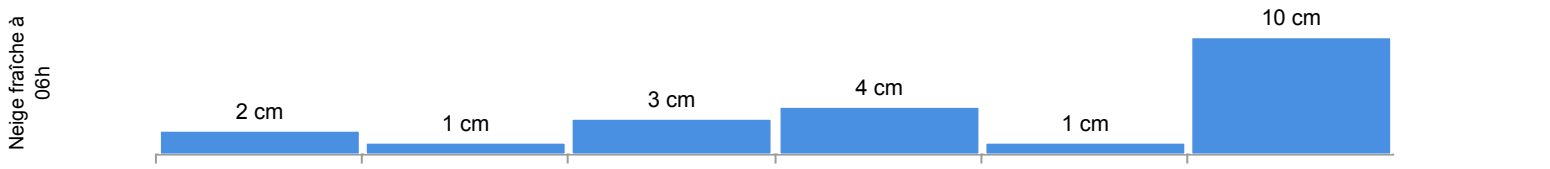

Risque d'avalanche	mar. 03/02	mer. 04/02	jeu. 05/02	ven. 06/02	sam. 07/02	dim. 08/02	lun. 09/02
	2	2	2	2	2	2	2

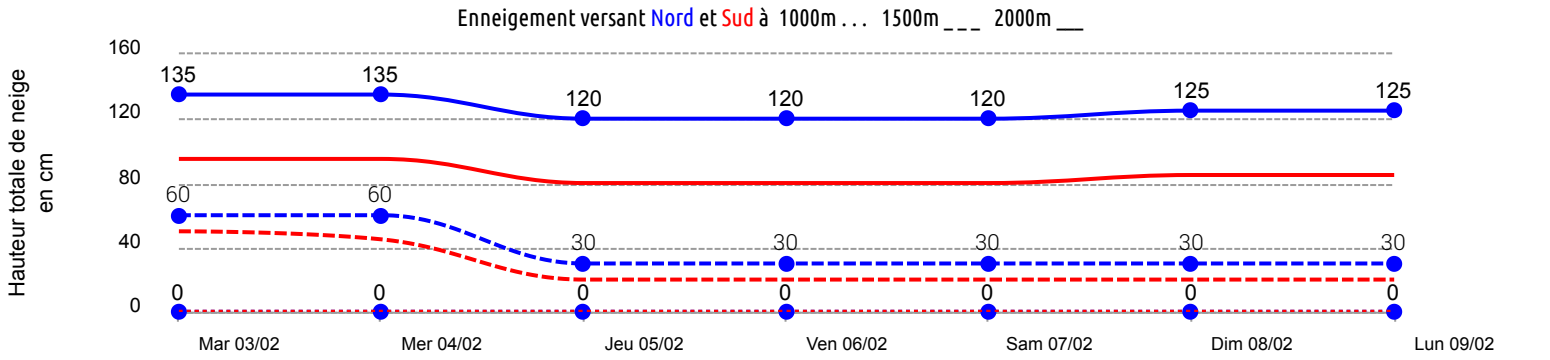

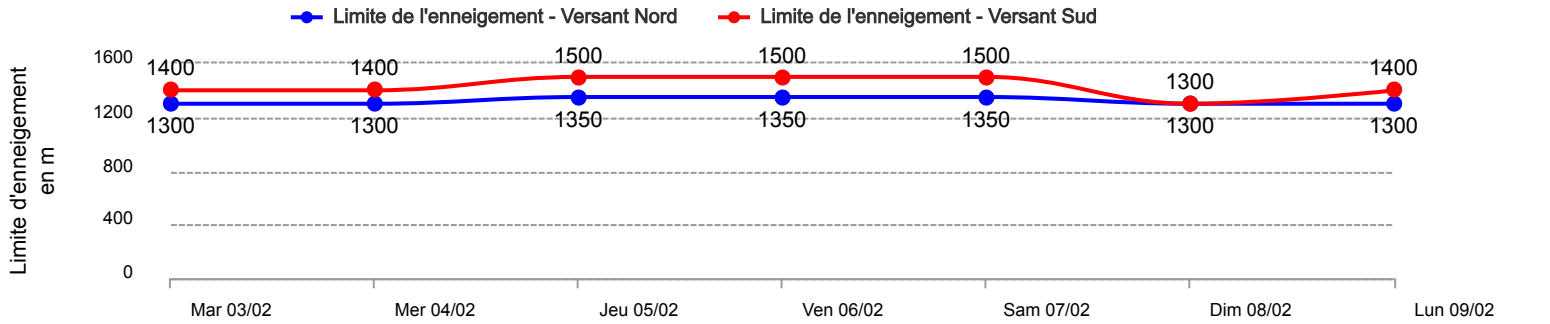

Pour consulter la vigilance en cours, veuillez vous rendre sur le site https://vigilance.meteofrance.fr/fr

Météo-France - 73 avenue de Paris, 94165 Saint-Mandé cedex - Contact : contact@meteo.fr

Rédigé par Météo-France avec la contribution des observateurs du réseau nivo-météorologiques. Partenariat : ANMSM (Maires de Stations de Montagne), DSF (Domaines Skiables de France), ADSP (Directeurs de Pistes et de la Sécurité des Stations de Sports d'Hiver) et autres acteurs de la montagne.

Bulletin neige & avalanches par téléphone au
0 892 68 10 20 Service 0,35 € / min + prix appel