Bulletin d'estimation du risque d'avalanche

(valable en dehors des pistes balisées et ouvertes)

MASSIF : Pelvoux

Rédigé le lundi 9 février 2026 à 16h

Estimation des risques pour le : MARDI 10 FÉVRIER

INSTABILITÉS ENCORE FACILES À DÉCLENCHER. EN UBACS D'ALTITUDE, SOUVENT VOLUMINEUSES

3

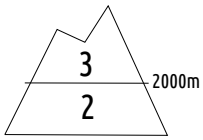

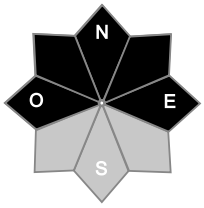

Au-dessus de 2000m indice de risque marqué, plus bas indice limité.

Départs spontanés : éventuels départs superficiels en neige humide. Rares plaques en haute altitude.

Déclenchements provoqués : avalanches de plaque, encore faciles à déclencher. En versants froids d'altitude, parfois grandes, déclenchables aussi parfois à distance.

Indices de risque : 5 très fort - 4 fort - 3 marqué - 2 limité - 1 faible -- En noir : les pentes les plus dangereuses

Stabilité du manteau neigeux

Situation avalancheuse typique : couche fragile persistante neige ventée

Déclenchements provoqués : instabilités en place en versants est / nord / ouest au-dessus de 2000 m environ. Elles peuvent être difficiles à identifier, car souvent d'aspect poudreux en surface. Déclenchement, parfois à distance, encore possible au passage d'un seul skieur, notamment sur les croupes et bords de couloir où le manteau neigeux est moins épais. Avalanches de plaque de taille moyenne à grande (taille 2 à 3), avec des cassures larges et épaisses, notamment au-delà de 2300/2400 m. En effet, présence d'une importante couche fragile enfouie à la base du manteau neigeux localement réactive.
Par ailleurs en altitude, quelques plaques plus superficielles en place en toute orientation dans la neige récente ventée, plutôt à proximité des crêtes. D'autres possiblement en formation à haute altitude avec le transport par le vent. Faciles à déclencher, générant des avalanches de petite taille, voire moyenne, mais peuvent déclencher en cascade les plaques plus volumineuses décrites précédemment.
Sous 2000 m, ainsi qu'en adrets raides d'altitude, l'instabilité est plus limitée. La neige récente a pris une bonne cohésion, avec la récente humidification, et les couches fragiles persistantes sont moins généralisées.
En fin de journée de mardi, avec les nouvelles chutes de neige attendues en altitude et le vent, nouvelles plaques en formation.

Départs spontanés : encore d'éventuels départs ponctuels de neige humidifiée avec le redoux temporaire en journée. Taille petite, rarement moyenne. En haute altitude, rares plaques cédant spontanément sous l'effet de la neige transportée par le vent. Taille moyenne, grande non exclue.
En fin de journée, avec le renforcement des précipitations, l'activité naturelle est en nette augmentation. En neige humide jusqu'à 1800/2000 m, en neige sèche au-dessus.

Qualité de la neige

L'enneigement est excédentaire pour un début février, en particulier en vallées.
Données observées : 196 cm à la Nivôse de Écrins vers 3000 m, 185 cm au Pré de Mme Carle à 1900 m, 120 cm au hameau de Dormillouse à 1730 m.

Limite d'enneigement skiable : la plupart des itinéraires sont skiables dès les fonds de vallées.

État de la neige de surface : quelques cm de neige fraiche sur de la neige récente en altitude, restée poudreuse et légère en versants froids au-dessus de 1700/1800 m, et parfois densifiée ou cartonnée par le vent près des crêtes. En versants ensoleillés, sur neige récente plus tassée et croutée sous 2400/2500 m.

Aperçu météo pour le mardi 10 février

Quelques cm de neige entre la fin de nuit/matinée. Dégradation plus franche en soirée/première partie de nuit de mardi.

	nuit	matin	après-midi	soir
Pluie-Neige	1 000 m	1 000 m	1 700 m	1 400 m
Iso 0 °C	1 500 m	1 600 m	2 000 m	1 800 m
Vent 2000 m	10 km/h	15 km/h	20 km/h	20 km/h
Vent 3000 m	30 km/h	30 km/h	30 km/h	50 km/h

Épaisseur de neige hors-piste

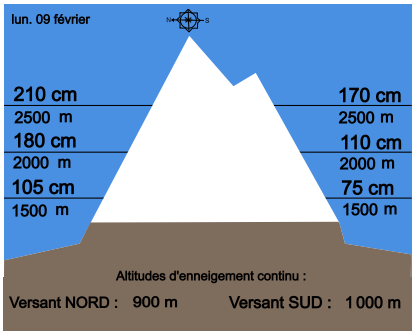

Précipitations à 1800 m

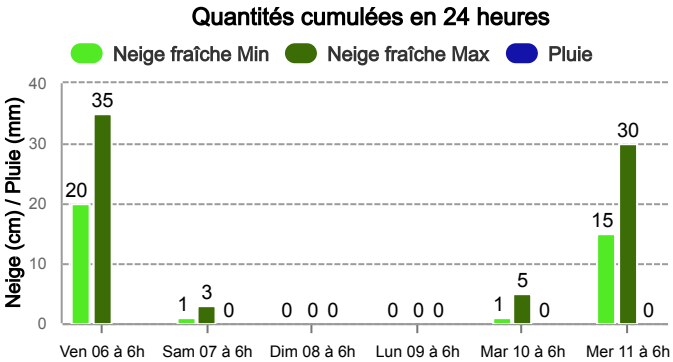

Tendance du mercredi 11 février

3 **Indice de risque marqué**

Risque en hausse. Formation de nouvelles instabilités.

Pour consulter la vigilance en cours, veuillez vous rendre sur le site https://vigilance.meteofrance.fr/fr

Météo-France - 73 avenue de Paris, 94165 Saint-Mandé cedex - Contact : contact@meteo.fr

Rédigé par Météo-France avec la contribution des observateurs du réseau nivo-météorologiques. Partenariat : ANMSM (Maires de Stations de Montagne), DSF (Domaines Skiables de France), ADSP (Directeurs de Pistes et de la Sécurité des Stations de Sports d'Hiver) et autres acteurs de la montagne.

Bulletin neige & avalanches par téléphone au

0 892 68 10 20 Service 0,35 € / min + prix appel

Bulletin d'estimation du risque d'avalanche

(valable en dehors des pistes balisées et ouvertes)

MASSIF : Pelvoux

Rédigé le lundi 9 février 2026 à 16h

Conditions nivo-météo des 7 derniers jours

	mar. 03/02				mer. 04/02				jeu. 05/02				ven. 06/02				sam. 07/02				dim. 08/02				lun. 09/02			
	03h	09h	15h	21h	03h	09h	15h	21h	03h	09h	15h	21h	03h	09h	15h	21h	03h	09h	15h	21h	03h	09h	15h	21h	03h	09h	15h	21h
Météo																												
Vent (km/h)	100	70	40	30	30	30	20	15	15	30	45	30	25	30	25	20	20	10	10	10	10	15	20	20	10	15	15	20
à 3000m																												
Vent (km/h)	60	35	25	15	15	15	15	10	10	10	20	20	5	10	15	10	5	5	10	5	5	15	20	20	5	5	10	10
à 2000m																												

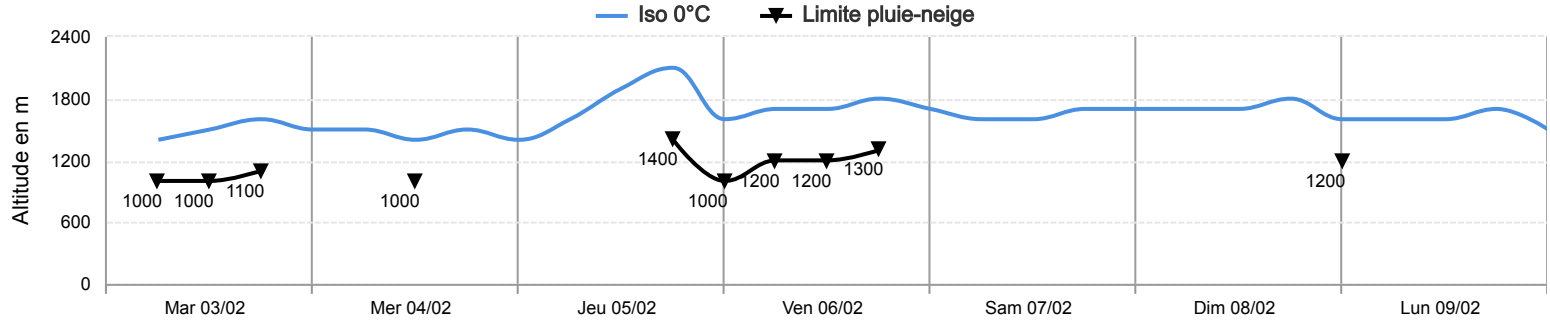

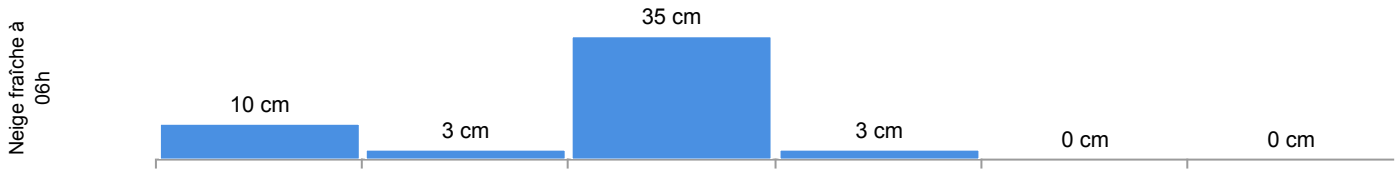

Risque d'avalanche	mar. 03/02	mer. 04/02	jeu. 05/02	ven. 06/02	sam. 07/02	dim. 08/02	lun. 09/02
	4	4	3	4	4	3	3

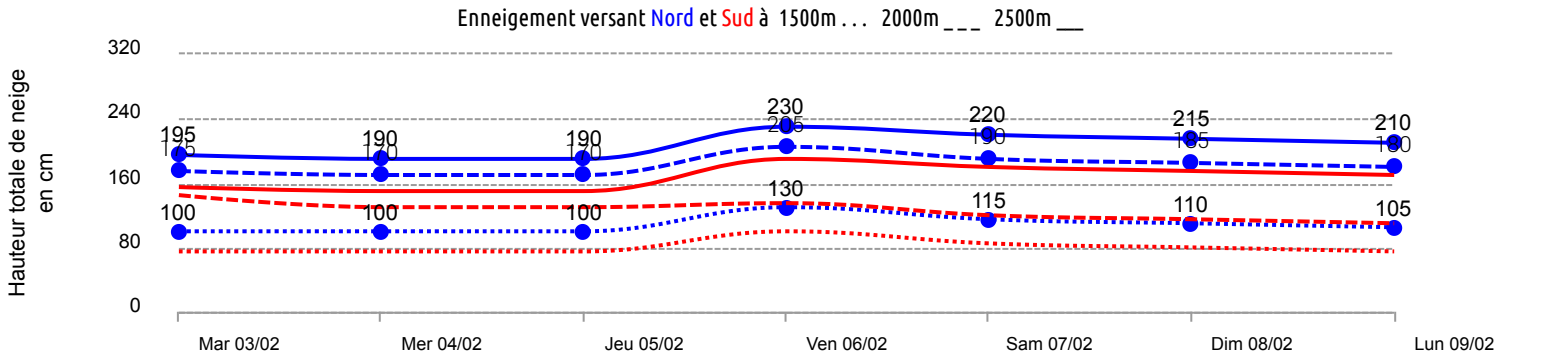

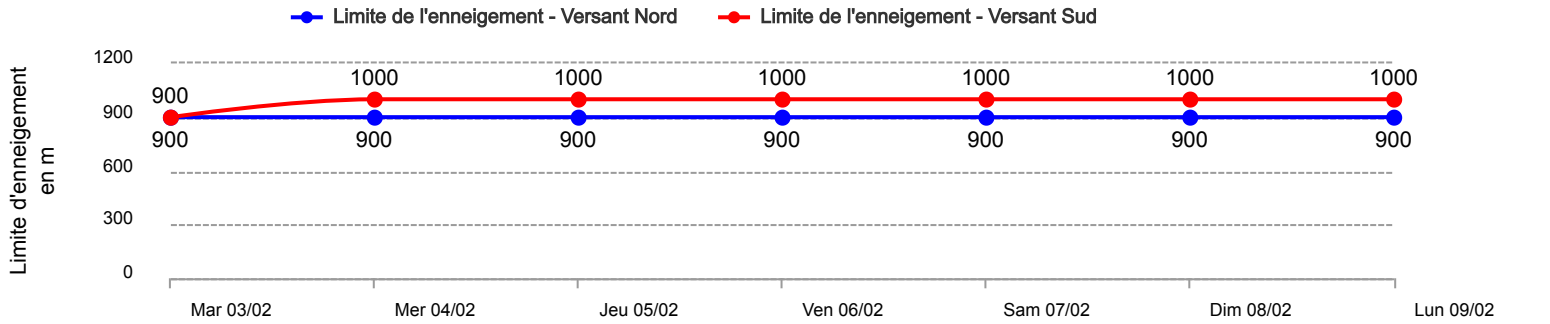

Pour consulter la vigilance en cours, veuillez vous rendre sur le site https://vigilance.meteofrance.fr/fr

Météo-France - 73 avenue de Paris, 94165 Saint-Mandé cedex - Contact : contact@meteo.fr

Bulletin neige & avalanches par téléphone au

0 892 68 10 20 Service 0,35 € / min + prix appel

Rédigé par Météo-France avec la contribution des observateurs du réseau nivo-météorologiques. Partenariat : ANMSM (Maires de Stations de Montagne), DSF (Domaines Skiables de France), ADSP (Directeurs de Pistes et de la Sécurité des Stations de Sports d'Hiver) et autres acteurs de la montagne.