Bulletin d'estimation du risque d'avalanche

(valable en dehors des pistes balisées et ouvertes)

MASSIF : Queyras

Rédigé le lundi 9 février 2026 à 16h

Estimation des risques pour le : MARDI 10 FÉVRIER

INSTABILITÉS ENCORE FACILES À DÉCLENCHER. EN UBACS D'ALTITUDE, SOUVENT VOLUMINEUSES

3

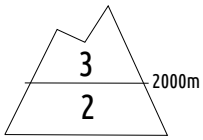

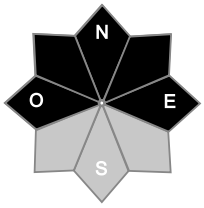

Au-dessus de 2000m indice de risque marqué, plus bas indice limité.

Départs spontanés : éventuels départs superficiels en neige humide. Rares plaques en haute altitude.

Déclenchements provoqués : avalanches de plaque, encore faciles à déclencher. En versants froids d'altitude, parfois grandes, déclenchables aussi à distance.

Indices de risque : 5 très fort - 4 fort - 3 marqué - 2 limité - 1 faible -- En noir : les pentes les plus dangereuses

Stabilité du manteau neigeux

Situation avalancheuse typique :

couche fragile persistante

neige ventée

Déclenchements provoqués : instabilités en place en versants est / nord / ouest au-dessus de 2000 m environ. Elles peuvent être difficiles à identifier, car souvent d'aspect poudreux en surface. Déclenchement encore possible au passage d'un seul skieur, souvent à distance. Avalanches de plaque de taille moyenne à grande (taille 2 à 3), avec des cassures larges et épaisses, notamment au-delà de 2300/2400 m. En effet, présence d'une importante couche fragile enfouie à la base du manteau neigeux encore réactive.
Par ailleurs en altitude, quelques plaques plus superficielles en place en toute orientation dans la neige récente ventée, plutôt à proximité des crêtes. D'autres possiblement en formation à haute altitude avec le transport par le vent. Faciles à déclencher, générant des avalanches de petite taille, voire moyenne, mais peuvent déclencher en cascade les plaques plus volumineuses décrites précédemment.
Sous 2000 m, ainsi qu'en adrets raides d'altitude, l'instabilité est plus limitée. La neige récente a pris une bonne cohésion, avec la récente humidification, et les couches fragiles persistantes sont moins généralisées.
En fin de journée de mardi, avec les nouvelles chutes de neige attendues en altitude et le vent, nouvelles plaques en formation.

Départs spontanés : encore d'éventuels départs ponctuels de neige humidifiée avec le redoux temporaire en journée. Taille petite, rarement moyenne. En haute altitude, rares plaques cédant spontanément sous l'effet de la neige transportée par le vent. Taille moyenne, grande non exclue.
En fin de journée, avec le renforcement des précipitations, l'activité naturelle est en augmentation. En neige humide jusqu'à 1800/2000 m, en neige sèche au-dessus.

Qualité de la neige

L'enneigement est proche des normales dans les ubacs, voire excédentaire vers le Briançonnais, mais reste déficitaire dans les adrets d'altitude, notamment dans le Haut Guil.
Données observées : 140cm en versant nord du col Izoard à 2300 m, 58 cm à la Nivôse du Col Agnel à 2630 m, 64 cm à Ristolas à 1670 m.

Limite d'enneigement skiable : dès 1000/1300 m en ubacs, plutôt 1500/1700 m en adrets avec peu de sous-couche jusqu'à haute altitude, notamment dans le Haut Guil.

État de la neige de surface : neige récente, restée poudreuse et légère en versants froids au-dessus de 1700/1800 m, et parfois densifiée ou cartonnée par le vent près des crêtes. En versants ensoleillés, neige récente plus tassée et croutée sous 2400/2500 m.

Aperçu météo pour le mardi 10 février

	nuit	matin	après-midi	soir
	Au mieux quelques cm de neige entre la fin de nuit/matinée. Nouvelle dégradation en soirée/première partie de nuit de mardi.			
Pluie-Neige	1 200 m	1 200 m	1 700 m	1 400 m
Iso 0 °C	1 500 m	1 700 m	2 000 m	1 800 m
Vent 2000 m	↑ 10 km/h	→ 20 km/h	→ 25 km/h	→ 25 km/h
Vent 3000 m	→ 30 km/h	→ 35 km/h	→ 40 km/h	→ 50 km/h

Épaisseur de neige hors-piste

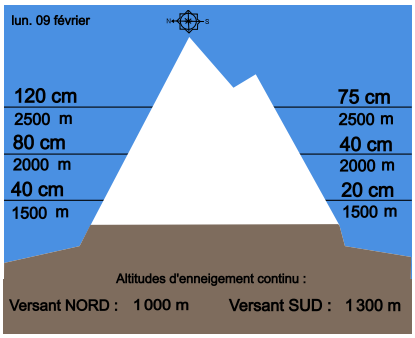

Précipitations à 1800 m

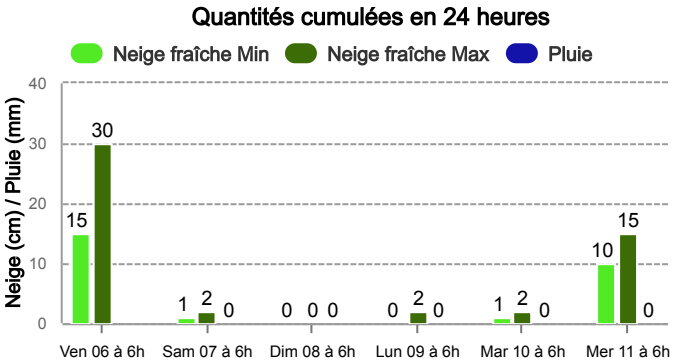

Tendance du mercredi 11 février

3

Indice de risque marqué

Risque en hausse. Formation de nouvelles instabilités.

Pour consulter la vigilance en cours, veuillez vous rendre sur le site https://vigilance.meteofrance.fr/fr

Météo-France - 73 avenue de Paris, 94165 Saint-Mandé cedex - Contact : contact@meteo.fr

Rédigé par Météo-France avec la contribution des observateurs du réseau nivo-météorologiques. Partenariat : ANMSM (Maires de Stations de Montagne), DSF (Domaines Skiables de France), ADSP (Directeurs de Pistes et de la Sécurité des Stations de Sports d'Hiver) et autres acteurs de la montagne.

Bulletin neige & avalanches par téléphone au

0 892 68 10 20 Service 0,35 € / min + prix appel

RÉPUBLIQUE FRANÇAISE
Liberté Égalité Fraternité

METEO FRANCE
À VOS CÔTÉS, DANS UN CLIMAT QUI CHANGE

Bulletin d'estimation du risque d'avalanche

(valable en dehors des pistes balisées et ouvertes)

MASSIF : Queyras

Rédigé le lundi 9 février 2026 à 16h

Conditions nivo-météo des 7 derniers jours

	mar. 03/02				mer. 04/02				jeu. 05/02				ven. 06/02				sam. 07/02				dim. 08/02				lun. 09/02			
	03h	09h	15h	21h	03h	09h	15h	21h	03h	09h	15h	21h	03h	09h	15h	21h	03h	09h	15h	21h	03h	09h	15h	21h	03h	09h	15h	21h
Météo																												
Vent (km/h)	80	60	40	40	30	30	25	30	20	25	40	25	35	35	40	25	25	15	15	10	10	20	35	35	15	10	15	20
à 3000m																												
Vent (km/h)	40	35	25	15	15	20	15	10	10	10	10	15	5	15	25	10	10	10	15	5	5	15	30	30	10	10	15	10
à 2000m																												

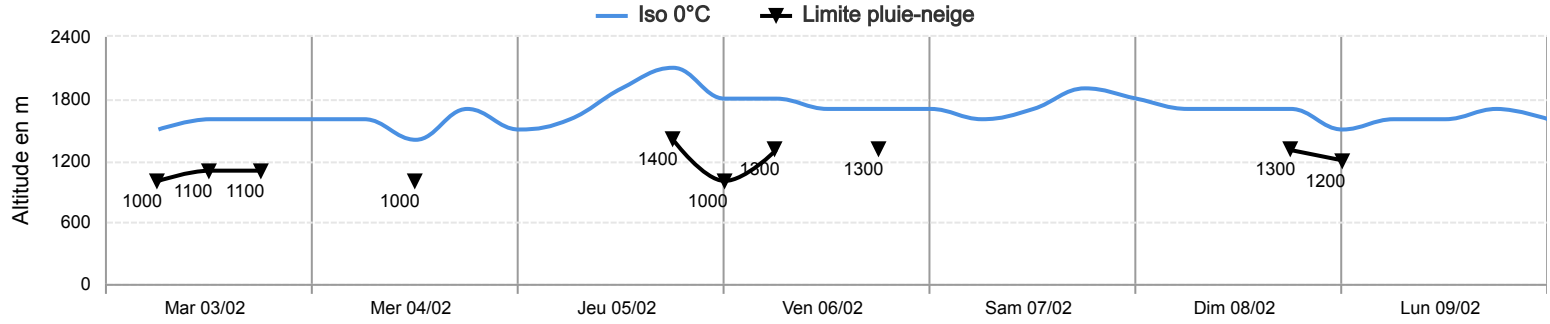

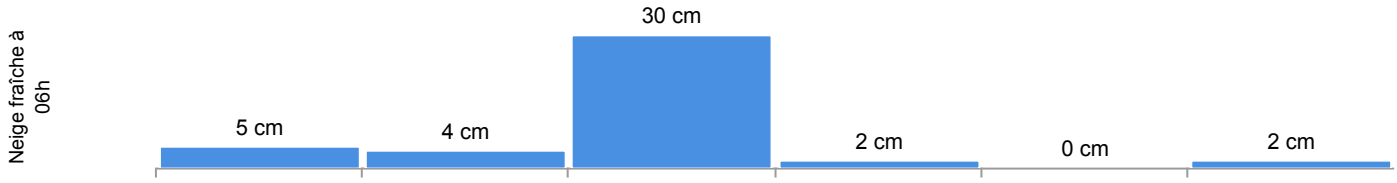

Risque d'avalanche	mar. 03/02	mer. 04/02	jeu. 05/02	ven. 06/02	sam. 07/02	dim. 08/02	lun. 09/02
	4	4	3	4	4	3	3

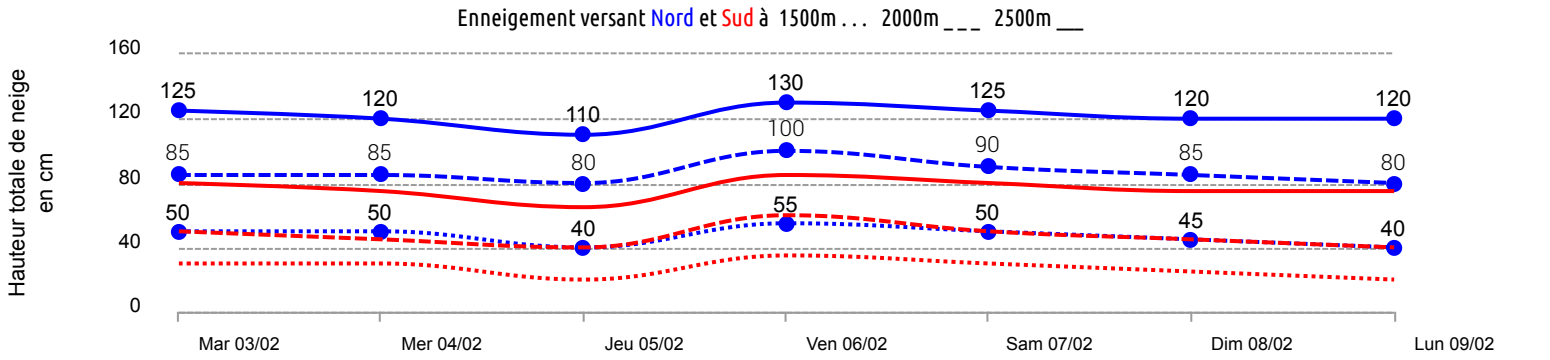

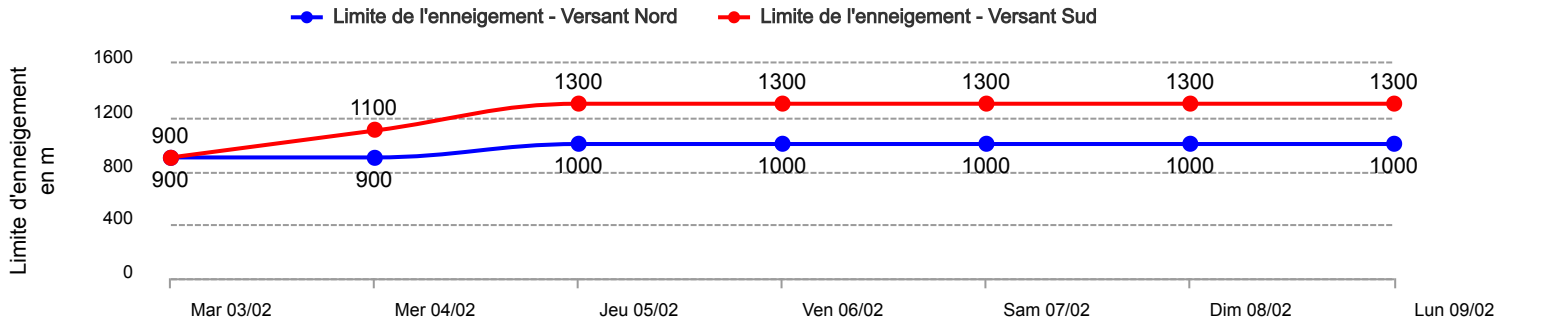

Pour consulter la vigilance en cours, veuillez vous rendre sur le site https://vigilance.meteofrance.fr/fr

Météo-France - 73 avenue de Paris, 94165 Saint-Mandé cedex - Contact : contact@meteo.fr

Bulletin neige & avalanches par téléphone au

0 892 68 10 20 Service 0,35 € / min + prix appel

Rédigé par Météo-France avec la contribution des observateurs du réseau nivo-météorologiques. Partenariat : ANMSM (Maires de Stations de Montagne), DSF (Domaines Skiables de France), ADSP (Directeurs de Pistes et de la Sécurité des Stations de Sports d'Hiver) et autres acteurs de la montagne.