Bulletin d'estimation du risque d'avalanche

(valable en dehors des pistes balisées et ouvertes)

MASSIF : Ubaye

Rédigé le lundi 9 février 2026 à 16h

Estimation des risques pour le : MARDI 10 FÉVRIER

MANTEAU NEIGEUX ENCORE PEU STABILISÉ. INSTABILITÉS LOCALEMENT VOLUMINEUSES

3

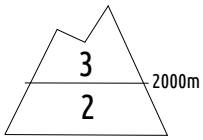

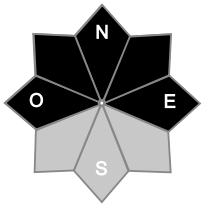

Au-dessus de 2000m indice de risque marqué, plus bas indice limité.

Départs spontanés : peu probables, ou superficiels en neige humide.

Déclenchements provoqués : instabilités encore faciles à déclencher, parfois volumineuses.

Indices de risque : 5 très fort - 4 fort - 3 marqué - 2 limité - 1 faible -- En noir : les pentes les plus dangereuses

Stabilité du manteau neigeux

Situation avalancheuse typique : couche fragile persistante neige ventée

Déclenchements provoqués :
- le manteau neigeux reste peu stabilisé dans de nombreuses pentes au-dessus de 2000 m environ, dans les orientations ouest, nord et est. Des instabilités liées à la présence de couches fragiles persistantes sont toujours en place, et localement facilement déclenchables par un skieur ou un randonneur, même à distance. Elles sont difficilement identifiables, car souvent d'aspect poudreux, voire recouvertes d'un léger saupoudrage de neige fraîche ce mardi matin. Elles engendrent des avalanches de taille moyenne à grande (2 à 3), avec des cassures parfois larges et épaisses.
- Quelques instabilités de surface sont également présentes, liées à la présence de plaques dans la neige récente. Elles peuvent être présentes en toutes orientations, plutôt au dessus de 2000 m. En cours de journée, quelques nouvelles plaques peuvent également se former dans les secteurs où la neige récente est encore légère, et transportable par le vent d'ouest à nord-ouest, plutôt au dessus de 2400 m environ. D'aspect poudreux ou légèrement travaillé par le vent, ces instabilités se trouvent généralement à proximité des crêtes et ruptures de pentes. Elles peuvent occasionner des avalanches de taille petite à parfois moyenne (1 à 2), mais un premier départ en surface peut solliciter la couche fragile enfouie en profondeur décrite précédemment, et emporter la totalité du manteau neigeux dans une avalanche de grande taille (taille 3).
- Sous 2000 m, ainsi qu'en adrets raides d'altitude, le risque de déclenchement est plus limité avec un manteau neigeux humidifié en surface.

Départs spontanés : peu probables. Un éventuel départ ponctuel de petite ampleur (taille 1) en neige récente humidifiée n'est pas exclu en pentes raides.

Autres : à partir de mardi soir, les chutes de neige ventée entrainent la formation de nombreuses nouvelles instabilités sous forme de plaques plus ou moins durcies par le vent. Sous la limite pluie-neige, initialement autour de 1800 m environ avant de s'abaisser dans la nuit, la pluie peut également faire partir des avalanches de neige humide généralement de petite taille. Plus de détails dans le prochain bulletin.

Qualité de la neige

Enneigement bon, voire excédentaire pour un début février.
Données observées : 103 cm au-dessus de Larche à 2270 m, 10 cm à Barcelonnette à 1200 m.

Enneigement skiable dès 1300/1400 m en terrain favorable, mais peu de sous-couche sous 1600 m en général.

État de la neige en surface : mardi matin, léger saupoudrage de neige fraîche, tombée sur une neige croutée en adrets jusque vers 2000/2200 m, plus bas en ubacs (1900/2000 m). Sinon neige récente en quantité, encore souvent poudreuse, localement densifiée par le vent. Corniches et congères parfois volumineuses en place.

Aperçu météo pour le mardi 10 février

	nuit	matin	après-midi	soir

Neige faible en fin de nuit et matinée, quelques flocons épars en journée, puis arrivée d'une nouvelle perturbation active en soirée.

	nuit	matin	après-midi	soir
Pluie-Neige	1 000 m	1 200 m	1 600 m	1 600 m
Iso 0 °C	1 600 m	1 800 m	1 900 m	1 900 m
Vent 2000 m	↗ 10 km/h	→ 15 km/h	→ 20 km/h	→ 20 km/h
Vent 3000 m	→ 30 km/h	→ 35 km/h	→ 45 km/h	→ 65 km/h

Épaisseur de neige hors-piste

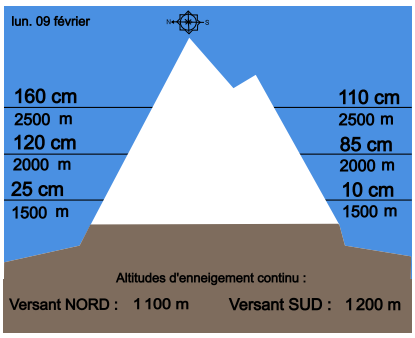

Précipitations à 1800 m

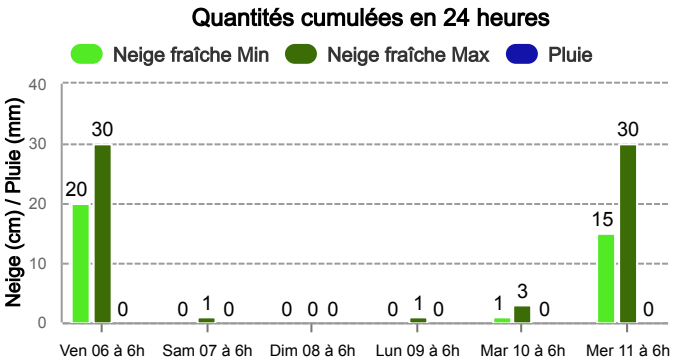

Tendance du mercredi 11 février

3 **Indice de risque marqué**

Risque en hausse avec les chutes de neige significatives et bien ventées de la nuit de mardi à mercredi. Nouvelles plaques parfois épaisses, venant s'ajouter aux instabilités déjà en place.

Pour consulter la vigilance en cours, veuillez vous rendre sur le site https://vigilance.meteofrance.fr/fr

Météo-France - 73 avenue de Paris, 94165 Saint-Mandé cedex - Contact : contact@meteo.fr

Rédigé par Météo-France avec la contribution des observateurs du réseau nivo-météorologiques. Partenariat : ANMSM (Maires de Stations de Montagne), DSF (Domaines Skiables de France), ADSP (Directeurs de Pistes et de la Sécurité des Stations de Sports d'Hiver) et autres acteurs de la montagne.

Bulletin neige & avalanches par téléphone au **0 892 68 10 20** Service 0,35 € / min + prix appel

RÉPUBLIQUE FRANÇAISE
Liberté Égalité Fraternité

METEO FRANCE
À VOS CÔTÉS, DANS UN CLIMAT QUI CHANGE

Bulletin d'estimation du risque d'avalanche

(valable en dehors des pistes balisées et ouvertes)

MASSIF : Ubaye

Rédigé le lundi 9 février 2026 à 16h

Conditions nivo-météo des 7 derniers jours

	mar. 03/02				mer. 04/02				jeu. 05/02				ven. 06/02				sam. 07/02				dim. 08/02				lun. 09/02			
	03h	09h	15h	21h	03h	09h	15h	21h	03h	09h	15h	21h	03h	09h	15h	21h	03h	09h	15h	21h	03h	09h	15h	21h	03h	09h	15h	21h
Météo																												
Vent (km/h)	70	45	35	25	25	25	20	20	25	30	40	40	30	35	35	25	30	15	15	10	10	25	25	15	15	25	25	30
à 3000m																												
Vent (km/h)	45	35	25	20	20	20	20	10	10	15	25	25	20	20	25	10	10	10	10	10	10	15	20	15	10	10	15	10
à 2000m																												

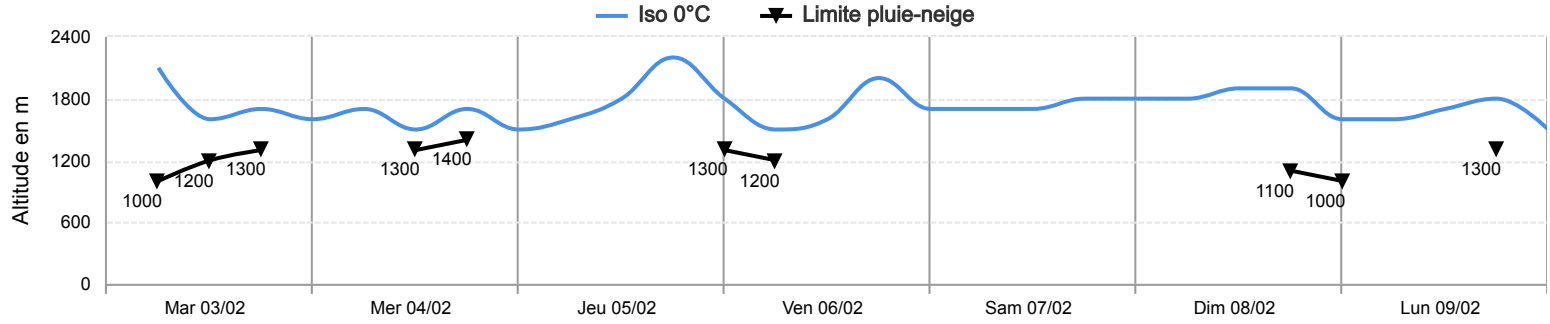

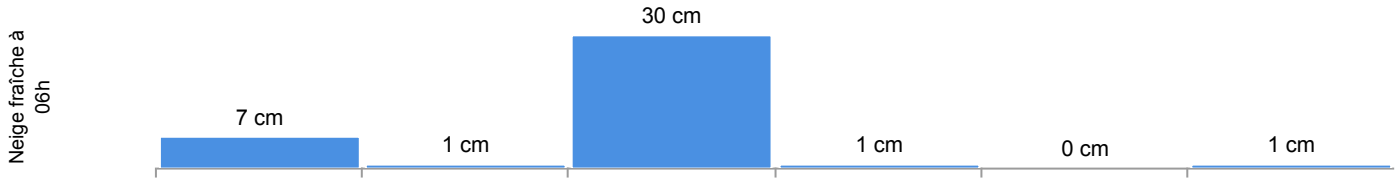

Risque d'avalanche	mar. 03/02	mer. 04/02	jeu. 05/02	ven. 06/02	sam. 07/02	dim. 08/02	lun. 09/02
	4	4	3	4	4	3	3

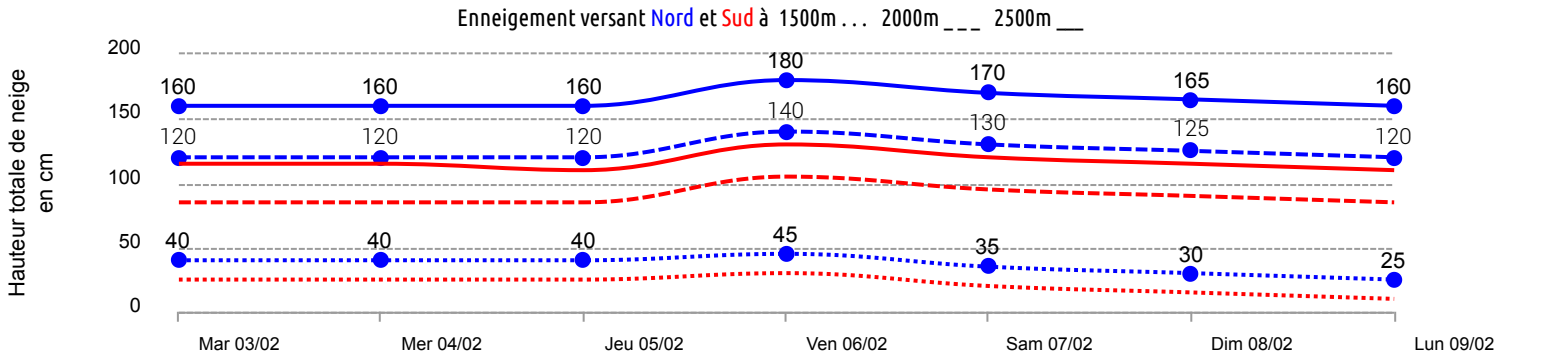

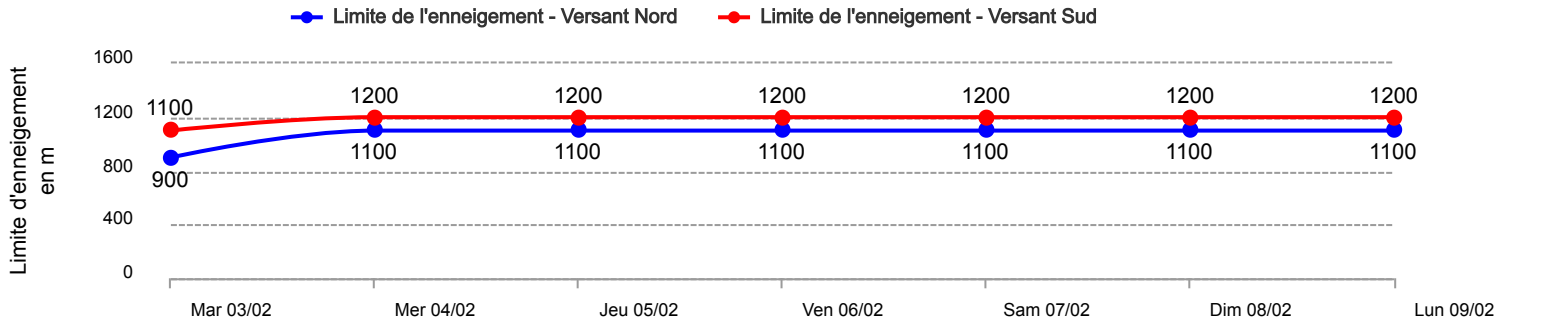

Pour consulter la vigilance en cours, veuillez vous rendre sur le site https://vigilance.meteofrance.fr/fr

Météo-France - 73 avenue de Paris, 94165 Saint-Mandé cedex - Contact : contact@meteo.fr

Rédigé par Météo-France avec la contribution des observateurs du réseau nivo-météorologiques. Partenariat : ANMSM (Maires de Stations de Montagne), DSF (Domaines Skiables de France), ADSP (Directeurs de Pistes et de la Sécurité des Stations de Sports d'Hiver) et autres acteurs de la montagne.

Bulletin neige & avalanches par téléphone au
0 892 68 10 20 Service 0,35 € / min + prix appel