Bulletin d'estimation du risque d'avalanche

(valable en dehors des pistes balisées et ouvertes)

MASSIF : Vercors

Rédigé le lundi 9 février 2026 à 16h

Estimation des risques pour le : MARDI 10 FÉVRIER

PLAQUES A VENT EN VERSANTS FROIDS D'ALTITUDE. EN SOIREE, NOMBREUSES COULEES HUMIDES SOUS LA PLUIE

3

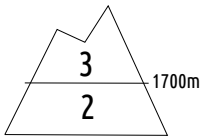

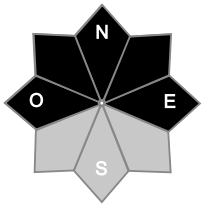

Au-dessus de 1700m indice de risque marqué, plus bas indice limité.

Départs spontanés : Quelques coulées humides sous la pluie en journée. Devenant nombreuses en soirée.

Déclenchements provoqués : Quelques plaques formées par le vent de Sud-Ouest dans la nuit et en journée.

Indices de risque : 5 très fort - 4 fort - 3 marqué - 2 limité - 1 faible -- En noir : les pentes les plus dangereuses

Stabilité du manteau neigeux

Situation avalancheuse typique : neige ventée neige humide

En journée : Faible passage perturbé dans la nuit et en matinée de mardi, avec 5 à 10cm dés 1500m. Formation de quelques plaques sous le vent d'Ouest / Sud-Ouest.
Déclenchements provoqués : Au-dessus de 1700m environ et surtout dans les versants froids, de nouvelles plaques se forment sous le vent de Sud-Ouest. Ces plaques peuvent être assez réactives, mais resteraient d'épaisseurs et de largeurs modestes. Les petites chutes de neige de la nuit apportent toutefois un peu de neige transportable, favorisant la formation de ces plaques. Plaques parfois difficiles à identifier, pouvant être d'aspect poudreuse plus ou moins dense...
Observables : Neige d'aspect ventée en surface, neige plus légère en profondeur, fissures sous les skis.
Départs spontanés : Sous 1300 puis 1500m, petites coulées humides possibles dans la nuit et en matinée sous la pluie. Quelques avalanches de fonds possibles sur les talus. Au-dessus de 1700m environ, petites coulées de neige fraîche possibles sous le vent de Sud-Ouest.

Soirée: En soirée, des pluies soutenues s'invitent jusqu'à 2000 voire 2200m, alourdissant fortement le manteau. Sous ces pluies, **de nombreuses avalanches de neige humides ou avalanches de fond sont possibles, souvent de tailles moyennes**. Plus nombreuses et plus grosses en versants Nord où les quantités de neige sont plus importantes et où le manteau est resté plus froid.

Qualité de la neige

Qualification de l'enneigement : L'enneigement s'est récemment dégradé aux basses altitudes, sous les sapins mais reste correct pour la saison dès la moyenne montagne et dans les combes Nord.
Limites skiables : Vers 1100/1400 m, sur les pistes forestières/clairières...

Qualité de la neige mardi : Sous 1700/1800m et au Sud, neige croutée par regel , s'humidifiant lors de brèves éclaircies (ski parfois difficile en pentes peu tracées) . En faces Nord d'altitude reste un peu de neige poudreuse, reposant sur des sous couches plus ventées. Un peu de vent de Sud possible vers les sommets ?

Aperçu météo pour le mardi 10 février

	nuit	matin	après-midi	soir

Faiblement perturbé en journée, avec de la neige sous 1300 puis 1500m. En soirée, pluies fortes jusqu'en haut du massif.

	nuit	matin	après-midi	soir
Pluie-Neige	1 200 m	1 400 m	1 700 m	2 000 m
Iso 0 °C	1 800 m	1 800 m	2 100 m	2 300 m
Vent 1500 m	↑ 40 km/h	↑ 30 km/h	↑ 35 km/h	↑ 50 km/h
Vent 2000 m	↗ 50 km/h	→ 40 km/h	↗ 50 km/h	→ 70 km/h

Épaisseur de neige hors-piste

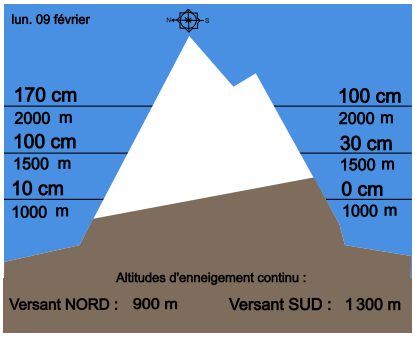

Précipitations à 1800 m

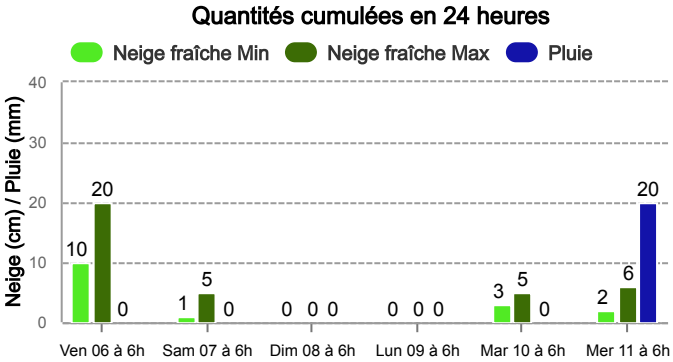

Tendance du mercredi 11 février

3 **Indice de risque marqué**

Mercredi, la neige s'abaisse à nouveau autour de 1500m. Nombreuses instabilités dans la neige fraîche. La pluie de la nuit continue de percoller dans le manteau neigeux, avec des avalanches de glissement encore possibles en journée.

Pour consulter la vigilance en cours, veuillez vous rendre sur le site https://vigilance.meteofrance.fr/fr

Météo-France - 73 avenue de Paris, 94165 Saint-Mandé cedex - Contact : contact@meteo.fr

Rédigé par Météo-France avec la contribution des observateurs du réseau nivo-météorologiques. Partenariat : ANMSM (Maires de Stations de Montagne), DSF (Domaines Skiables de France), ADSP (Directeurs de Pistes et de la Sécurité des Stations de Sports d'Hiver) et autres acteurs de la montagne.

Bulletin neige & avalanches par téléphone au 0 892 68 10 20 Service 0,35 € / min + prix appel

RÉPUBLIQUE FRANÇAISE
Liberté Égalité Fraternité

METEO FRANCE
À VOS CÔTÉS, DANS UN CLIMAT QUI CHANGE

Bulletin d'estimation du risque d'avalanche

(valable en dehors des pistes balisées et ouvertes)

MASSIF : Vercors

Rédigé le lundi 9 février 2026 à 16h

Conditions nivo-météo des 7 derniers jours

	mar. 03/02				mer. 04/02				jeu. 05/02				ven. 06/02				sam. 07/02				dim. 08/02				lun. 09/02			
	03h	09h	15h	21h	03h	09h	15h	21h	03h	09h	15h	21h	03h	09h	15h	21h	03h	09h	15h	21h	03h	09h	15h	21h	03h	09h	15h	21h
Météo																												
Vent (km/h)	125	90	75	70	45	50	50	30	25	35	50	45	55	25	25	15	15	15	15	10	25	20	25	20	10	25	25	35
à 2000m	↑	↑	↑	↑	↑	↑	↑	↑	↑	↑	↑	↑	↑	↘	↘	↘	↗	↓	↙	↙	↑	↑	↑	↖	↙	↑	↗	↑
Vent (km/h)	110	75	55	50	40	45	40	25	25	20	45	30	20	20	20	10	10	10	15	10	15	20	20	15	10	15	25	25
à 1500m	↑	↑	↑	↑	↑	↑	↑	↑	↑	↑	↑	↑	↗	→	→	↓	↙	↖	↓	↙	↖	↑	↑	↖	↙	↑	↑	↑

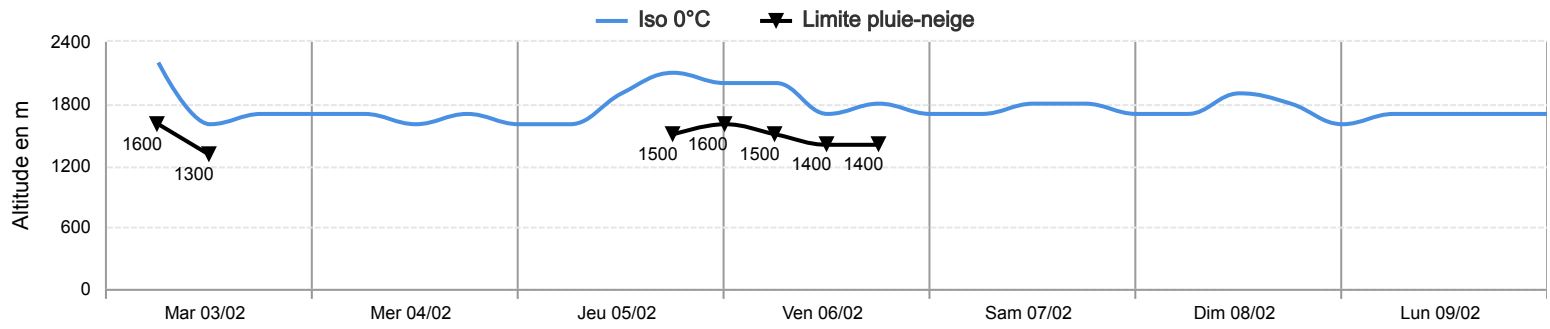

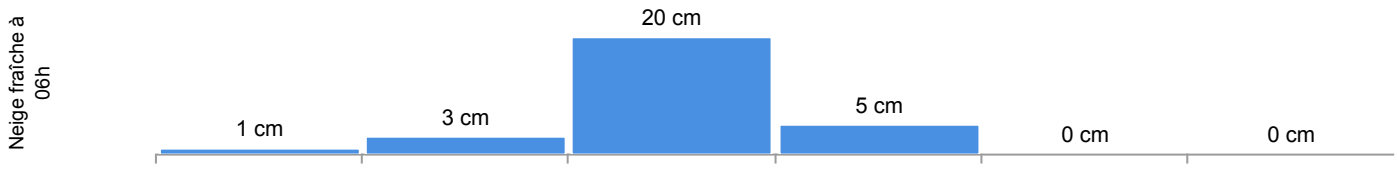

Risque d'avalanche	mar. 03/02	mer. 04/02	jeu. 05/02	ven. 06/02	sam. 07/02	dim. 08/02	lun. 09/02
	3	3	3	3	3	2	2

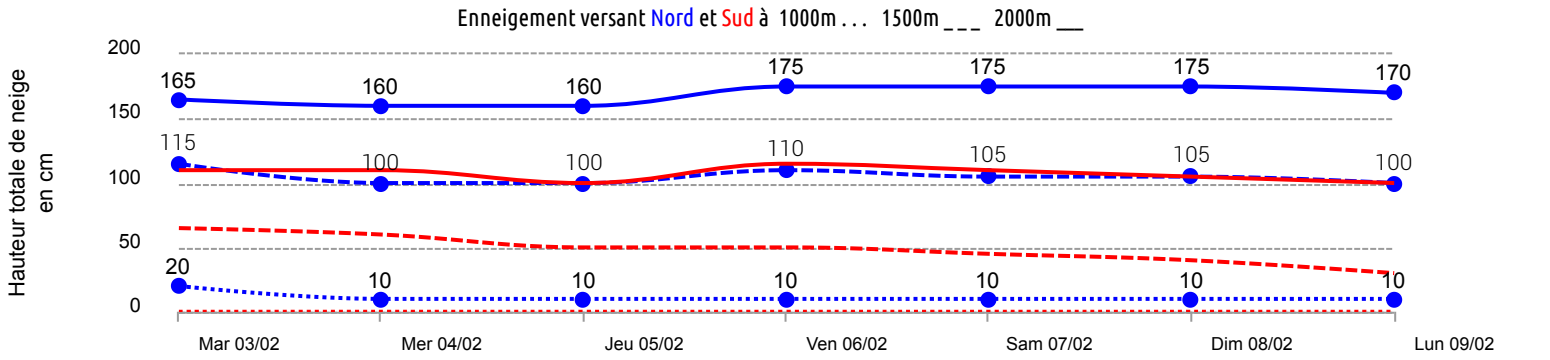

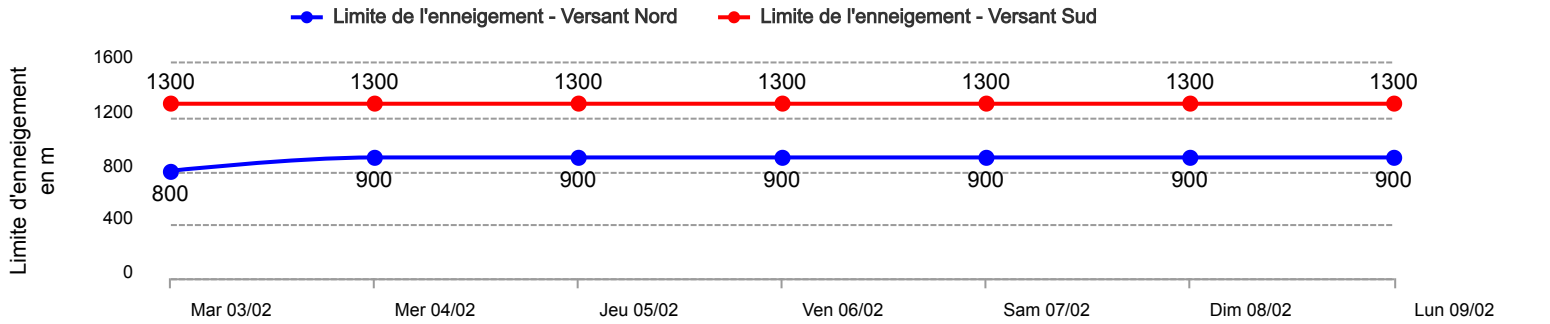

Pour consulter la vigilance en cours, veuillez vous rendre sur le site https://vigilance.meteofrance.fr/fr

Météo-France - 73 avenue de Paris, 94165 Saint-Mandé cedex - Contact : contact@meteo.fr

Rédigé par Météo-France avec la contribution des observateurs du réseau nivo-météorologiques. Partenariat : ANMSM (Maires de Stations de Montagne), DSF (Domaines Skiables de France), ADSP (Directeurs de Pistes et de la Sécurité des Stations de Sports d'Hiver) et autres acteurs de la montagne.

Bulletin neige & avalanches par téléphone au
0 892 68 10 20 Service 0,35 € / min + prix appel