Lawinengefahr

Aktualisiert am 9.2.2026, 17:00

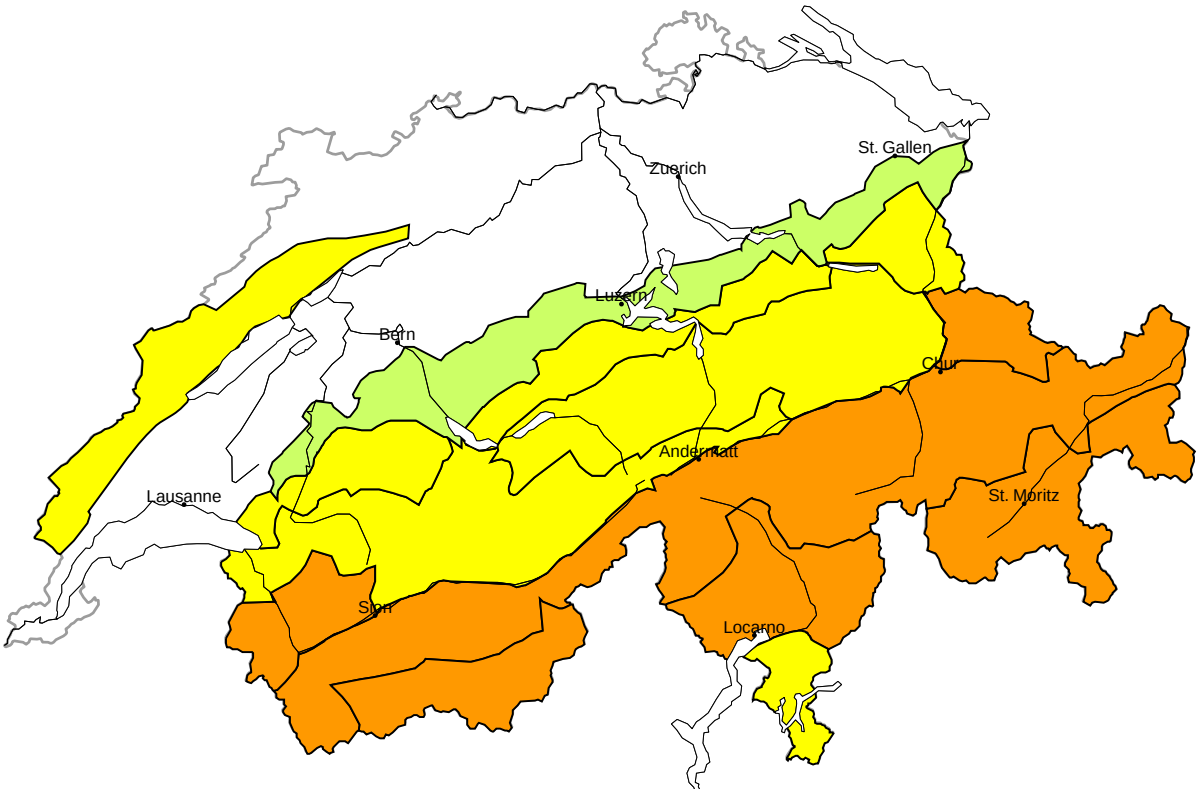

Gebiet A — Erheblich (3+)

Altschnee

Gefahrenstellen

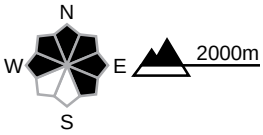

Gefahrenbeschrieb

Ausgeprägte Schwachschichten im Altschnee erfordern Vorsicht und Zurückhaltung. Lawinen können in tiefen Schichten anreissen und vereinzelt gross werden. Die Gefahrenstellen sind häufig. Fernauslösungen sind zu erwarten. Wummgeräusche und Risse beim Betreten der Schneedecke sowie frische Lawinen weisen auf die Gefahr hin.
Touren und Variantenabfahrten erfordern viel Erfahrung in der Beurteilung der Lawinengefahr und Zurückhaltung.

Gefahrenstufen 1 gering | 2 mässig | 3 erheblich | 4 gross | 5 sehr gross

Gebiet B — Erheblich (3=)

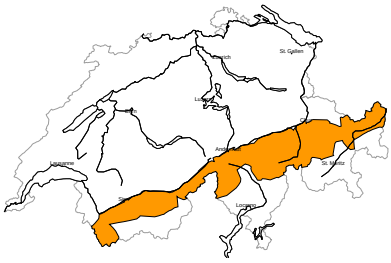

Altschnee

Gefahrenstellen

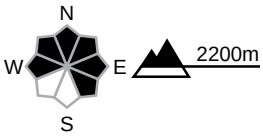

Gefahrenbeschrieb
Schwachschichten im Altschnee erfordern Vorsicht. Schon einzelne Schneesportler können Lawinen auslösen. Diese können in tiefen Schichten anreissen und vereinzelt gross werden. Fernauslösungen sind möglich. Wummgeräusche und Risse beim Betreten der Schneedecke sowie frische Lawinen können auf die Gefahr hinweisen.
Touren und Variantenabfahrten erfordern viel Erfahrung in der Beurteilung der Lawinengefahr.

Gebiet C — Erheblich (3=)

Neuschnee, Altschnee

Gefahrenstellen

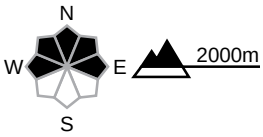

Gefahrenbeschrieb
Der Neuschnee liegt verbreitet auf einer schwachen Altschneedecke. Schon einzelne Schneesportler können Lawinen auslösen. Diese können in tiefen Schichten anreissen und vereinzelt gross werden. Fernauslösungen sind möglich. Wummgeräusche und Risse beim Betreten der Schneedecke sowie frische Lawinen können auf die Gefahr hinweisen.
Touren und Variantenabfahrten erfordern viel Erfahrung in der Beurteilung der Lawinengefahr.

Gebiet D — Erheblich (3-)

Triebschnee, Altschnee

Gefahrenstellen

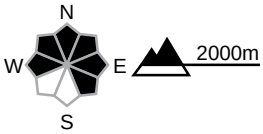

Gefahrenbeschrieb
Neu- und Triebschnee überlagern eine schwache Altschneedecke. Lawinen können schon von einzelnen Wintersportlern ausgelöst werden. Zudem können stellenweise Lawinen auch in tieferen Schichten ausgelöst werden. Diese Gefahrenstellen liegen vor allem an Übergängen von wenig zu viel Schnee sowie im selten befahrenen Tourengelände. Lawinen sind meist mittelgross.
Touren erfordern eine vorsichtige Routenwahl.

Gebiet E — Erheblich (3-)

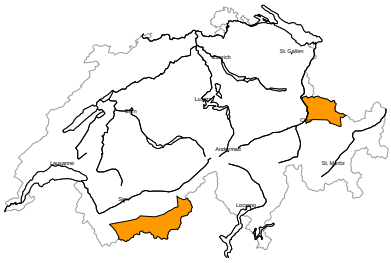

Altschnee

Gefahrenstellen

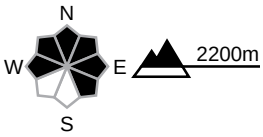

Gefahrenbeschrieb
Schwachschichten im Altschnee erfordern Vorsicht. Schon einzelne Schneesportler können stellenweise Lawinen auslösen. Diese können in tiefen Schichten anreissen und vereinzelt gross werden.
Fernauslösungen sind vereinzelt möglich.
Wummgeräusche und Risse beim Betreten der Schneedecke können auf die Gefahr hinweisen.
Touren und Variantenabfahrten erfordern viel Erfahrung in der Beurteilung der Lawinengefahr.

Gebiet F — Mässig (2+)

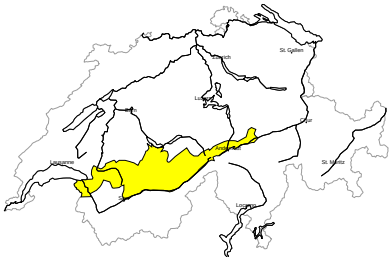

Triebschnee, Altschnee

Gefahrenstellen

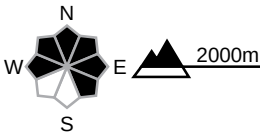

Gefahrenbeschrieb
Die frischen und älteren Triebschneeansammlungen sind teils störanfällig. Zudem können stellenweise Lawinen auch im Altschnee ausgelöst werden. Diese Gefahrenstellen liegen vor allem an Übergängen von wenig zu viel Schnee sowie im selten befahrenen Tourengelände. Lawinen können mittlere Grösse erreichen.
Touren erfordern eine vorsichtige Routenwahl.

Gebiet G — Mässig (2+)

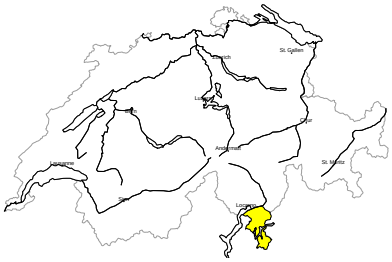

Neuschnee, Altschnee

Gefahrenstellen

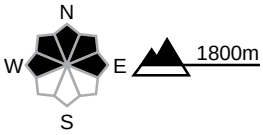

Gefahrenbeschrieb
Der Neuschnee überlagert eine schwache Altschneedecke. Stellenweise können Lawinen von einzelnen Wintersportlern ausgelöst werden. Lawinen können in tiefen Schichten anreissen und mittlere Grösse erreichen.
Touren und Variantenabfahrten erfordern eine defensive Routenwahl.

Gebiet H — Mässig (2=)

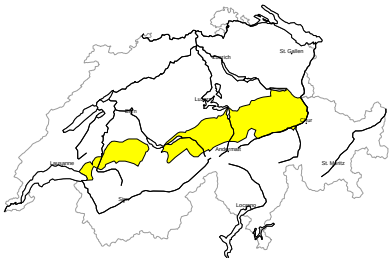

Triebschnee, Altschnee

Gefahrenstellen

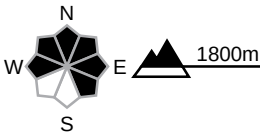

Gefahrenbeschrieb
Die frischen und schon etwas älteren Triebschneeansammlungen sind teils störanfällig. Die Gefahrenstellen liegen vor allem in Rinnen, Mulden und hinter Geländekanten. Zudem können vereinzelt Lawinen auch im Altschnee ausgelöst werden. Diese Gefahrenstellen liegen vor allem an Übergängen von wenig zu viel Schnee. Es sind kleine und vereinzelt mittlere Lawinen möglich.
Eine vorsichtige Routenwahl ist empfohlen.

Gebiet I — Mässig (2-)

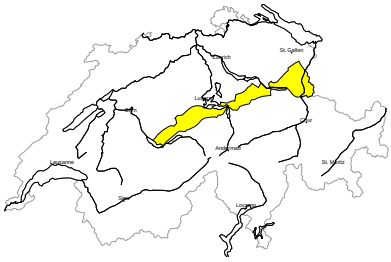

Kein ausgeprägtes Lawinenproblem

Gefahrenstellen

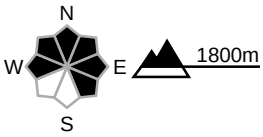

Gefahrenbeschrieb
Die oberflächennahen Schneeschichten können vor allem an Übergängen von wenig zu viel Schnee wie z.B. bei der Einfahrt in Rinnen und Mulden stellenweise ausgelöst werden. Lawinen sind meist eher klein. Eine vorsichtige Routenwahl ist empfohlen.

Gebiet J — Mässig (2-)

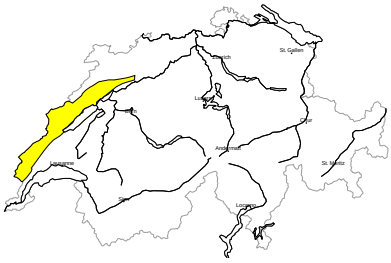

Triebschnee

Gefahrenstellen

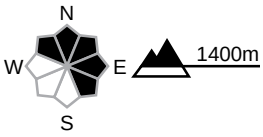

Gefahrenbeschrieb
Mit Neuschnee und teils starkem Südwestwind entstehen meist kleine Triebschneeansammlungen. Sie sollten im sehr steilen Gelände vorsichtig beurteilt werden. Nebst der Verschüttungsgefahr sollte vor allem die Mitreiss- und Absturzgefahr beachtet werden.

Gebiet K — Gering (1)

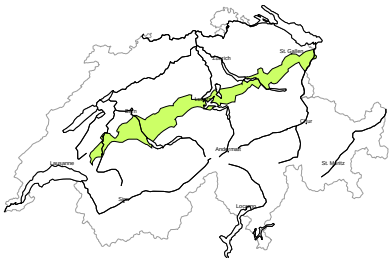

Kein ausgeprägtes Lawinenproblem

Gefahrenstellen

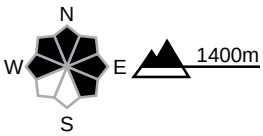

Gefahrenbeschrieb
Einzelne Gefahrenstellen liegen im extremen Steilgelände. Lawinen sind meist nur klein aber vereinzelt von einzelnen Wintersportlern auslösbar. Die Mitreiss- und Absturzgefahr sollte beachtet werden.

Gefahrenstufen 1 gering | 2 mässig | 3 erheblich | 4 gross | 5 sehr gross

Schneedecke und Wetter

Aktualisiert am 9.2.2026, 17:00

Schneedecke

Im südlichen Wallis, im Tessin und in Graubünden ist der Schneedeckenaufbau verbreitet ungünstig. Im mittleren und unteren Teil der Schneedecke befinden sich ausgeprägte, störanfällige Schwachschichten. Es werden aus diesen Gebieten weiterhin Wummgeräuschen und Lawinen gemeldet, welche durch Personen ausgelöst wurden und dies oft auch aus Distanz. Am Alpennordhang und im nördlichen Wallis ist der Schneedeckenaufbau etwas günstiger, aber es existieren auch in diesen Gebieten Schwachschichten tiefer in der Schneedecke. Diese können vor allem noch an schneearmen Stellen sowie an Übergängen von viel zu wenig Schnee ausgelöst werden.

Wetter Rückblick auf Montag

Im Süden war es stark bewölkt und es fiel wenig Schnee oberhalb von rund 1400 m. Sonst war es in den Bergen mit zunehmend dichteren Wolken aus Westen teilweise sonnig.

Neuschnee
am zentralen Alpensüdhang ein paar Zentimerter oberhalb von 1400 m

Temperatur
am Mittag auf 2000 m bei -3 °C

Wind
am nördlichen Alpenkamm zeitweise mässiger Südostwind, sonst mehrheitlich schwach

Wetter Prognose bis Dienstag

Im Norden ist es wechselnd bis stark bewölkt. Aufhellungen sind vor allem in den Vispertälern und in Graubünden möglich. Im Süden ist es stark bewölkt. Vor allem im Westen und Süden ist etwas Niederschlag zu erwarten. Die Schneefallgrenze liegt zwischen 1000 und 1500 m.

Neuschnee
- Jura, westlichstes Unterwallis, nördliches Wallis, zentraler Alpensüdhang: 5 bis 15 cm
- sonst wenige Zentimeter, in Mittelbünden und im Engadin trocken

Temperatur
am Mittag auf 2000 m zwischen -2 °C im Norden und -5 °C im Süden

Wind
zunehmend mässig, im Westen stark aus Südwest

Tendenz für Mittwoch und Donnerstag

Am Alpensüdhang ist es an beiden Tagen wechselnd bewölkt mit Aufhellungen und etwas Niederschlag. Im Norden ist es stark bewölkt und es fällt wiederholt Niederschlag. Der Niederschlagsschwerpunkt liegt im Westen und am Alpennordhang. Im westlichsten und nördlichen Unterwallis ist mehr als ein Meter Neuschnee zu erwarten, sonst am Alpennordhang westlich der Reuss und im Unterwallis 70 bis 100 cm, am Alpennordhang östlich der Reuss und im Oberwallis 40 bis 70 cm, sonst weniger. Die Schneefallgrenze sinkt im Norden von 1800 m gegen 1200 m, im Süden liegt sie bei 1300 m. Der Wind aus westlichen Richtungen bläst oft stark bis stürmisch. Die Lawinengefahr steigt am Mittwoch am westlichen Alpennordhang und im Wallis verbeitet rasch und markant auf die Stufe 4 (gross) an. Auch in den übrigen Gebieten steigt die Lawinengefahr an, am deutlichsten am übrigen Alpennordhang, im Gotthardgebiet und in Nordbünden.