Bollettino valanghe sino a martedì, 10. febbraio 2026

Pericolo valanghe

aggiornato al 9.2.2026, 17:00

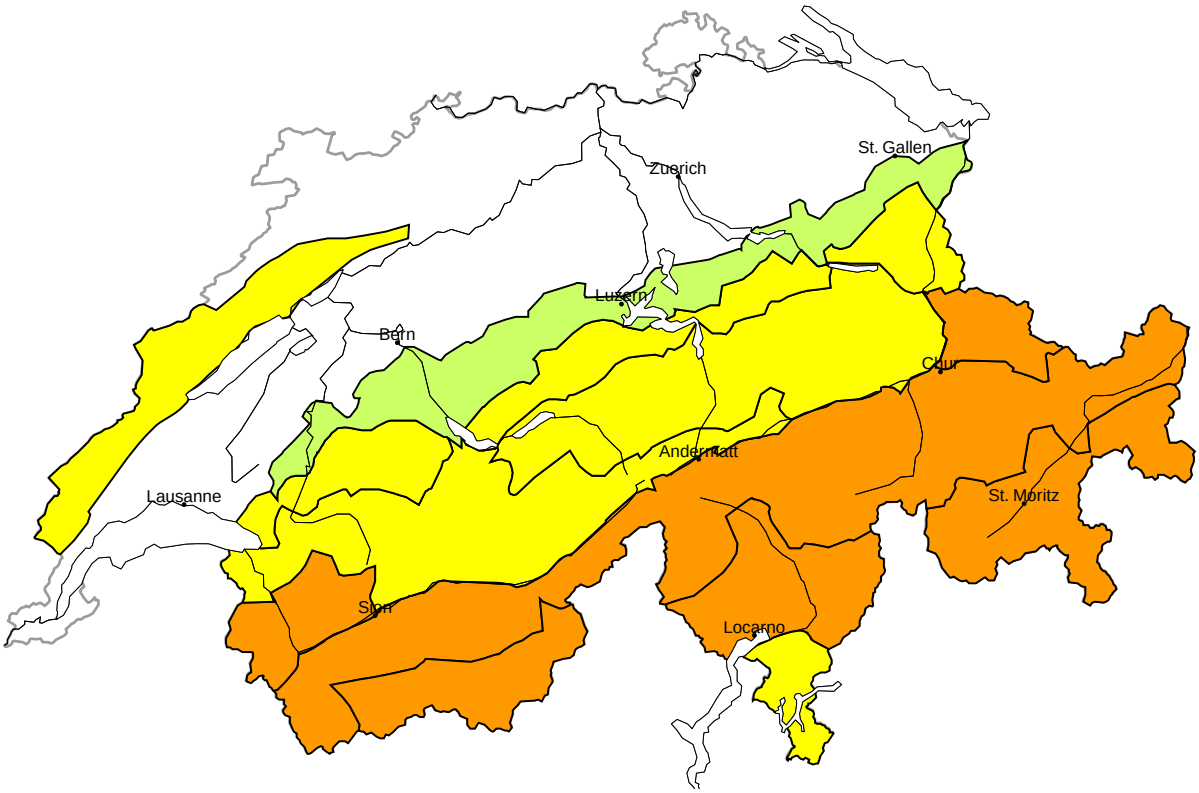

regione A — Marcato (3+)

Strati deboli persistenti

Punti pericolosi

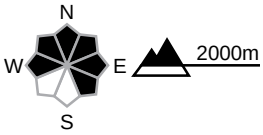

Descrizione del pericolo

Gli strati deboli molto pronunciati presenti nella neve vecchia richiedono attenzione e prudenza. Le valanghe possono distaccarsi negli strati più profondi e raggiungere grandi dimensioni a livello isolato. I punti pericolosi sono frequenti. Si prevedono distacchi a distanza. I rumori di "whum" e la formazione di fessure quando si calpesta la coltre di neve così come nuove valanghe sono segnali da ricondurre a questo pericolo. Le escursioni e le discese fuori pista richiedono molta esperienza nella valutazione del pericolo di valanghe e cautela.

Scala del pericolo 1 debole | 2 moderato | 3 marcato | 4 forte | 5 molto forte

regione B — Marcato (3=)

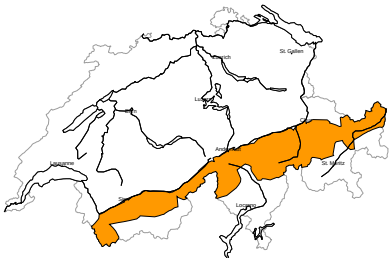

Strati deboli persistenti

Punti pericolosi

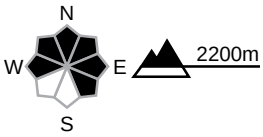

Descrizione del pericolo
Gli strati deboli presenti nella neve vecchia richiedono attenzione. Già un singolo appassionato di sport invernali può provocare il distacco di valanghe. Queste possono distaccarsi negli strati più profondi e raggiungere grandi dimensioni a livello isolato. Sono possibili distacchi a distanza. I rumori di "whum" e la formazione di fessure quando si calpesta la coltre di neve così come nuove valanghe sono possibili segnali di pericolo.
Le escursioni e le discese fuori pista richiedono molta esperienza nella valutazione del pericolo di valanghe.

regione C — Marcato (3=)

Neve fresca, Strati deboli persistenti

Punti pericolosi

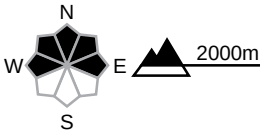

Descrizione del pericolo
In molti punti la neve fresca poggia su un debole manto di neve vecchia. Già un singolo appassionato di sport invernali può provocare il distacco di valanghe. Queste possono distaccarsi negli strati più profondi e raggiungere grandi dimensioni a livello isolato. Sono possibili distacchi a distanza. I rumori di "whum" e la formazione di fessure quando si calpesta la coltre di neve così come nuove valanghe sono possibili segnali di pericolo.
Le escursioni e le discese fuori pista richiedono molta esperienza nella valutazione del pericolo di valanghe.

regione D — Marcato (3-)

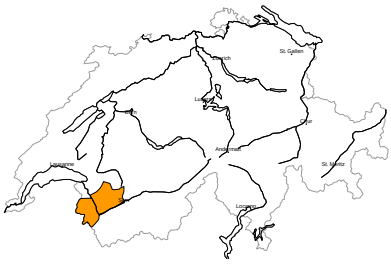

Lastroni da vento, Strati deboli persistenti

Punti pericolosi

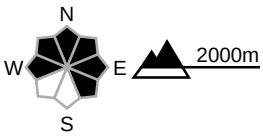

Descrizione del pericolo
La neve fresca e la neve ventata ricoprono un debole manto di neve vecchia. Le valanghe possono distaccarsi già in seguito al passaggio di un singolo appassionato di sport invernali. Inoltre, in alcuni punti le valanghe possono subire un distacco anche negli strati più profondi del manto nevoso. Questi punti pericolosi si trovano soprattutto nelle zone di passaggio da poca a molta neve come pure nelle zone escursionistiche poco frequentate. Le valanghe sono per lo più di dimensioni medie.
Le escursioni richiedono una prudente scelta dell'itinerario.

regione E — Marcato (3-)

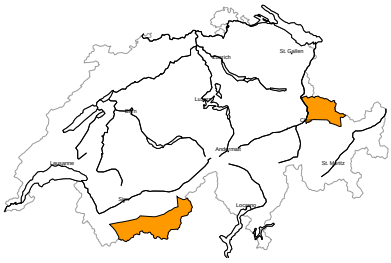

Strati deboli persistenti

Punti pericolosi

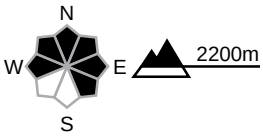

Descrizione del pericolo
Gli strati deboli presenti nella neve vecchia richiedono attenzione. Già un singolo appassionato di sport invernali può in alcuni punti provocare il distacco di valanghe. Queste possono distaccarsi negli strati più profondi e raggiungere grandi dimensioni a livello isolato. A livello isolato sono possibili distacchi a distanza. I rumori di "whum" e la formazione di fessure quando si calpesta la coltre di neve sono possibili segnali di pericolo.
Le escursioni e le discese fuori pista richiedono molta esperienza nella valutazione del pericolo di valanghe.

regione F — Moderato (2+)

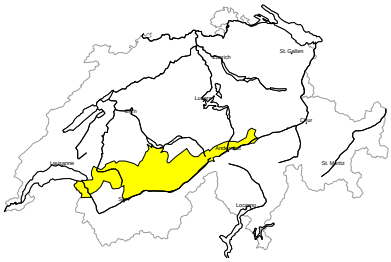

Lastroni da vento, Strati deboli persistenti

Punti pericolosi

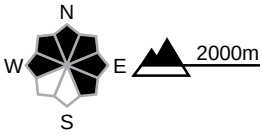

Descrizione del pericolo
I nuovi e i vecchi accumuli di neve ventata sono in parte instabili. Inoltre, in alcuni punti le valanghe possono subire un distacco anche nella neve vecchia. Questi punti pericolosi si trovano soprattutto nelle zone di passaggio da poca a molta neve come pure nelle zone escursionistiche poco frequentate. Le valanghe possono raggiungere dimensioni medie.
Le escursioni richiedono una prudente scelta dell'itinerario.

regione G — Moderato (2+)

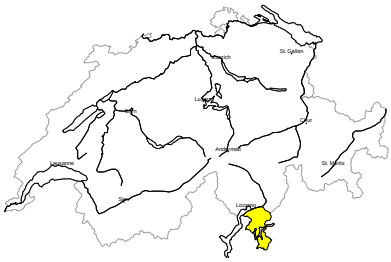

Neve fresca, Strati deboli persistenti

Punti pericolosi

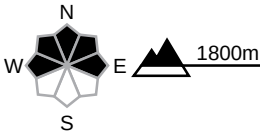

Descrizione del pericolo
La neve fresca ricopre un debole manto di neve vecchia. In alcuni punti, le valanghe possono subire un distacco in seguito al passaggio di un singolo appassionato di sport invernali. Le valanghe possono distaccarsi negli strati più profondi e raggiungere dimensioni medie.
Le escursioni e le discese fuori pista richiedono una prudente scelta dell'itinerario.

regione H — Moderato (2=)

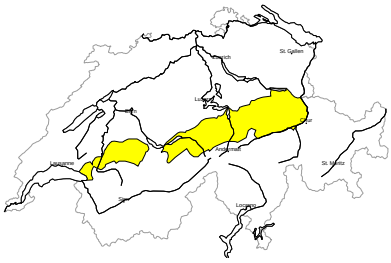

Lastroni da vento, Strati deboli persistenti

Punti pericolosi

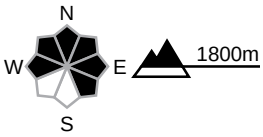

Descrizione del pericolo
I nuovi accumuli di neve ventata e quelli meno recenti sono in parte instabili. I punti pericolosi si trovano soprattutto nelle conche, nei canaloni e dietro ai cambi di pendenza. Inoltre, isolate valanghe possono subire un distacco anche nella neve vecchia. Questi punti pericolosi si trovano soprattutto nelle zone di passaggio da poca a molta neve. Sono possibili valanghe di piccole e, a livello isolato, di medie dimensioni.
Si raccomanda una prudente scelta dell'itinerario.

regione I — Moderato (2-)

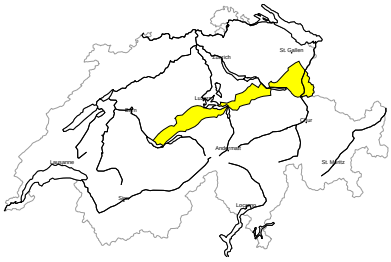

Nessun problema valanghivo evidente

Punti pericolosi

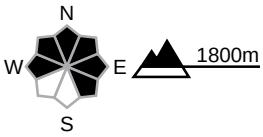

Descrizione del pericolo
Soprattutto nelle zone di passaggio da poca a molta neve come p.es. all'ingresso di conche e canaloni, gli strati superficiali di neve possono distaccarsi in alcuni punti. Le valanghe sono per lo più di dimensioni piuttosto piccole. Si raccomanda una prudente scelta dell'itinerario.

regione J — Moderato (2-)

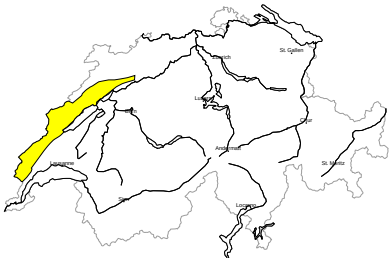

Lastroni da vento

Punti pericolosi

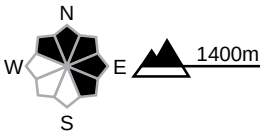

Descrizione del pericolo
Con neve fresca e vento in parte forte proveniente da sud ovest si formeranno accumuli di neve ventata per lo più di piccole dimensioni. Essi dovrebbero essere valutati con attenzione sui pendii molto ripidi. Oltre al pericolo di seppellimento, occorre fare attenzione soprattutto al pericolo di trascinamento e caduta.

regione K — Debole (1)

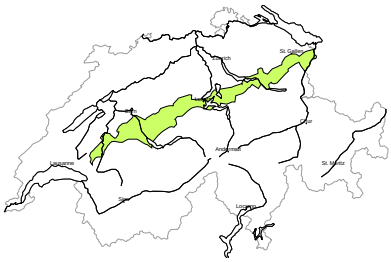

Nessun problema valanghivo evidente

Punti pericolosi

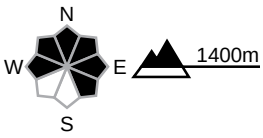

Descrizione del pericolo
Isolati punti pericolosi si trovano sui pendii estremamente ripidi. Le valanghe sono per lo più solo di piccole dimensioni ma a livello isolato distaccabili da un singolo appassionato di sport invernali. Attenzione al pericolo di trascinamento e di caduta.

Manto nevoso e meteo

aggiornato al 9.2.2026, 17:00

Manto nevoso

Nel sud del Vallese, in Ticino e nei Grigioni la struttura del manto nevoso è sfavorevole in molti punti. Nella parte centrale e basale del manto sono presenti pronunciati strati fragili instabili,. In queste regioni continuano a essere segnalati rumori di assestamento e valanghe provocate da persone, spesso anche a distanza. Sul versante nordalpino e nel nord del Vallese la struttura del manto nevoso è leggermente più favorevole. Tuttavia, anche in queste regioni la parte basale del manto nevoso ingloba strati fragili che possono subire un distacco soprattutto ancora nei punti scarsamente innevati, così come nelle zone di passaggio da poca a molta neve.

Retrospettiva meteo fino a lunedì

Nelle regioni meridionali il cielo è stato molto nuvoloso, con deboli nevicate al di sopra dei 1400 m circa. Altrove il tempo in montagna è stato parzialmente soleggiato, con nubi via via sempre più fitte a partire dalle regioni occidentali.

Neve fresca
Sul versante sudalpino centrale qualche centimetro al di sopra dei 1400 m circa

Temperatura
Sul mezzogiorno a 2000 m di -3 °C

Vento
Proveniente da sud est: sulla cresta settentrionale delle Alpi a tratti moderato, altrimenti prevalentemente debole

Previsioni meteo fino a martedì

Nelle regioni settentrionali il tempo sarà da variabile a molto nuvoloso. Potranno esserci schiarite soprattutto nelle valli della Vispa e nei Grigioni. Nelle regioni meridionali il cielo sarà molto nuvoloso. Soprattutto nelle regioni occidentali e meridionali si prevedono deboli precipitazioni. Il limite delle nevicate si collocherà tra i 1000 e i 1500 m.

Neve fresca
- Giura, Basso Vallese occidentale estremo, nord del Vallese, versante sudalpino centrale: dai 5 ai 15 cm
- Altrove: pochi centimetri; centro dei Grigioni ed Engadina: tempo asciutto

Temperatura
Sul mezzogiorno a 2000 m compresa tra -2 °C nelle regioni settentrionali e -5 °C in quelle meridionali

Vento
Via via moderato, nelle regioni occidentali forte, proveniente da sud ovest

Tendenza per mercoledì e giovedì

In entrambe le giornate, sul versante sudalpino il tempo sarà variamente nuvoloso con schiarite e deboli precipitazioni. Nelle regioni settentrionali il cielo sarà molto nuvoloso con ripetute precipitazioni. Il nucleo precipitativo interesserà le regioni occidentali e il versante nordalpino. Nella parte occidentale estrema e settentrionale del Basso Vallese si prevede oltre un metro di neve fresca, sul versante nordalpino ad ovest della Reuss e nel Basso Vallese dai 70 ai 100 cm, sul versante nordalpino a est della Reuss e nell'Alto Vallese dai 40 ai 70 cm, altrove meno. Nelle regioni settentrionali il limite delle nevicate scenderà dai 1800 ai 1200 m circa, mentre in quelle meridionali si collocherà intorno ai 1300 m. Il vento proveniente dai quadranti occidentali sarà spesso da forte a tempestoso. Mercoledì, in molti punti del versante nordalpino occidentale e del Vallese il pericolo di valanghe aumenterà in modo rapido e deciso fino al grado 4 (forte). Il pericolo di valanghe salirà anche nelle restanti regioni, in maniera particolarmente netta sul resto del versante nordalpino, nella regione del Gottardo e nel nord dei Grigioni.