GOBIERNO DE ESPAÑA
VICEPRESIDENCIA TERCERA DEL GOBIERNO
MINISTERIO PARA LA TRANSICIÓN ECOLÓGICA Y EL RETO DEMOGRÁFICO

Boletín de información nivológica y de peligro de aludes

Pirineo Navarro y Aragonés

aemet Agencia Estatal de Meteorología

martes, 10 de febrero de 2026

Pronóstico hasta las 24 horas del miércoles, día 11 de febrero

(Válido fuera de pistas de esquí balizadas y abiertas)

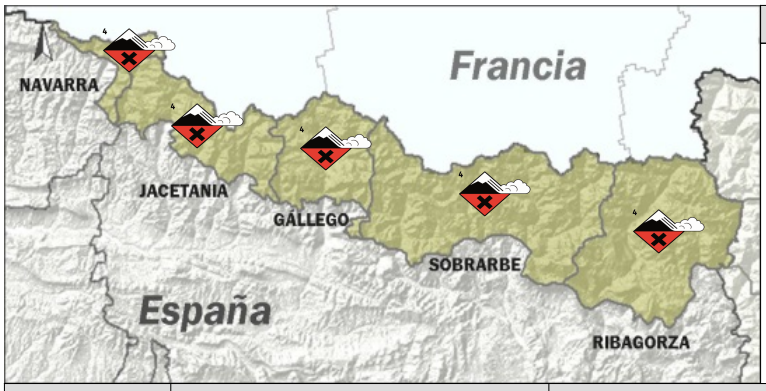

Problemas de aludes

Nieve húmeda

Placas de viento

Macizo	Peligro	Problemas de aludes, cota, orientación, tamaño	Innivación observada (m)
Navarra	4 Fuerte	Nieve húmeda: 3; N, S; 2400	2026-02-10 Cotas bajas
Jacetania	4 Fuerte	Nieve húmeda: 3; N, S; 2400 Placas de viento: 3; N, S; 2400	2026-02-10 Cotas bajas
Gállego	4 Fuerte	Nieve húmeda: 3; N, S; 2400 Placas de viento: 3; N, S; 2400	2026-02-10 Cotas bajas
Sobrarbe	4 Fuerte	Nieve húmeda: 3; N, S; 2400 Placas de viento: 3; N, S; 2400	2026-02-10 Cotas bajas

AEMET. Se autoriza la reproducción de su contenido citando la fuente.

Boletín de información nivológica y de peligro de aludes

Pirineo Navarro y Aragonés

Ribagorza	 **Fuerte**	**Nieve húmeda**				
		Placas de viento				

2026-02-10

Cotas bajas

Estado del manto y observaciones recientes

Importantes precipitaciones durante las últimas 24 horas, en forma líquida hasta altitudes considerables, que han ocasionado un aumento de espesores en cotas altas de entre 5 y 30 cm o incluso más, y una mengua generalizada en medianías y zonas bajas. Pese a ello, la nieve sigue siendo continua desde fondos de valle en numerosas áreas, con espesores que se van incrementando conforme ascendemos, de manera que en torno a 2.100 metros se superan fácilmente los 200 a 220 cm, aún más en ventisqueros, hoyas y otras zonas propensas a la acumulación.

El perfil del manto consta de una capa superficial de nieve reciente, seca o húmeda, de espesor variable y otras múltiples en el interior donde se van intercalando grano fino o redondo con costras de rehielo. En cotas medias y bajas el agua ha ido percolando por el manto, humedeciéndolo notablemente, sobre todo en sus estratos más externos, que ya presentan rugosidades y estrías asociadas a la lluvia. Por encima de 2.400 ó 2.500 metros la nieve se mantiene más suelta, venteada y menos evolucionada, en particular en zonas de umbría, donde todavía pueden persistir estratos débiles a diferentes profundidades.

Se han registrado numerosos aludes de nieve húmeda en diferentes puntos de observación, de tamaño mediano en su mayor parte, aunque en algún caso han llegado a ser grandes.

Evolución del manto y peligro de aludes para el miércoles, día 11

Situación de nieve húmeda y deslizamientos basales, así como de placas de viento en la alta montaña.

Durante las próximas 24 horas volverán a producirse precipitaciones con mayor o menor continuidad, con una cota de nieve variable pero que se situará en altitudes considerables la mayor parte del periodo, por lo que la lluvia seguirá percolando por el manto, humedeciéndolo e inestabilizándolo. Así, serán frecuentes las purgas de nieve húmeda en laderas con suficiente inclinación y sin orientación preferente, que podrán ser de tamaño mediano o incluso grande, suficiente como para enterrar a un grupo de personas, sin descartarse la ocurrencia de deslizamientos basales en algunos enclaves, como por ejemplo pueden ser las canales, capaces de adquirir dimensión muy grande y alcanzar fondos de valle.

Por encima de unos 2.400 ó 2.500 metros las precipitaciones serán íntegramente en forma sólida y estarán acompañadas de fuertes vientos de componente oeste, volviendo a formarse placas en diferentes áreas de la alta montaña, mayormente en vertientes este, que vendrán a sumarse a las ya existentes, en algunos casos difíciles de localizar. Todas estas estructuras

AEMET. Se autoriza la reproducción de su contenido citando la fuente.

permanecerán frágiles y podrán fracturarse ante una sobrecargas débiles, como es el paso de un esquiador, dando lugar a aludes que pueden alcanzar dimensión grande. Además, en las umbrías de la alta montaña pueden existir aún capas débiles en el interior del manto que en zonas de poco espesor podrían resultar problemáticas, por lo que se recomienda extremar las precauciones.

Predicción meteorológica para el miércoles, día 11

Predominio de cielos muy nubosos o cubiertos, con apertura ocasional de claros. Se esperan precipitaciones débiles o moderadas, en ocasiones en forma de chubascos acompañados de alguna tormenta, que serán más frecuentes durante la segunda mitad del día y en la Jacetania y Alto Gállego. Cota de nieve: fluctuante, en torno a 1.800 ó 2.000 metros a primeras y últimas horas y subiendo a unos 2.400 ó 2.500 en horas centrales. Temperaturas sin cambios o en ligero descenso. Heladas débiles en la alta montaña, localmente moderadas. Vientos fuertes de componente oeste, con rachas muy fuertes en cotas altas y zonas expuestas, donde no se descarta que puedan llegar a ser huracanadas.

Datos en la atmósfera libre:

Altitud de la isoterma de 0 ºC: 2.500 m
Altitud de la isoterma de -10 ºC: 4.200 m

Viento a 1500 m: W 50 km/h
Viento a 3000 m: W 70 km/h

Evolución para el jueves día 12

Con el descenso de las temperaturas tenderá a disminuir el nivel de peligro por nieve húmeda.

(Información elaborada a partir de los datos recibidos de los refugios de Linza, Lizara, Panticosa, Bachimaña, Pineta, Estós, Angel Orús y La Renclusa, de las estaciones de esquí de Candanchú, Formigal y Panticosa (lagos), de la estación de esquí de fondo de Llanos del Hospital y de Ordesa Pradera)

Escala europea de peligro de aludes

Débil | Limitado | Notable | Fuerte | Muy Fuerte

Problemas de aludes

Nieve reciente | Placas de viento | Capas débiles persistentes | Nieve húmeda | Deslizamientos basales | Sin problema evidente

Nota1: Se recuerda que, siempre que haya nieve, la ausencia total de peligro no existe. Hay que tener presente que en circunstancias desfavorables, con aludes de tamaño 1 (alud pequeño o colada) y tamaño 2 (alud mediano), se pueden sufrir severos daños personales.

Nota2: Los BPA se elaboran en base a información meteorológica así como al estado del manto nivoso a través de sondeos puntuales. Se advierte a los usuarios de la variabilidad de esta información al extrapolarla a zonas extensas de montaña. Por ello, AEMET no se hace responsable de su uso para la toma de decisiones que conciernen a la seguridad personal, ni de los riesgos físicos o materiales de ellas derivadas.

AEMET. Se autoriza la reproducción de su contenido citando la fuente.