Mardi 10.02.2026

Update du 10 02 2026, 08:00

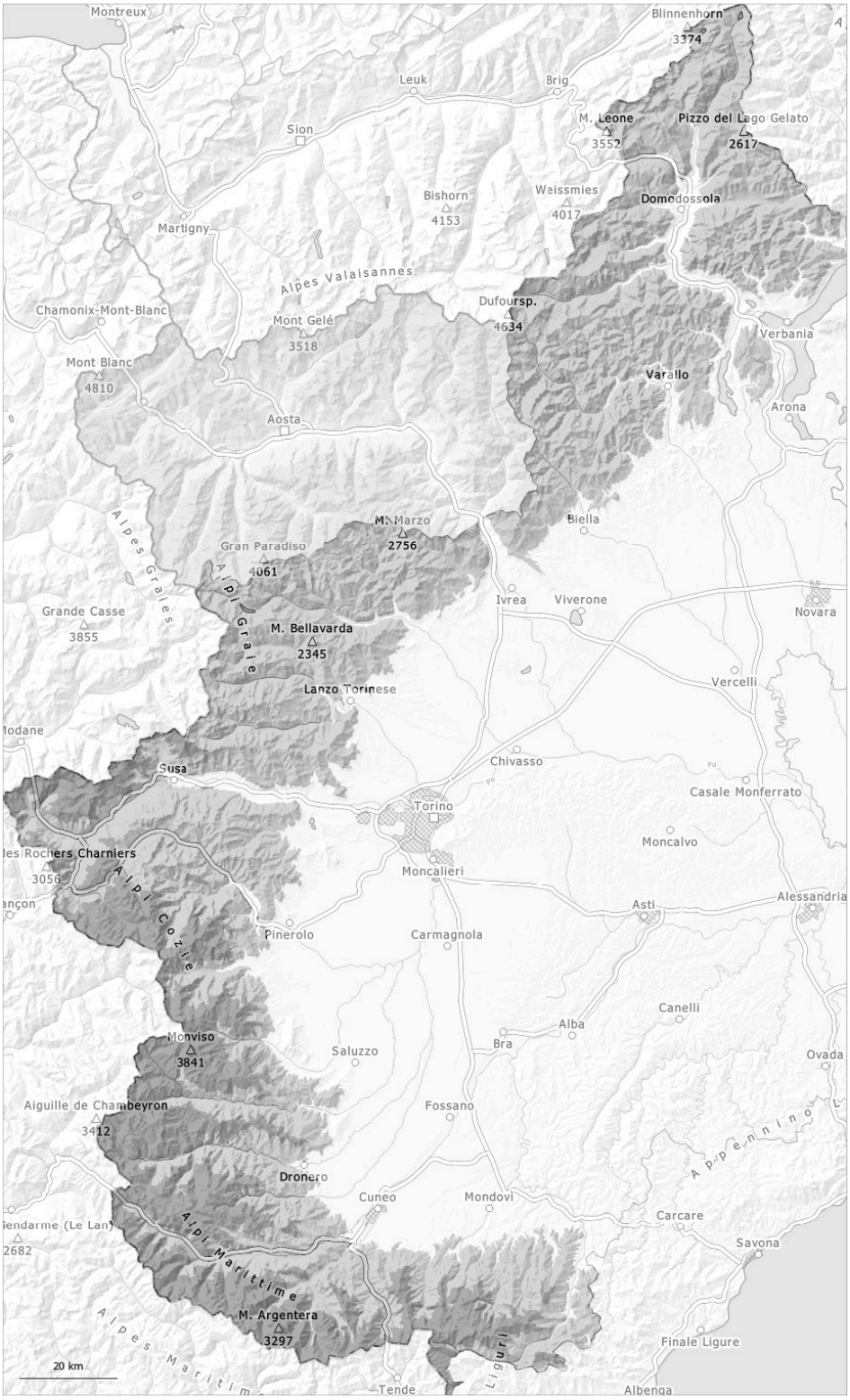

1	2	3	4	5
faible	limité	marqué	fort	très fort

Degré de danger 3 - Marqué

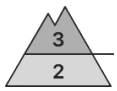

Limite de la forêt

Tendance: danger d'avalanche constant
leMercredi 11 02 2026

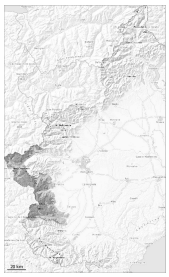

Limite de la forêt

Neige soufflée
(Neige ventée)

Limite de la forêt

Neige soufflée
(Neige ventée)

À moyenne et haute altitude des avalanches de plaque de neige sèche sont toujours possibles. Le danger d'avalanches ne diminue pas encore.

Des accumulations de neige soufflée en général peu épaisses se sont formées avec la neige fraîche et le vent modéré. Les accumulations de neige soufflée peuvent être déjà déclenchées par un seul amateur de sports d'hiver. Ceci surtout sur les pentes raides comme dans les combes, couloirs et derrière les ruptures de terrain aussi à moyenne altitude.
Des avalanches peuvent être déclenchées surtout sur les pentes raides à l'ombre dans les couches plus profondes du manteau neigeux.
Les endroits dangereux sont à peine identifiables par mauvaise visibilité.

Un choix réfléchi des itinéraires est nécessaire. Des distances de délestage et des descentes un par un sont recommandées.

Manteau neigeux

Modèles de danger md.6: froid, neige légère et vent

Depuis dimanche il est tombé au-dessus d'environ 1200 m de 5 à 10 cm de neige. Des accumulations de neige soufflée supplémentaires se sont formées avec la neige fraîche et le vent de secteur ouest partiellement modéré surtout au-dessus de la limite de la forêt. La neige fraîche et la neige soufflée reposent sur des couches meubles sur les pentes protégées du vent à l'ombre.
La partie supérieure du manteau neigeux présente un arrondissement des grains de neige, avec une croûte de regel non porteuse à la surface, surtout sur les pentes raides ensoleillées.

Aux altitudes moyennes et élevées: Dans la partie inférieure du manteau neigeux des couches fragiles isolées susceptibles d'être déclenchées sont présentes, surtout sur les pentes très raides à l'ombre.

Degré de danger 3 - Marqué

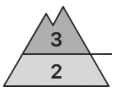

Limite de la forêt

Tendance: danger d'avalanche constant
leMercredi 11 02 2026

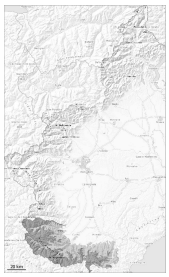

Neige soufflée
(Neige ventée)

Limite de la forêt

Avalanches
mouillées
(Neige
humide)

1500m

Avec la neige fraîche et le vent danger d'avalanches sèches en général marqué. Ceci surtout au-dessus de la limite de la forêt.

Des accumulations de neige soufflée supplémentaires se sont formées avec la neige fraîche et le vent modéré. La neige fraîche et en particulier les accumulations de neige soufflée parfois grandes peuvent être déclenchées par un seul amateur de sports d'hiver à toutes les expositions et en général au-dessus de la limite de la forêt. Ceci surtout sur les pentes raides et à proximité des crêtes, dans les combes et couloirs. Les avalanches peuvent se déclencher dans les différentes couches de neige fraîche et soufflée et atteindre une grande taille.
Les endroits dangereux sont à peine identifiables par mauvaise visibilité.
En dessous d'environ 1500 m des avalanches humides et mouillées de petite et moyenne taille sont possibles.

Un choix prudent d'itinéraire et des distances de délestage sont recommandés.

Manteau neigeux

Modèles de danger md.6: froid, neige légère et vent

Dans les derniers deux jours il est tombé au-dessus d'environ 1200 m de 10 à 15 cm de neige, localement plus. Avec les chutes de neige et le vent d'ouest modéré, de nouvelles accumulations de neige soufflée se sont formées. La neige fraîche et soufflée reposent en général sur des couches molles.
La partie supérieure du manteau neigeux présente un arrondissement des grains de neige, avec une croûte de regel non porteuse à la surface, surtout sur les pentes ensoleillées.
À basse altitude le manteau neigeux sera humide.

Au-dessus d'environ 1500 m il y a beaucoup de neige.

Degré de danger 2 - Limité

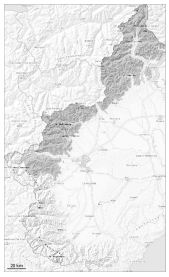

2

Tendance: danger d'avalanche constant
leMercredi 11 02 2026

Neige soufflée
(Neige ventée)

Quelques endroits dangereux se situent surtout en terrain raide à moyenne et haute altitude.

Les accumulations récentes et déjà plus anciennes de neige soufflée constituent le danger principal. Les endroits dangereux se situent surtout à proximité des crêtes et des cols ainsi que sur les pentes raides peu fréquentées. En altitude ces endroits dangereux sont plus fréquents et plus étendus.
Les avalanches sont de taille moyenne et en général déclenchables seulement avec une surcharge importante.
En outre, des avalanches peuvent de manière très isolée se déclencher dans la neige ancienne et atteindre une grande taille.

Les endroits dangereux sont à peine identifiables par mauvaise visibilité. Un choix prudent d'itinéraire et des distances de délestage sont recommandés.

Manteau neigeux

Modèles de danger md.6: froid, neige légère et vent

Les endroits dangereux se situent spécialement sur les versants où s'est accumulée la neige soufflée. Les accumulations de neige soufflée reposent sur des couches meubles surtout sur les pentes à l'ombre.
La partie supérieure du manteau neigeux présente un arrondissement des grains de neige, avec une croûte de regel non porteuse à la surface, notamment sur les pentes raides à l'ombre.
Dans la partie inférieure du manteau neigeux des couches fragiles ayant subi une métamorphose constructive à grains anguleux sont présentes sur les pentes à l'ombre, notamment à moyenne et haute altitude.