ICGC Institut Cartogràfic i Geològic de Catalunya

Servei Meteorològic de Catalunya meteo.cat

Boletín de peligro de aludes para el Pirineo de Catalunya
Del 10/02/2026 al 11/02/2026

(Válido fuera pistas de esquí y zonas no controladas)

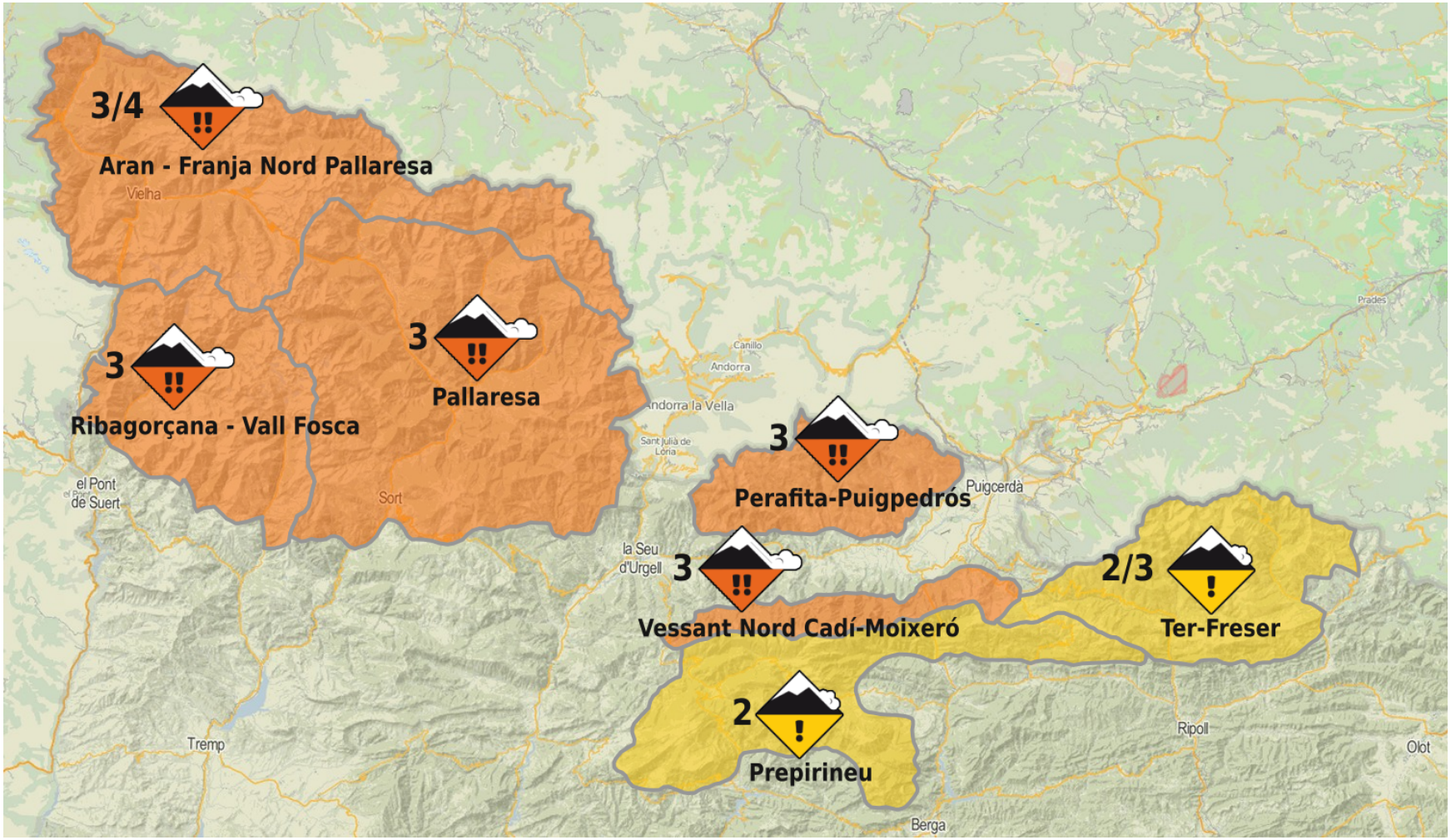

5 MUY FUERTE	4 FUERTE	3 NOTABLE	2 LIMITADO	1 DÉBIL

ICGC Institut Cartogràfic i Geològic de Catalunya

meteo.cat Servei Meteorològic de Catalunya

Boletín de peligro de aludes Aran - Franja Nord Pallaresa Del 10/02/2026 al 11/02/2026

(Válido fuera pistas de esquí y zonas no controladas)

MARCADO (3), en la Franja Norte Pallaresa. FUERTE (4), en Aran, hasta la noche del martes.

Situación primaria

Deslizamientos basales **Distribución** **Tamaño** **Origen** **Tendencia**

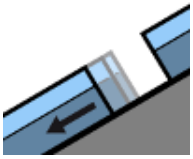

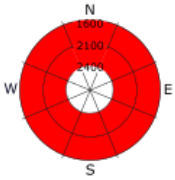

Situación secundaria

Nieve húmeda **Distribución** **Tamaño** **Origen** **Tendencia**

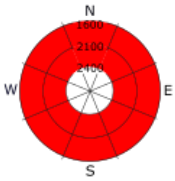

Estado del manto nivoso

Debido a la lluvia en cotas cercanas a los 2.500 m, con el humedecimiento del manto, aumentará el grado de peligro por problemas con la nieve húmeda y los deslizamientos. Se esperan aludes naturales de gran tamaño (con capacidad de colgar un grupo de personas), en todas las orientaciones y, con mayor probabilidad, en cotas bajas y medias. Localmente, podrá caer algún alud de tamaño muy grande (que pueda llegar a fondo de valle). Se recomienda no realizar actividades cerca de terreno avalanchoso. Los aludes caerán, sobre todo, en pendientes fuertemente inclinadas como canales o cubetas. Con el viento del oeste y del noroeste previsto se formarán nuevas placas de viento. Estas placas las encontraremos en cota muy alta, bajo collados, en cualquier orientación, preferentemente, en N y E. Pueden ser de tamaño medio, con capacidad de enterrar a una persona, o incluso, localmente, a un grupo de personas. El grado de peligro 4 (Fuerte) queda restringido en el Aran, hasta la noche del martes.

Distribución del manto nivoso

Hay nieve en el suelo a 1.000 m. El manto es esquiable por encima de unos 1.500 m. Los espesores a unos 2.200 m rondan los 110-140 cm en el norte de Arán y 140-190 cm en la Franja Norte Pallaresa y en el sur de Aran, y son superiores a los normales por estas fechas.

Tendencia para las próximas 48-72h

Con el descenso térmico disminuye el problema de nieve húmeda. El fuerte viento del NW mantendrá reactivas las placas. Peligro ESTACIONARIO.

El próximo boletín será emitido el día 2026-02-11

5 MUY FUERTE	4 FUERTE	3 NOTABLE	2 LIMITADO	1 DÉBIL

EAWS EUROPEAN AVALANCHE WARNING SERVICES

ICGC Institut Cartogràfic i Geològic de Catalunya

Servei Meteorològic de Catalunya meteo.cat

Boletín de peligro de aludes Ribagorçana - Vall Fosca Del 10/02/2026 al 11/02/2026

(Válido fuera pistas de esquí y zonas no controladas)

NOTABLE (3).

Situación primaria

Nieve húmeda

Distribución

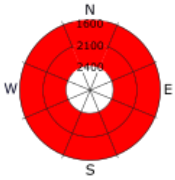

Tamaño

Origen

Tendencia

Situación secundaria

Nieve venteada

Distribución

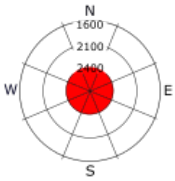

Tamaño

Origen

Tendencia

Estado del manto nivoso

El último frente ha dejado lluvia hasta 2.500 m. El manto se ha humedecido y el problema predominante será el de la nieve húmeda. Los aludes caerán de forma natural y llegarán hasta tamaño medio (con capacidad de enterrar a un montañero). Se darán, sobre todo, en pendientes fuertemente inclinadas. Localmente, no se descarta algún alud de tamaño grande (con capacidad de enterrar a un grupo de personas). Con el fuerte viento del Oeste y del Noroeste previsto se habrán formado nuevas placas de viento, más probables en cota alta, por encima de los 2.400 m, en todas orientaciones, pero en especial en vertiente E y SE. Las más sensibles y frágiles estarán por encima de los 2.500 m, bajo collados y cordales, y podrán caer fácilmente al paso de un montañero y alcanzar tamaño suficiente para enterrar a una persona. Además son posibles purgas de nieve reciente (húmedecida), en cota alta, de tamaño pequeño y medio, que pueden caer de manera natural o ser desencadenadas al paso de un montañero.

Distribución del manto nivoso

Hay nieve en el suelo a 1.500 m. El manto es esquiable por encima de unos 1500-1600 m. Los grosores alcanzan los 130-160 cm. Estos valores son muy superiores a los normales en la época.

Tendencia para las próximas 48-72h

Con el descenso térmico disminuye el problema de nieve húmeda. El fuerte viento del NW mantendrá reactivas las placas. Peligro ESTACIONARIO.

El próximo boletín será emitido el día 2026-02-11

5 MUY FUERTE	4 FUERTE	3 NOTABLE	2 LIMITADO	1 DÉBIL

EAWS EUROPEAN AVALANCHE WARNING SERVICES

ICGC Institut Cartogràfic i Geològic de Catalunya

Servei Meteorològic de Catalunya meteo.cat

Boletín de peligro de aludes Pallaresa
Del 10/02/2026 al 11/02/2026

(Válido fuera pistas de esquí y zonas no controladas)

NOTABLE (3).

Situación primaria

Nieve húmeda

Distribución

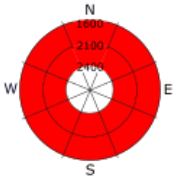

Tamaño

Origen

Tendencia

Situación secundaria

Nieve venteada

Distribución

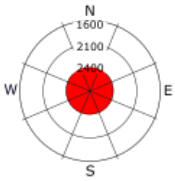

Tamaño

Origen

Tendencia

Estado del manto nivoso

El último frente ha dejado lluvia hasta 2.500 m. El manto se ha humedecido y el problema predominante será el de la nieve húmeda. Los aludes caerán de forma natural y llegarán hasta tamaño medio (con capacidad de enterrar a un montañero). Se darán, sobre todo, en pendientes fuertemente inclinadas. Localmente, no se descarta algún alud de tamaño grande (con capacidad de enterrar a un grupo de personas). Con el fuerte viento del Oeste y del Noroeste previsto se habrán formado nuevas placas de viento, más probables en cota alta, por encima de los 2.400 m, en todas orientaciones, pero en especial en vertiente E y SE. Las más sensibles y frágiles estarán por encima de los 2.500 m, bajo collados y cordales, y podrán caer fácilmente al paso de un montañero y alcanzar tamaño suficiente para enterrar a una persona. Además son posibles purgas de nieve reciente (húmedecida), en cota alta, de tamaño pequeño y medio, que pueden caer de manera natural o ser desencadenadas al paso de un montañero.

Distribución del manto nivoso

Hay nieve desde los 1600 m. Los espesores en cotas altas y medias superan los 140-150 cm. Estos valores son superiores a los normales para la época.

Tendencia para las próximas 48-72h

Con el descenso térmico disminuye el problema de nieve húmeda. El fuerte viento del NW mantendrá reactivas las placas. Peligro ESTACIONARIO.

El próximo boletín será emitido el día 2026-02-11

5 MUY FUERTE	4 FUERTE	3 NOTABLE	2 LIMITADO	1 DÉBIL

EAWS EUROPEAN AVALANCHE WARNING SERVICES

ICGC Institut Cartogràfic i Geològic de Catalunya

meteo.cat Servei Meteorològic de Catalunya

Boletín de peligro de aludes Perafita-Puigpedrós Del 10/02/2026 al 11/02/2026

(Válido fuera pistas de esquí y zonas no controladas)

NOTABLE (3).

Situación primaria

Nieve húmeda

Distribución

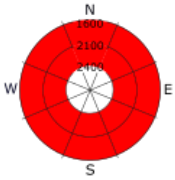

Tamaño

Origen

Tendencia

Situación secundaria

Nieve venteada

Distribución

Tamaño

Origen

Tendencia

Estado del manto nivoso

El manto se ha humedecido por debajo de los 2.500 m debido a la última nevada, con cota de nieve alta. El problema predominante seguirá siendo el de la nieve húmeda. Los aludes caerán de forma natural y llegarán hasta tamaño medio (con capacidad de enterrar a un montañero). Se darán, sobre todo, en pendientes fuertemente inclinadas como canales o corredores. Localmente, no se descarta algún alud de tamaño grande (con capacidad de enterrar a un grupo de personas). Con el fuerte viento del Oeste y del Noroeste previsto se habrán formado nuevas placas de viento, más probables en cota alta, por encima de los 2.400-2.500 m, en todas orientaciones, pero en especial en vertiente E y SE. Las más sensibles y frágiles estarán por encima de los 2.500 m, bajo collados y cordales, y podrán caer fácilmente al paso de un montañero y alcanzar tamaño suficiente para enterrar a una persona.

Distribución del manto nivoso

Hay nieve en el suelo por encima de 1.400-1500 m. Sin embargo, el manto es esquiable por encima de 1.500-1.600 m. Los grosores alcanzan los 130-150 cm a 2.200 m. Son grosores muy por encima de los habituales por la época.

Tendencia para las próximas 48-72h

Con el descenso térmico disminuye el problema de nieve húmeda. El fuerte viento del NW mantendrá reactivas las placas. Peligro ESTACIONARIO.

El próximo boletín será emitido el día 2026-02-11

5 MUY FUERTE	4 FUERTE	3 NOTABLE	2 LIMITADO	1 DÉBIL

EAWS EUROPEAN AVALANCHE WARNING SERVICES

ICGC Institut Cartogràfic i Geològic de Catalunya

Servei Meteorològic de Catalunya meteo.cat

Boletín de peligro de aludes
Vessant Nord Cadí-Moixeró
Del 10/02/2026 al 11/02/2026

(Válido fuera pistas de esquí y zonas no controladas)

NOTABLE (3).

Situación primaria

Nieve húmeda

Distribución

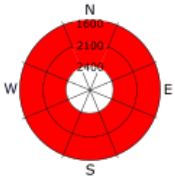

Tamaño

Origen

Tendencia

Situación secundaria

Nieve venteada

Distribución

Tamaño

Origen

Tendencia

Estado del manto nivoso

El manto se ha humedecido con el paso del último frente cálido. El problema predominante será el de la nieve húmeda. Los aludes caerán de forma natural con el humedecimiento previsto. Llegarán hasta tamaño medio (con capacidad de enterrar a una persona) y se darán, sobre todo, en pendientes fuertemente inclinadas, como en las Canals del Cadí. En las cotas más altas podremos encontrar placas de viento que pueden caer al paso de un montañero y alcanzar tamaño medio, suficiente para enterrar a una persona. Por lo general, las encontraremos en laderas Este, Norte y en zonas resguardadas del viento del Oeste. De forma local, alguna placa desatada podría implicar más manto y generar un alud de gran tamaño (con capacidad de enterrar a un grupo de personas).

Distribución del manto nivoso

Hay nieve desde 1.300 m en el norte y desde 1.400 a 1500 m en sur, esquiable por encima de unos 1.500 m. Los grosores están alrededor de 150-170 cm a 2.200 m. Estos valores son muy excedentarios para la época del año.

Tendencia para las próximas 48-72h

Con el descenso térmico disminuye el problema de nieve húmeda. El fuerte viento del NW mantendrá reactivas las placas. Peligro ESTACIONARIO.

El próximo boletín será emitido el día 2026-02-11

5 MUY FUERTE	4 FUERTE	3 NOTABLE	2 LIMITADO	1 DÉBIL

EAWS EUROPEAN AVALANCHE WARNING SERVICES

ICGC Institut Cartogràfic i Geològic de Catalunya

meteo.cat Servei Meteorològic de Catalunya

Boletín de peligro de aludes Prepirineu
Del 10/02/2026 al 11/02/2026

(Válido fuera pistas de esquí y zonas no controladas)

LIMITADO (2), por la mañana. NOTABLE (3), a partir de mediodía.

Situación primaria

Nieve húmeda

Distribución

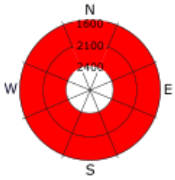

Tamaño

Origen

Tendencia

Situación secundaria

Nieve venteada

Distribución

Tamaño

Origen

Tendencia

Estado del manto nivoso

Con el humedecimiento del manto, después del último frente cálido y la lluvia en cota alta, el problema predominante será el de la nieve húmeda. Los aludes caerán de forma natural y llegarán hasta tamaño medio (con capacidad de enterrar a una persona). Se darán, sobre todo, en pendientes fuertemente inclinadas. En cota alta, cerca de las cimas, encontraremos placas de viento, bajo collados y cordales, que pueden caer al paso de un montañero y alcanzar tamaño suficiente para enterrar a una persona. Por lo general, se encuentran en laderas Este, Norte y en zonas resguardadas del viento del Oeste.

Distribución del manto nivoso

Hay nieve desde 1400-1500 m. El manto es esquiable a partir de 1600 m. Los grosores están alrededor de 110-130 cm a unos 2.200 my son superiores a los habituales.

Tendencia para las próximas 48-72h

Con el descenso térmico disminuye el problema de nieve húmeda. El fuerte viento del NW mantendrá reactivas las placas. Peligro ESTACIONARIO.

El próximo boletín será emitido el día 2026-02-11

5 MUY FUERTE	4 FUERTE	3 NOTABLE	2 LIMITADO	1 DÉBIL

EAWS EUROPEAN AVALANCHE WARNING SERVICES

ICGC Institut Cartogràfic i Geològic de Catalunya

Servei Meteorològic de Catalunya meteo.cat

Boletín de peligro de aludes Ter-Freser
Del 10/02/2026 al 11/02/2026

(Válido fuera pistas de esquí y zonas no controladas)

LIMITADO (2), miércoles.
NOTABLE (3), martes.

Situación primaria

Nieve húmeda

Distribución

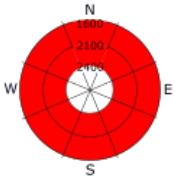

Tamaño

Origen

Tendencia

Situación secundaria

Nieve venteada

Distribución

Tamaño

Origen

Tendencia

Estado del manto nivoso

El último frente ha dejado lloviznas hasta cota alta. El manto se ha humedecido, por tanto, el problema predominante será el de la nieve húmeda. Los aludes caerán de forma natural y llegarán hasta tamaño medio (con capacidad de enterrar a un montañero). Se darán, sobre todo, en pendientes fuertemente inclinadas como canales o corredores. Localmente, no se descarta algún alud de tamaño grande (con capacidad de enterrar a un grupo de personas). Con el fuerte viento del Oeste y del Noroeste se habrán formado nuevas placas de viento, más probables en cota alta, por encima de los 2.500 m, en todas orientaciones, pero en especial en vertiente E y SE. Las más sensibles y frágiles estarán a cota alta, por debajo de collados y cordales, y podrán caer fácilmente al paso de un montañero y alcanzar tamaño suficiente para enterrar a una persona.

Distribución del manto nivoso

El manto nivoso presenta grosores muy excedentarios para la época del año. En lugares no afectados por el viento, los espesores oscilan entre 100-140 cm a unos 2.000 m, siendo esquiable a partir de unos 1.500 m.

Tendencia para las próximas 48-72h

Con el descenso térmico disminuye el problema de nieve húmeda. El fuerte viento del NW mantendrá reactivas las placas. Peligro ESTACIONARIO.

El próximo boletín será emitido el día 2026-02-11

5 MUY FUERTE	4 FUERTE	3 NOTABLE	2 LIMITADO	1 DÉBIL

EAWS EUROPEAN AVALANCHE WARNING SERVICES