BUTLLETÍ DEL PERILL D'ALLAUS DEL PRINCIPAT D'ANDORRA

Servei meteorològic nacional
Principat d'Andorra

Elaborat el 10/02/2026 16:00
Propera actualització 11/02/2026 a les 16h

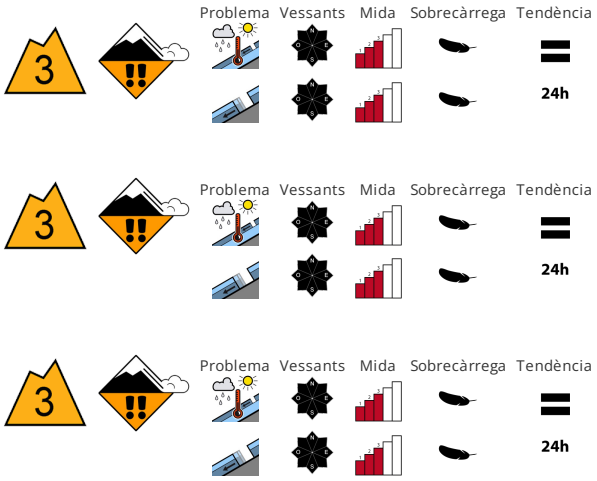

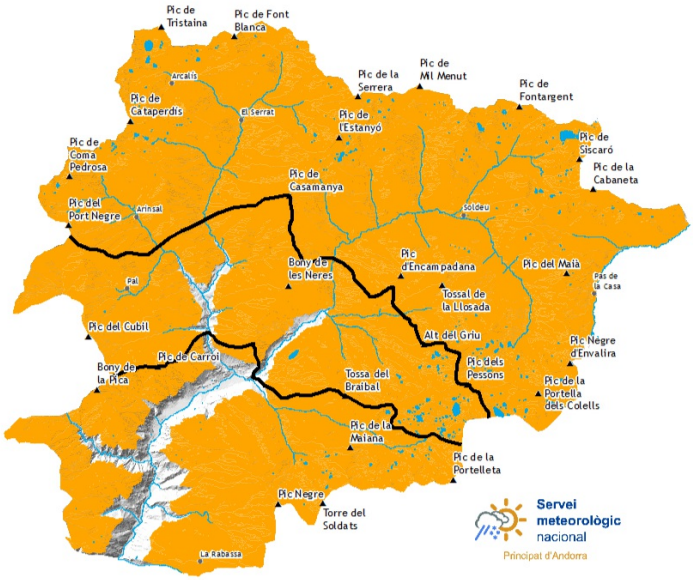

ESTABILITAT DEL MANTELL NIVAL

Amb la pujada de la cota de neu, augment clar del perill d'allaus de neu humida i de neu molt humida. A més, són d'esperar allaus de lliscament basal en qualsevol moment. Evitar les zones amb esquerdes de lliscament basal. Són d'esperar allaus naturals de mida mitjana i, localment, gran. Aquestes poden implicar les capes més profundes del mantell de neu., també en el cas de zones de sortida ja purgades. Els indrets perillosos són generalitzats. Si és possible les excursions haurien de limitar-se a terreny pla o controlat. Es recomana una selecció acurada de la ruta i mantenir la distància entre els components.

QUALITAT DE LA NEU

Sobretot prop dels cims en cotes altes els gruixos de neu varien molt per la influència del vent. El dimarts caurà pluja fins a cotes altes. La pluja causarà en una àrea extensa una clara humidificació del mantell de neu en totes les orientacions. La superfície del mantell de neu es refredarà tot just durant la nit ennuvolada.

GRUIXOS DEL MANTELL NIVAL FORA DE PISTA

Zona nord		Gruix neu		
Mantell Nival		1500m	2000m	2500m
N	1300 m	50 cm	150 cm	200 cm
S	1300 m	30 cm	100 cm	130 cm

Zona centre		Gruix neu		
Mantell Nival		1500m	2000m	2500m
N	1300 m	50 cm	150 cm	200 cm
S	1300 m	30 cm	100 cm	130 cm

Zona sud		Gruix neu		
Mantell Nival		1500m	2000m	2500m
N	1300 m	50 cm	100 cm	100 cm
S	1300 m	30 cm	70 cm	70 cm

Govern d'Andorra

EAWS EUROPEAN AVALANCHE WARNING SERVICES

Aquest butlletí ha estat elaborat seguint les normes i recomanacions de l'**European Avalanche Warning Services**, del qual el **Servei meteorològic Nacional** n'és membre

BUTLLETÍ DEL PERILL D'ALLAUS DEL PRINCIPAT D'ANDORRA

Servei meteorològic nacional
Principat d'Andorra

Informació detallada per espais naturals protegits

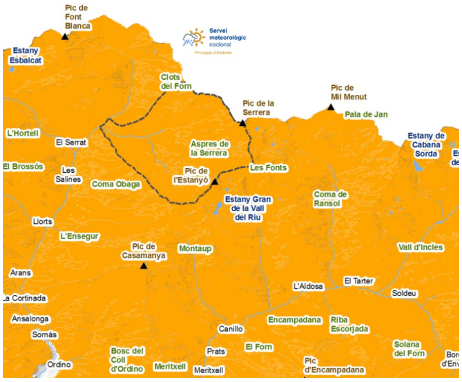

SORTENY

La pluja fins a cotes altes humidificarà les capes febles de la part superficial del mantell, acumulades en les febles nevades dels darrers dies. La previsió d´allaus humides naturals ens han de fer extremar les precaucions i limitar les activitats a terreny simple.

COMAPEDROSA

La falta de regel nocturn encara pot provocar que baixin allaus humides per les canals que creuen els camins. A més, encara que ja hi hagi hagut allaus durant l´hivern que hagin purgat alguns vessants, no podem descartar que tornin a baixar allaus grans.

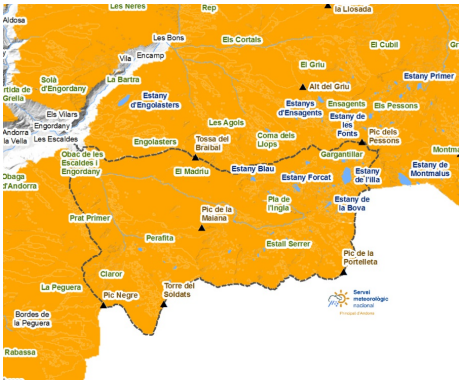

MADRIU-PERAFITA-CLAROR

Com a tot el país, haurem d´extremar les precaucions en els vessants més inclinats. La pluja causarà una fosa del mantell a les cotes més baixes, dificultant els accessos a la Vall. La neu molla i tova no suporta el pes d´un excursionista.

Govern d'Andorra

EAWS
EUROPEAN AVALANCHE WARNING SERVICES

Aquest butlletí ha estat elaborat seguint les normes i recomanacions de l'**European Avalanche Warning Services**, del qual el **Servei meteorològic Nacional** n'és membre

BUTLLETÍ DEL PERILL D'ALLAUS DEL PRINCIPAT D'ANDORRA

Servei meteorològic nacional
Principat d'Andorra

Gruixos de neu nova dels darrers dies (de les últimes 24h mesurat a les 06:00h UTC)

	06/02/2026	07/02/2026	08/02/2026	09/02/2026
FEDA (Central)	0 cm	0 cm	0 cm	0 cm
Engolasters - FEDA	0 cm	0 cm	0 cm	0 cm
Bony de les Neres	0 cm	0 cm	0 cm	11 cm
Sorteny	0 cm	3 cm	2 cm	22 cm
Les Fonts d'Arinsal	0 cm	0 cm	10 cm	15 cm
Perafita	0 cm	0 cm	0 cm	8 cm
Tossa Espiolets	0 cm	0 cm	4 cm	5 cm
Grau Roig - FEDA	0 cm	0 cm	0 cm	13 cm
Fontverd	0 cm	0 cm	0 cm	7 cm
Ransol - FEDA	0 cm	1 cm	0 cm	4 cm
Setúria	0 cm	4 cm	6 cm	12 cm
Caborreu	0 cm	0 cm	0 cm	6 cm
Coll Pa	0 cm	2 cm	3 cm	13 cm
Envalira Antenes	0 cm	0 cm	4 cm	18 cm
Vall del Riu FEDA	0 cm	9 cm	0 cm	7 cm