BUTLLETÍ DEL PERILL D'ALLAUS DEL PRINCIPAT D'ANDORRA

Elaborado el 10/02/2026 16:00
Proxima actualización 11/02/2026 a las 16h

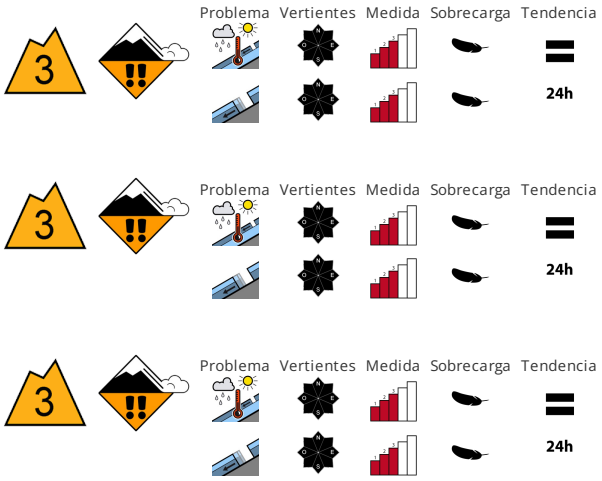

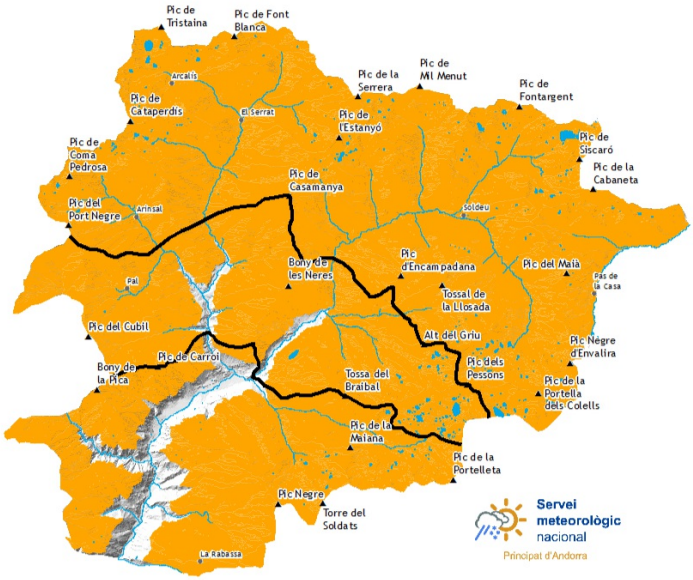

CALIDAD DE LA NIEVE

Con la subida de la cota de nieve, claro aumento del peligro de aludes de nieve húmeda o muy húmeda. Además son de esperar aludes de deslizamiento basal en cualquier momento. Evitar las zonas con grietas de deslizamiento basal. Son son probables aludes naturales de tamaño mediano y, locamente, grande. Estos pueden implicar las capas más profundas del manto de nieve., también en el caso de zonas de salida ya purgadas. Los lugares peligrosos son generalizados. Si es posible, las excursiones deberían limitarse a terrreno llano o controlado. Se recomienda una elección cuidadosa de la ruta y mantener la distancia de seguridad entre los miembros del grupo.

ESTABILIDAD DEL MANTO NIVOSO

Cerca de las cumbres en cotas altas los espesores de nieve varían mucho por la influencia del viento. El martes caerá lluvia hasta en cotas altas. La lluvia causará en un área extensa una clara humidificación del manto de nieve en todas las orientaciones. La superficie del manto de nieve se enfriará apenas durante la noche nublada.

ESPESORES DEL MANTO NIVOSO FUERA DE PISTA

Zona norte		Espesor nieve		
Manto Nival		1500m	2000m	2500m
N	1300 m	50 cm	150 cm	200 cm
S	1300 m	30 cm	100 cm	130 cm

zona centro		Espesor nieve		
Manto Nival		1500m	2000m	2500m
N	1300 m	50 cm	150 cm	200 cm
S	1300 m	30 cm	100 cm	130 cm

Zona sur		Espesor nieve		
Manto Nival		1500m	2000m	2500m
N	1300 m	50 cm	100 cm	100 cm
S	1300 m	30 cm	70 cm	70 cm

Govern d'Andorra

EAWS EUROPEAN AVALANCHE WARNING SERVICES

Aquest butlletí ha estat elaborat seguint les normes i recomanacions de l'**European Avalanche Warning Services**, del qual el **Servei meteorològic Nacional** n'és membre

BUTLLETÍ DEL PERILL D'ALLAUS DEL PRINCIPAT D'ANDORRA

Servei meteorològic nacional
Principat d'Andorra

Información detallada por espacios naturales protegidos

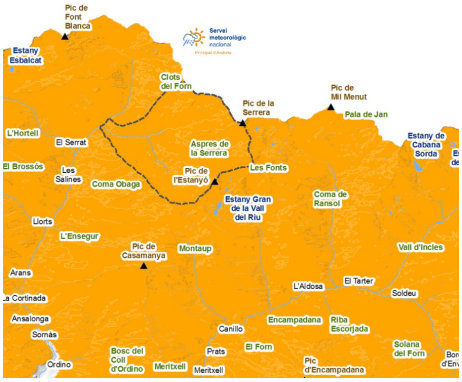

SORTENY

Las lluvias que llegarán a gran altura humedecerán las capas débiles de la parte superficial del manto, acumuladas en las nieves débiles de los últimos días. La previsión de aludes naturales húmedos debería hacernos extremar las precauciones y limitar las actividades a terrenos llanos. , , ,

COMAPEDROSA

La falta de heladas nocturnas aún puede provocar la caída de avalanchas de agua por los canales que cruzan las carreteras. Además, aunque ya se han producido durante el invierno aludes que han despejado algunas laderas, no podemos descartar que vuelvan a caer grandes aludes. , , ,

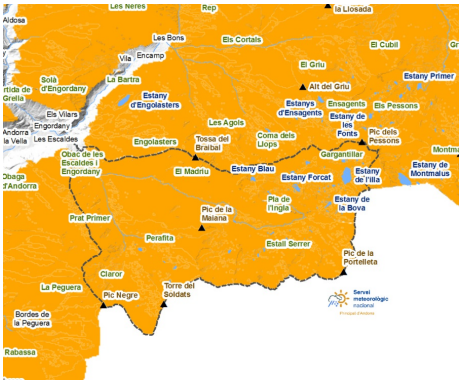

MADRIU-PERAFITA-CLAROR

Como en todo el país, tendremos que extremar las precauciones en las pendientes más pronunciadas. Las lluvias provocarán un derretimiento del manto en las cotas más bajas, dificultando el acceso al Valle. La nieve blanda y blanda no puede soportar el peso de un excursionista. , , , , ,

Govern d'Andorra

EAWS
EUROPEAN AVALANCHE WARNING SERVICES

Aquest butlletí ha estat elaborat seguint les normes i recomanacions de l'**European Avalanche Warning Services**, del qual el **Servei meteorològic Nacional** n'és membre

BUTLLETÍ DEL PERILL D'ALLAUS DEL PRINCIPAT D'ANDORRA

Servei meteorològic nacional
Principat d'Andorra

Espesores de nieve nueva de los últimos días (de las ultimas 24h mesurado a las 06:00h UTC)

	06/02/2026	07/02/2026	08/02/2026	09/02/2026
FEDA (Central)	0 cm	0 cm	0 cm	0 cm
Engolasters - FEDA	0 cm	0 cm	0 cm	0 cm
Bony de les Neres	0 cm	0 cm	0 cm	11 cm
Sorteny	0 cm	3 cm	2 cm	22 cm
Les Fonts d'Arinsal	0 cm	0 cm	10 cm	15 cm
Perafita	0 cm	0 cm	0 cm	8 cm
Tossa Espiolets	0 cm	0 cm	4 cm	5 cm
Grau Roig - FEDA	0 cm	0 cm	0 cm	13 cm
Fontverd	0 cm	0 cm	0 cm	7 cm
Ransol - FEDA	0 cm	1 cm	0 cm	4 cm
Setúria	0 cm	4 cm	6 cm	12 cm
Caborreu	0 cm	0 cm	0 cm	6 cm
Coll Pa	0 cm	2 cm	3 cm	13 cm
Envalira Antenes	0 cm	0 cm	4 cm	18 cm
Vall del Riu FEDA	0 cm	9 cm	0 cm	7 cm