BUTLLETÍ DEL PERILL D'ALLAUS DEL PRINCIPAT D'ANDORRA

Préparé le 10/02/2026 16:00
Prochaine mise à jour le 11/02/2026 à 16h

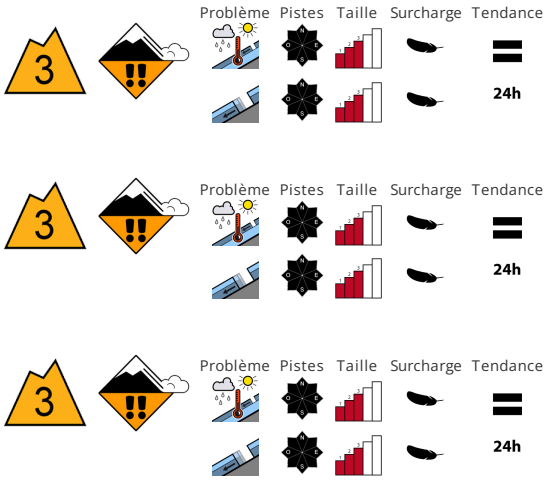

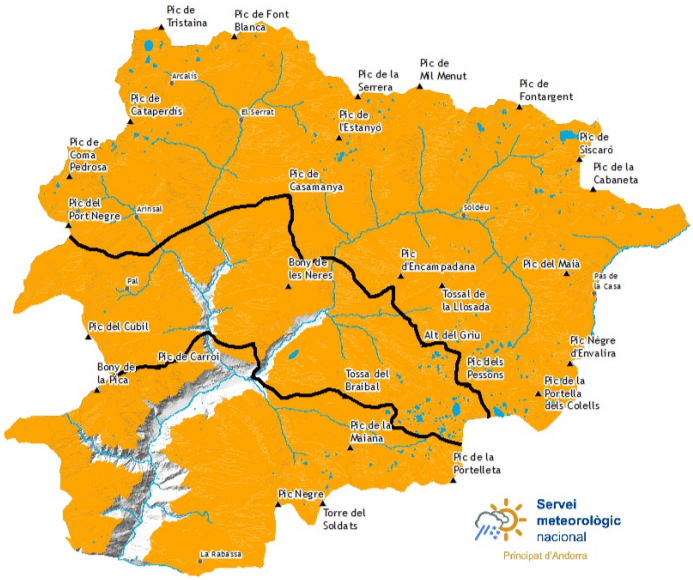

STABILITÉ DU MANTEAU NEIGEUX

Augmentation marquée du danger d'avalanches humides et mouillées avec la remontée de la limite des chutes de neige. En outre, des avalanches de glissement sont à attendre à tout moment.. Les zones présentant des fissures de glissement doivent être évitées.. Des avalanches spontanées de moyenne et rarement grande taille sont à attendre. Explication: celles-ci ne peut signifier que celles-ci avalanches peuvent se déclencher dans les couches profondes. , ceci aussi au niveau des zones de départ déjà déchargées. Les endroits dangereux sont largement répandus. Les randonnées devraient dans la mesure du possible être limitées au terrain être limité à plat ou sécurisé. Un choix prudent d'itinéraire et des distances de délestage sont recommandés..

QUALITÈ DE LA NEIGE

À proximité des sommets à haute altitude on trouve suivant l'influence du vent des hauteurs de neiges très différentes. Mardi il tombera de la pluie jusqu'à haute altitude. La pluie entraîne à toutes les expositions généralement une humidification nette du manteau neigeux. La surface de la neige ne se refroidit qu'à peine pendant la nuit couverte.

EPAISSEUR DE NEIGE HORS PISTE

Zone nord		Epaisseur de neige		
Nival manteau		1500m	2000m	2500m
N	1300 m	50 cm	150 cm	200 cm
S	1300 m	30 cm	100 cm	130 cm

Zone centre		Epaisseur de neige		
Nival manteau		1500m	2000m	2500m
N	1300 m	50 cm	150 cm	200 cm
S	1300 m	30 cm	100 cm	130 cm

Zone sud		Epaisseur de neige		
Nival manteau		1500m	2000m	2500m
N	1300 m	50 cm	100 cm	100 cm
S	1300 m	30 cm	70 cm	70 cm

BUTLLETÍ DEL PERILL D'ALLAUS DEL PRINCIPAT D'ANDORRA

Servei meteorològic nacional
Principat d'Andorra

Des informations détaillées par espace naturel protégé

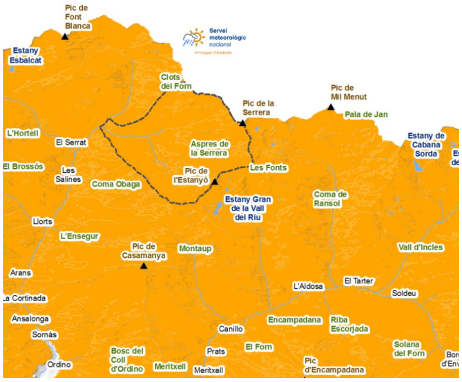

SORTENY

La pluie jusqu'aux hautes altitudes humidifiera les couches fragiles de la partie superficielle du manteau, accumulées dans les faibles neiges des derniers jours. La prévision d'avalanches mouillées naturelles devrait nous inciter à prendre des précautions extrêmes et à limiter les activités aux terrains plats. , , ,

COMAPEDROSA

L'absence de gel nocturne peut encore provoquer des avalanches mouillées dans les canaux qui traversent les routes. De plus, même s'il y a déjà eu des avalanches au cours de l'hiver qui ont dégagé certaines pentes, on ne peut pas exclure que de grosses avalanches redescendent. , , ,

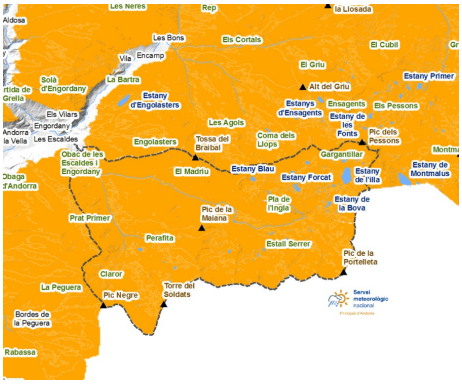

MADRIU-PERAFITA-CLAROR

Comme dans tout le pays, il faudra prendre des précautions extrêmes sur les pentes les plus raides. La pluie provoquera une fonte du manteau aux niveaux les plus bas, rendant l'accès à la Vallée difficile. La neige molle et molle ne peut supporter le poids d'un randonneur. , , , , ,

Govern d'Andorra

EAWS
EUROPEAN AVALANCHE WARNING SERVICES

Aquest butlletí ha estat elaborat seguint les normes i recomanacions de l'**European Avalanche Warning Services**, del qual el **Servei meteorològic Nacional** n'és membre

BUTLLETÍ DEL PERILL D'ALLAUS DEL PRINCIPAT D'ANDORRA

Servei meteorològic nacional
Principat d'Andorra

Couche de neige fraiche des derniers jours (De 24 h mesurée à 06:00 h UTC)

	06/02/2026	07/02/2026	08/02/2026	09/02/2026
FEDA (Central)	0 cm	0 cm	0 cm	0 cm
Engolasters - FEDA	0 cm	0 cm	0 cm	0 cm
Bony de les Neres	0 cm	0 cm	0 cm	11 cm
Sorteny	0 cm	3 cm	2 cm	22 cm
Les Fonts d'Arinsal	0 cm	0 cm	10 cm	15 cm
Perafita	0 cm	0 cm	0 cm	8 cm
Tossa Espiolets	0 cm	0 cm	4 cm	5 cm
Grau Roig - FEDA	0 cm	0 cm	0 cm	13 cm
Fontverd	0 cm	0 cm	0 cm	7 cm
Ransol - FEDA	0 cm	1 cm	0 cm	4 cm
Setúria	0 cm	4 cm	6 cm	12 cm
Caborreu	0 cm	0 cm	0 cm	6 cm
Coll Pa	0 cm	2 cm	3 cm	13 cm
Envalira Antenes	0 cm	0 cm	4 cm	18 cm
Vall del Riu FEDA	0 cm	9 cm	0 cm	7 cm