MINISTERO DELLA DIFESA

meteomont
Servizio Nazionale di previsione neve e valanghe

EAWS EUROPEAN AVALANCHE WARNING SERVICES

CARABINIERI

ALPI CARNICHE OCCIDENTALI

Bollettino Valanghe N. 341/2026 del 10/02/2026 ore 14.00
Validità 48 ore prossima emissione 11/02/2026

A cura del Servizio METEOMONT dell'ARMA dei CARABINIERI
In collaborazione con Servizio Meteorologico dell'Aeronautica militare

SITUAZIONE alle 14:00 del 10/02/2026

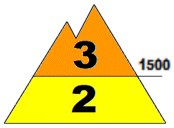

SITUAZIONE TIPO: neve a debole coesione e vento.

SITUAZIONE TIPO: situazione primaverile.

Quota neve (mslm)	Nord	Sud
	500 - 700	800 - 900

Altezza Neve (cm)	Neve al suolo	Neve Fresca	Quota (mslm)
	119	01	1976
	13	00	652

VALANGHE OSSERVATE: Alcune valanghe di medie dimensioni, Valanghe di neve a debole coesione di fondo.

PREVISIONI 11/02/2026

GRADO DI PERICOLO: MARCATO 3

SITUAZIONE TIPO: neve a debole coesione e vento.

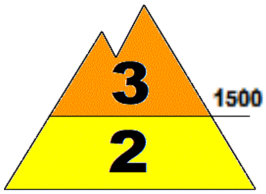

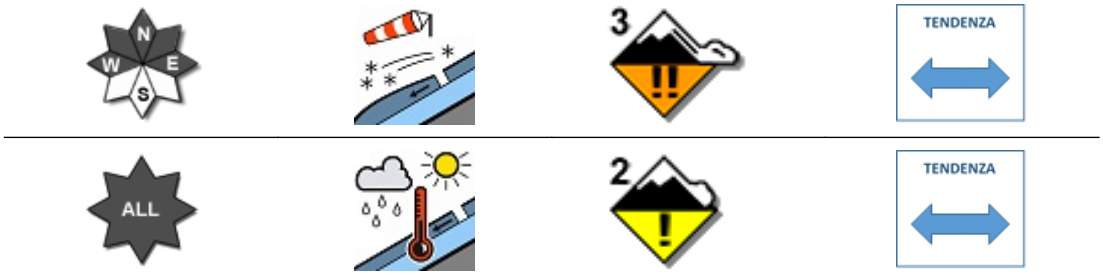

SITUAZIONE TIPO: situazione primaverile.

MANTO NEVOSO: La stabilità del manto nevoso è scarsa su alcuni punti (aree) per versanti da ovest a est al di sopra di 1500 mslm, possibili valanghe di dimensioni grandi.
La stabilità del manto nevoso è scarsa su alcuni punti (aree) per tutte le esposizioni al di sotto di 1500 mslm, possibili valanghe di dimensioni medie.

AVVERTENZE

Attenzione alla presenza di accumuli eolici di difficile individuazione.

SCALA EUROPEA DEL GRADO DI PERICOLO VALANGHE

LEGENDA PROBLEMA

Bollettino realizzato su scala sinottica-regionale (standard EAWS). La sua valutazione non può escludere in alcun modo la necessità di una seria e capace valutazione locale del pericolo (singolo pendio) che può essere anche sensibilmente diverso. Le previsioni meteorologiche sono relative all'orario UTC (per l'Italia +1 in inverno e +2 in estate).

MINISTERO DELLA DIFESA

meteomont
Servizio Nazionale di previsione neve e valanghe

EAWS EUROPEAN AVALANCHE WARNING SERVICES

CARABINIERI

ALPI CARNICHE OCCIDENTALI

PREVISIONE METEO

Quota		11/02/2026 h6:00	11/02/2026 h12:00	11/02/2026 h18:00
1000	Venti	00 Calma	00 Calma	01 nodi da N-Ovest
	Temperature	-02 °C	+00 °C	+00 °C
	Temp.percepita	-2 °C	0 °C	0 °C
2000	Venti	03 Nodi da S-Ovest	01 nodi da N-Ovest	02 nodi da N-Ovest
	Temperature	-03 °C	-01 °C	+00 °C
	Temp.percepita	-5 °C	-1 °C	0 °C
3000	Venti	09 Nodi da Ovest	05 nodi da N-Ovest	10 nodi da N-Ovest
	Temperature	-07 °C	-05 °C	-07 °C
	Temp.percepita	-13 °C	-9 °C	-14 °C
Zero termico		1300-1500 m.	1500-1700 m.	1900-2100 m.
Fenomeno			—	—
Stato del cielo				

LEGENDA FENOMENI

— Assenza Fenomeni · Nebbia · Foschia · Pioggia debole · Pioggia moderata · Pioggia forte · Temporali

Nevicata debole · Nevicata moderata · Nevicata forte

STATO DEL CIELO

Sereno · Poco nuvoloso · Nuvoloso · Molto nuvoloso · Coperto

Parametri meteonivometrici registrati presso i campi di rilevamento il 10/02/2026.

Località	Comune	Quota (m.s.l.m.)	Altezza neve (cm)	Neve caduta nelle 24 ore (cm)	Temp. Min (°C)	Temp. Max (°C)	Condizioni del tempo
MALGA VARMOST	Forni di Sopra (UD)	1728	94	0	N.P.	N.P.	Assenza di precipitazioni
SAURIS DI SOPRA	Sauris (UD)	1425	66	0	-2	+5	Assenza di precipitazioni

(*) Rilievi fuori campo

L'INFORMAZIONE E' PREVENZIONE - LEGGI L'ATTUALE GRADO DI PERICOLO VALANGHE!

IL CAPO DEL CENTRO NAZIONALE METEOMONT
(Ten. Col. RFI Emanuela Gini)
FIRMA AUTOGRAFA OMESSA AI SENSI
DELL'ART.3 DEL D.LGS N.39/1993