MINISTERO DELLA DIFESA

meteomont Servizio Nazionale di previsione neve e valanghe

EAWS EUROPEAN AVALANCHE WARNING SERVICES

CARABINIERI

ALPI OROBICHE

Bollettino Valanghe N. 341/2026 del 10/02/2026 ore 14.00
Validità 48 ore prossima emissione 11/02/2026

A cura del Servizio METEOMONT dell'ARMA dei CARABINIERI
In collaborazione con Servizio Meteorologico dell'Aeronautica militare

SITUAZIONE alle 14:00 del 10/02/2026

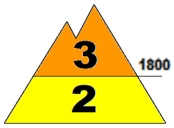

SITUAZIONE TIPO: strato debole persistente basale.

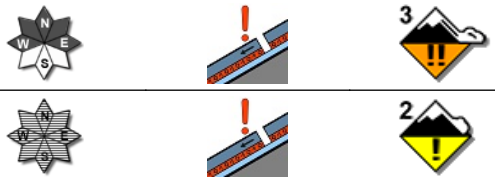

SITUAZIONE TIPO: passaggio da poca a molta neve.

Quota neve (mslm)	Nord	Sud
	1300 - 1400	1300 - 1400

Altezza Neve (cm)	Neve al suolo	Neve Fresca	Quota (mslm)
	120	001	2080
	67	002	1760

VALANGHE OSSERVATE: Nessuna valanga.

PREVISIONI 11/02/2026

GRADO DI PERICOLO: MARCATO 3

SITUAZIONE TIPO: strato debole persistente basale.

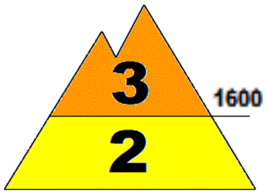

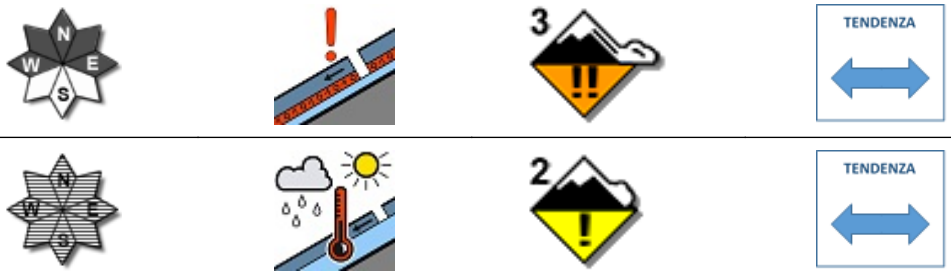

SITUAZIONE TIPO: pioggia su neve.

MANTO NEVOSO: La stabilità del manto nevoso è molto scarsa su molti punti (aree) per versanti da ovest a est al di sopra di 1600 mslm, possibili valanghe di dimensioni medie.
La stabilità del manto nevoso è scarsa su alcuni punti (aree) per isolati pendii al di sotto di 1600 mslm, possibili valanghe di dimensioni medie.

AVVERTENZE

In considerazione delle avverse condizioni meteorologiche previste, e della scarsa visibilità, risulterà difficoltosa l'individuazione dell'itinerario e della valutazione del singolo pendio.

SCALA EUROPEA DEL GRADO DI PERICOLO VALANGHE

LEGENDA PROBLEMA

Bollettino realizzato su scala sinottica-regionale (standard EAWS). La sua valutazione non può escludere in alcun modo la necessità di una seria e capace valutazione locale del pericolo (singolo pendio) che può essere anche sensibilmente diverso. Le previsioni meteorologiche sono relative all'orario UTC (per l'Italia +1 in inverno e +2 in estate).

ALPI OROBICHE

PREVISIONE METEO

Quota		11/02/2026 h6:00	11/02/2026 h12:00	11/02/2026 h18:00
1000	Venti	00 Calma	01 Nodi da Nord	02 Nodi da Nord
	Temperature	-01 °C	+00 °C	+00 °C
	Temp.percepita	-1 °C	0 °C	0 °C
2000	Venti	00 Calma	02 Nodi da Nord	02 Nodi da Nord
	Temperature	-02 °C	+00 °C	+01 °C
	Temp.percepita	-2 °C	0 °C	1 °C
3000	Venti	06 nodi da N-Ovest	09 nodi da N-Ovest	07 nodi da N-Ovest
	Temperature	-07 °C	-06 °C	-07 °C
	Temp.percepita	-12 °C	-12 °C	-13 °C
Zero termico		1400-1600 m.	1700-1900 m.	1600-1800 m.
Fenomeno			—	—
Stato del cielo				

LEGENDA FENOMENI

— Assenza Fenomeni · Nebbia · Foschia · Pioggia debole · Pioggia moderata · Pioggia forte · Temporali

Nevicata debole · Nevicata moderata · Nevicata forte

STATO DEL CIELO

Sereno · Poco nuvoloso · Nuvoloso · Molto nuvoloso · Coperto

Parametri meteonivometrici registrati presso i campi di rilevamento il 10/02/2026.

Località	Comune	Quota (m.s.l.m.)	Altezza neve (cm)	Neve caduta nelle 24 ore (cm)	Temp. Min (°C)	Temp. Max (°C)	Condizioni del tempo
VODALA	Gromo (BG)	1635	67	2	-2	+1	Assenza di precipitazioni
QUARTA BAITA	Foppolo (BG)	1760	67	2	-4	+1	Assenza di precipitazioni
CIMA BIANCA	Colere (BG)	2080	120	1	-5	0	Assenza di precipitazioni
BAITE SALINE *	Vilminore di Scalve (BG)	1748	85	2	N.P.	N.P.	Assenza di precipitazioni

(*) Rilievi fuori campo

L'INFORMAZIONE E' PREVENZIONE - LEGGI L'ATTUALE GRADO DI PERICOLO VALANGHE!

IL CAPO DEL CENTRO NAZIONALE METEOMONT
(Ten. Col. RFI Emanuela Gini)
FIRMA AUTOGRAFA OMESSA AI SENSI
DELL'ART.3 DEL D.LGS N.39/1993

Bollettino realizzato su scala sinottica-regionale (standard EAWS). La sua valutazione non può escludere in alcun modo la necessità di una seria e capace valutazione locale del pericolo (singolo pendio) che può essere anche sensibilmente diverso. Le previsioni meteorologiche sono relative all'orario UTC (per l'Italia +1 in inverno e +2 in estate).