MINISTERO DELLA DIFESA

meteomont Servizio Nazionale di previsione neve e valanghe

EAWS EUROPEAN AVALANCHE WARNING SERVICES

CARABINIERI

AERONAUTICA MILITARE SERVIZIO METEOROLOGICO

PREALPI LOMBARDE

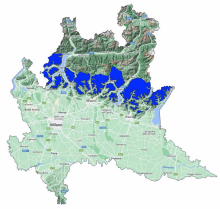

Bollettino Valanghe N. 340/2026 del 10/02/2026 ore 14.00
Validità 48 ore prossima emissione 11/02/2026

A cura del Servizio METEOMONT dell'ARMA dei CARABINIERI
In collaborazione con Servizio Meteorologico dell'Aeronautica militare

SITUAZIONE alle 14:00 del 10/02/2026

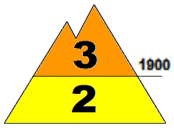

SITUAZIONE TIPO: strato debole persistente basale.



SITUAZIONE TIPO: pioggia su neve.

Quota neve (mslm)	Nord	Sud
	1200 - 1400	1000 - 1200

Altezza Neve (cm)	Neve al suolo	Neve Fresca	Quota (mslm)
	72	4	1724
	33	0	1445

VALANGHE OSSERVATE: Valanghe di piccole dimensioni, Valanghe di neve a debole coesione di fondo.

PREVISIONI 11/02/2026

GRADO DI PERICOLO: MARCATO 3

SITUAZIONE TIPO: strato debole persistente basale.

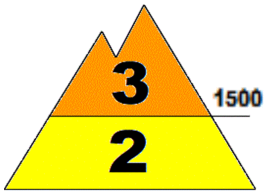

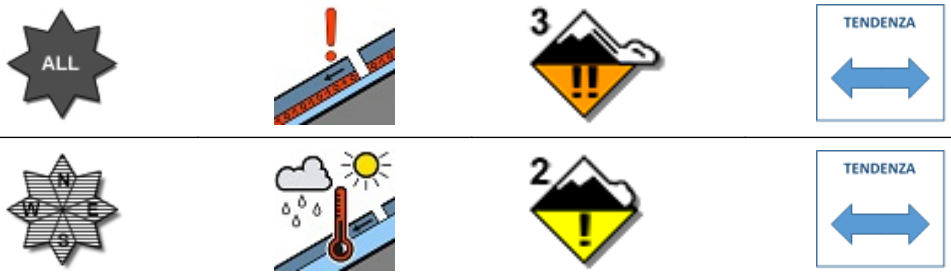

SITUAZIONE TIPO: pioggia su neve.

MANTO NEVOSO: La stabilità del manto nevoso è molto scarsa su molti punti (aree) per tutte le esposizioni al di sopra di 1500 mslm, possibili valanghe di dimensioni medie.
La stabilità del manto nevoso è scarsa su alcuni punti (aree) per isolati pendii al di sotto di 1500 mslm, possibili valanghe di dimensioni medie.

AVVERTENZE

In considerazione delle avverse condizioni meteorologiche previste, e della scarsa visibilità, risulterà difficoltosa l'individuazione dell'itinerario e della valutazione del singolo pendio.

SCALA EUROPEA DEL GRADO DI PERICOLO VALANGHE

LEGENDA PROBLEMA

Bollettino realizzato su scala sinottica-regionale (standard EAWS). La sua valutazione non può escludere in alcun modo la necessità di una seria e capace valutazione locale del pericolo (singolo pendio) che può essere anche sensibilmente diverso. Le previsioni meteorologiche sono relative all'orario UTC (per l'Italia +1 in inverno e +2 in estate).

MINISTERO DELLA DIFESA

meteomont
Servizio Nazionale di previsione neve e valanghe

EAWS EUROPEAN AVALANCHE WARNING SERVICES

CARABINIERI

PREALPI LOMBARDE

PREVISIONE METEO

Quota		11/02/2026 h6:00	11/02/2026 h12:00	11/02/2026 h18:00
1000	Venti	01 Nodi da S-Ovest	01 nodi da N-Ovest	02 Nodi da Nord
	Temperature	-01 °C	+01 °C	+02 °C
	Temp.percepita	-1 °C	1 °C	2 °C
2000	Venti	02 Nodi da Ovest	03 nodi da N-Ovest	03 Nodi da Nord
	Temperature	-03 °C	+00 °C	+01 °C
	Temp.percepita	-3 °C	-2 °C	-1 °C
3000	Venti	08 nodi da N-Ovest	11 nodi da N-Ovest	07 nodi da N-Ovest
	Temperature	-06 °C	-06 °C	-07 °C
	Temp.percepita	-12 °C	-13 °C	-13 °C
Zero termico		1300-1500 m.	1900-2100 m.	2000-2200 m.
Fenomeno			—	—
Stato del cielo				

LEGENDA FENOMENI

— Assenza Fenomeni · Nebbia · Foschia · Pioggia debole · Pioggia moderata · Pioggia forte · Temporali

Nevicata debole · Nevicata moderata · Nevicata forte

STATO DEL CIELO

Sereno · Poco nuvoloso · Nuvoloso · Molto nuvoloso · Coperto

Parametri meteonivometrici registrati presso i campi di rilevamento il 10/02/2026.

Località	Comune	Quota (m.s.l.m.)	Altezza neve (cm)	Neve caduta nelle 24 ore (cm)	Temp. Min (°C)	Temp. Max (°C)	Condizioni del tempo
PIANI DI BOBBIO	Barzio (LC)	1724	72	4	-1	+2	Precipitazioni all'orizzonte (pioggia, neve, grandine, temporali) ma non sulla stazione
PASSO MANIVA	Collio (BS)	1751	48	12	-5	+8	Assenza di precipitazioni
ALPE PAGLIO *	Casargo (LC)	1451	23	0	N.P.	N.P.	Assenza di precipitazioni
DASDANA *	Collio (BS)	2100	115	12	N.P.	N.P.	Assenza di precipitazioni

(*) Rilievi fuori campo

L'INFORMAZIONE E' PREVENZIONE - LEGGI L'ATTUALE GRADO DI PERICOLO VALANGHE!

IL CAPO DEL CENTRO NAZIONALE METEOMONT
(Ten. Col. RFI Emanuela Gini)
FIRMA AUTOGRAFA OMESSA AI SENSI
DELL'ART.3 DEL D.LGS N.39/1993

Bollettino realizzato su scala sinottica-regionale (standard EAWS). La sua valutazione non può escludere in alcun modo la necessità di una seria e capace valutazione locale del pericolo (singolo pendio) che può essere anche sensibilmente diverso. Le previsioni meteorologiche sono relative all'orario UTC (per l'Italia +1 in inverno e +2 in estate).