MINISTERO DELLA DIFESA

meteomont
Servizio Nazionale di previsione neve e valanghe

EAWS EUROPEAN AVALANCHE WARNING SERVICES

CARABINIERI

ALPI APUANE - APPENNINO TOSCANO SETTENTRIONALE

Bollettino Valanghe N. 253/2026 del 09/02/2026 ore 14.00
Validità 48 ore prossima emissione 10/02/2026
A cura del Servizio METEOMONT dell'ARMA dei CARABINIERI
In collaborazione con Servizio Meteorologico dell'Aeronautica militare

SITUAZIONE alle 14:00 del 09/02/2026

SITUAZIONE TIPO: neve pallottolare sepolta.

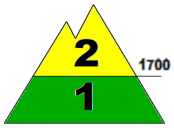



SITUAZIONE TIPO: pioggia su neve.

Quota neve (mslm)	Nord	Sud
	1200 - 1400	1300 - 1500

Altezza Neve (cm)	Neve al suolo	Neve Fresca	Quota (mslm)
	145	001	1660
	049	000	1340

VALANGHE OSSERVATE: Nessuna valanga.

PREVISIONI 10/02/2026

GRADO DI PERICOLO: MODERATO 2

SITUAZIONE TIPO: neve pallottolare sepolta.

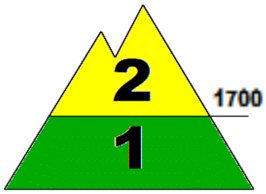

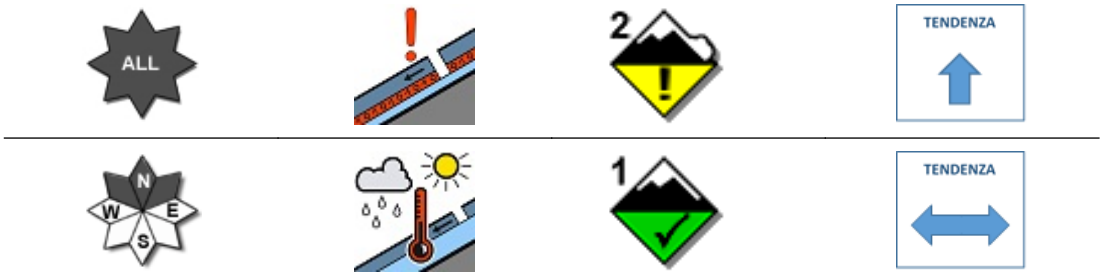

SITUAZIONE TIPO: pioggia su neve.

MANTO NEVOSO: La stabilità del manto nevoso è discreta su molti punti (aree) per tutte le esposizioni al di sopra di 1700 mslm, possibili valanghe di dimensioni medie.
La stabilità del manto nevoso è buona su pochi punti (aree) per versanti settentrionali al di sotto di 1700 mslm, possibili valanghe di dimensioni medie.

AVVERTENZE

In considerazione degli importanti accumuli di neve ventata in conche, canaloni, cambi di pendenza e pendii sotto vento in genere, è richiesta un'ottima valutazione locale della stabilità ed individuazione dell'itinerario.

SCALA EUROPEA DEL GRADO DI PERICOLO VALANGHE

5 - MOLTO FORTE | 4 - FORTE | 3 - MARCATO | 2 - MODERATO | 1 - DEBOLE | NO NEVE | NO INFO

LEGENDA PROBLEMA

NEVE FRESCA | LASTRONI DA VENTO | STRATI DEBOLI PERSISTENTI | NEVE BAGNATA | SLITTAMENTO | CORNICI | NESSUN PROBLEMA VALANGHIVO EVIDENTE | NO_INFO

Bollettino realizzato su scala sinottica-regionale (standard EAWS). La sua valutazione non può escludere in alcun modo la necessità di una seria e capace valutazione locale del pericolo (singolo pendio) che può essere anche sensibilmente diverso. Le previsioni meteorologiche sono relative all'orario UTC (per l'Italia +1 in inverno e +2 in estate).

MINISTERO DELLA DIFESA

meteomont
Servizio Nazionale di previsione neve e valanghe

EAWS EUROPEAN AVALANCHE WARNING SERVICES

CARABINIERI

ALPI APUANE - APPENNINO TOSCANO SETTENTRIONALE

PREVISIONE METEO

Quota		10/02/2026 h6:00	10/02/2026 h12:00	10/02/2026 h18:00
1000	Venti	01 Nodi da S-Ovest	03 Nodi da S-Ovest	04 Nodi da S-Ovest
	Temperature	+01 °C	+02 °C	+02 °C
	Temp.percepita	1 °C	0 °C	-0 °C
2000	Venti	07 Nodi da Ovest	11 Nodi da S-Ovest	14 Nodi da S-Ovest
	Temperature	-03 °C	-03 °C	-02 °C
	Temp.percepita	-8 °C	-9 °C	-9 °C
3000	Venti	09 Nodi da Ovest	13 Nodi da Ovest	13 Nodi da Ovest
	Temperature	-09 °C	-08 °C	-07 °C
	Temp.percepita	-16 °C	-16 °C	-15 °C
Zero termico		1500-1700 m.	1500-1700 m.	1500-1700 m.
Fenomeno		—		
Stato del cielo				

LEGENDA FENOMENI

Assenza Fenomeni · Nebbia · Foschia · Pioggia debole · Pioggia moderata · Pioggia forte · Temporali

Nevicata debole · Nevicata moderata · Nevicata forte

STATO DEL CIELO

Sereno · Poco nuvoloso · Nuvoloso · Molto nuvoloso · Coperto

Parametri meteonivometrici registrati presso i campi di rilevamento il 09/02/2026.

Località	Comune	Quota (m.s.l.m.)	Altezza neve (cm)	Neve caduta nelle 24 ore (cm)	Temp. Min (°C)	Temp. Max (°C)	Condizioni del tempo
PONTE ALLE LIME	Abetone Cutigliano (PT)	1340	49	0	N.P.	N.P.	Nevicata debole intermittente
ORECCHIELLA	San Romano in Garfagnana (LU)	1240	0	0	+2	+5	Assenza di precipitazioni
FAGGIO DI MARIA *	Abetone Cutigliano (PT)	1550	50	1	N.P.	N.P.	Assenza di precipitazioni
PASSO CROCE ARCANA *	Abetone Cutigliano (PT)	1660	145	1	N.P.	N.P.	Nevicata debole intermittente
SELLA DI CAMPAIANA *	Villa Collemandina (LU)	1574	32	0	N.P.	N.P.	Assenza di precipitazioni

(*) Rilievi fuori campo

L'INFORMAZIONE E' PREVENZIONE - LEGGI L'ATTUALE GRADO DI PERICOLO VALANGHE!

IL CAPO DEL CENTRO NAZIONALE METEOMONT
(Ten. Col. RFI Emanuela Gini)
FIRMA AUTOGRAFA OMESSA AI SENSI
DELL'ART.3 DEL D.LGS N.39/1993

Bollettino realizzato su scala sinottica-regionale (standard EAWS). La sua valutazione non può escludere in alcun modo la necessità di una seria e capace valutazione locale del pericolo (singolo pendio) che può essere anche sensibilmente diverso. Le previsioni meteorologiche sono relative all'orario UTC (per l'Italia +1 in inverno e +2 in estate).