# MAJELLA

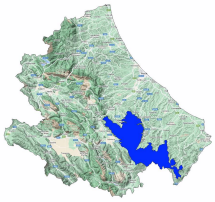

Bollettino Valanghe N. 328/2026 del 09/02/2026 ore 14.00
Validità 48 ore prossima emissione 10/02/2026
**A cura del Servizio METEOMONT dell'ARMA dei CARABINIERI**
**In collaborazione con Servizio Meteorologico dell'Aeronautica militare**

## SITUAZIONE alle 14:00 del 09/02/2026

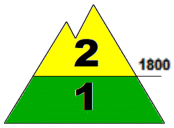


**SITUAZIONE TIPO: passaggio da poca a molta neve.**




**SITUAZIONE TIPO: situazione primaverile.**

| Quota neve (mslm) | Nord | Sud |
|---|---|---|
| | 1500 - 1600 | 1800 - 1900 |

| Altezza Neve (cm) | Neve al suolo | Neve Fresca | Quota (mslm) |
|---|---|---|---|
| | 019 | 002 | 1650 |
| | 000 | 000 | 1270 |

**VALANGHE OSSERVATE: Nessuna valanga.**

## PREVISIONI 10/02/2026

## GRADO DI PERICOLO: MODERATO 2

## SITUAZIONE TIPO: passaggio da poca a molta neve.

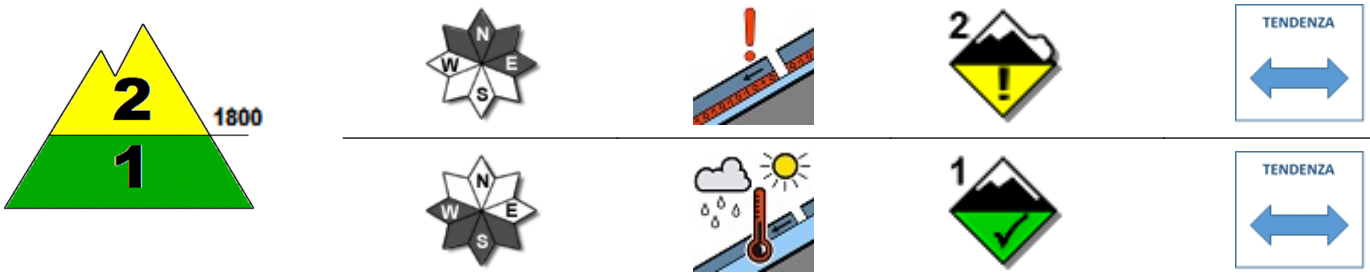


## SITUAZIONE TIPO: situazione primaverile.

**MANTO NEVOSO: La stabilità del manto nevoso è discreta su alcuni punti (aree) per versanti in ombra al di sopra di 1800 mslm, possibili valanghe di dimensioni medie.**
**La stabilità del manto nevoso è discreta su molti punti (aree) per versanti al sole al di sotto di 1800 mslm, possibili valanghe di dimensioni piccole.**

## AVVERTENZE

Meteomont rammenta ARTVA, pala e sonda sempre al seguito.

## SCALA EUROPEA DEL GRADO DI PERICOLO VALANGHE

## LEGENDA PROBLEMA

**Bollettino realizzato su scala sinottica-regionale (standard EAWS). La sua valutazione non può escludere in alcun modo la necessità di una seria e capace valutazione locale del pericolo (singolo pendio) che può essere anche sensibilmente diverso. Le previsioni meteorologiche sono relative all'orario UTC (per l'Italia +1 in inverno e +2 in estate).**

MINISTERO DELLA DIFESA

meteomont
Servizio Nazionale di previsione neve e valanghe

EAWS EUROPEAN AVALANCHE WARNING SERVICES

CARABINIERI

# MAJELLA

## PREVISIONE METEO

| Quota | | 10/02/2026 h6:00 | 10/02/2026 h12:00 | 10/02/2026 h18:00 |
|---|---|---|---|---|
| 1000 | Venti | 02 Nodi da S-Ovest | 02 Nodi da S-Ovest | 02 Nodi da S-Ovest |
| | Temperature | +00 °C | +02 °C | +01 °C |
| | Temp.percepita | 0 °C | 2 °C | 1 °C |
| 2000 | Venti | 03 Nodi da Ovest | 04 Nodi da S-Ovest | 04 Nodi da S-Ovest |
| | Temperature | -01 °C | -01 °C | -01 °C |
| | Temp.percepita | -3 °C | -4 °C | -4 °C |
| 3000 | Venti | 03 nodi da Ovest | 07 Nodi da Ovest | 08 Nodi da Ovest |
| | Temperature | -08 °C | -07 °C | -08 °C |
| | Temp.percepita | -11 °C | -13 °C | -14 °C |
| Zero termico | | 1800-2000 m. | 1800-2000 m. | 1800-2000 m. |
| Fenomeno | | — | — | — |
| Stato del cielo | | | | |

## LEGENDA FENOMENI

— Assenza Fenomeni · Nebbia · Foschia · Pioggia debole · Pioggia moderata · Pioggia forte · Temporali

Nevicata debole · Nevicata moderata · Nevicata forte

## STATO DEL CIELO

Sereno · Poco nuvoloso · Nuvoloso · Molto nuvoloso · Coperto

## Parametri meteonivometrici registrati presso i campi di rilevamento il 09/02/2026.

| Località | Comune | Quota (m.s.l.m.) | Altezza neve (cm) | Neve caduta nelle 24 ore (cm) | Temp. Min (°C) | Temp. Max (°C) | Condizioni del tempo |
|---|---|---|---|---|---|---|---|
| QUARTARANA | Campo di Giove (AQ) | 1200 | 0 | 0 | -1 | +8 | Nebbia con cielo visibile |
| PASSOLANCIANO | Lettomanoppello (PE) | 1300 | 0 | 0 | 0 | +5 | Nebbia con cielo non visibile |
| VALICO DELLA FORCHETTA | Palena (CH) | 1270 | 0 | 0 | -1 | +5 | Assenza di precipitazioni |
| VALLE DEL SOLE | Pizzoferrato (CH) | 1440 | 1 | 1 | -1 | +8 | Nebbia con cielo non visibile |
| MAIELETTA MAMMA ROSA | Pretoro (CH) | 1650 | 19 | 2 | -3 | +4 | Nebbia con cielo non visibile |
| PASSO SAN LEONARDO | Sant'Eufemia a Maiella (PE) | 1145 | 0 | 0 | +1 | +10 | Assenza di precipitazioni |

**(*) Rilievi fuori campo**

**L'INFORMAZIONE E' PREVENZIONE - LEGGI L'ATTUALE GRADO DI PERICOLO VALANGHE!**

**IL CAPO DEL CENTRO NAZIONALE METEOMONT**
**(Ten. Col. RFI Emanuela Gini)**
**FIRMA AUTOGRAFA OMESSA AI SENSI**
**DELL'ART.3 DEL D.LGS N.39/1993**

**Bollettino realizzato su scala sinottica-regionale (standard EAWS). La sua valutazione non può escludere in alcun modo la necessità di una seria e capace valutazione locale del pericolo (singolo pendio) che può essere anche sensibilmente diverso. Le previsioni meteorologiche sono relative all'orario UTC (per l'Italia +1 in inverno e +2 in estate).**