MINISTERO DELLA DIFESA

meteomont
Servizio Nazionale di previsione neve e valanghe

EAWS EUROPEAN AVALANCHE WARNING SERVICES

CARABINIERI

AERONAUTICA MILITARE SERVIZIO METEOROLOGICO

MONTI SIMBRUINI E META

Bollettino Valanghe N. 275/2026 del 09/02/2026 ore 14.00
Validità 48 ore prossima emissione 10/02/2026

A cura del Servizio METEOMONT dell'ARMA dei CARABINIERI
In collaborazione con Servizio Meteorologico dell'Aeronautica militare

SITUAZIONE alle 14:00 del 09/02/2026

SITUAZIONE TIPO: neve pallottolare sepolta.

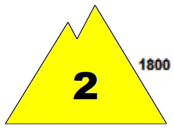



SITUAZIONE TIPO: pioggia su neve.

Quota neve (mslm)	Nord	Sud
	1500	1500 - 1600

Altezza Neve (cm)	Neve al suolo	Neve Fresca	Quota (mslm)
	082	003	1790
	030	005	1550

VALANGHE OSSERVATE: Nessuna valanga.

PREVISIONI 10/02/2026

GRADO DI PERICOLO: MODERATO 2

SITUAZIONE TIPO: neve pallottolare sepolta.

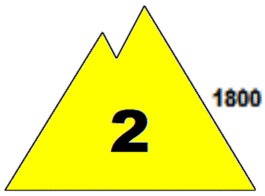



SITUAZIONE TIPO: pioggia su neve.

MANTO NEVOSO: La stabilità del manto nevoso è scarsa su molti punti (aree) per tutte le esposizioni al di sopra di 1800 mslm, possibili valanghe di dimensioni medie.
La stabilità del manto nevoso è scarsa su alcuni punti (aree) per tutte le esposizioni al di sotto di 1800 mslm, possibili valanghe di dimensioni medie.

AVVERTENZE

In considerazione dei recenti apporti di neve fresca, è richiesta una buona valutazione locale della stabilità ed individuazione dell'itinerario.

SCALA EUROPEA DEL GRADO DI PERICOLO VALANGHE

LEGENDA PROBLEMA

Bollettino realizzato su scala sinottica-regionale (standard EAWS). La sua valutazione non può escludere in alcun modo la necessità di una seria e capace valutazione locale del pericolo (singolo pendio) che può essere anche sensibilmente diverso. Le previsioni meteorologiche sono relative all'orario UTC (per l'Italia +1 in inverno e +2 in estate).

MONTI SIMBRUINI E META

PREVISIONE METEO

Quota		10/02/2026 h6:00	10/02/2026 h12:00	10/02/2026 h18:00
1000	Venti	01 Nodi da Ovest	02 Nodi da S-Ovest	02 Nodi da S-Ovest
	Temperature	+03 °C	+04 °C	+03 °C
	Temp.percepita	3 °C	4 °C	3 °C
2000	Venti	04 nodi da Ovest	06 Nodi da Ovest	04 Nodi da Ovest
	Temperature	-02 °C	-02 °C	-02 °C
	Temp.percepita	-5 °C	-6 °C	-5 °C
3000	Venti	05 Nodi da Ovest	08 Nodi da Ovest	09 Nodi da Ovest
	Temperature	-07 °C	-07 °C	-07 °C
	Temp.percepita	-11 °C	-13 °C	-13 °C
Zero termico		1600-1800 m.	1600-1800 m.	1700-1900 m.
Fenomeno		—		—
Stato del cielo				

LEGENDA FENOMENI

— Assenza Fenomeni · Nebbia · Foschia · Pioggia debole · Pioggia moderata · Pioggia forte · Temporali

Nevicata debole · Nevicata moderata · Nevicata forte

STATO DEL CIELO

Sereno · Poco nuvoloso · Nuvoloso · Molto nuvoloso · Coperto

Parametri meteonivometrici registrati presso i campi di rilevamento il 09/02/2026.

Località	Comune	Quota (m.s.l.m.)	Altezza neve (cm)	Neve caduta nelle 24 ore (cm)	Temp. Min (°C)	Temp. Max (°C)	Condizioni del tempo
PRATI DI MEZZO	Picinisco (FR)	1430	8	0	-1	+2	Assenza di precipitazioni
CAMPO DELL'OSSO	Subiaco (RM)	1550	30	5	0	+4	Assenza di precipitazioni
C.STAFFI	Filettino (FR)	1780	69	1	-2	+2	Assenza di precipitazioni
CAMPO CATINO	Guarcino (FR)	1790	82	3	-3	+1	Assenza di precipitazioni

(*) Rilievi fuori campo

L'INFORMAZIONE E' PREVENZIONE - LEGGI L'ATTUALE GRADO DI PERICOLO VALANGHE!

IL CAPO DEL CENTRO NAZIONALE METEOMONT
(Ten. Col. RFI Emanuela Gini)
FIRMA AUTOGRAFA OMESSA AI SENSI
DELL'ART.3 DEL D.LGS N.39/1993