Bulletin d'estimation du risque d'avalanche
(valable en dehors des pistes balisées et ouvertes)

MASSIF : Aure Louron

Rédigé le mardi 10 Février 2026 à 16h

Estimation des risques pour le : MERCREDI 11 FÉVRIER

HUMIDIFICATION EN PROFONDEUR

3

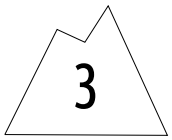

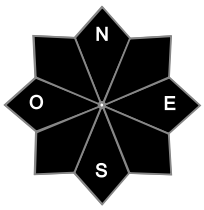

Humidification-pluie

Indice de risque marqué.

Départs spontanés : Quelques départs en neige humide, partant parfois du sol

Déclenchements provoqués : Plaques à vent au-dessus de 2500 m

Indices de risque : 5 très fort - 4 fort - 3 marqué - 2 limité - 1 faible -- En noir : les pentes les plus dangereuses

Stabilité du manteau neigeux

Situation avalancheuse typique : neige humide neige ventée

Départs spontanés : Quelques départs en neige humide sont encore attendus ce mercredi, en toutes orientations. Les avalanches sont souvent moyennes à grande, mais une rare grande reste possible, notamment dans les pentes les plus chargés, d'un large secteur Est et Nord. Elles partent généralement du sol, ou d'une couche fragile enfouit n'ayant pas encore été humidifié. Leur déclenchement est plus probable à partir du milieu de journée jusqu'en soirée avec l'arrivée d'un nouveau passage pluvieux.

Déclenchements provoqués :
* En toutes orientations, en pente raide et en dessous de 2500 m un skieur peut, par forte sollicitation, déclencher d'une avalanche en neige humide par l'ajout de son poids sur une neige déjà très lourde. Cette situation est plus probable l'après-midi avec la hausse de l'so 0°C.
* Des plaques à vent facilement déclenchables sont présentes ou en formation au-dessus de 2500 m, avec les chutes de neige ventée ce mercredi après-midi. Elles sont souvent de faible épaisseur. Risque limité à un large secteur Est, sous le vent d'Ouest.

Autres : Corniches souvent imposantes au-dessus des pentes d'un large secteur Est.

Qualité de la neige

Enneigement : Bon pour la saison, mais les crêtes, cols et sommets en expositions ouest sont souvent pelés. Poursuite d'une fonte importante mercredi après-midi.
Limites skiables : Manteau neigeux skiable à partir de 1400 m.
État de la neige : La surface du manteau neigeux est matelassée par les pluies. La neige est bien humidifiée et lourde jusqu'en profondeur sous 2000 m. Au-dessus, la surface est mole jusque vers 2300 m, elle est regelée au-dessus.

Aperçu météo pour le mercredi 11 février

	nuit	matin	après-midi	soir

Petite baisse temporaire de l'iso 0°C la nuit de mardi à mercredi et le matin, accompagné par de faible cumules, les plus importants étants l'après-midi.

Pluie-Neige	1 900 m		2 500 m	2 300 m
Iso 0 °C	2 300 m	2 200 m	2 900 m	2 700 m
Vent 1500 m	→ 60 km/h	→ 25 km/h	↗ 60 km/h	↗ 100 km/h
Vent 3000 m	→ 100 km/h	↘ 60 km/h	↘ 90 km/h	→ 120 km/h

Épaisseur de neige hors-piste

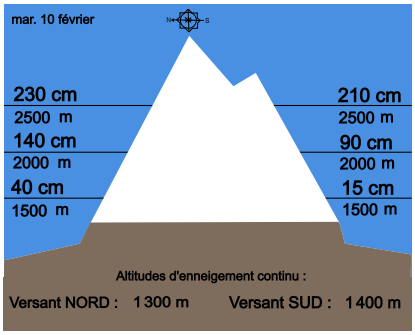

Précipitations à 1800 m

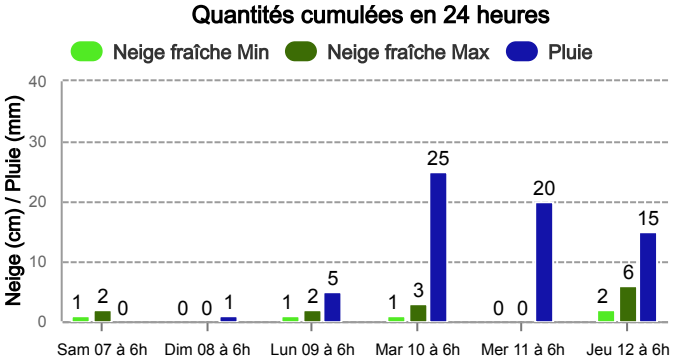

Tendance du jeudi 12 février

3

Indice de risque marqué

Retour des chutes de neige sur un manteau stable.

Pour consulter la vigilance en cours, veuillez vous rendre sur le site https://vigilance.meteofrance.fr/fr

Météo-France - 73 avenue de Paris, 94165 Saint-Mandé cedex - Contact : contact@meteo.fr

Rédigé par Météo-France avec la contribution des observateurs du réseau nivo-météorologiques. Partenariat : ANMSM (Maires de Stations de Montagne), DSF (Domaines Skiables de France), ADSP (Directeurs de Pistes et de la Sécurité des Stations de Sports d'Hiver) et autres acteurs de la montagne.

Bulletin neige & avalanches par téléphone au **0 892 68 10 20** Service 0,35 € / min + prix appel

Bulletin d'estimation du risque d'avalanche

(valable en dehors des pistes balisées et ouvertes)

MASSIF : Aure Louron

Rédigé le mardi 10 février 2026 à 16h

Conditions nivo-météo des 7 derniers jours

	mer. 04/02				jeu. 05/02				ven. 06/02				sam. 07/02				dim. 08/02				lun. 09/02				mar. 10/02			
	03h	09h	15h	21h	03h	09h	15h	21h	03h	09h	15h	21h	03h	09h	15h	21h	03h	09h	15h	21h	03h	09h	15h	21h	03h	09h	15h	21h
Météo																												
Vent (km/h)	95	100	60	55	75	110	95	70	60	60	60	50	40	35	35	45	50	35	50	40	45	50	55	80	75	90	100	100
à 3000m																												
Vent (km/h)	60	40	30	30	45	70	65	40	30	35	25	25	20	10	15	25	30	10	20	15	15	15	15	20	40	60	70	70
à 1500m																												

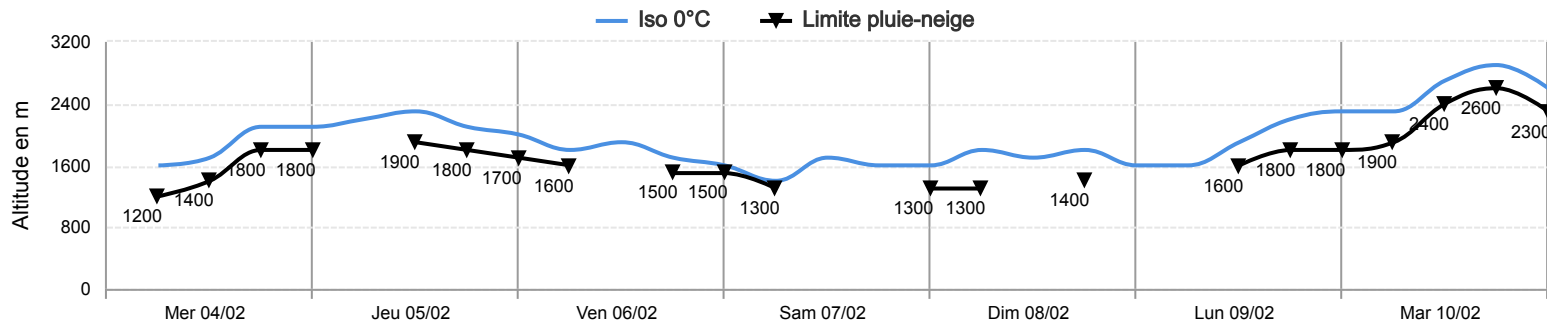

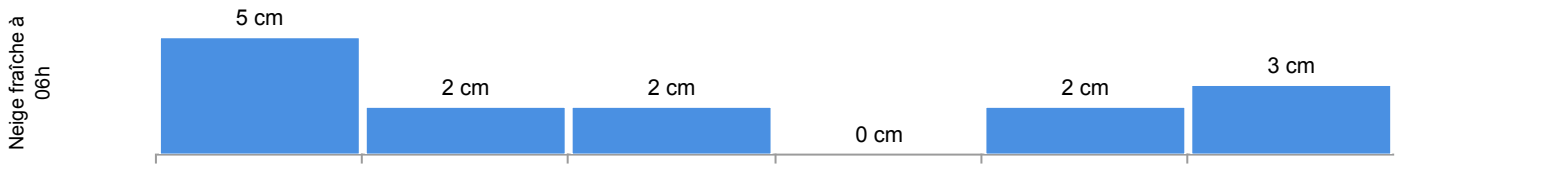

Risque d'avalanche	mer. 04/02	jeu. 05/02	ven. 06/02	sam. 07/02	dim. 08/02	lun. 09/02	mar. 10/02
	3	3	3	2	2	2	3

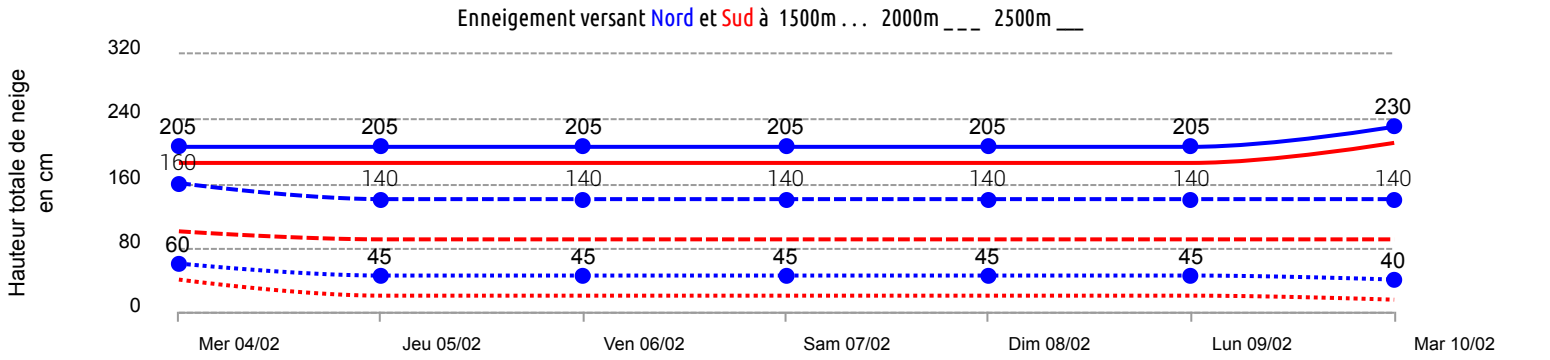

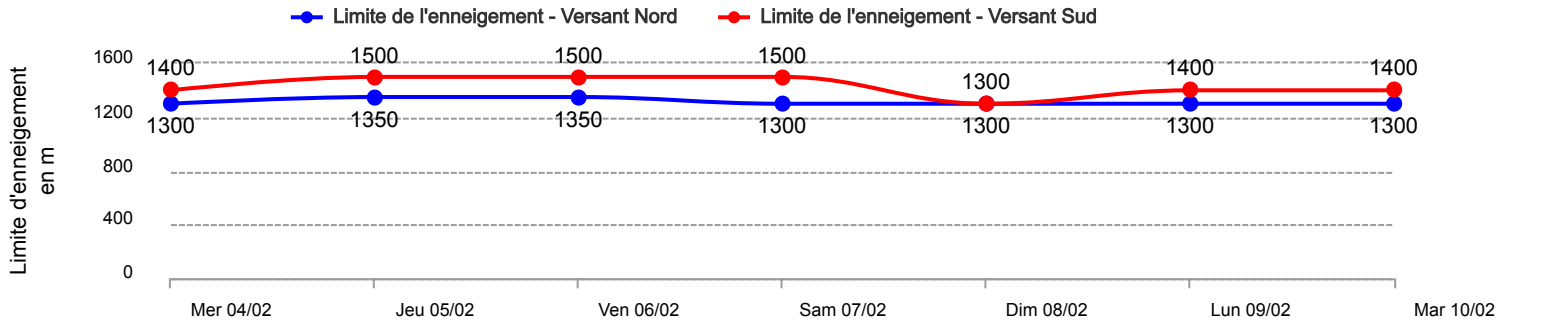

Pour consulter la vigilance en cours, veuillez vous rendre sur le site https://vigilance.meteofrance.fr/fr

Météo-France - 73 avenue de Paris, 94165 Saint-Mandé cedex - Contact : contact@meteo.fr

Rédigé par Météo-France avec la contribution des observateurs du réseau nivo-météorologiques. Partenariat : ANMSM (Maires de Stations de Montagne), DSF (Domaines Skiables de France), ADSP (Directeurs de Pistes et de la Sécurité des Stations de Sports d'Hiver) et autres acteurs de la montagne.

Bulletin neige & avalanches par téléphone au

0 892 68 10 20 Service 0,35 € / min + prix appel