Bulletin d'estimation du risque d'avalanche

(valable en dehors des pistes balisées et ouvertes)

MASSIF : Beaufortain

Rédigé le mardi 10 Février 2026 à 16h

Estimation des risques pour le : MERCREDI 11 FÉVRIER

FORTE ACTIVITÉ AVALANCHEUSE NATURELLE ET FORT RISQUE ACCIDENTEL.

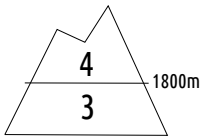

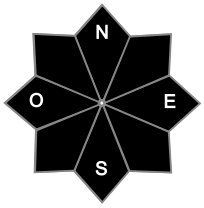

Au-dessus de 1800m indice de risque fort, plus bas indice marqué.

Départs spontanés : très nombreuses avalanches au fil de chutes.

Déclenchements provoqués : très nombreuses plaques dans la neige fraîche.

Indices de risque : 5 très fort - 4 fort - 3 marqué - 2 limité - 1 faible -- En noir : les pentes les plus dangereuses

Stabilité du manteau neigeux

Situation avalancheuse typique : neige fraîche neige humide

Dans la nuit de mardi à mercredi : le redoux pluvieux va engendrer des avalanches naturelles de neige humide sous 1800 m à l'Ouest du massif, sensiblement plus bas à l'Est (redoux moins marqué). En départ ponctuel (en poire) ou en plaque, les avalanches engendrées sont de taille 1 ou 2 (petite à moyenne). Avec l'abaissement de la limite pluie neige vers 1400 m en journée, le risque naturelle en neige humide diminue.

mercredi journée : nombreuses plaques dans la neige fraîche, en tous versants et au-delà de 1800m. Elles se déclenchement aussi bien naturellement qu'accidentellement, surtout à l'approche des crêtes où le vent d'Ouest transporte en continue la neige fraîchement tombée. Avec ~60 cm de neige fraîche attendue en moyenne en fin de journée, les avalanches sont souvent de taille 2, localement de taille 3 (grande) quand la topographie s'y prête.

Qualité de la neige

Enneigement : Un peu en dessous des normales de saison mais les chutes qui débutent ce mardi vont améliorer nettement l'enneigement au dessus de 1600m, en dessous la pluie attendue va bien dégrader le manteau.

Limite skiable : Les versants froids voyant pas ou peu le soleil ont gardé de la neige à basse altitude, skiable sur l'herbe ou sur pistes forestières dès 900/1000m. Sous bois skiables dès 1200m. En versant sud skiable dès 1300/1400m en prairies pas trop raides, 1600/1700m en Sud raide.

Qualité de la neige : en basse montagne, la neige est trempée, en moyenne montagne, la neige est humide jusqu'à ~1800 m. Plus haut, gros cumuls de neige fraîche avec bien 60 cm généralisés d'ici la fin de journée, localement plus. Le vent modéré engendre des grosses accumulations aux abords des crêtes; derrière les croupes.

Aperçu météo pour le mercredi 11 février

	nuit	matin	après-midi	soir
Journée très neigeuse. Eclaircies en fin de journée.				
Pluie-Neige	1 600 m	1 400 m	1 400 m	1 500 m
Iso 0 °C	2 000 m	1 800 m	1 900 m	2 000 m
Vent 2000 m	→ 40 km/h	→ 40 km/h	↘ 30 km/h	↘ 30 km/h
Vent 3000 m	→ 60 km/h	→ 55 km/h	→ 45 km/h	↘ 45 km/h

Épaisseur de neige hors-piste

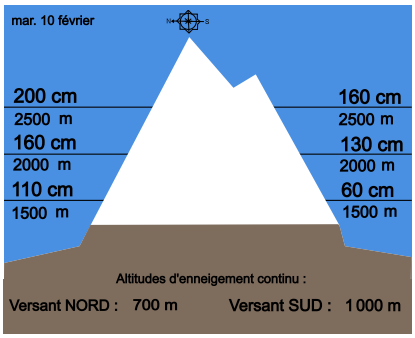

Précipitations à 1800 m

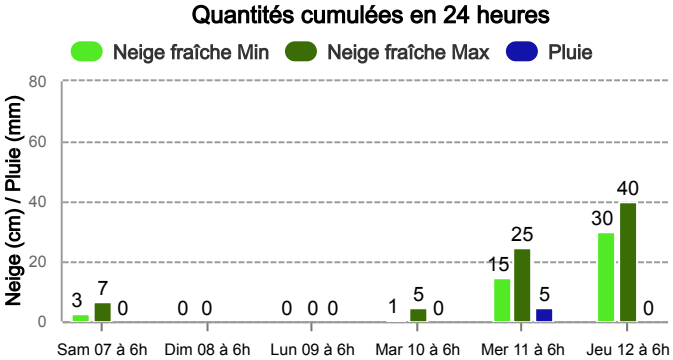

Tendance du jeudi 12 février

Indice de risque très fort

D'ici à jeudi soir, le Beaufortain pourrait recevoir entre 120 et 150 cm de neige fraîche. L'activité naturelle attendue en conséquence devient remarquable. Le risque maximal est envisagé pour la journée de jeudi.

Pour consulter la vigilance en cours, veuillez vous rendre sur le site https://vigilance.meteofrance.fr/fr

Météo-France - 73 avenue de Paris, 94165 Saint-Mandé cedex - Contact : contact@meteo.fr

Rédigé par Météo-France avec la contribution des observateurs du réseau nivo-météorologiques. Partenariat : ANMSM (Maires de Stations de Montagne), DSF (Domaines Skiables de France), ADSP (Directeurs de Pistes et de la Sécurité des Stations de Sports d'Hiver) et autres acteurs de la montagne.

Bulletin neige & avalanches par téléphone au **0 892 68 10 20** Service 0,35 € / min + prix appel

RÉPUBLIQUE FRANÇAISE
Liberté Égalité Fraternité

METEO FRANCE
À VOS CÔTÉS, DANS UN CLIMAT QUI CHANGE

Bulletin d'estimation du risque d'avalanche

(valable en dehors des pistes balisées et ouvertes)

MASSIF : Beaufortain

Rédigé le mardi 10 février 2026 à 16h

Conditions nivo-météo des 7 derniers jours

	mer. 04/02				jeu. 05/02				ven. 06/02				sam. 07/02				dim. 08/02				lun. 09/02				mar. 10/02			
	03h	09h	15h	21h	03h	09h	15h	21h	03h	09h	15h	21h	03h	09h	15h	21h	03h	09h	15h	21h	03h	09h	15h	21h	03h	09h	15h	21h
Météo																												
Vent (km/h)	60	30	20	20	30	25	25	30	40	35	25	20	15	10	5	5	15	20	20	20	20	15	20	25	30	35	45	55
à 3000m																												
Vent (km/h)	50	20	10	10	15	15	15	25	25	20	15	10	5	5	0	0	10	15	10	10	10	10	10	10	15	20	25	35
à 2000m																												

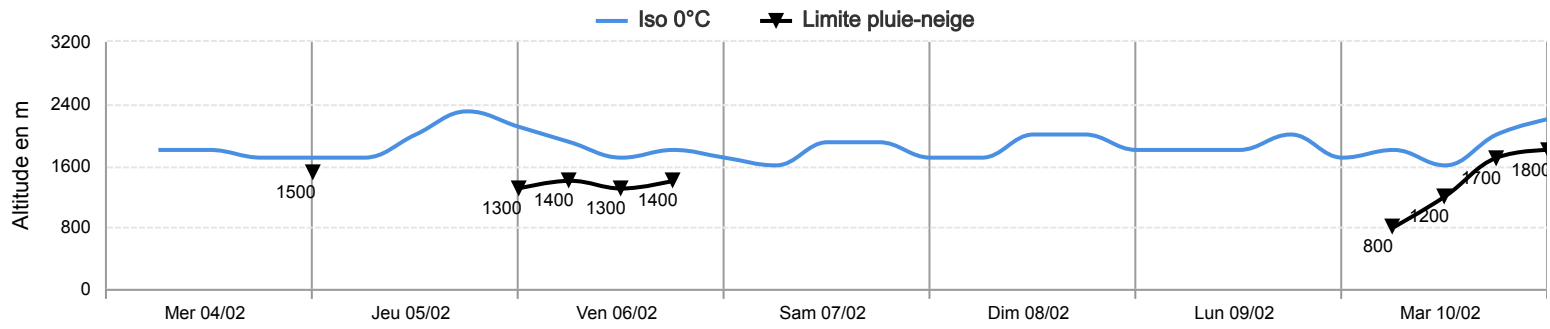

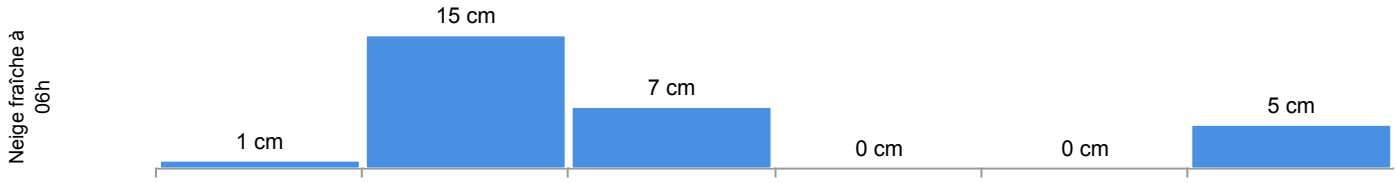

Risque d'avalanche	mer. 04/02	jeu. 05/02	ven. 06/02	sam. 07/02	dim. 08/02	lun. 09/02	mar. 10/02
	3	2	3	3	2	2	3

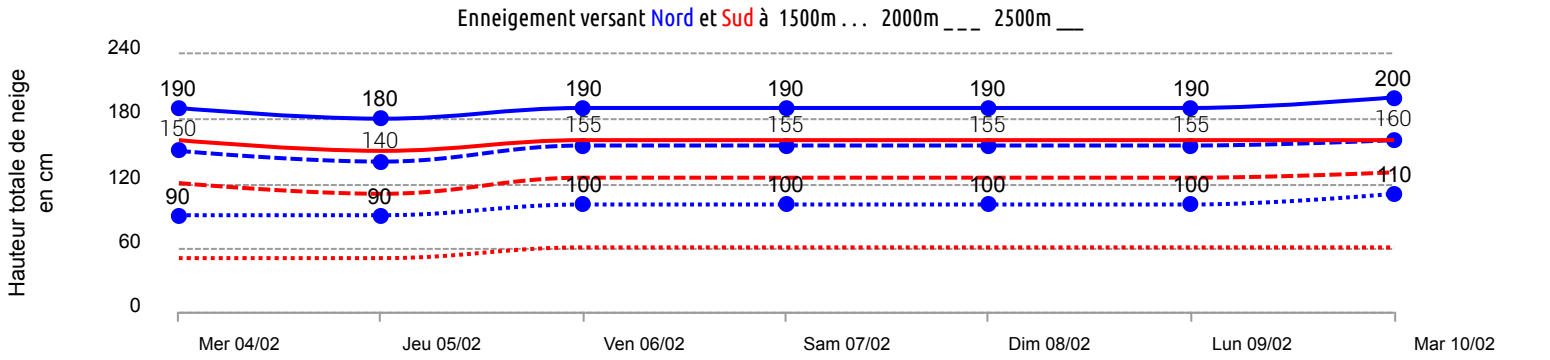

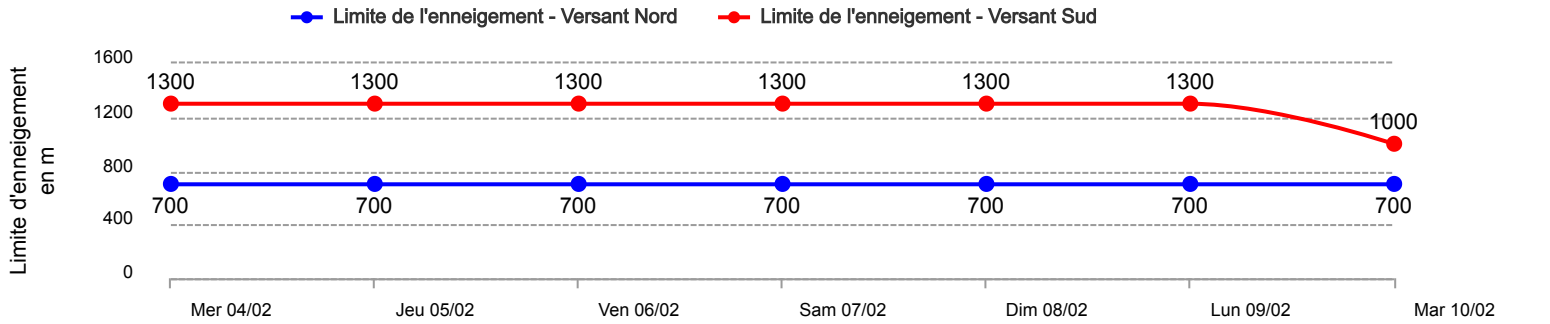

Pour consulter la vigilance en cours, veuillez vous rendre sur le site https://vigilance.meteofrance.fr/fr

Météo-France - 73 avenue de Paris, 94165 Saint-Mandé cedex - Contact : contact@meteo.fr

Rédigé par Météo-France avec la contribution des observateurs du réseau nivo-météorologiques. Partenariat : ANMSM (Maires de Stations de Montagne), DSF (Domaines Skiables de France), ADSP (Directeurs de Pistes et de la Sécurité des Stations de Sports d'Hiver) et autres acteurs de la montagne.

Bulletin neige & avalanches par téléphone au
0 892 68 10 20 Service 0,35 € / min + prix appel