Bulletin d'estimation du risque d'avalanche

(valable en dehors des pistes balisées et ouvertes)

MASSIF : Capcir Puymorens

Rédigé le mardi 10 Février 2026 à 16h

Estimation des risques pour le : MERCREDI 11 FÉVRIER

INSTABILITÉ GÉNÉRALISÉE EN NEIGE HUMIDE

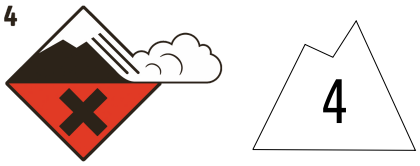

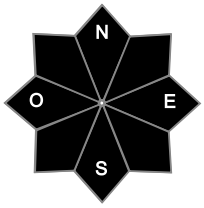

Indice de risque fort.

Départs spontanés : Nombreux en toutes expositions

Déclenchements provoqués : Structures de plaques présentes et en formation en haute montagne

Indices de risque : 5 très fort - 4 fort - 3 marqué - 2 limité - 1 faible -- En noir : les pentes les plus dangereuses

Stabilité du manteau neigeux

Situation avalancheuse typique : neige humide neige ventée

Départs spontanés :
Avec la douceur qui persiste et les pluies de la veille qui continuent à s'infiltrer dans le manteau neigeux, de nombreux départs spontanés parfois de grande taille (taille 3) se produiront en toutes orientations et à toute heure en dessous de 2300/2400m :
* Ils pourront mobiliser des volumes de neige importants avec l'humidification qui gagne en profondeur dans le manteau neigeux, notamment dans les pentes pas ou peu humidifiées avant ce lundi (au dessus de 2000m d'altitude, ainsi que dans un large secteur nord) (observables : neige meuble, "escargots").
* Des avalanches de glissement sur des pentes herbeuses/roches lisses pas encore humidifiées jusqu'au sol sont aussi à attendre (observables : large fissures, reptations).
Le risque se maintient dans la nuit de mercredi à jeudi avec de nouvelles précipitations attendues.

Déclenchements provoqués :
Plaques à vent facilement déclenchables présentes ou en formation en altitude, généralement de faible épaisseur. Risque limité à un large secteur Est au-dessus de 2400m. Avalanches de taille 1 à 2, rarement 3. (observables : affaissement soudain du manteau neigeux, fissures sous les skis, traces de transport de neige par le vent).

Autre :
Corniches fragilisées par l'humidification en dessous de 2400m.

Qualité de la neige

Enneigement :
Malgré un début de fonte, l'enneigement sur le massif est encore largement excédentaire. La limite de skiabilité se situe au plus bas vers 1300/1400 m dans les meilleures configurations et on peut skier confortablement dès 1500m

État de la neige :
La neige est bien humide voir 'pourrie' dès le matin en-dessous de 2000m avec un regel nocturne peu efficace. Au dessus de 2400m, on trouvera de la neige fraiche en quantité hétérogène souvent bien travaillée par le vent d'ouest. En journée, l'humidification gagnera en profondeur en dessous de 2000m. La neige fraiche de la nuit présente en altitude s'humidifiera aussi dans la couche nuageuse ou sous les éclaircies en journée.

Aperçu météo pour le mercredi 11 février

	nuit	matin	après-midi	soir
Temps doux et humide				
Pluie-Neige	2 200 m		2 200 m	2 300 m
Iso 0 °C	2 600 m	2 400 m	2 800 m	2 800 m
Vent 2000 m	→ 50 km/h	↘ 50 km/h	→ 35 km/h	→ 45 km/h
Vent 3000 m	→ 65 km/h	↘ 55 km/h	→ 45 km/h	↗ 65 km/h

Épaisseur de neige hors-piste

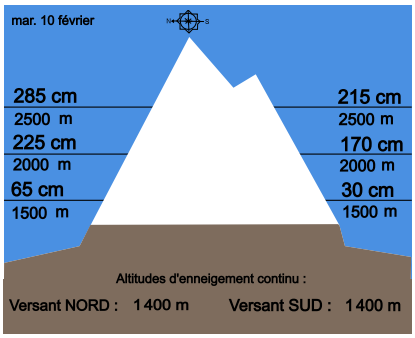

Précipitations à 1800 m

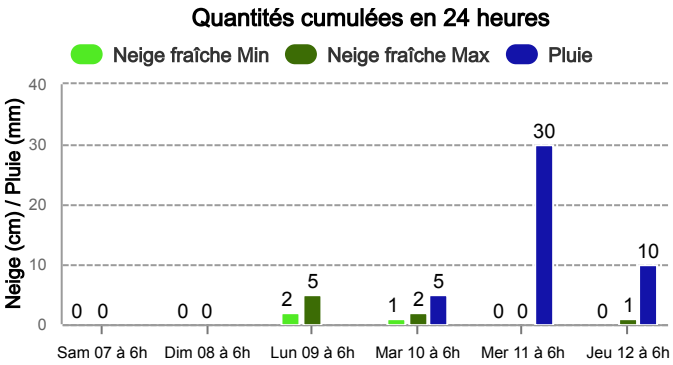

Tendance du jeudi 12 février

Indice de risque marqué

Risque naturel en baisse avec le refroidissement, maintien du risque accidentel en altitude avec de nouvelles chutes ventées.

Pour consulter la vigilance en cours, veuillez vous rendre sur le site https://vigilance.meteofrance.fr/fr

Météo-France - 73 avenue de Paris, 94165 Saint-Mandé cedex - Contact : contact@meteo.fr

Rédigé par Météo-France avec la contribution des observateurs du réseau nivo-météorologiques. Partenariat : ANMSM (Maires de Stations de Montagne), DSF (Domaines Skiables de France), ADSP (Directeurs de Pistes et de la Sécurité des Stations de Sports d'Hiver) et autres acteurs de la montagne.

Bulletin neige & avalanches par téléphone au **0 892 68 10 20** Service 0,35 € / min + prix appel

RÉPUBLIQUE FRANÇAISE
Liberté Égalité Fraternité

METEO FRANCE
À VOS CÔTÉS, DANS UN CLIMAT QUI CHANGE

Bulletin d'estimation du risque d'avalanche

(valable en dehors des pistes balisées et ouvertes)

MASSIF : Capcir Puymorens

Rédigé le mardi 10 février 2026 à 16h

Conditions nivo-météo des 7 derniers jours

	mer. 04/02				jeu. 05/02				ven. 06/02				sam. 07/02				dim. 08/02				lun. 09/02				mar. 10/02			
	03h	09h	15h	21h	03h	09h	15h	21h	03h	09h	15h	21h	03h	09h	15h	21h	03h	09h	15h	21h	03h	09h	15h	21h	03h	09h	15h	21h
Météo																												
Vent (km/h)	40	55	50	40	65	80	75	55	40	25	25	30	30	20	20	50	55	30	55	50	55	40	60	65	70	70	80	85
à 3000m																												
Vent (km/h)	30	45	35	30	45	60	55	40	25	15	15	20	20	15	15	40	45	20	35	35	35	20	30	35	35	40	50	60
à 2000m																												

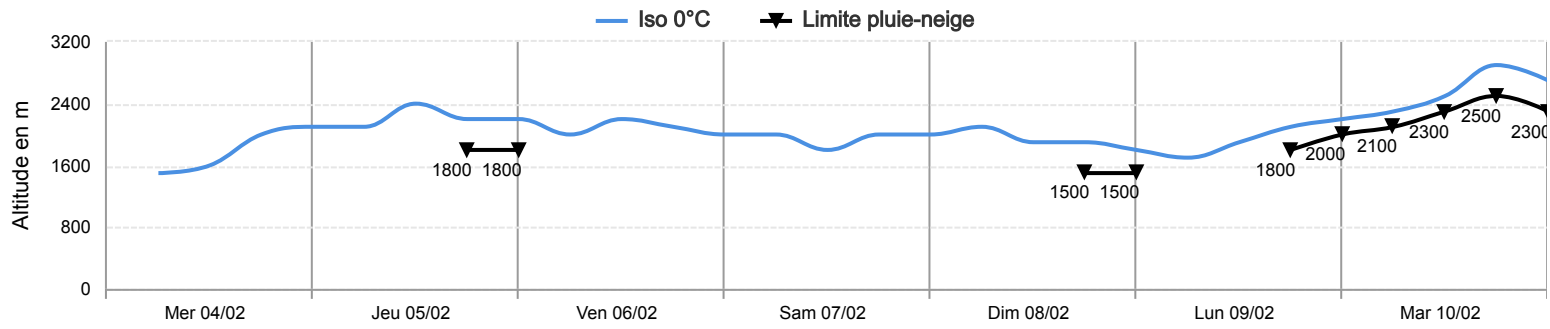

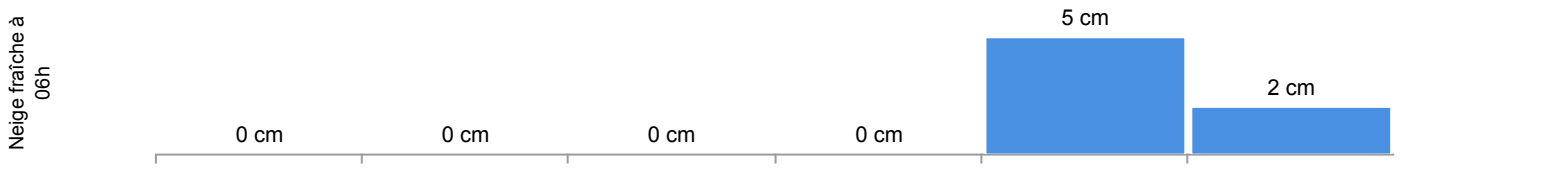

Risque d'avalanche	mer. 04/02	jeu. 05/02	ven. 06/02	sam. 07/02	dim. 08/02	lun. 09/02	mar. 10/02
	3	3	2	2	2	2	4

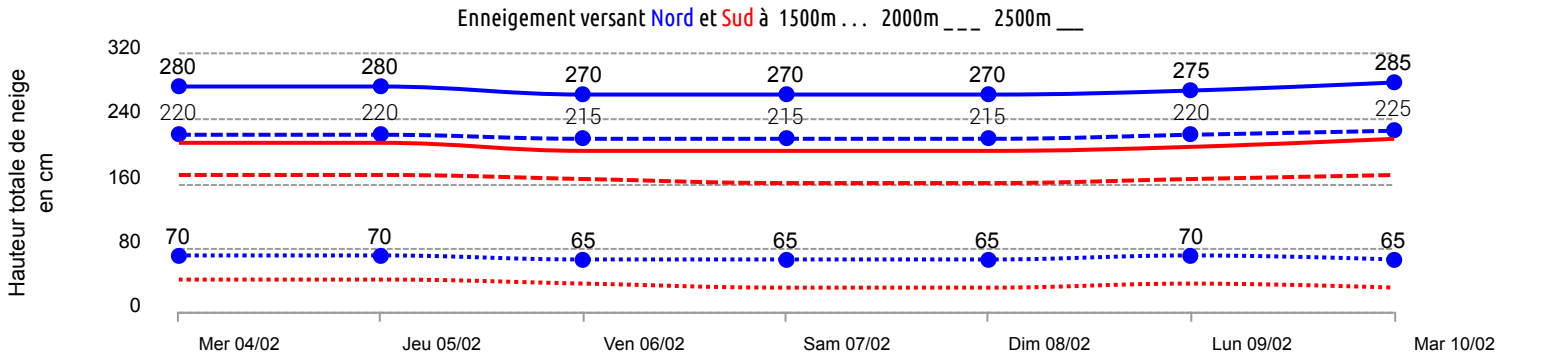

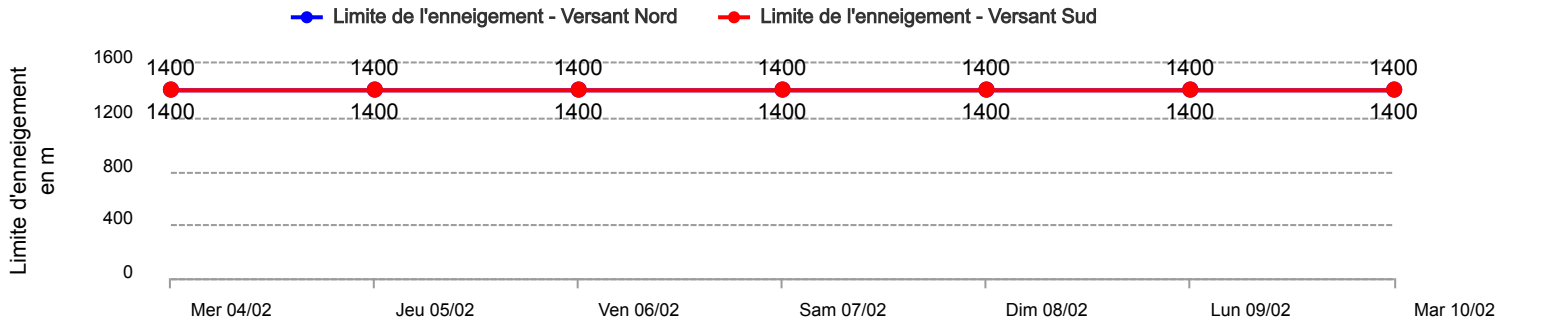

Pour consulter la vigilance en cours, veuillez vous rendre sur le site https://vigilance.meteofrance.fr/fr

Météo-France - 73 avenue de Paris, 94165 Saint-Mandé cedex - Contact : contact@meteo.fr

Rédigé par Météo-France avec la contribution des observateurs du réseau nivo-météorologiques. Partenariat : ANMSM (Maires de Stations de Montagne), DSF (Domaines Skiables de France), ADSP (Directeurs de Pistes et de la Sécurité des Stations de Sports d'Hiver) et autres acteurs de la montagne.

Bulletin neige & avalanches par téléphone au
0 892 68 10 20 Service 0,35 € / min + prix appel