Bulletin d'estimation du risque d'avalanche

(valable en dehors des pistes balisées et ouvertes)

MASSIF : Cerdagne Canigou

Rédigé le mardi 10 Février 2026 à 16h

Estimation des risques pour le : MERCREDI 11 FÉVRIER

HUMIDIFICATION QUI GAGNE EN PROFONDEUR ET PLAQUES EN ALTITUDE

3

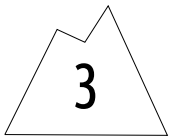

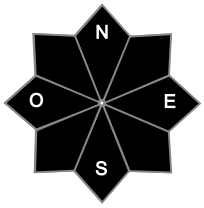

Indice de risque marqué.

Départs spontanés : Avalanches en neige humide

Déclenchements provoqués : Plaques à vent présentes et en formation en altitude

Indices de risque : 5 très fort - 4 fort - 3 marqué - 2 limité - 1 faible -- En noir : les pentes les plus dangereuses

Stabilité du manteau neigeux

Situation avalancheuse typique : neige humide neige ventée

Départs spontanés :

* Avalanches de glissement possibles en pentes raides herbeuses ou sur des dalles rocheuses en toutes orientations en dessous de 2200m principalement (Taille 1 ou 2, rarement 3). (observables : présence de gueules de baleine, reptations, neige dense et très humide).
* Départs ponctuels en surface (tailles1 à 2) en neige humide à la faveur des éclaircies.

Le risque se maintient la nuit de mercredi à jeudi avec de nouvelles précipitations d'abord sous forme de pluie en dessous de 2200m.

Déclenchements provoqués :

* Au-dessus de 2400 m, dans un large secteur Est, déclenchements possibles au passage d'un randonneur d'avalanches de taille moyenne (T2), voire de grande taille (T3) dans les secteurs les plus défavorables. En effet, des structures de plaques sont en place et continuent de se former avec le fort vent d'ouest.

Autre :

Corniches fragilisées par l'humidification en dessous de 2400m.

Qualité de la neige

Enneigement :

Malgré un début de fonte à basse altitude, l'enneigement est excellent et très largement excédentaire pour la saison sur le massif. La limite de skiabilité se situe vers 1300/1400 m dans les meilleures configurations.

État de la neige :

Au petit matin, neige déjà humide et peu portante à cause d'un mauvais regel nocturne. Poursuite de l'humidification ensuite au fil des éclaircies.

Aperçu météo pour le mercredi 11 février

	nuit	matin	après-midi	soir
Persistance d'une grande douceur.				
Pluie-Neige	2 200 m		2 200 m	2 400 m
Iso 0 °C	2 700 m	2 600 m	2 900 m	2 900 m
Vent 2000 m	45 km/h	45 km/h	35 km/h	50 km/h
Vent 3000 m	75 km/h	75 km/h	60 km/h	70 km/h

Épaisseur de neige hors-piste

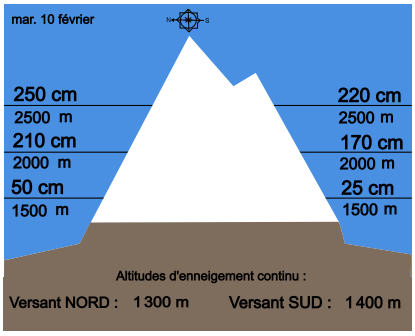

Précipitations à 1800 m

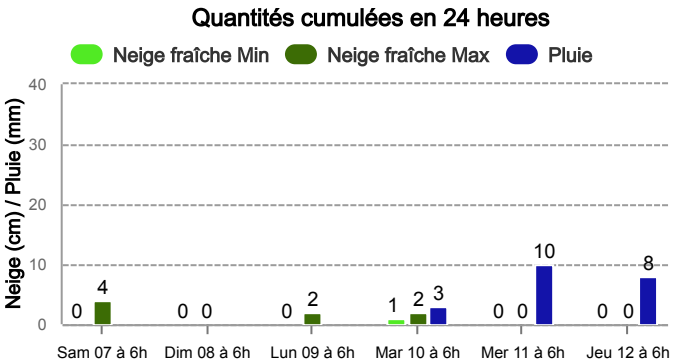

Tendance du jeudi 12 février

3

Indice de risque marqué

Risque naturel en baisse avec le refroidissement, maintien du risque accidentel en altitude avec de nouvelles chutes ventées.

Pour consulter la vigilance en cours, veuillez vous rendre sur le site https://vigilance.meteofrance.fr/fr

Météo-France - 73 avenue de Paris, 94165 Saint-Mandé cedex - Contact : contact@meteo.fr

Rédigé par Météo-France avec la contribution des observateurs du réseau nivo-météorologiques. Partenariat : ANMSM (Maires de Stations de Montagne), DSF (Domaines Skiables de France), ADSP (Directeurs de Pistes et de la Sécurité des Stations de Sports d'Hiver) et autres acteurs de la montagne.

Bulletin neige & avalanches par téléphone au

0 892 68 10 20 Service 0,35 € / min + prix appel

RÉPUBLIQUE FRANÇAISE
Liberté Égalité Fraternité

METEO FRANCE
À VOS CÔTÉS, DANS UN CLIMAT QUI CHANGE

Bulletin d'estimation du risque d'avalanche

(valable en dehors des pistes balisées et ouvertes)

MASSIF : Cerdagne Canigou

Rédigé le mardi 10 février 2026 à 16h

Conditions nivo-météo des 7 derniers jours

	mer. 04/02				jeu. 05/02				ven. 06/02				sam. 07/02				dim. 08/02				lun. 09/02				mar. 10/02			
	03h	09h	15h	21h	03h	09h	15h	21h	03h	09h	15h	21h	03h	09h	15h	21h	03h	09h	15h	21h	03h	09h	15h	21h	03h	09h	15h	21h
Météo																												
Vent (km/h)	50	75	40	35	65	80	75	55	40	25	25	30	30	20	25	50	55	50	50	40	50	35	55	45	50	50	55	60
à 3000m																												
Vent (km/h)	25	45	25	25	45	60	55	40	25	15	15	20	20	15	15	40	45	40	35	25	30	20	25	20	30	30	30	40
à 2000m																												

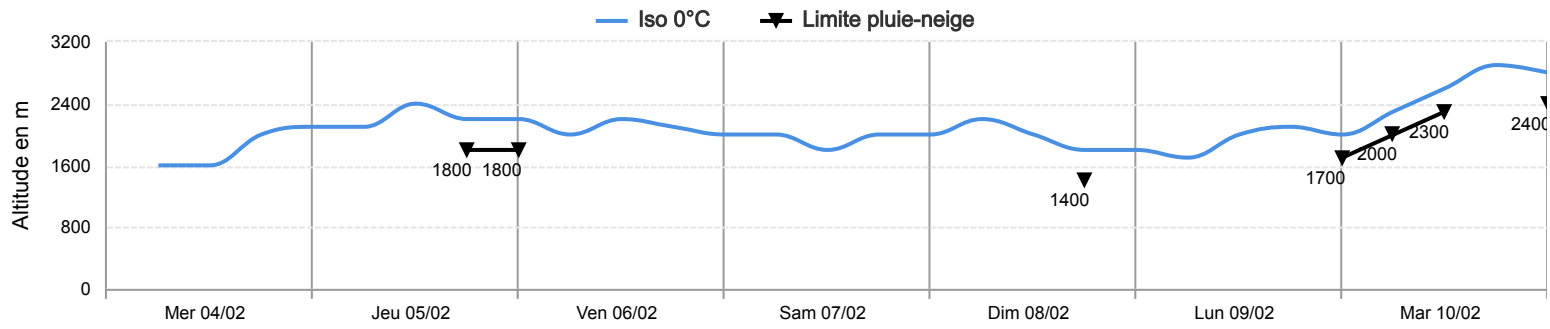

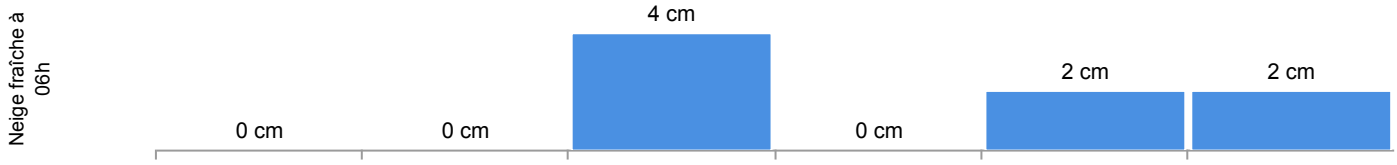

Risque d'avalanche	mer. 04/02	jeu. 05/02	ven. 06/02	sam. 07/02	dim. 08/02	lun. 09/02	mar. 10/02
	3	2	2	2	2	2	2

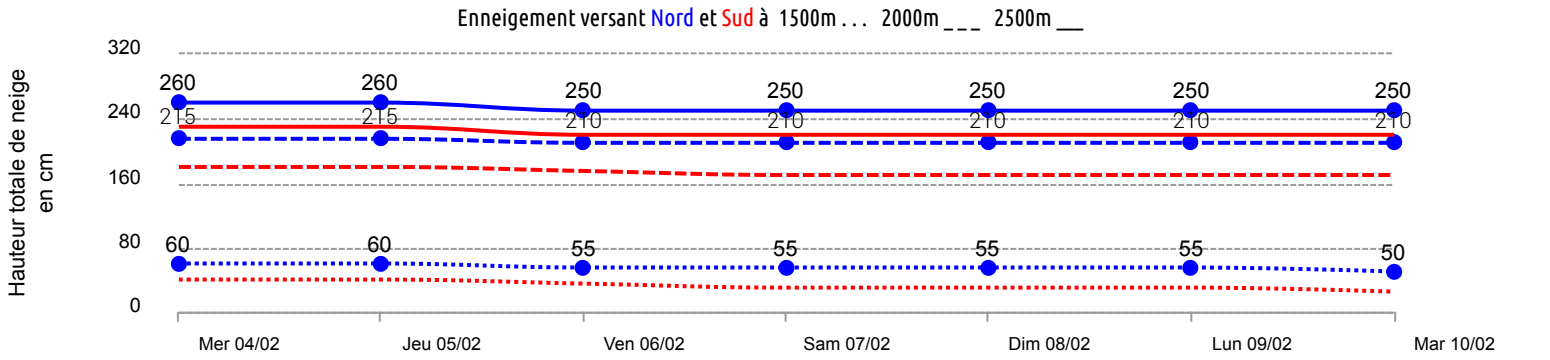

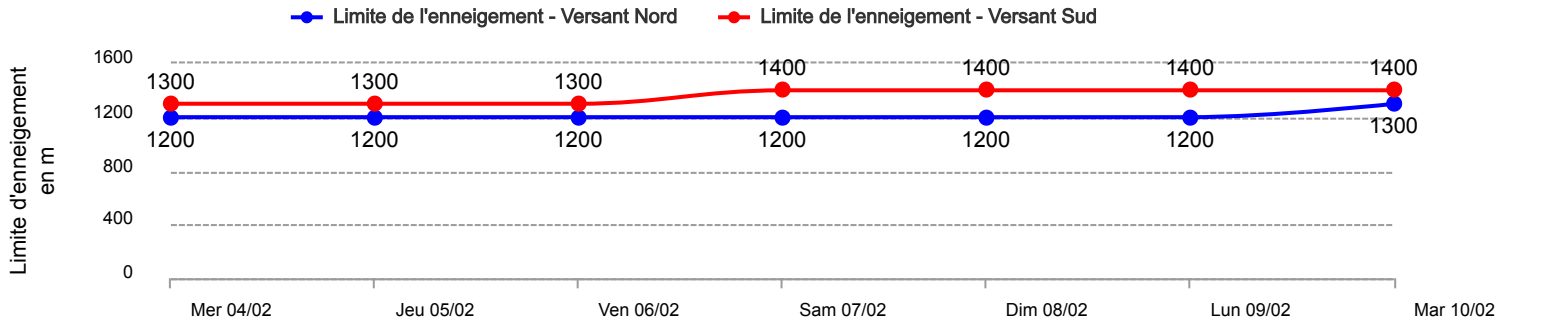

Pour consulter la vigilance en cours, veuillez vous rendre sur le site https://vigilance.meteofrance.fr/fr

Météo-France - 73 avenue de Paris, 94165 Saint-Mandé cedex - Contact : contact@meteo.fr

Bulletin neige & avalanches par téléphone au

0 892 68 10 20 Service 0,35 € / min + prix appel

Rédigé par Météo-France avec la contribution des observateurs du réseau nivo-météorologiques. Partenariat : ANMSM (Maires de Stations de Montagne), DSF (Domaines Skiables de France), ADSP (Directeurs de Pistes et de la Sécurité des Stations de Sports d'Hiver) et autres acteurs de la montagne.