Bulletin d'estimation du risque d'avalanche

(valable en dehors des pistes balisées et ouvertes)

MASSIF : Ubaye

Rédigé le mardi 10 Février 2026 à 16h

Estimation des risques pour le : MERCREDI 11 FÉVRIER

NOMBREUSES PLAQUES EN FORMATION DANS LA NEIGE FRAÎCHE, INSTABILITÉS ENFOUIES VOLUMINEUSES

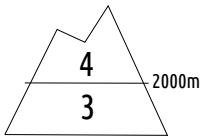

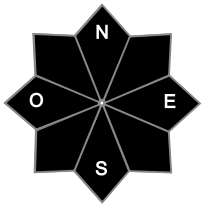

Au-dessus de 2000m indice de risque fort, plus bas indice marqué.

Départs spontanés : en neige fraîche, pendant les chutes ou ensuite par transport par le vent.

Déclenchements provoqués : nombreuses nouvelles plaques en formation dans la neige ventée, et instabilités enfouies encore actives.

Indices de risque : 5 très fort - 4 fort - 3 marqué - 2 limité - 1 faible -- En noir : les pentes les plus dangereuses

Stabilité du manteau neigeux

Situation avalancheuse typique : couche fragile persistante — neige fraîche

Déclenchements provoqués :

- Le manteau neigeux reste peu stabilisé dans de nombreuses pentes au-dessus de 2000 m environ, dans les orientations ouest, nord et est. Des instabilités liées à la présence de couches fragiles persistantes sont toujours en place, et restent facilement déclenchables par un skieur, même à distance, ainsi qu'en cas de premier départ en surface. Elles sont difficilement identifiables, car enfouies dans le manteau neigeux. Elles peuvent engendrer des avalanches de grande taille, avec des cassures parfois larges et épaisses, emportant la totalité du manteau neigeux.

- Nombreuses nouvelles plaques en formation pendant les chutes de neige ventée, ou en journée par transport de neige par le vent de nord-ouest. D'aspect souvent durci par le vent, ces nouvelles instabilités sont possibles en toutes orientations, surtout au dessus de 2000 m, même loin des crêtes et ruptures de pentes, mais plus nombreuses dans les pentes d'un large secteur est, où le vent de nord-ouest forme de plus importantes accumulations. Elles sont faciles à déclencher, sous forme de rupture linéaire, et peuvent provoquer des avalanches de taille petite à moyenne (1 à 2), parfois grande (3) dans les zones d'importantes accumulations, plutôt sur l'ouest du massif.

- Sous 2000 m, le risque est modéré, avec principalement une problématique de nouvelles plaques dans la neige fraîche, présentes en toutes orientations, parfois encore friables dans les secteurs moins exposés au vent. Elles sont un peu plus difficiles à déclencher avec une neige fraîche souvent plus lourde, et restent généralement de taille petite à moyenne.

Départs spontanés : avalanches de neige fraîche pendant les chutes. Départs ponctuels ou parfois linéaires de taille petite à moyenne en pentes raides. Des départs linéaires sont possibles après l'arrêt des chutes par surcharge du manteau neigeux avec le transport de neige par le vent de nord-ouest. Localement une rare grande taille est possible, en versants ouest, nord et est au dessus de 2000 m, si la surcharge liée à la neige fraîche provoque la rupture d'une couche fragile enfouie.

Qualité de la neige

Enneigement bon, voire excédentaire pour un début février.
Données observées : 100 cm au-dessus de Larche à 2270 m, 11 cm à Barcelonnette à 1200 m.

Enneigement skiable dès 1300/1400 m en terrain favorable, mais peu de sous-couche sous 1600 m en général.

État de la neige en surface : mercredi, la neige fraîche est froide et légère au dessus de 2000 m environ, plus lourde en dessous. Elle est souvent densifiée par le vent. Elle repose sur de la neige récente restée encore poudreuse sur 20/30 cm, localement déjà densifiée par le vent . Corniches et congères parfois volumineuses en place.

Aperçu météo pour le mercredi 11 février

Chutes de neige conséquentes dans la nuit, faiblissant en cours de journée. Fort vent de nord-ouest en altitude.

	nuit	matin	après-midi	soir
Pluie-Neige	1 600 m	1 500 m	1 700 m	1 400 m
Iso 0 °C	2 000 m	2 000 m	2 200 m	1 900 m
Vent 2000 m	25 km/h	35 km/h	30 km/h	25 km/h
Vent 3000 m	80 km/h	70 km/h	55 km/h	70 km/h

Épaisseur de neige hors-piste

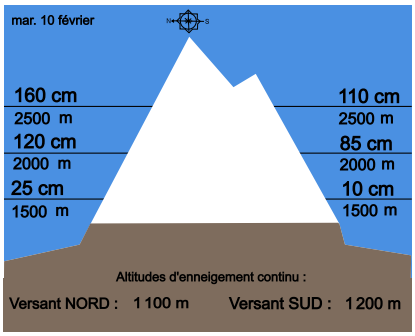

Précipitations à 1800 m

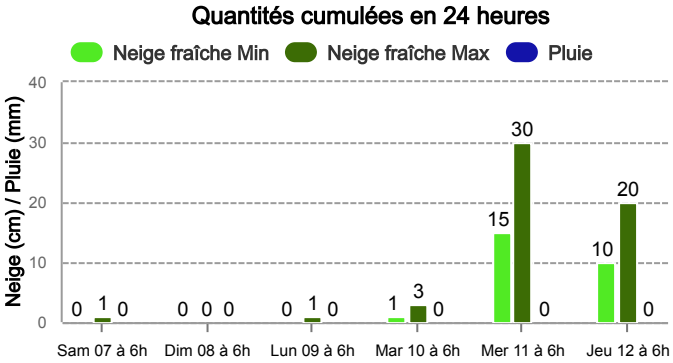

Tendance du jeudi 12 février

Indice de risque fort

Maintient d'un risque fort avec de nouvelles chutes de neige prévues dans la nuit de mercredi à jeudi. Le vent de nord-ouest se renforce à nouveau et souffle toute la journée.

Pour consulter la vigilance en cours, veuillez vous rendre sur le site https://vigilance.meteofrance.fr/fr

Météo-France - 73 avenue de Paris, 94165 Saint-Mandé cedex - Contact : contact@meteo.fr

Rédigé par Météo-France avec la contribution des observateurs du réseau nivo-météorologiques. Partenariat : ANMSM (Maires de Stations de Montagne), DSF (Domaines Skiables de France), ADSP (Directeurs de Pistes et de la Sécurité des Stations de Sports d'Hiver) et autres acteurs de la montagne.

Bulletin neige & avalanches par téléphone au **0 892 68 10 20** Service 0,35 € / min + prix appel

RÉPUBLIQUE FRANÇAISE
Liberté Égalité Fraternité

METEO FRANCE
À VOS CÔTÉS, DANS UN CLIMAT QUI CHANGE

Bulletin d'estimation du risque d'avalanche

(valable en dehors des pistes balisées et ouvertes)

MASSIF : Ubaye

Rédigé le mardi 10 février 2026 à 16h

Conditions nivo-météo des 7 derniers jours

	mer. 04/02				jeu. 05/02				ven. 06/02				sam. 07/02				dim. 08/02				lun. 09/02				mar. 10/02			
	03h	09h	15h	21h	03h	09h	15h	21h	03h	09h	15h	21h	03h	09h	15h	21h	03h	09h	15h	21h	03h	09h	15h	21h	03h	09h	15h	21h
Météo																												
Vent (km/h)	25	25	20	20	25	30	40	40	30	35	35	25	30	15	15	10	10	25	25	15	15	25	25	30	30	35	45	65
à 3000m																												
Vent (km/h)	20	20	20	10	10	15	25	25	20	20	25	10	10	10	10	10	10	15	20	15	10	10	15	10	10	15	20	20
à 2000m																												

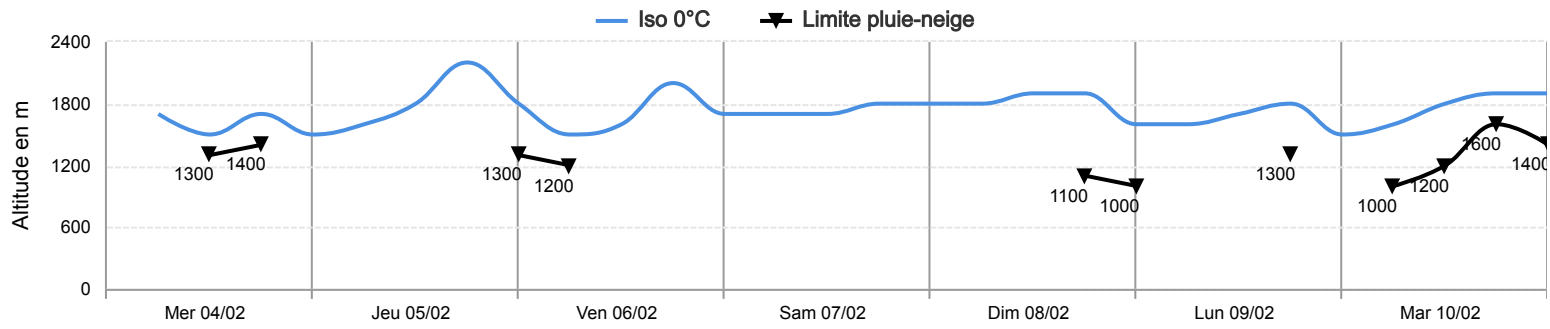

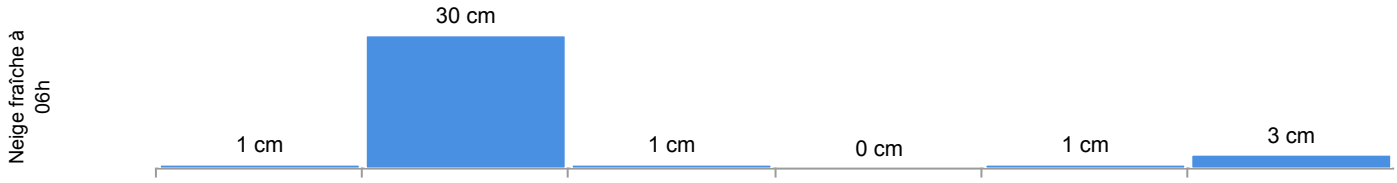

Risque d'avalanche	mer. 04/02	jeu. 05/02	ven. 06/02	sam. 07/02	dim. 08/02	lun. 09/02	mar. 10/02
	4	3	4	4	3	3	3

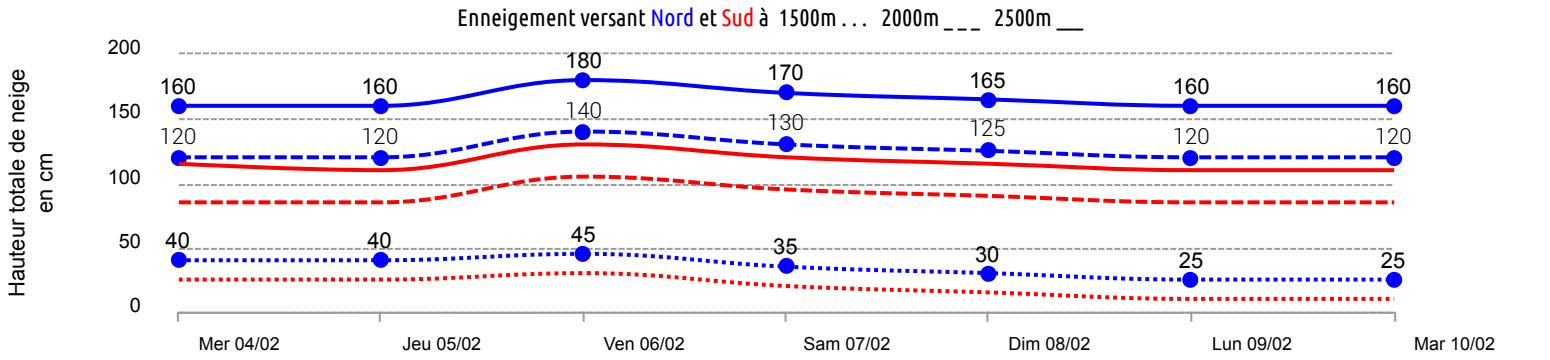

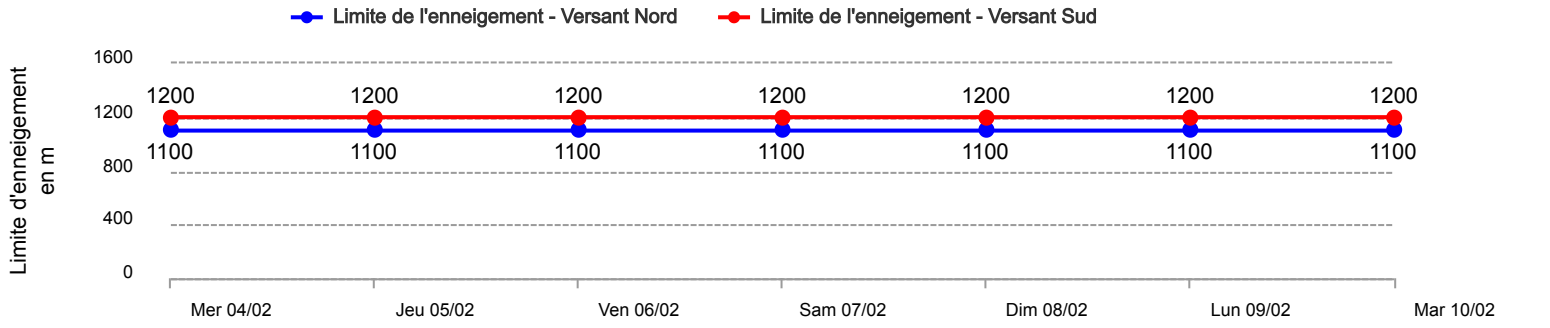

Pour consulter la vigilance en cours, veuillez vous rendre sur le site https://vigilance.meteofrance.fr/fr

Météo-France - 73 avenue de Paris, 94165 Saint-Mandé cedex - Contact : contact@meteo.fr

Rédigé par Météo-France avec la contribution des observateurs du réseau nivo-météorologiques. Partenariat : ANMSM (Maires de Stations de Montagne), DSF (Domaines Skiables de France), ADSP (Directeurs de Pistes et de la Sécurité des Stations de Sports d'Hiver) et autres acteurs de la montagne.

Bulletin neige & avalanches par téléphone au
0 892 68 10 20 Service 0,35 € / min + prix appel