Bulletin d'estimation du risque d'avalanche
(valable en dehors des pistes balisées et ouvertes)

MASSIF : Vercors

Rédigé le mardi 10 Février 2026 à 16h

Estimation des risques pour le : MERCREDI 11 FÉVRIER

NOMBREUX DEPARTS SOUS LA PLUIE, INSTABILITES SOMMITALES EN NEIGE FRAICHE

3

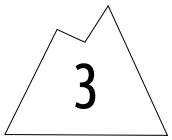

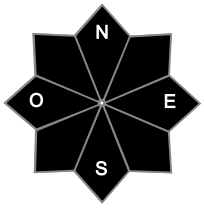

Indice de risque marqué.

Départs spontanés : Nombreuses purges avec l'humidification du manteau neigeux. Départs dans la neige récente en altitude, surtout dans les versants Est.

Déclenchements provoqués : Formation de plaques sur le haut du massif dans la neige fraîche / ventée.

Indices de risque : 5 très fort - 4 fort - 3 marqué - 2 limité - 1 faible -- En noir : les pentes les plus dangereuses

Stabilité du manteau neigeux

Situation avalancheuse typique : neige humide neige fraîche

Sous la pluie, de rares coulées de neige humide peuvent atteindre des routes, notamment sous les talus.

Mardi soir des pluies soutenues gagnent l'ensemble du massif avec une limite pluie-neige remontant vers 2000m. La neige s'abaisse à nouveau vers 1800 puis 1500m mercredi matin.

Départs spontanés : L'enneigement est encore correct sur le massif, et la pluie va fortement humidifier le manteau neigeux, faisant partir de nombreuses avalanches entre mardi soir et mercredi midi. Elles seront plus nombreuses dans les secteurs abrités du soleil, où la neige est restée froide ces derniers jours, tandis que les versants ensoleillés ont souvent déjà été purgés. Quelques avalanches de fond de petites tailles peuvent glisser sur les talus et atteindre les routes.

Au-dessus de 1500/1600m environ, quelques départs sont possibles en deuxième partie de nuit et en matinée de mercredi dans la neige fraîche. Sous le vent d'Ouest, le risque sera un peu plus marqué dans les pentes de la barrière orientale du Vercors.

Déclenchements provoqués : La neige s'abaisse à nouveau en cours de matinée sous 1800m puis 1500m, sous un vent de Nord-Ouest soutenu en altitude. Sur le haut du massif on peut attendre localement 20-30cm de neige. Cette couche de neige fraîche est peu stabilisée, avec des plaques généralement peu larges mais souvent très réactives. Elles sont difficiles à identifier, d'aspect poudreuse plus ou moins densifié par le vent. Les chutes de neige faiblissent l'après-midi mais le vent d'Ouest reste sensible et forme de nouvelles plaques l'après-midi.

Qualité de la neige

Qualification de l'enneigement : L'enneigement s'est récemment dégradé aux basses altitudes, sous les sapins mais reste correct pour la saison dès la moyenne montagne et dans les combes Nord.

Limites skiables : Vers 1100/1400 m, sur les pistes forestières/clairières...

Qualité de la neige mercredi : La pluie remonte jusqu'à 2000m mardi soir. Neige devenant pourrie sur le bas du massif. Mercredi matin la neige s'abaisse à nouveau vers 1800m puis 1500m. Neige souvent humide sous 1700m, plus froide au-dessus où elle est souvent densifiée par le vent. Sous couche humide non regelée.

Aperçu météo pour le mercredi 11 février

	nuit	matin	après-midi	soir

Fortes chutes de neige au-dessus de 1800 puis 1500m en matinée, sous un vent d'Ouest fort. Plus calme l'après-midi.

Pluie-Neige	1 800 m	1 600 m	1 700 m	1 800 m
Iso 0 °C	2 300 m	1 800 m	1 900 m	2 200 m
Vent 1500 m	→ 60 km/h	↗ 30 km/h	↗ 30 km/h	↑ 55 km/h
Vent 2000 m	→ 80 km/h	→ 65 km/h	→ 55 km/h	↗ 75 km/h

Épaisseur de neige hors-piste

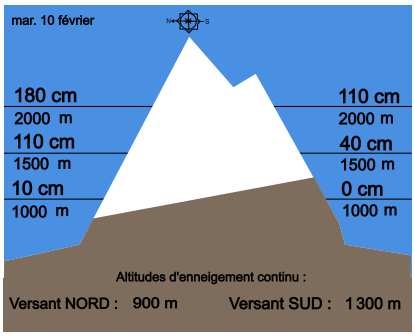

Précipitations à 1800 m

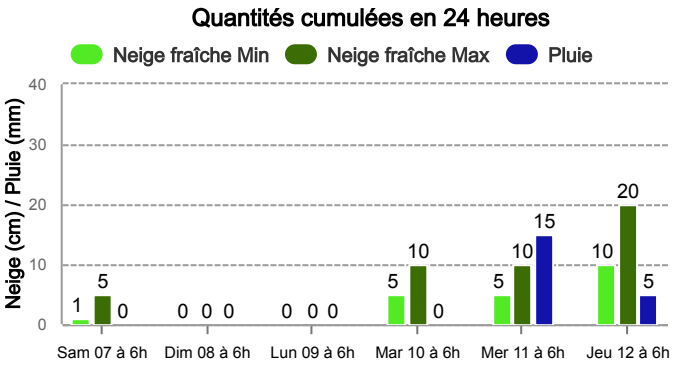

Tendance du jeudi 12 février

Indice de risque fort

Jeudi, chutes de neige abondantes s'abaissant vers 1200m sous un vent d'Ouest soutenu. Risque fort sur l'ensemble du massif.

Pour consulter la vigilance en cours, veuillez vous rendre sur le site https://vigilance.meteofrance.fr/fr

Météo-France - 73 avenue de Paris, 94165 Saint-Mandé cedex - Contact : contact@meteo.fr

Rédigé par Météo-France avec la contribution des observateurs du réseau nivo-météorologiques. Partenariat : ANMSM (Maires de Stations de Montagne), DSF (Domaines Skiables de France), ADSP (Directeurs de Pistes et de la Sécurité des Stations de Sports d'Hiver) et autres acteurs de la montagne.

Bulletin neige & avalanches par téléphone au **0 892 68 10 20** Service 0,35 € / min + prix appel

RÉPUBLIQUE FRANÇAISE
Liberté Égalité Fraternité

METEO FRANCE
À VOS CÔTÉS, DANS UN CLIMAT QUI CHANGE

Bulletin d'estimation du risque d'avalanche
(valable en dehors des pistes balisées et ouvertes)

MASSIF : Vercors

Rédigé le mardi 10 février 2026 à 16h

Conditions nivo-météo des 7 derniers jours

	mer. 04/02				jeu. 05/02				ven. 06/02				sam. 07/02				dim. 08/02				lun. 09/02				mar. 10/02			
	03h	09h	15h	21h	03h	09h	15h	21h	03h	09h	15h	21h	03h	09h	15h	21h	03h	09h	15h	21h	03h	09h	15h	21h	03h	09h	15h	21h
Météo																												
Vent (km/h)	45	50	50	30	25	35	50	45	55	25	25	15	15	15	15	10	25	20	25	20	10	25	25	35	50	40	50	70
à 2000m	↑	↑	↑	↑	↑	↑	↑	↑	↑	↘	↘	↘	↗	↓	↙	↙	↑	↑	↑	↖	↙	↑	↗	↑	↗	→	↗	→
Vent (km/h)	40	45	40	25	25	20	45	30	20	20	20	10	10	10	15	10	15	20	20	15	10	15	25	25	40	30	35	50
à 1500m	↑	↑	↑	↑	↑	↑	↑	↑	↗	→	→	↓	↙	↖	↓	↙	↖	↑	↑	↖	↙	↑	↑	↑	↑	↑	↑	↑

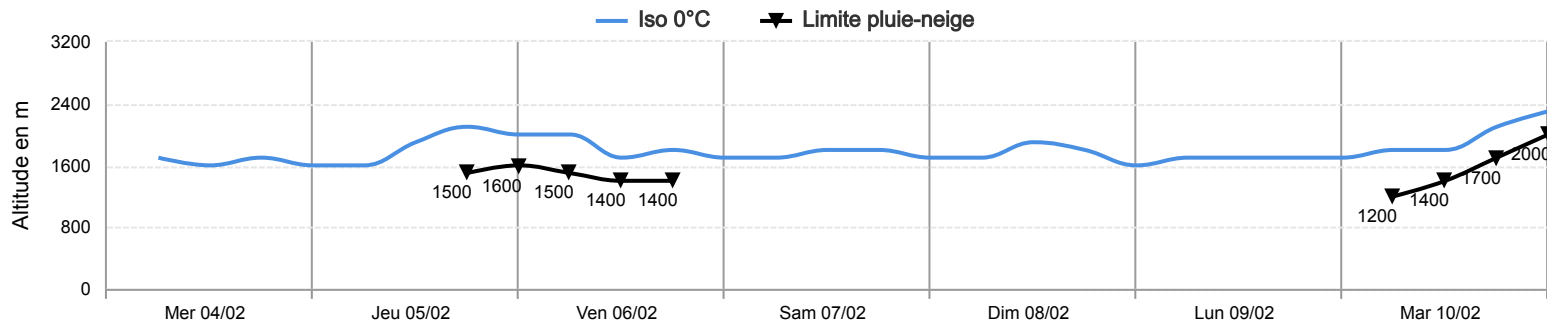

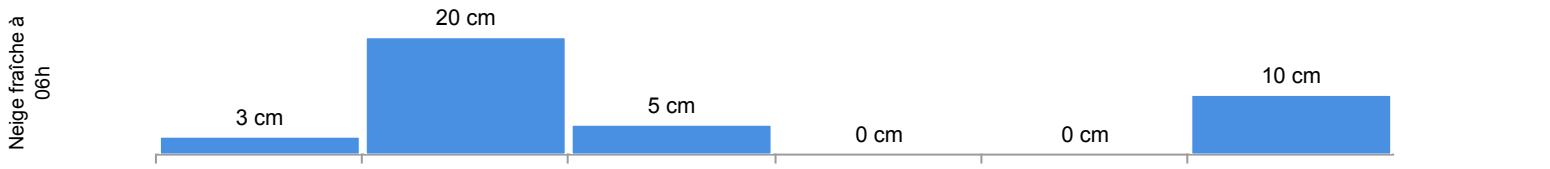

Risque d'avalanche	mer. 04/02	jeu. 05/02	ven. 06/02	sam. 07/02	dim. 08/02	lun. 09/02	mar. 10/02
	3	3	3	3	2	2	3

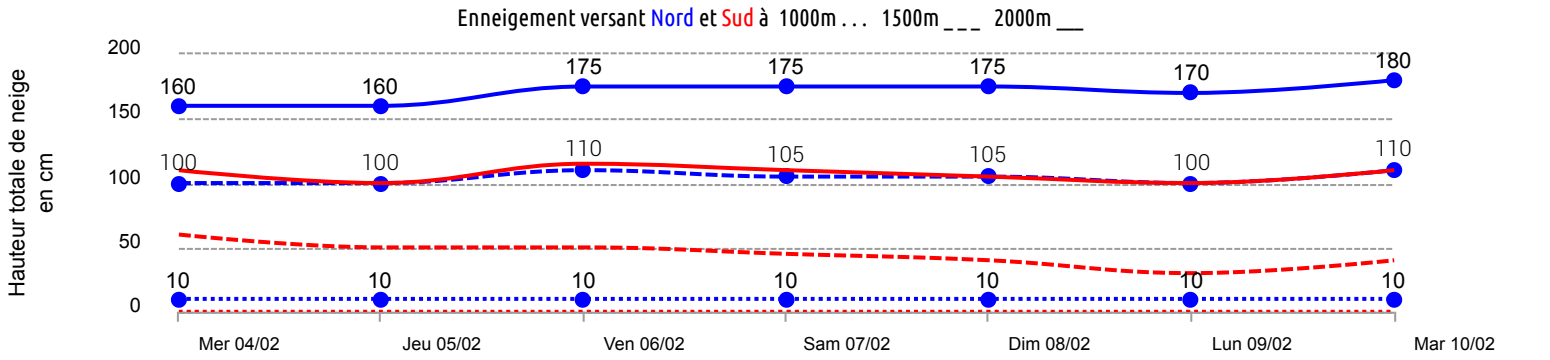

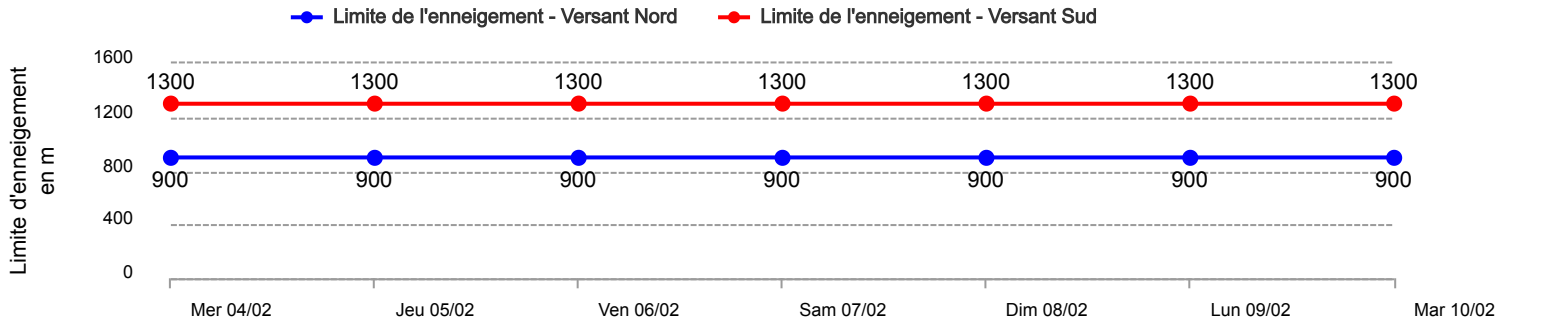

Pour consulter la vigilance en cours, veuillez vous rendre sur le site https://vigilance.meteofrance.fr/fr

Météo-France - 73 avenue de Paris, 94165 Saint-Mandé cedex - Contact : contact@meteo.fr

Rédigé par Météo-France avec la contribution des observateurs du réseau nivo-météorologiques. Partenariat : ANMSM (Maires de Stations de Montagne), DSF (Domaines Skiables de France), ADSP (Directeurs de Pistes et de la Sécurité des Stations de Sports d'Hiver) et autres acteurs de la montagne.

Bulletin neige & avalanches par téléphone au
0 892 68 10 20 Service 0,35 € / min + prix appel