Bulletin d'estimation du risque d'avalanche

(valable en dehors des pistes balisées et ouvertes)

MASSIF : Cinto Rotondo

Rédigé le mardi 10 février 2026 à 17h

Estimation des risques pour le : MERCREDI 11 FÉVRIER

DÉSTABILISATION DU MANTEAU NEIGEUX PAR LA PLUIE VERS 2000/2300M, POURSUITE DES CHUTES DE NEIGE PLUS EN ALTITUDE ET FORMATION DE NOUVELLES PLAQUES PAR LE VENT

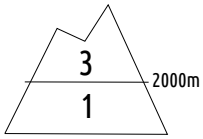

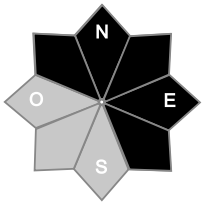

Au-dessus de 2000m indice de risque marqué, plus bas indice faible.

Départs spontanés : Coulées ou avalanches de taille moyenne, en neige humide sous 2200/2300m, en neige fraîche en altitude

Déclenchements provoqués : Formation de nouvelles plaques par le vent en altitude, s'ajoutant aux anciennes instabilités

Indices de risque : 5 très fort - 4 fort - 3 marqué - 2 limité - 1 faible -- En noir : les pentes les plus dangereuses

Stabilité du manteau neigeux

Situation avalancheuse typique : neige ventée couche fragile persistante

Déclenchements provoqués : Des couches fragiles subsistent dans le manteau neigeux mais celui-ci est généralement bien tassé, surtout en dessous de 2000 m. C'est dans les pentes ombragées, en altitude, que certaines plaques peuvent encore être déclenchées au passage d'un seul randonneur. Ce mercredi, les nouvelles chutes de neige transportées par le vent fort génèrent de nouvelles plaques, souvent loin des crêtes, surtout dans les orientations Est. Les anciennes couches étant plus difficiles à solliciter, les volumes mobilisables correspondent plutôt à des avalanches de taille moyenne (taille 2) mais une grande avalanche (taille 3) ne peut être exclue.

Départs spontanés : Cette nuit de mardi à mercredi, la pluie remonte temporairement jusque vers 2200 à 2300 m d'altitude. En dessous de 2000 m, quelques coulées de neige humide se produisent dans les pentes raides, cependant le manteau neigeux bien tassé reste assez bien consolidé. Entre 2000 et 2300 m, la pluie entraine des avalanches de neige humide, généralement de taille moyenne (taille 2), localement de grande taille (taille 3) par humidification d'une sous-couche fragile persistante plus enfouie. Au-dessus de 2200 à 2300 m, les chutes de neige lourde et humide entrainent des coulées et avalanches de neige fraîche de taille moyenne. Au cours de la journée, la limite pluie-neige s'abaisse et les coulées de neige fraîche deviennent possibles dès 1700 à 1800 m.

Qualité de la neige

Qualification de l'enneigement : L'enneigement est excellent pour la saison à toutes altitudes. On relève 2m78 sur la Maniccia à 2350 m dans le massif du Rotondo.

Limite d'enneigement skiable : vers 1500 m.

État de la neige : Le manteau neigeux a connu un cycle dégel/regel sous 1800m voire plus haut en versants sud. La neige est souvent dure et portante en dessous de 2000 m environ. Au-dessus de 2000m en secteurs ombragés ou à soleil plus rasant, la neige reste sèche, légère et profonde à l'abri du vent d'ouest et de la neige très changeante (dure, carton, regelée) dans les secteurs ventés. Au-dessus de 1600m on peut trouver une dizaine de cm de neige fraîche. Corniches et accumulations parfois volumineuses en place. Par endroits, on peut même apercevoir l'effet du Sirocco de la semaine dernière avec de la neige colorée.

Aperçu météo pour le mercredi 11 février

	nuit	matin	après-midi	soir

Temps très perturbé avec des précipitations et du vent fort. Redoux pour cette nuit, rafraichissement pour mercredi en journée.

Pluie-Neige	2 000 m	1 600 m	1 500 m	1 500 m
Iso 0 °C	2 300 m	2 000 m	1 900 m	2 000 m
Vent 1500 m	→ 50 km/h	→ 90 km/h	→ 80 km/h	→ 80 km/h
Vent 3000 m	→ 80 km/h	→ 100 km/h	↘ 90 km/h	→ 90 km/h

Épaisseur de neige hors-piste

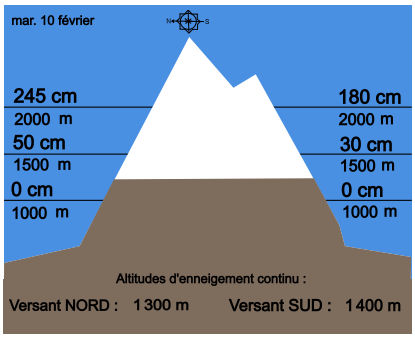

Précipitations à 1800 m

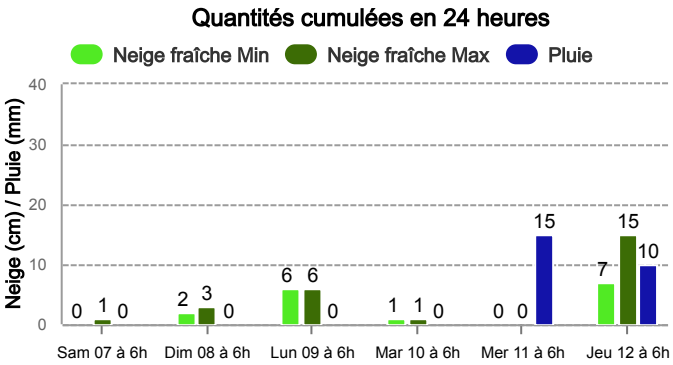

Tendance du jeudi 12 février

Indice de risque marqué

Poursuite d'un temps perturbé avec des chutes de neige et du vent violent. Maintien d'un risque marqué.

Pour consulter la vigilance en cours, veuillez vous rendre sur le site https://vigilance.meteofrance.fr/fr

Météo-France - 73 avenue de Paris, 94165 Saint-Mandé cedex - Contact : contact@meteo.fr

Rédigé par Météo-France avec la contribution des observateurs du réseau nivo-météorologiques. Partenariat : ANMSM (Maires de Stations de Montagne), DSF (Domaines Skiables de France), ADSP (Directeurs de Pistes et de la Sécurité des Stations de Sports d'Hiver) et autres acteurs de la montagne.

Bulletin neige & avalanches par téléphone au **0 892 68 10 20** Service 0,35 € / min + prix appel

Bulletin d'estimation du risque d'avalanche

(valable en dehors des pistes balisées et ouvertes)

MASSIF : Cinto Rotondo

Rédigé le mardi 10 février 2026 à 17h

Conditions nivo-météo des 7 derniers jours

	mer. 04/02				jeu. 05/02				ven. 06/02				sam. 07/02				dim. 08/02				lun. 09/02				mar. 10/02			
	03h	09h	15h	21h	03h	09h	15h	21h	03h	09h	15h	21h	03h	09h	15h	21h	03h	09h	15h	21h	03h	09h	15h	21h	03h	09h	15h	21h
Météo																												
Vent (km/h)	15	60	50	20	35	50	45	65	100	85	80	65	65	45	60	45	65	15	20	20	15	10	15	20	30	25	40	70
à 3000m																												
Vent (km/h)	15	30	25	15	25	35	30	50	80	70	70	55	55	30	45	35	45	10	20	15	10	10	10	10	10	10	20	30
à 1500m																												

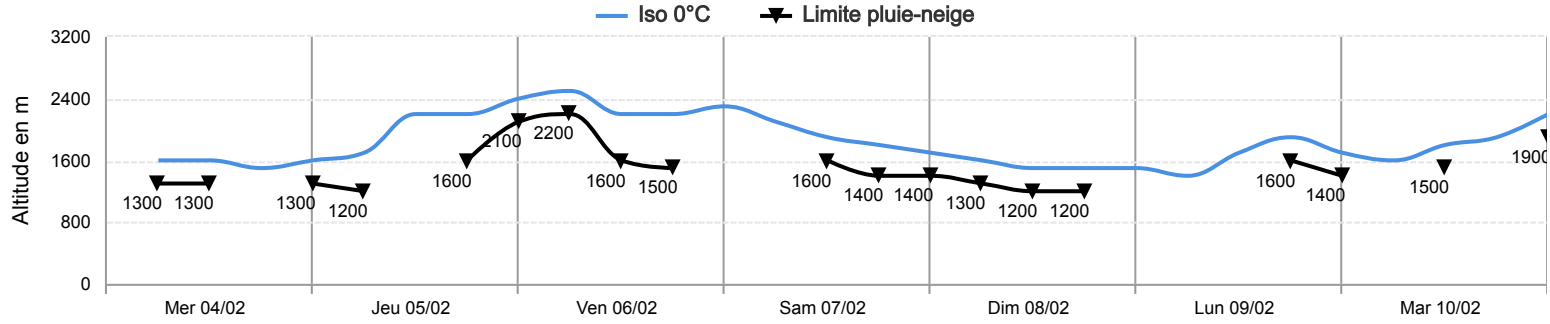

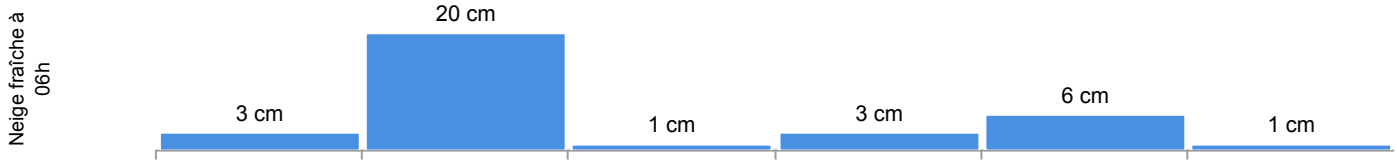

Risque d'avalanche	mer. 04/02	jeu. 05/02	ven. 06/02	sam. 07/02	dim. 08/02	lun. 09/02	mar. 10/02
	3	3	3	3	3	3	2

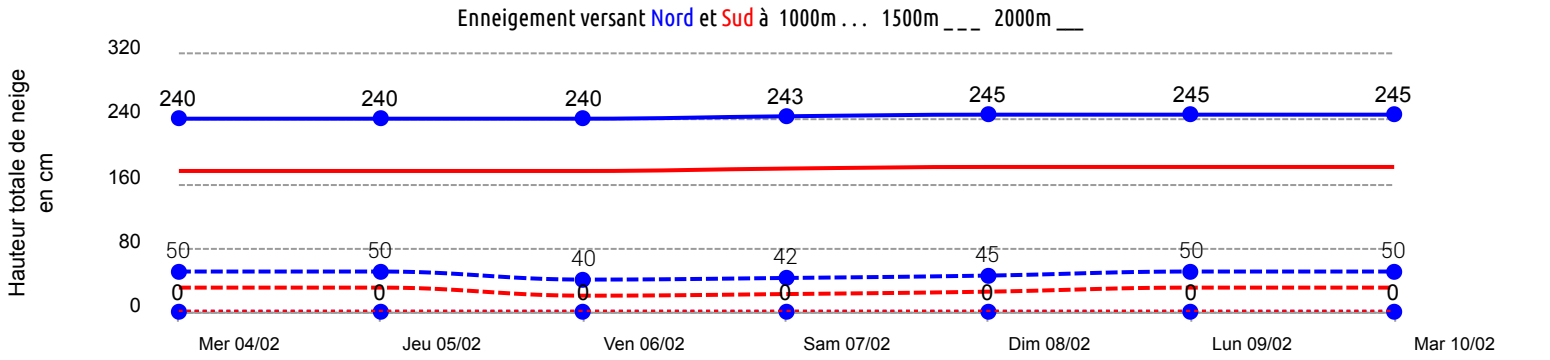

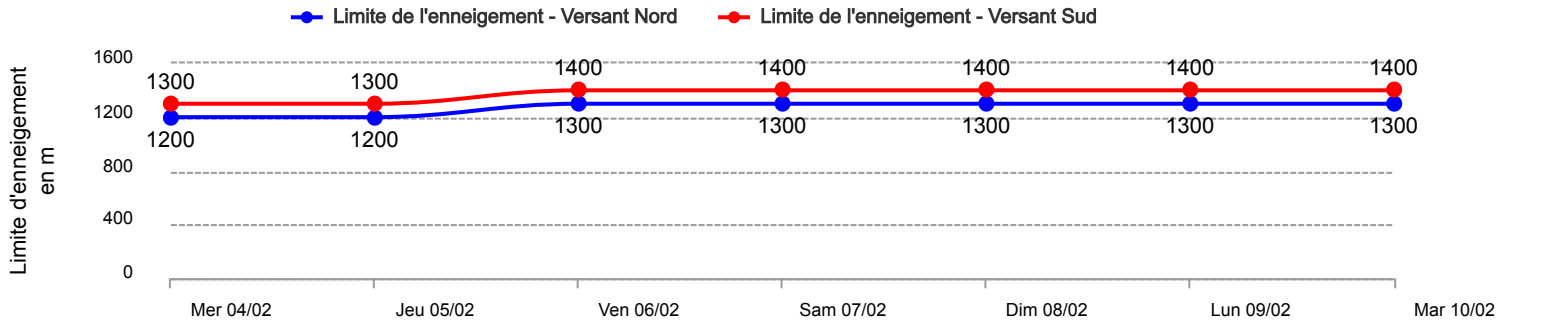

Pour consulter la vigilance en cours, veuillez vous rendre sur le site https://vigilance.meteofrance.fr/fr

Météo-France - 73 avenue de Paris, 94165 Saint-Mandé cedex - Contact : contact@meteo.fr

Rédigé par Météo-France avec la contribution des observateurs du réseau nivo-météorologiques. Partenariat : ANMSM (Maires de Stations de Montagne), DSF (Domaines Skiables de France), ADSP (Directeurs de Pistes et de la Sécurité des Stations de Sports d'Hiver) et autres acteurs de la montagne.

Bulletin neige & avalanches par téléphone au

0 892 68 10 20 Service 0,35 € / min + prix appel