RÉPUBLIQUE FRANÇAISE
Liberté Égalité Fraternité

METEO FRANCE
À VOS CÔTÉS, DANS UN CLIMAT QUI CHANGE

Bulletin d'estimation du risque d'avalanche
(valable en dehors des pistes balisées et ouvertes)

MASSIF : Devoluy

Rédigé le mardi 10 Février 2026 à 17h

Estimation des risques pour le : MERCREDI 11 FÉVRIER

INSTABILITÉ MARQUÉE EN NEIGE SÈCHE EN ALTITUDE, EN NEIGE HUMIDE PLUS BAS.

3

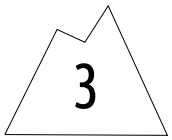

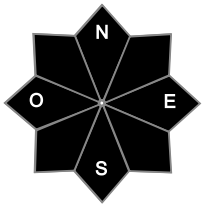

Indice de risque marqué.

Départs spontanés : en altitude, départs ponctuels, plus rarement en plaque. Plus bas, départs ponctuels en neige humide.

Déclenchements provoqués : intabilités, faciles à déclencher. En versants froids d'altitude, avalanches de plaque parfois grandes, mais difficiles à déclencher.

Indices de risque : 5 très fort - 4 fort - 3 marqué - 2 limité - 1 faible -- En noir : les pentes les plus dangereuses

Stabilité du manteau neigeux

Situation avalancheuse typique : neige fraîche neige humide

Déclenchements provoqués : nouvelles instabilités en formation, plus épaisses au fil des chutes, sous l'action du vent et au-dessus de 1800/2000m. Possiblement présentes en toute orientation. Plaques pouvant être d'aspect poudreux, faciles à déclencher, parfois à distance. Avalanches de taille petite à moyenne. Grande non exclue en zone de forte d'accumulation (souvent large est) ou dans les ubacs (pentes ouest, nord, est) en cas de sollicitation de l'importante couche fragile enfouie au fond du manteau neigeux, mais le déclenchement semble difficile. Mais un premier départ peut faciliter en cascade le déclenchement de ces plaques très volumineuses.

Départs spontanés : avalanches de neige fraîche en pente raide d'altitude devenant plus nombreuses au fil des chutes de neige souvent ventées. Taille petite à moyenne, voire grande dans une pente fortement chargée par le vent. Départ parfois en plaque en versants froids de taille moyenne, voire grande. Mercredi après-midi, avec l'arrêt des chutes, l'activité naturelle est en baisse, mais encore possible avec la surcharge liée au transport de neige par le vent.
Sous 1800 m environ, départs ponctuels en toute orientation en neige humide. Taille petite, voire moyenne, avec la pluie ou la neige lourde humide.

Qualité de la neige

L'enneigement est excédentaire pour un début février.
Données observées : environ 110 cm vers 2000 m d'altitude.

Limite d'enneigement skiable : vers 1200/1300 m sur la plupart des itinéraires.

État de la neige de surface : neige fraiche en quantité plus ou moins travaillées par le vent, mais possiblement lourde/ humide sous 1800/2000 m.

Aperçu météo pour le mercredi 11 février

	nuit	matin	après-midi	soir
Poursuite des chutes de neige en matinée. Cumuls : 15 à 30 cm. Accalmie en seconde partie de journée. Vent restant sensible.				
Pluie-Neige	1 600 m	1 500 m	1 600 m	1 500 m
Iso 0 °C	2 000 m	1 800 m	2 000 m	2 000 m
Vent 2000 m	→ 30 km/h	→ 30 km/h	→ 30 km/h	↑ 25 km/h
Vent 3000 m	↘ 65 km/h	↘ 75 km/h	↘ 60 km/h	→ 45 km/h

Épaisseur de neige hors-piste

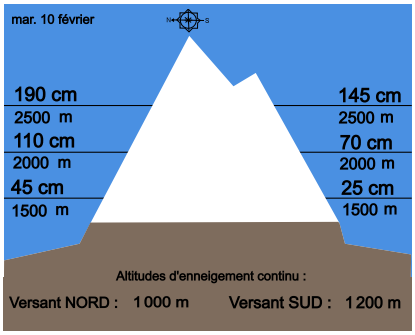

Précipitations à 1800 m

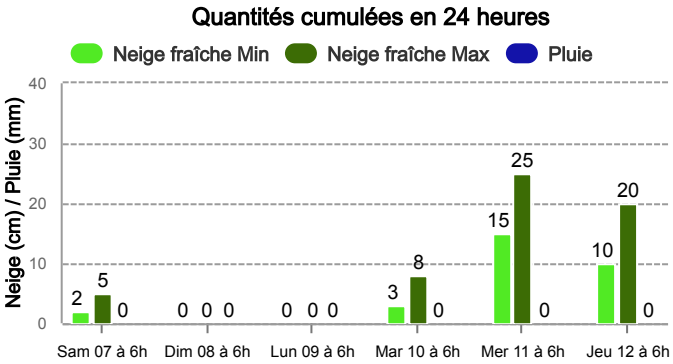

Tendance du jeudi 12 février

Indice de risque fort

Risque en hausse, avec les nouvelles chutes et le vent. Instabilités faciles à déclencher.

Pour consulter la vigilance en cours, veuillez vous rendre sur le site https://vigilance.meteofrance.fr/fr

Météo-France - 73 avenue de Paris, 94165 Saint-Mandé cedex - Contact : contact@meteo.fr

Rédigé par Météo-France avec la contribution des observateurs du réseau nivo-météorologiques. Partenariat : ANMSM (Maires de Stations de Montagne), DSF (Domaines Skiables de France), ADSP (Directeurs de Pistes et de la Sécurité des Stations de Sports d'Hiver) et autres acteurs de la montagne.

Bulletin neige & avalanches par téléphone au
0 892 68 10 20 Service 0,35 € / min + prix appel

Bulletin d'estimation du risque d'avalanche

(valable en dehors des pistes balisées et ouvertes)

MASSIF : Devoluy

Rédigé le mardi 10 février 2026 à 17h

Conditions nivo-météo des 7 derniers jours

	mer. 04/02				jeu. 05/02				ven. 06/02				sam. 07/02				dim. 08/02				lun. 09/02				mar. 10/02			
	03h	09h	15h	21h	03h	09h	15h	21h	03h	09h	15h	21h	03h	09h	15h	21h	03h	09h	15h	21h	03h	09h	15h	21h	03h	09h	15h	21h
Météo																												
Vent (km/h)	40	40	30	15	30	15	60	40	40	45	35	20	15	10	10	5	10	25	25	10	5	15	15	20	30	40	40	55
à 3000m																												
Vent (km/h)	35	30	20	5	10	20	60	10	25	25	25	15	10	10	15	10	10	20	20	10	5	15	15	15	20	15	20	25
à 2000m																												

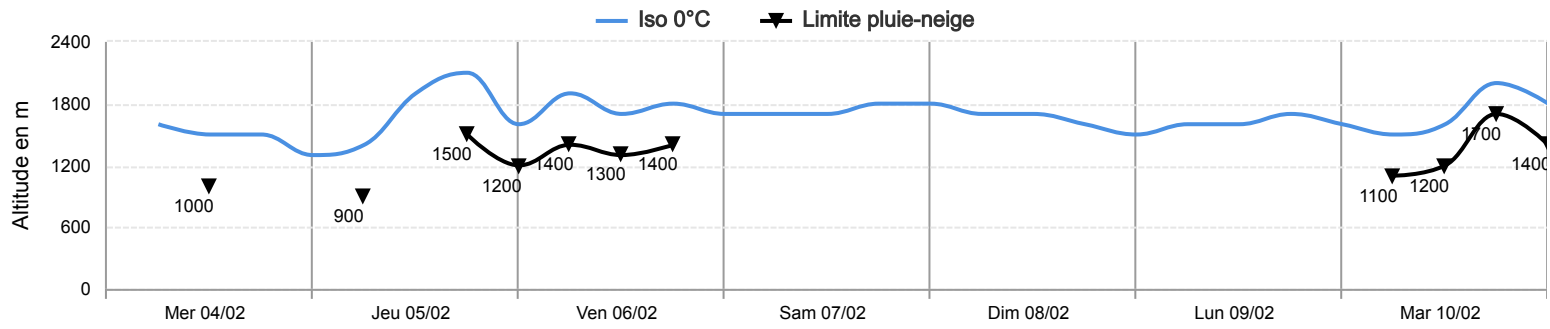

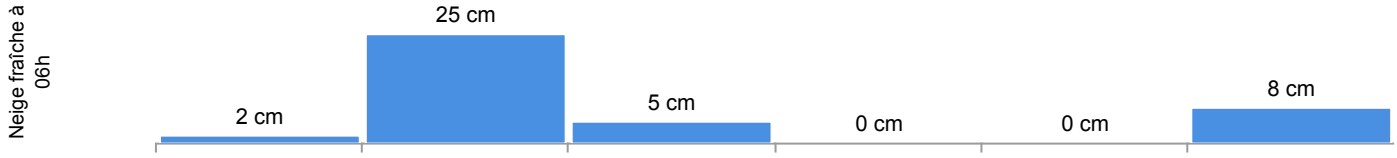

Risque d'avalanche	mer. 04/02	jeu. 05/02	ven. 06/02	sam. 07/02	dim. 08/02	lun. 09/02	mar. 10/02
	3	3	4	3	3	2	2

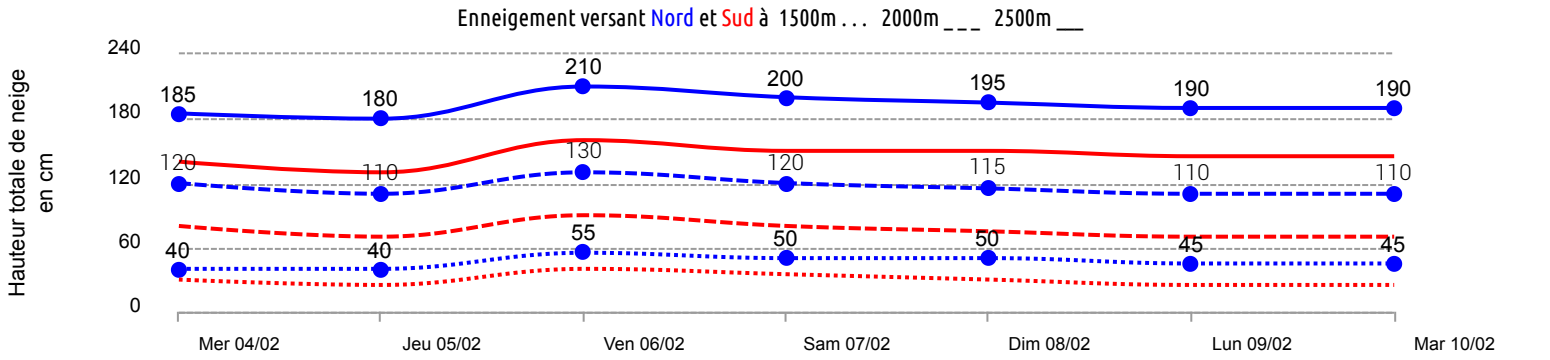

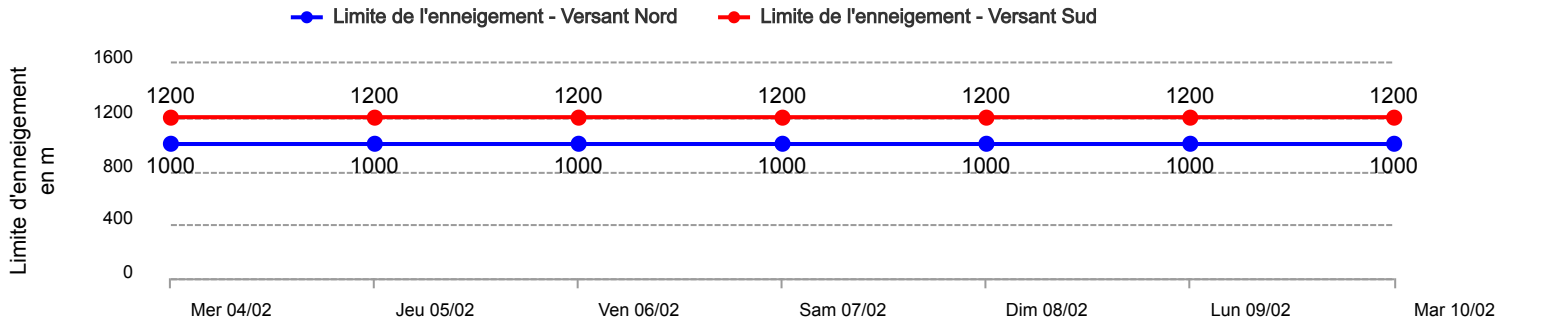

Pour consulter la vigilance en cours, veuillez vous rendre sur le site https://vigilance.meteofrance.fr/fr

Météo-France - 73 avenue de Paris, 94165 Saint-Mandé cedex - Contact : contact@meteo.fr

Bulletin neige & avalanches par téléphone au

0 892 68 10 20 Service 0,35 € / min + prix appel

Rédigé par Météo-France avec la contribution des observateurs du réseau nivo-météorologiques. Partenariat : ANMSM (Maires de Stations de Montagne), DSF (Domaines Skiables de France), ADSP (Directeurs de Pistes et de la Sécurité des Stations de Sports d'Hiver) et autres acteurs de la montagne.