RÉPUBLIQUE FRANÇAISE
Liberté Égalité Fraternité

METEO FRANCE
À VOS CÔTÉS, DANS UN CLIMAT QUI CHANGE

Bulletin d'estimation du risque d'avalanche
(valable en dehors des pistes balisées et ouvertes)
MASSIF : Embrunais Parpaillon

Rédigé le mardi 10 février 2026 à 17h

Estimation des risques pour le : MERCREDI 11 FÉVRIER

FORTE INSTABILITÉ. LOCALEMENT GROS VOLUMES DE NEIGE MOBILISABLES

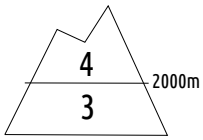

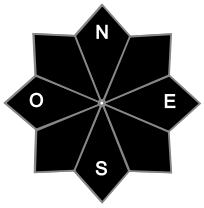

Au-dessus de 2000m indice de risque fort, plus bas indice marqué.

Départs spontanés : nombreux départs ponctuels ou avalanches de plaque, parfois grands.

Déclenchements provoqués : nombreuses avalanches de plaque, faciles à déclencher, parfois à distance.

Indices de risque : 5 très fort - 4 fort - 3 marqué - 2 limité - 1 faible -- En noir : les pentes les plus dangereuses

Stabilité du manteau neigeux

Situation avalancheuse typique : neige fraîche couche fragile persistante

Déclenchements provoqués : nouvelles instabilités en formation, plus nombreuses et épaisses au fil des chutes, sous l'action du vent et au-dessus de 1800/2000m. Possiblement présentes en toute orientation. Plaques pouvant être d'aspect poudreux, faciles à déclencher, parfois à distance. Avalanches de taille petite à moyenne, voire grande en zone d'accumulation (souvent large est).
Dans les ubacs (pentes ouest, nord, est), en cas de sollicitation de l'importante couche fragile enfouie au fond du manteau neigeux, les cassures peuvent être encore plus épaisses et larges, notamment au-delà de 2300/2400 m. Avalanche de grande taille, très grande non exclue. Déclenchement plus ou moins difficile. Un premier départ peut aussi faciliter aussi en cascade le déclenchement de ces plaques très volumineuses.

Départs spontanés : avalanches de neige fraîche en pente raide d'altitude devenant plus nombreuses au fil des chutes de neige souvent ventées. Taille petite à moyenne, grande non exclue dans une pente fortement chargée par le vent. Départ parfois en plaque en versants froids de taille moyenne à grande. Mercredi après-midi, avec l'arrêt des chutes, l'activité naturelle est en baisse, mais encore possible avec la surcharge liée au transport de neige par le vent.

Qualité de la neige

L'enneigement est légèrement excédentaire pour un début février.
Données observées : 77 cm à la Nivôse du Parpaillon à 2550 m, secteur soufflé par le vent.

Limite d'enneigement skiable : dès 1200/1400 m sur la plupart des itinéraires, peu de sous-couche en adrets à cette altitude.

État de la neige de surface : neige fraiche en quantité plus ou moins travaillées par le vent, mais possiblement lourde/ humide sous 1800/2000 m.

Aperçu météo pour le mercredi 11 février

	nuit	matin	après-midi	soir

Poursuite des chutes de neige en matinée. Cumuls : 15 à 30 cm. Accalmie en seconde partie de journée. Vent restant sensible.

	nuit	matin	après-midi	soir
Pluie-Neige	1 600 m	1 400 m	1 600 m	1 500 m
Iso 0 °C	1 900 m	1 700 m	2 000 m	2 000 m
Vent 2000 m	↗ 20 km/h	↘ 25 km/h	↗ 30 km/h	↗ 25 km/h
Vent 3000 m	↘ 70 km/h	↘ 65 km/h	↘ 55 km/h	→ 40 km/h

Épaisseur de neige hors-piste

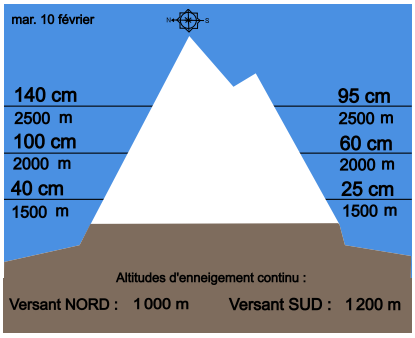

Précipitations à 1800 m

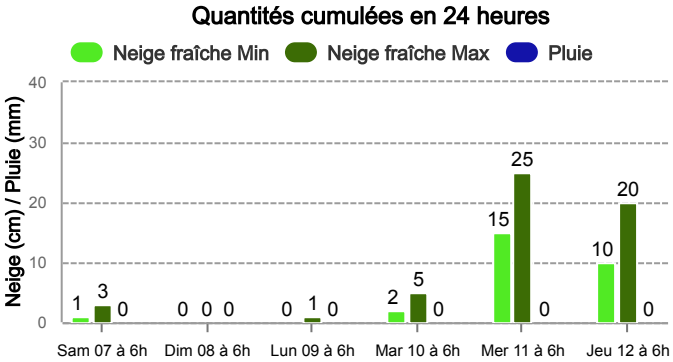

Tendance du jeudi 12 février

Indice de risque fort

Risque fort, avec les nouvelles chutes et le vent. Instabilités faciles à déclencher.

Pour consulter la vigilance en cours, veuillez vous rendre sur le site https://vigilance.meteofrance.fr/fr

Météo-France - 73 avenue de Paris, 94165 Saint-Mandé cedex - Contact : contact@meteo.fr

Rédigé par Météo-France avec la contribution des observateurs du réseau nivo-météorologiques. Partenariat : ANMSM (Maires de Stations de Montagne), DSF (Domaines Skiables de France), ADSP (Directeurs de Pistes et de la Sécurité des Stations de Sports d'Hiver) et autres acteurs de la montagne.

Bulletin neige & avalanches par téléphone au
0 892 68 10 20 Service 0,35 € / min + prix appel

RÉPUBLIQUE FRANÇAISE
Liberté Égalité Fraternité

METEO FRANCE
À VOS CÔTÉS, DANS UN CLIMAT QUI CHANGE

Bulletin d'estimation du risque d'avalanche

(valable en dehors des pistes balisées et ouvertes)

MASSIF : Embrunais Parpaillon

Rédigé le mardi 10 février 2026 à 17h

Conditions nivo-météo des 7 derniers jours

	mer. 04/02				jeu. 05/02				ven. 06/02				sam. 07/02				dim. 08/02				lun. 09/02				mar. 10/02			
	03h	09h	15h	21h	03h	09h	15h	21h	03h	09h	15h	21h	03h	09h	15h	21h	03h	09h	15h	21h	03h	09h	15h	21h	03h	09h	15h	21h
Météo																												
Vent (km/h)	40	40	20	15	25	20	45	15	40	35	35	20	20	10	5	5	15	15	30	30	10	15	20	20	30	45	50	60
à 3000m																												
Vent (km/h)	15	20	15	10	10	10	20	15	15	15	20	10	10	5	10	10	10	10	20	20	10	5	15	10	10	15	15	15
à 2000m																												

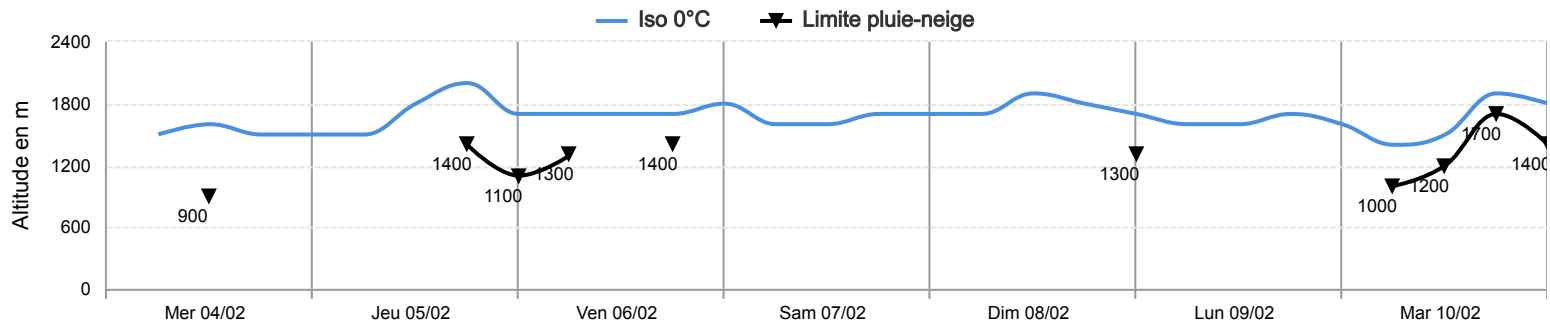

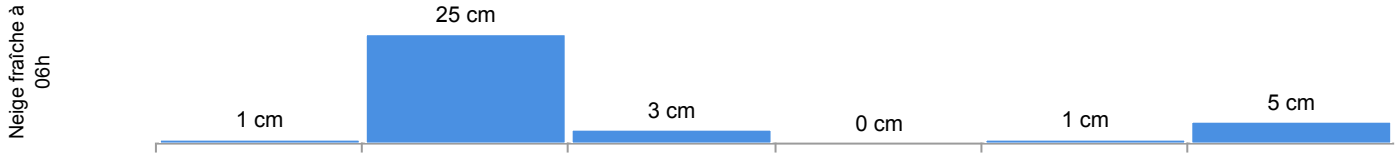

Risque d'avalanche	mer. 04/02	jeu. 05/02	ven. 06/02	sam. 07/02	dim. 08/02	lun. 09/02	mar. 10/02
	4	3	4	4	3	3	3

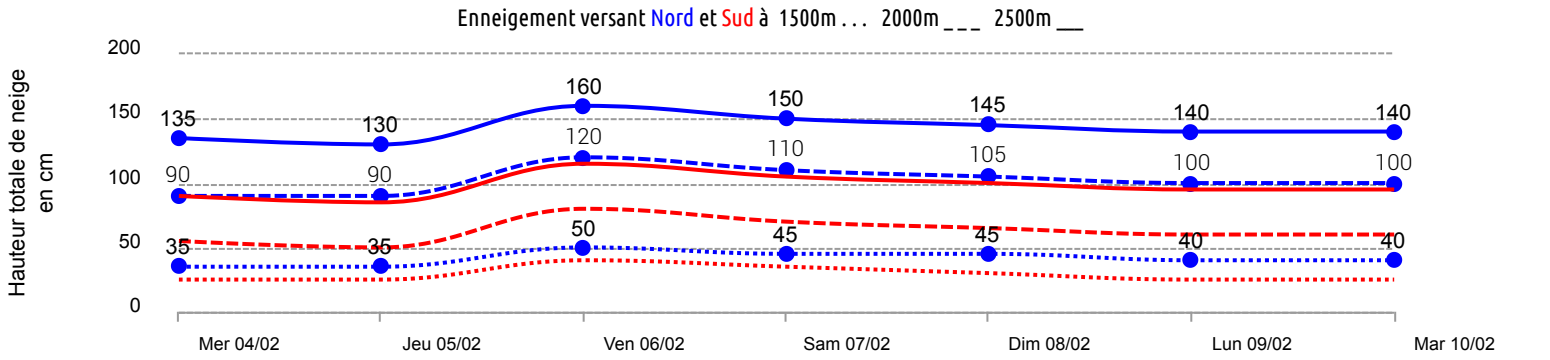

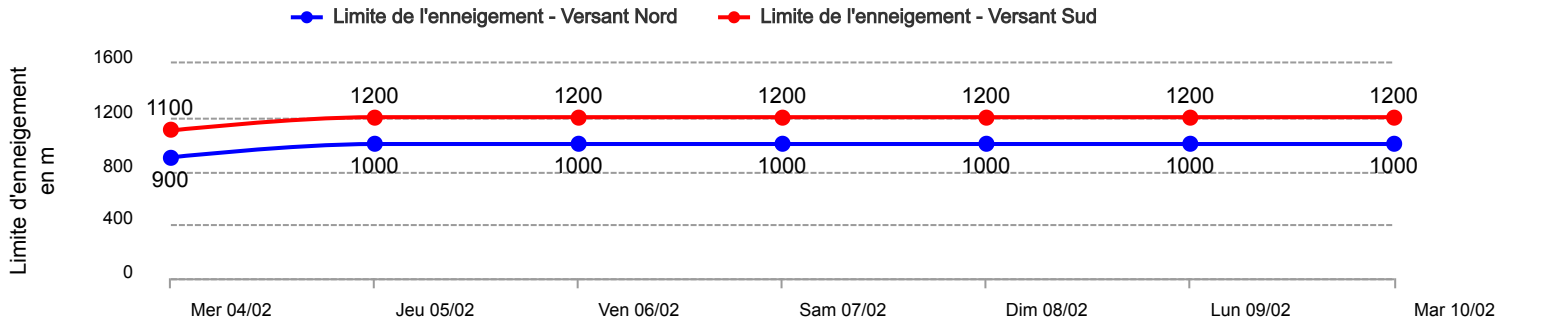

Pour consulter la vigilance en cours, veuillez vous rendre sur le site https://vigilance.meteofrance.fr/fr

Météo-France - 73 avenue de Paris, 94165 Saint-Mandé cedex - Contact : contact@meteo.fr

Rédigé par Météo-France avec la contribution des observateurs du réseau nivo-météorologiques. Partenariat : ANMSM (Maires de Stations de Montagne), DSF (Domaines Skiables de France), ADSP (Directeurs de Pistes et de la Sécurité des Stations de Sports d'Hiver) et autres acteurs de la montagne.

Bulletin neige & avalanches par téléphone au

0 892 68 10 20 Service 0,35 € / min + prix appel