Bulletin d'estimation du risque d'avalanche
(valable en dehors des pistes balisées et ouvertes)

MASSIF : Queyras

Rédigé le mardi 10 Février 2026 à 17h

Estimation des risques pour le : MERCREDI 11 FÉVRIER

FORTE PROBABILITÉ DE DÉCLENCHEMENTS DE PLAQUES VOLUMINEUSES

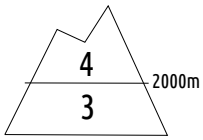

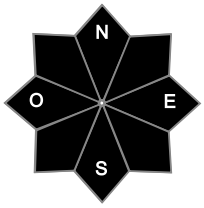

Au-dessus de 2000m indice de risque fort, plus bas indice marqué.

Départs spontanés : quelques départs ponctuels, plus rarement en plaque.

Déclenchements provoqués : avalanches de plaque, faciles à déclencher. En versants froids d'altitude, parfois grandes, déclenchables aussi à distance.

Indices de risque : 5 très fort - 4 fort - 3 marqué - 2 limité - 1 faible -- En noir : les pentes les plus dangereuses

Stabilité du manteau neigeux

Situation avalancheuse typique : couche fragile persistante neige fraîche

Déclenchements provoqués : instabilités en place en versants est / nord / ouest au-dessus de 2000 m environ. Difficiles à identifier. Déclenchement encore possible au passage d'un seul skieur, souvent à distance. Avalanches de plaque de taille moyenne à grande (taille 2 à 3), avec des cassures larges et épaisses, notamment au-delà de 2300/2400 m. En effet, présence d'une importante couche fragile enfouie à la base du manteau neigeux encore réactive.
Par ailleurs, plaques en place ou en formation avec les chutes de neige et le vent. Possiblement présentes en toute orientation. Faciles à déclencher, générant des avalanches de petite taille à moyenne. Mais elles peuvent déclencher en cascade les plaques plus volumineuses décrites précédemment.

Départs spontanés : quelques avalanches de neige fraîche en pente raide d'altitude au fil des chutes de neige souvent ventées. Taille généralement petite, voire moyenne dans une pente fortement chargée par le vent. Evenuels départ en plaque en versants froids de taille moyenne à grande. Mercredi après-midi, avec l'arrêt des chutes, l'activité naturelle est en baisse, mais encore possible avec la surcharge liée au transport de neige par le vent.

Qualité de la neige

L'enneigement est proche des normales dans les ubacs, voire excédentaire vers le Briançonnais, mais reste déficitaire dans les adrets d'altitude, notamment dans le Haut Guil.
Données observées : 137 cm en versant nord du col Izoard à 2300 m, 60 cm à la Nivôse du Col Agnel à 2630 m, 61 cm à Ristolas à 1670 m.

Limite d'enneigement skiable : dès 1000/1300 m en ubacs, plutôt 1500/1700 m en adrets avec peu de sous-couche jusqu'à haute altitude, notamment dans le Haut Guil.

État de la neige de surface : neige fraiche, souvent lourde sous 1800/2000 m. En versant froid, sur de la neige restée poudreuse et légère, parfois densifiée ou cartonnée par le vent près des crêtes. En versants ensoleillés, sur neige humide / croutée sous 2400/2500 m.

Aperçu météo pour le mercredi 11 février

	nuit	matin	après-midi	soir

Poursuite des chutes de neige en matinée. Cumuls : 15 à 30 cm. Accalmie en seconde partie de journée. Vent restant sensible.

Pluie-Neige	1 600 m	1 500 m	1 600 m	1 500 m
Iso 0 °C	1 800 m	1 900 m	2 000 m	2 000 m
Vent 2000 m	→ 25 km/h	→ 25 km/h	→ 30 km/h	→ 30 km/h
Vent 3000 m	→ 50 km/h	→ 45 km/h	→ 45 km/h	→ 55 km/h

Épaisseur de neige hors-piste

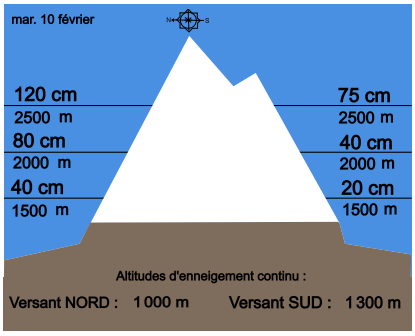

Précipitations à 1800 m

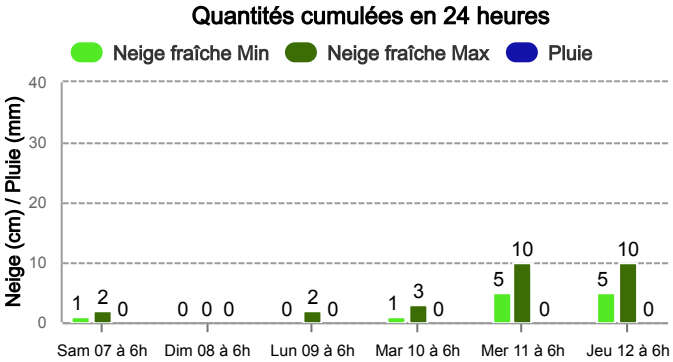

Tendance du jeudi 12 février

Indice de risque fort

Risque fort, avec les nouvelles chutes et le vent. Instabilités faciles à déclencher.

Pour consulter la vigilance en cours, veuillez vous rendre sur le site https://vigilance.meteofrance.fr/fr

Météo-France - 73 avenue de Paris, 94165 Saint-Mandé cedex - Contact : contact@meteo.fr

Rédigé par Météo-France avec la contribution des observateurs du réseau nivo-météorologiques. Partenariat : ANMSM (Maires de Stations de Montagne), DSF (Domaines Skiables de France), ADSP (Directeurs de Pistes et de la Sécurité des Stations de Sports d'Hiver) et autres acteurs de la montagne.

Bulletin neige & avalanches par téléphone au
0 892 68 10 20 Service 0,35 € / min + prix appel

RÉPUBLIQUE FRANÇAISE
Liberté Égalité Fraternité

METEO FRANCE
À VOS CÔTÉS, DANS UN CLIMAT QUI CHANGE

Bulletin d'estimation du risque d'avalanche

(valable en dehors des pistes balisées et ouvertes)

MASSIF : Queyras

Rédigé le mardi 10 février 2026 à 17h

Conditions nivo-météo des 7 derniers jours

	mer. 04/02				jeu. 05/02				ven. 06/02				sam. 07/02				dim. 08/02				lun. 09/02				mar. 10/02			
	03h	09h	15h	21h	03h	09h	15h	21h	03h	09h	15h	21h	03h	09h	15h	21h	03h	09h	15h	21h	03h	09h	15h	21h	03h	09h	15h	21h
Météo																												
Vent (km/h)	30	30	25	30	20	25	40	25	35	35	40	25	25	15	15	10	10	20	35	35	15	10	15	20	30	35	40	50
à 3000m																												
Vent (km/h)	15	20	15	10	10	10	10	15	5	15	25	10	10	10	15	5	5	15	30	30	10	10	15	10	10	20	25	25
à 2000m																												

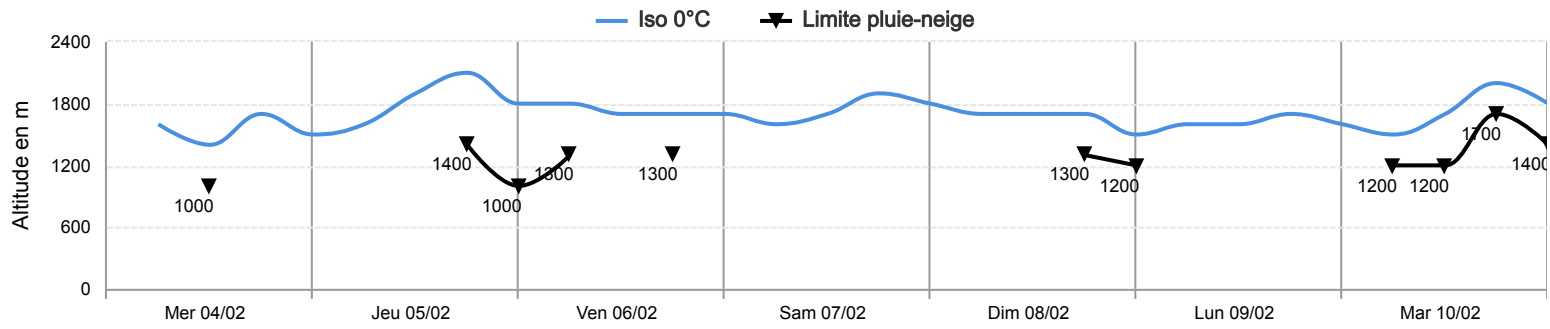

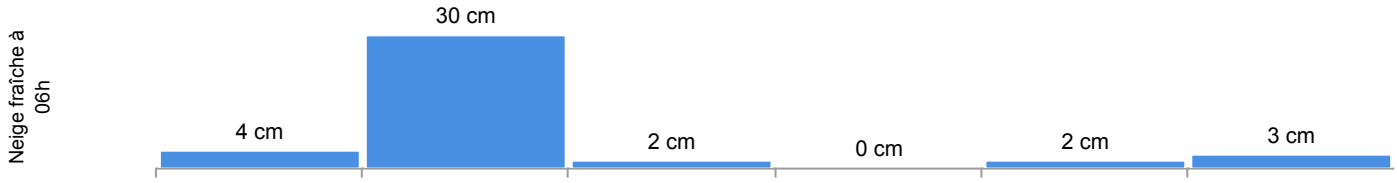

Risque d'avalanche	mer. 04/02	jeu. 05/02	ven. 06/02	sam. 07/02	dim. 08/02	lun. 09/02	mar. 10/02
	4	3	4	4	3	3	3

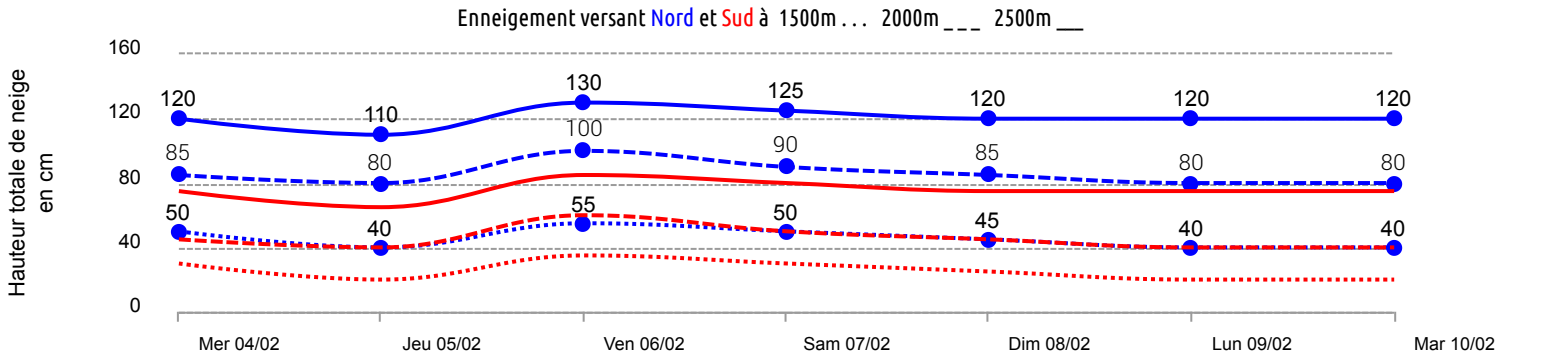

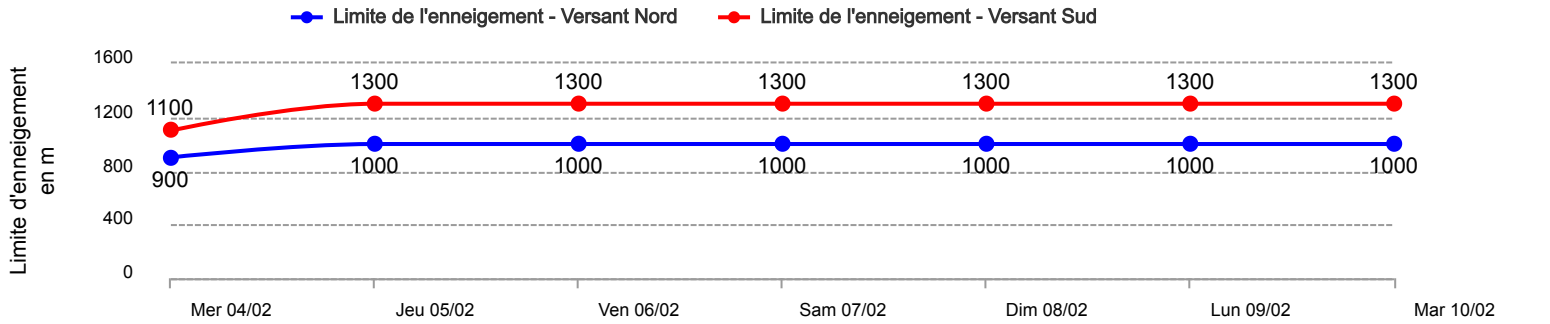

Pour consulter la vigilance en cours, veuillez vous rendre sur le site https://vigilance.meteofrance.fr/fr

Météo-France - 73 avenue de Paris, 94165 Saint-Mandé cedex - Contact : contact@meteo.fr

Rédigé par Météo-France avec la contribution des observateurs du réseau nivo-météorologiques. Partenariat : ANMSM (Maires de Stations de Montagne), DSF (Domaines Skiables de France), ADSP (Directeurs de Pistes et de la Sécurité des Stations de Sports d'Hiver) et autres acteurs de la montagne.

Bulletin neige & avalanches par téléphone au
0 892 68 10 20 Service 0,35 € / min + prix appel